Dimanche 01.03.2026

Publié 28 02 2026, 17:00

Matin

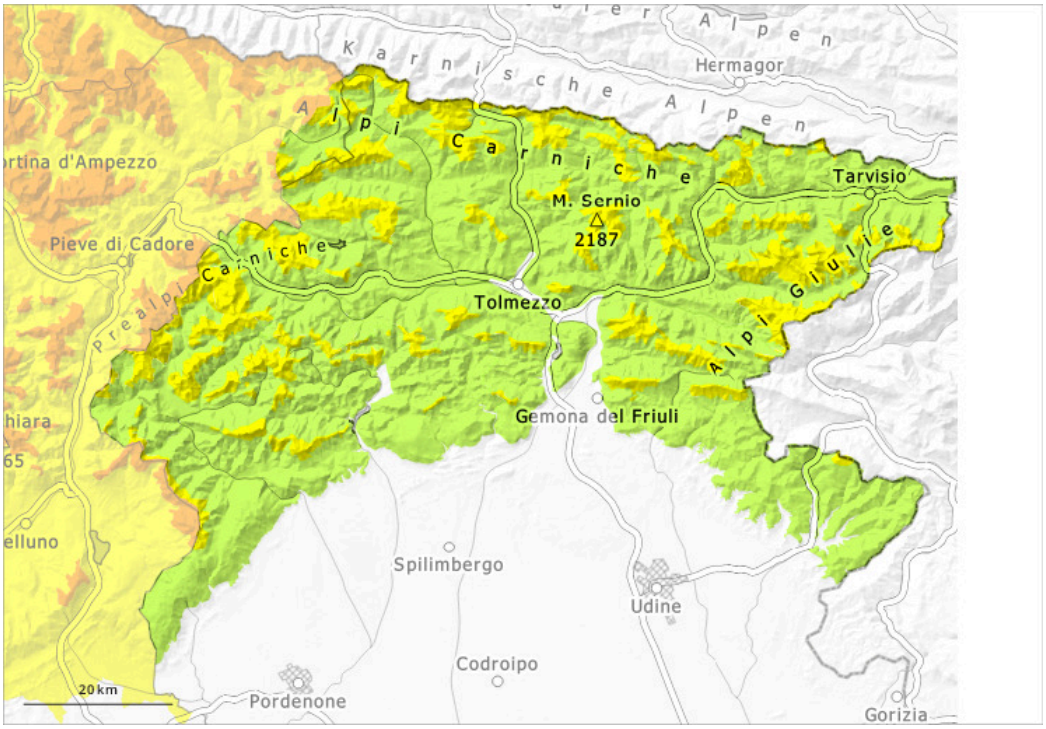

Après-midi

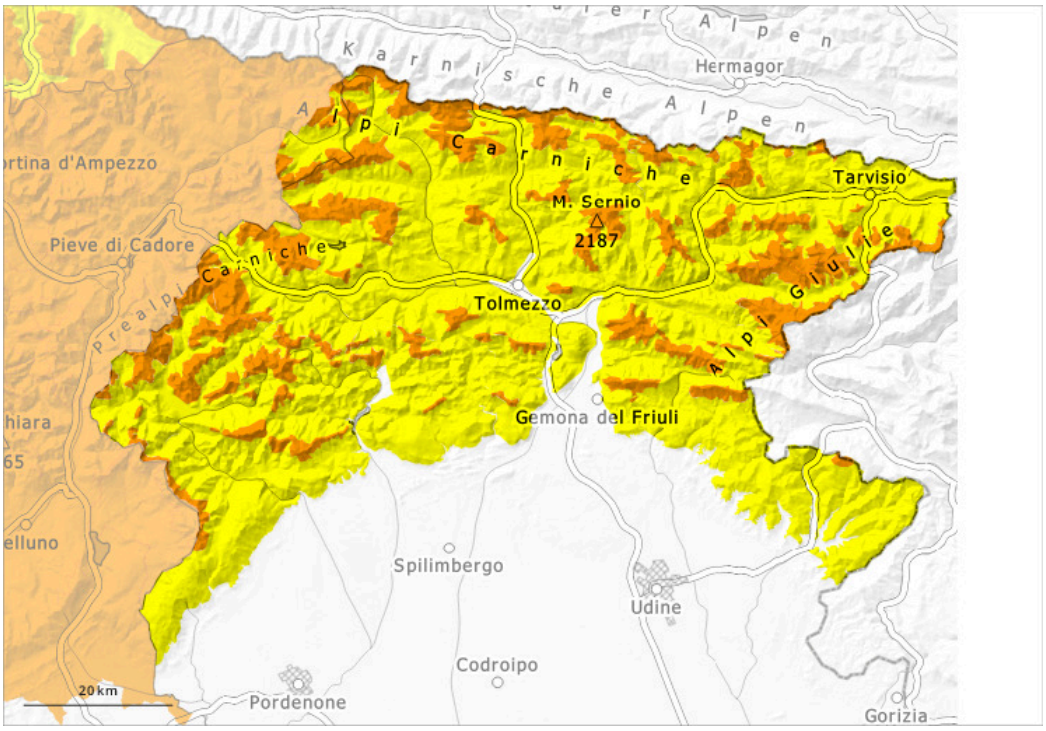

1	2	3	4	5
faible	limité	marqué	fort	très fort

Dimanche 01.03.2026

Publié 28 02 2026, 17:00

Degré de danger 3 - Marqué

AM:

Limite de la forêt

Tendance: danger d'avalanche constant
leLundi 02 03 2026

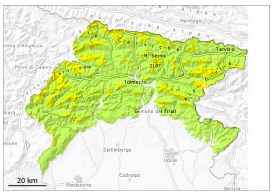

Avalanches mouillées (Neige humide)

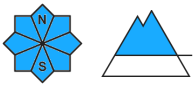

Limite de la forêt

Neige ancienne (Sous-couche fragile persistante)

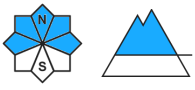

Limite de la forêt

PM:

Limite de la forêt

Tendance: danger d'avalanche constant
leLundi 02 03 2026

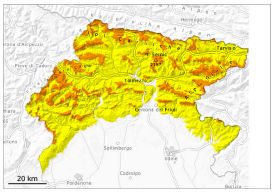

Avalanches mouillées (Neige humide)

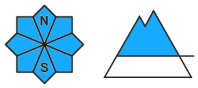

Limite de la forêt

Neige ancienne (Sous-couche fragile persistante)

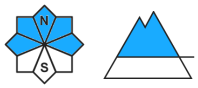

Limite de la forêt

Avalanches mouillées (Neige humide)

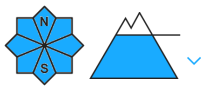

Limite de la forêt

Avec le réchauffement diurne et le rayonnement solaire les endroits dangereux se multiplient en cours de journée.

The dangerous spots are found on steep slopes, especially grassy ones, as well as in areas near the ridges

and at the base of rock walls, also due to the possibility of debris falling from above. Avec le réchauffement diurne et le rayonnement solaire la probabilité de déclenchement d'avalanches humides augmente progressivement surtout sur les pentes au soleil. En outre, des avalanches de glissement sont à attendre. Les accumulations de neige soufflée sont de manière isolée fragiles. Les randonnées demandent de l' expérience dans l'évaluation du danger d'avalanche et un choix prudent des itinéraires.

Manteau neigeux

Les conditions météorologiques entraînent un ramollissement rapide du manteau neigeux. Dans le manteau neigeux des couches fragiles sont présentes, surtout sur les pentes à l'ombre.

Tendance

Il fait un temps nuageux.