ICGC Institut Cartogràfic i Geològic de Catalunya

Servei Meteorològic de Catalunya meteo.cat

Boletín de peligro de aludes para el Pirineo de Catalunya
Del 28/02/2026 al 02/03/2026

(Válido fuera pistas de esquí y zonas no controladas)

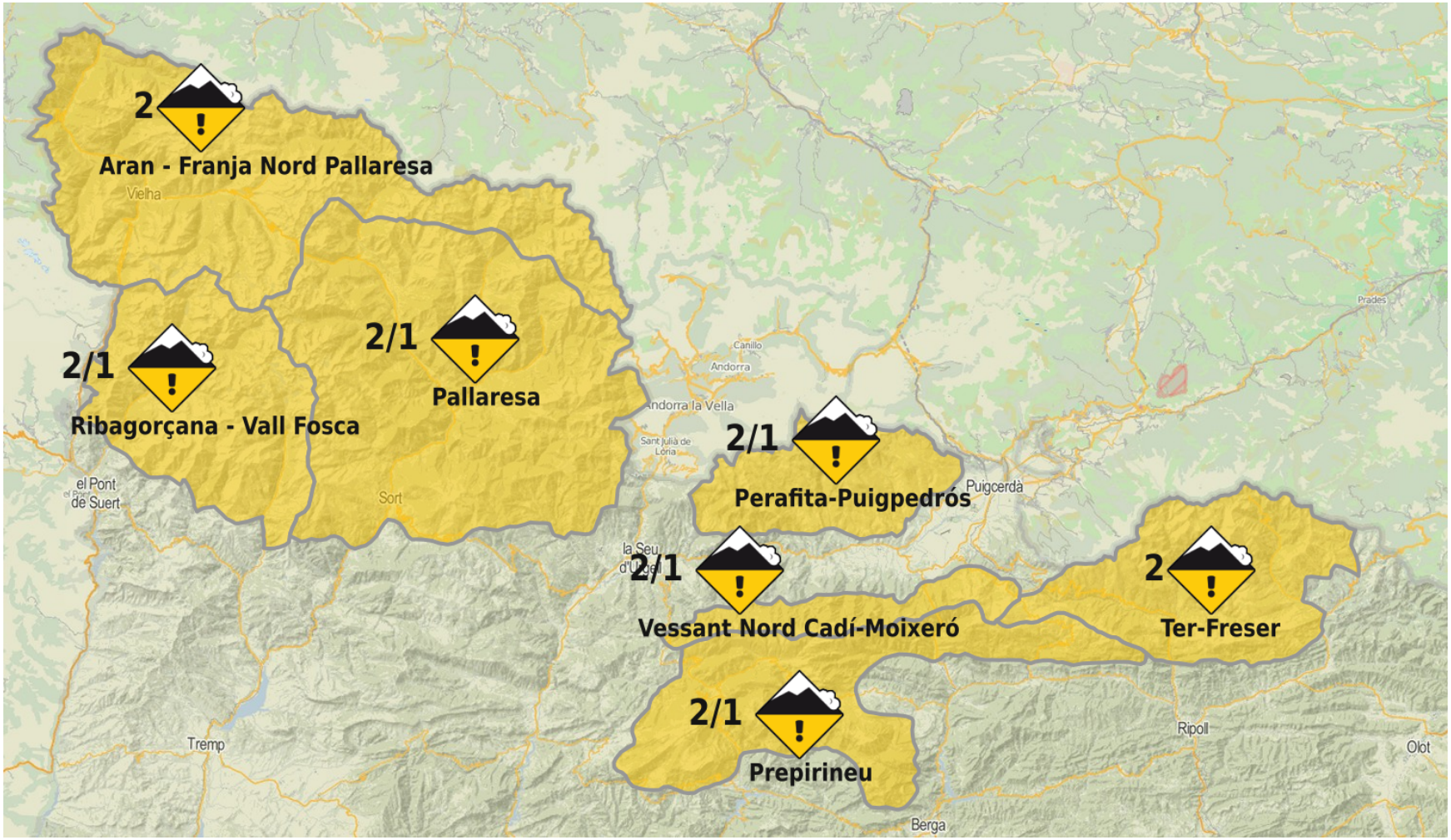

5 MUY FUERTE	4 FUERTE	3 NOTABLE	2 LIMITADO	1 DÉBIL

ICGC Institut Cartogràfic i Geològic de Catalunya

Servei Meteorològic de Catalunya

Boletín de peligro de aludes Aran - Franja Nord Pallaresa Del 28/02/2026 al 02/03/2026

(Válido fuera pistas de esquí y zonas no controladas)

LIMITADO (2)

Situación primaria

Nieve venteada

Distribución

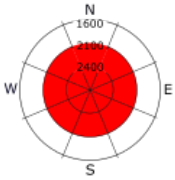

Tamaño

Origen

Tendencia

Situación secundaria

Deslizamientos basales

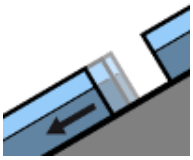

Distribución

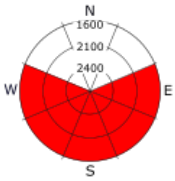

Tamaño

Origen

Tendencia

Estado del manto nivoso

Se espera la formación de nuevas placas por las nevadas del sábado seguidas de varios episodios de viento. Se encontrarán especialmente en sotaventos elevados orientados a norte y este y, a partir del domingo a mediodía, también a sur. En algunos casos estas placas nuevas repondrán sobre niveles de nieve facetada, que podrían facilitar su desencadenamiento y propagación de aludes. Al paso de una persona, se podrán desencadenar aludes en general de tamaño 1, aunque al final del día podrían ser mayores. Durante las últimas jornadas, la actividad de deslizamientos basales ha sido sostenida en el tiempo. Con el sol y el incremento térmico de domingo y lunes se espera que continúen, alcanzando tamaño 2, suficiente para enterrar a una persona, u ocasionalmente mayores. Caerán principalmente de vertientes lisas y herbosas de fuerte pendiente, y sobre todo en momentos de insolación.

Distribución del manto nivoso

Hay nieve por encima de unos 1.400 ma umbrías y 1.600 ma solanas. Los espesores a unos 2.200 m son superiores a los normales y rondan los 120-140 cm en el norte de Aran y los 160-200 cm en la Franja Norte Pallaresa y en el sur de Aran, puntualmente superiores.

Tendencia para las próximas 48-72h

Progresiva estabilización de las placas de viento. Los deslizamientos basales seguirán siendo probables. Peligro EN DESCENSO.

El próximo boletín será emitido el día 2026-03-02

5 MUY FUERTE	4 FUERTE	3 NOTABLE	2 LIMITADO	1 DÉBIL

EAWS EUROPEAN AVALANCHE WARNING SERVICES

ICGC Institut Cartogràfic i Geològic de Catalunya

Servei Meteorològic de Catalunya meteo.cat

Boletín de peligro de aludes Ribagorçana - Vall Fosca Del 28/02/2026 al 02/03/2026

(Válido fuera pistas de esquí y zonas no controladas)

LIMITADO (2) durante las horas de insolación. DÉBIL (1) el resto.

Situación primaria

Deslizamientos basales **Distribución** **Tamaño** **Origen** **Tendencia**

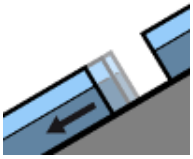

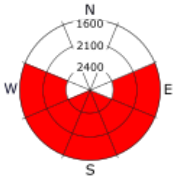

Situación secundaria

Nieve venteada **Distribución** **Tamaño** **Origen** **Tendencia**

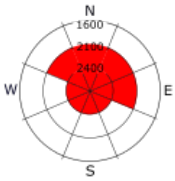

Estado del manto nivoso

Todavía son probables caídas de deslizamientos basales de tamaño 2, suficiente para enterrar a una persona, o incluso mayor. Se desprenden de terreno soleado, de fuerte pendiente, liso y herboso o rocoso, o bajo paredes rocosas. Se debe evitar el terreno bajo grietas, ya que pueden indicar condiciones de deslizamiento del manto sobre el suelo. Entre el domingo y el lunes también serán posibles purgas de nieve húmeda que sobre todo afectarán a la nieve caída el sábado. También encontraremos placas de viento en diferentes sotaventos, los más importantes en orientaciones norte y este, pero también a sur por el giro de viento previsto. Serán placas blandas y, por lo general, bien atadas. Localmente se podrán desprender al paso de una persona y, en caso de caer, serán aludes de tamaño 1 en general.

Distribución del manto nivoso

Hay nieve en el suelo a 1.500 m en terreno umbrío, y por encima de unos 1.700-1800 m en laderas soleadas. El manto es esquiable por encima de unos 1.600 m en umbrías. Los espesores alcanzan los 100-140 cm en cotas medias. Estos valores son superiores a los normales para la época.

Tendencia para las próximas 48-72h

Podrán continuar los deslizamientos basales en sitios propicios. Las placas serán aún menos sensibles al desencadenamiento accidental. Peligro EN LEVE DESCENSO.

El próximo boletín será emitido el día 2026-03-02

5 MUY FUERTE	4 FUERTE	3 NOTABLE	2 LIMITADO	1 DÉBIL

EAWS EUROPEAN AVALANCHE WARNING SERVICES

ICGC Institut Cartogràfic i Geològic de Catalunya

Servei Meteorològic de Catalunya

Boletín de peligro de aludes Pallaresa
Del 28/02/2026 al 02/03/2026

(Válido fuera pistas de esquí y zonas no controladas)

LIMITADO (2) durante las horas de insolación. DÉBIL (1) el resto.

Situación primaria

Deslizamientos basales **Distribución** **Tamaño** **Origen** **Tendencia**

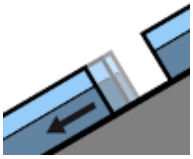

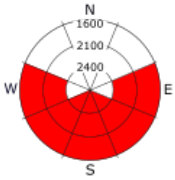

Situación secundaria

Nieve venteada **Distribución** **Tamaño** **Origen** **Tendencia**

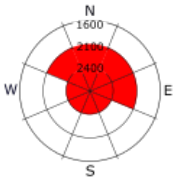

Estado del manto nivoso

Todavía son probables caídas de deslizamientos basales de tamaño 2, suficiente para enterrar a una persona, o incluso mayor. Se desprenden de terreno soleado, de fuerte pendiente, liso y herboso o rocoso, o bajo paredes rocosas. Se debe evitar el terreno bajo grietas, ya que pueden indicar condiciones de deslizamiento del manto sobre el suelo. Entre el domingo y el lunes también serán posibles purgas de nieve húmeda que sobre todo afectarán a la nieve caída el sábado. También encontraremos placas de viento en diferentes sotaventos, los más importantes en orientaciones norte y este, pero también a sur por el giro de viento previsto. Serán placas blandas y, por lo general, bien atadas. Localmente se podrán desprender al paso de una persona y, en caso de caer, serán aludes de tamaño 1 en general.

Distribución del manto nivoso

Hay nieve en el suelo a 1.500 m en terreno umbrío, esquiable por encima de unos 1.600 m; en orientaciones soleadas la nieve está presente por encima de unos 1.700-1.800 m. Los espesores alcanzan los 110-150 cm en cotas medias. Estos valores son superiores a los normales para la época.

Tendencia para las próximas 48-72h

Podrán continuar los deslizamientos basales en sitios propicios. Las placas serán aún menos sensibles al desencadenamiento accidental. Peligro EN LEVE DESCENSO.

El próximo boletín será emitido el día 2026-03-02

5 MUY FUERTE	4 FUERTE	3 NOTABLE	2 LIMITADO	1 DÉBIL

EAWS EUROPEAN AVALANCHE WARNING SERVICES

ICGC Institut Cartogràfic i Geològic de Catalunya

Servei Meteorològic de Catalunya meteo.cat

Boletín de peligro de aludes Perafita-Puigpedrós Del 28/02/2026 al 02/03/2026

(Válido fuera pistas de esquí y zonas no controladas)

LIMITADO (2) durante las horas centrales del día, DÉBIL (1) el resto

Situación primaria

Deslizamientos basales **Distribución** **Tamaño** **Origen** **Tendencia**

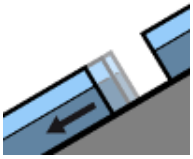

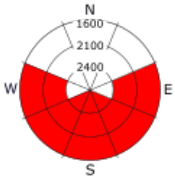

Situación secundaria

Nieve venteada **Distribución** **Tamaño** **Origen** **Tendencia**

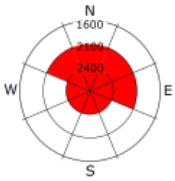

Estado del manto nivoso

De forma local son probables caídas de deslizamientos basales de tamaño 2, suficiente para enterrar a una persona, o incluso mayor. Se desprenden de terreno muy específico, soleado, de fuerte pendiente, liso y herboso o rocoso. Evitar el terreno bajo grietas que llegan hasta el suelo, ya que pueden indicar condiciones de deslizamiento del manto sobre el suelo. El domingo y el lunes también serán probables purgas de nieve húmeda que afectarán a la nieve más superficial y tendrán lugar especialmente a orientaciones este, sur y oeste. Además podremos encontrar placas de viento formadas a partir de la nieve del sábado y el viento, que debe ir girando de componente sur a norte. Serán placas locales, distribuidas por sotaventos de diferentes orientaciones, pero es posible su desencadenamiento al paso de una persona, dando lugar a aludes de tamaño 1.

Distribución del manto nivoso

Hay nieve en el suelo por encima de unos 1.600 m, aunque en las solanas más derechas el manto va retranqueando y la nieve está presente por encima de 1.800 m. Los espesores, aunque irregulares, rondan los 70-100 cm en cotas medias, con frecuentes deflaciones en orientaciones norte y oeste por encima del nivel del bosque. Son grosores muy por encima de los habituales por la época.

Tendencia para las próximas 48-72h

Los deslizamientos basales podrán seguir afectando al sector de forma local, mientras las placas de viento irán estabilizando. Peligro EN LEVE DESCENSO.

El próximo boletín será emitido el día 2026-03-02

5 MUY FUERTE	4 FUERTE	3 NOTABLE	2 LIMITADO	1 DÉBIL

EAWS EUROPEAN AVALANCHE WARNING SERVICES

ICGC Institut Cartogràfic i Geològic de Catalunya

Servei Meteorològic de Catalunya meteo.cat

Boletín de peligro de aludes Vessant Nord Cadí-Moixeró Del 28/02/2026 al 02/03/2026

(Válido fuera pistas de esquí y zonas no controladas)

LIMITADO (2) por encima de 2.200 m.
DÉBIL (1) por debajo.

Situación primaria

Nieve venteada

Distribución

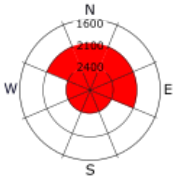

Tamaño

Origen

Tendencia

Situación secundaria

Deslizamientos basales

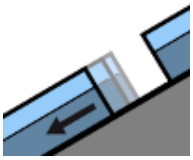

Distribución

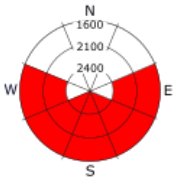

Tamaño

Origen

Tendencia

Estado del manto nivoso

Encontraremos placas de viento formadas durante las nevadas del sábado y los posteriores episodios de transporte, de norte el domingo y nuevamente de sur el lunes. Se encontrarán en zonas de acumulación de distintas orientaciones. Se tratará de placas delgadas, ya que no se esperan grandes acumulaciones y por tanto se podrán romper fácilmente al paso de personas, pero en general ofrecerán un buen vínculo con la nieve vieja y no tendrán una gran capacidad de propagar. Además, son posibles caídas de deslizamientos basales de tamaño 2, suficiente para enterrar a una persona, o incluso mayor. Se desprenden de terreno soleado, de fuerte pendiente, liso y herboso o rocoso, o bajo paredes rocosas. Se debe evitar el terreno bajo grietas, ya que pueden indicar condiciones de deslizamiento del manto sobre el suelo. A partir del domingo podrían caer algunas purgas superficiales de nieve húmeda en momentos de sol.

Distribución del manto nivoso

En umbrías hay nieve por encima de 1.500 m, esquiable por encima de unos 1.700 m. En solanas la nieve está presente por encima de 1.700 m. Los espesores están alrededor de 130-160 cm en cotas medias. Estos valores son excedentarios para la época del año.

Tendencia para las próximas 48-72h

Las placas de viento irán siendo menos inestables. Peligro EN DESCENSO.

El próximo boletín será emitido el día 2026-03-02

5 MUY FUERTE	4 FUERTE	3 NOTABLE	2 LIMITADO	1 DÉBIL

EAWS EUROPEAN AVALANCHE WARNING SERVICES

ICGC Institut Cartogràfic i Geològic de Catalunya

Servei Meteorològic de Catalunya

Boletín de peligro de aludes Prepirineu
Del 28/02/2026 al 02/03/2026

(Válido fuera pistas de esquí y zonas no controladas)

LIMITADO (2) durante las horas centrales del día, DÉBIL (1) el resto

Situación primaria

Deslizamientos basales **Distribución** **Tamaño** **Origen** **Tendencia**

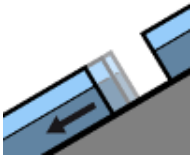

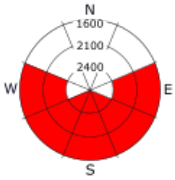

Situación secundaria

Nieve venteada **Distribución** **Tamaño** **Origen** **Tendencia**

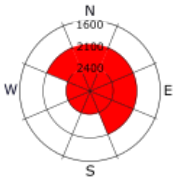

Estado del manto nivoso

De forma local son probables caídas de deslizamientos basales de tamaño 2, suficiente para enterrar a una persona, o incluso mayor. Se desprenden de terreno muy específico, soleado, de fuerte pendiente, liso y herboso o rocoso. Evitar el terreno bajo grietas que llegan hasta el suelo, ya que pueden indicar condiciones de deslizamiento del manto sobre el suelo. El domingo y el lunes también serán probables purgas de nieve húmeda que afectarán a la nieve más superficial y tendrán lugar especialmente a orientaciones este, sur y oeste. Además podremos encontrar placas de viento formadas a partir de la nieve del sábado y el viento, que debe ir girando de componente sur a norte. Serán placas locales, distribuidas por sotaventos de diferentes orientaciones, pero es posible su desencadenamiento al paso de una persona, dando lugar a aludes de tamaño 1.

Distribución del manto nivoso

Hay nieve desde 1.500 a 1600 m esquiable a partir de unos 1.700 m en orientaciones umbrías. En solanas el manto está presente a partir de unos 1.700-1.800 m. Los grosores están alrededor de 90-110 cm a unos 2.200 my son superiores a los habituales. Aparecen deflaciones por encima del nivel del bosque, sobre todo en lugares bien expuestos al viento de norte y oeste.

Tendencia para las próximas 48-72h

Los deslizamientos basales podrán seguir afectando al sector de forma local, mientras las placas de viento irán estabilizando. Peligro EN LEVE DESCENSO.

El próximo boletín será emitido el día 2026-03-02

5 MUY FUERTE	4 FUERTE	3 NOTABLE	2 LIMITADO	1 DÉBIL

EAWS EUROPEAN AVALANCHE WARNING SERVICES

ICGC Institut Cartogràfic i Geològic de Catalunya

Servei Meteorològic de Catalunya

Boletín de peligro de aludes Ter-Freser Del 28/02/2026 al 02/03/2026

(Válido fuera pistas de esquí y zonas no controladas)

LIMITADO (2)

Situación primaria

Deslizamientos basales **Distribución** **Tamaño** **Origen** **Tendencia**

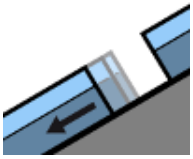

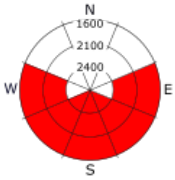

Situación secundaria

Nieve venteada **Distribución** **Tamaño** **Origen** **Tendencia**

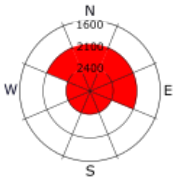

Estado del manto nivoso

La última semana han sido frecuentes los desprendimientos de deslizamientos basales en los sectores. Aún son probables con aludes que podrían llegar a tamaño 3 (suficiente para enterrar a un grupo de personas). Tendrán lugar en laderas empinadas y herbosas, o bajo resaltes rocosos. Habrá que prestar atención con la aparición de grietas hasta el suelo y evitar terreno similar a donde se hayan detectado estos aludes. El domingo y el lunes también serán probables purgas de nieve húmeda que afectarán a la nieve más superficial y tendrán lugar especialmente a orientaciones este, sur y oeste. Además podremos encontrar placas de viento formadas a partir de la nieve del sábado y el viento, que debe ir girando de componente sur a norte. Serán placas locales, distribuidas por sotaventos de diferentes orientaciones, pero es posible su desencadenamiento al paso de una persona, dando lugar a aludes de tamaño 1.

Distribución del manto nivoso

El manto nivoso presenta grosores muy excedentarios para la época del año. En lugares no afectados por el viento, los espesores oscilan entre 80-100 cm a unos 2.000 m, siendo esquiable a partir de unos 1.600 m. Aparecen deflaciones por encima del nivel del bosque, sobre todo en lugares bien expuestos al viento de norte y oeste.

Tendencia para las próximas 48-72h

Continuará la probabilidad de deslizamientos basales de forma local. Las placas de viento irán estabilizando. Peligro EN LEVE DESCENSO.

El próximo boletín será emitido el día 2026-03-02

5 MUY FUERTE	4 FUERTE	3 NOTABLE	2 LIMITADO	1 DÉBIL

EAWS EUROPEAN AVALANCHE WARNING SERVICES