BUTLLETÍ DEL PERILL D'ALLAUS DEL PRINCIPAT D'ANDORRA

Préparé le 28/02/2026 16:00
Prochaine mise à jour le 01/03/2026 à 16h

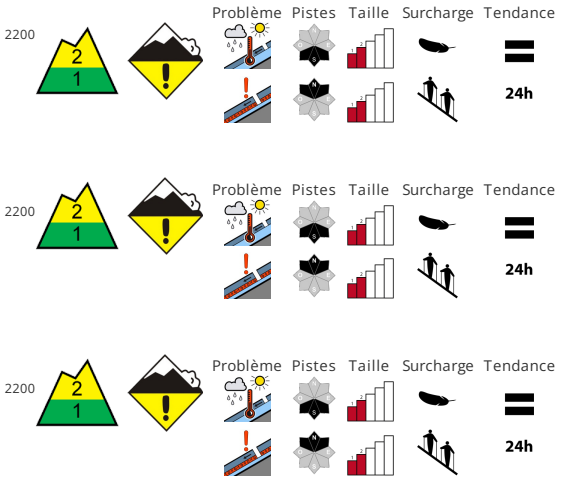

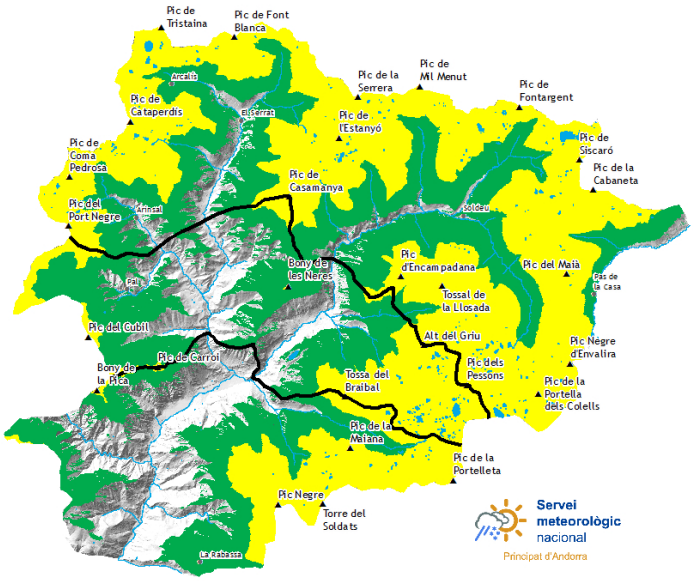

STABILITÉ DU MANTEAU NEIGEUX

Pendant la nuit il tombera un peu de neige. Au milieu du manteau neigeux des couches fragiles sont présentes ils se rencontrent , aussi sur les pentes très raides exposées au nord. Celles-ci peuvent de manière isolée être déchaîné avec une surcharge importante et atteindre une taille moyenne.. Des distances de délestage sont recommandées.. À partir de midi d'avalanches humides augmente un peu augmentera. En outre, des avalanches de glissement sont possibles à tout moment.. Sur la croûte dure il existe en terrain raide un risque de chute..

QUALITÈ DE LA NEIGE

Les conditions sont printanières. Le rayonnement nocturne est bon.. On trouve suivant l'influence du vent des hauteurs de neiges très différentes au-dessus d'environ 2500 m. Les zones présentant des fissures de glissement doivent être évitées..

EPAISSEUR DE NEIGE HORS PISTE

Zone nord		Epaisseur de neige		
Nival manteau		1500m	2000m	2500m
N	1500 m	30 cm	150 cm	200 cm
S	1800 m	0 cm	100 cm	150 cm

Zone centre		Epaisseur de neige		
Nival manteau		1500m	2000m	2500m
N	1500 m	20 cm	150 cm	200 cm
S	1800 m	0 cm	100 cm	150 cm

Zone sud		Epaisseur de neige		
Nival manteau		1500m	2000m	2500m
N	1500 m	20 cm	120 cm	150 cm
S	1800 m	0 cm	60 cm	100 cm

Govern d'Andorra

EAWS EUROPEAN AVALANCHE WARNING SERVICES

Aquest butlletí ha estat elaborat seguint les normes i recomanacions de l'**European Avalanche Warning Services**, del qual el **Servei meteorològic Nacional** n'és membre

BUTLLETÍ DEL PERILL D'ALLAUS DEL PRINCIPAT D'ANDORRA

Servei meteorològic nacional
Principat d'Andorra

Des informations détaillées par espace naturel protégé

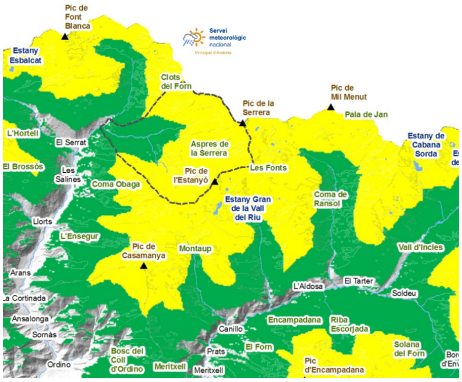

SORTENY

Peu de neige, nouvelle neige ne change pas les conditions de stabilité. Nous trouvons de la neige sur toutes les routes depuis Llorts et l'accès à skis au Refuge peut se faire car on ne l'a pas vu depuis tant de semaines d'affilée depuis des années. Au-dessus du lac, sur le versant nord, nous trouvons des couches fragiles et persistantes cachées sous la poudreuse. Ces couches faibles persistantes pourraient déclencher des avalanches de plaques moyennes qui pourraient créer d'importantes coupures de neige ou des cicatrices qui pourraient avoir de graves conséquences. Ainsi, même si ce type de stabilité n'a été identifié que sur les pentes les plus raides, au-dessus de 2 400 mètres et orientées vers le nord (obacs), il faut en tenir compte pour choisir son itinéraire en toute sécurité. , , , , , , , , ,

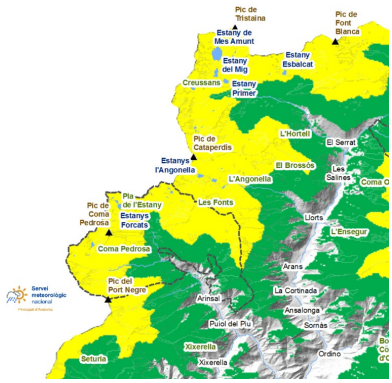

COMAPEDROSA

Il faudra faire attention à ne pas glisser à cause de la croûte de glace qui sera cachée sous une fine couche de neige fraîche. La répartition de la neige est très irrégulière à cause du vent. Sur les pentes nord plus inclinées, nous devrons conduire avec prudence et garder une distance de sécurité pour éviter d'activer les couches faibles persistantes. , , , , ,

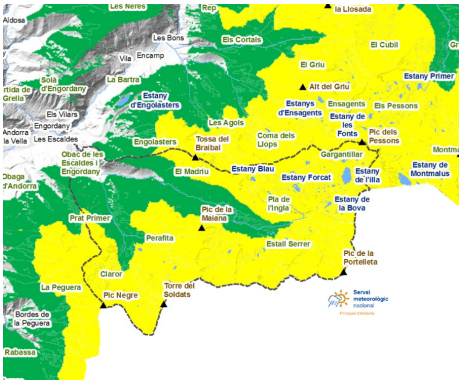

MADRIU-PERAFITA-CLAROR

Sur le versant sud et à basse altitude, les conditions sont printanières, neige dure le matin et neige molle l'après-midi, avec des formes typiques de fonte lorsque le soleil frappe perpendiculairement à la pente. Le peu de neige fraîche ne recouvrira pas complètement ces formes ni les nombreuses traces de la course d'il y a une semaine. Sur les versants nord et les plaines, la neige reste poudreuse. , , , , ,

Govern d'Andorra

EAWS
EUROPEAN AVALANCHE WARNING SERVICES

Aquest butlletí ha estat elaborat seguint les normes i recomanacions de l'**European Avalanche Warning Services**, del qual el **Servei meteorològic Nacional** n'és membre

BUTLLETÍ DEL PERILL D'ALLAUS DEL PRINCIPAT D'ANDORRA

Servei meteorològic nacional
Principat d'Andorra

Couche de neige fraiche des derniers jours (De 24 h mesurée à 06:00 h UTC)

	24/02/2026	25/02/2026	26/02/2026	27/02/2026
FEDA (Central)	0 cm	0 cm	0 cm	0 cm
Engolasters - FEDA	0 cm	0 cm	0 cm	0 cm
Bony de les Neres	0 cm	0 cm	0 cm	0 cm
Sorteny	0 cm	0 cm	0 cm	0 cm
Perafita	0 cm	0 cm	0 cm	0 cm
Tossa Espiolets	0 cm	0 cm	0 cm	0 cm
Grau Roig - FEDA	0 cm	0 cm	0 cm	0 cm
Fontverd	0 cm	0 cm	0 cm	0 cm
Ransol - FEDA	0 cm	0 cm	0 cm	0 cm
Setúria	0 cm	0 cm	0 cm	0 cm
Caborreu	0 cm	0 cm	0 cm	0 cm
La Solana	0 cm	0 cm	0 cm	0 cm
Envalira Antenes	0 cm	0 cm	0 cm	0 cm
Vall del Riu FEDA	0 cm	0 cm	0 cm	0 cm