ALPI RETICHE

Bollettino Valanghe N. 360/2026 del 27/02/2026 ore 14.00
Validità 48 ore prossima emissione 28/02/2026

A cura del Servizio METEOMONT dell'ARMA dei CARABINIERI
In collaborazione con Servizio Meteorologico dell'Aeronautica militare

SITUAZIONE alle 14:00 del 27/02/2026

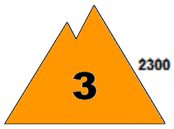

SITUAZIONE TIPO: passaggio da poca a molta neve.



SITUAZIONE TIPO: situazione primaverile.

Quota neve (mslm)	Nord	Sud
	1400 - 1600	1700 - 1900

Altezza Neve (cm)	Neve al suolo	Neve Fresca	Quota (mslm)
	59	0	2582
	52	0	1640

VALANGHE OSSERVATE: Alcune valanghe di medie dimensioni, I due tipi di valanghe di neve di superficie.

PREVISIONI 28/02/2026

GRADO DI PERICOLO: MARCATO 3

SITUAZIONE TIPO: passaggio da poca a molta neve.

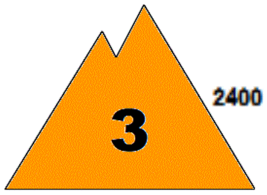



SITUAZIONE TIPO: situazione primaverile.

MANTO NEVOSO: La stabilità del manto nevoso è molto scarsa su alcuni punti (aree) per versanti da ovest a est al di sopra di 2400 mslm, possibili valanghe di dimensioni medie.
La stabilità del manto nevoso è scarsa su molti punti (aree) per versanti da est a ovest al di sotto di 2400 mslm, possibili valanghe di dimensioni medie.

AVVERTENZE

Il rialzo termico diurno richiede un'attenta valutazione temporale dell'escursione che eviti l'attraversamento di pendii ripidi nelle ore più calde della giornata.

SCALA EUROPEA DEL GRADO DI PERICOLO VALANGHE

LEGENDA PROBLEMA

Bollettino realizzato su scala sinottica-regionale (standard EAWS). La sua valutazione non può escludere in alcun modo la necessità di una seria e capace valutazione locale del pericolo (singolo pendio) che può essere anche sensibilmente diverso. Le previsioni meteorologiche sono relative all'orario UTC (per l'Italia +1 in inverno e +2 in estate).

MINISTERO DELLA DIFESA

meteomont
Servizio Nazionale di previsione neve e valanghe

EAWS EUROPEAN AVALANCHE WARNING SERVICES

CARABINIERI

ALPI RETICHE

PREVISIONE METEO

Quota		28/02/2026 h6:00	28/02/2026 h12:00	28/02/2026 h18:00
1000	Venti	00 Calma	01 Nodi da Est	01 Nodi da N-Est
	Temperature	+04 °C	+04 °C	+02 °C
	Temp.percepita	4 °C	4 °C	2 °C
2000	Venti	00 Calma	01 Nodi da Est	01 Nodi da N-Est
	Temperature	+04 °C	+04 °C	+02 °C
	Temp.percepita	4 °C	4 °C	2 °C
3000	Venti	04 Nodi da S-Ovest	06 Nodi da S-Ovest	05 Nodi da S-Ovest
	Temperature	-01 °C	-02 °C	-02 °C
	Temp.percepita	-4 °C	-6 °C	-5 °C
Zero termico		2300-2500 m.	2400-2600 m.	2300-2500 m.
Fenomeno		—	—	—
Stato del cielo				

LEGENDA FENOMENI

— Assenza Fenomeni
Nebbia
Foschia
Pioggia debole
Pioggia moderata
Pioggia forte
Temporali
Nevicata debole
Nevicata moderata
Nevicata forte

STATO DEL CIELO

Sereno
Poco nuvoloso
Nuvoloso
Molto nuvoloso
Coperto

Parametri meteonivometrici registrati presso i campi di rilevamento il 27/02/2026.

Località	Comune	Quota (m.s.l.m.)	Altezza neve (cm)	Neve caduta nelle 24 ore (cm)	Temp. Min (°C)	Temp. Max (°C)	Condizioni del tempo
VALAR	Valdidentro (SO)	1930	73	0	N.P.	N.P.	Assenza di precipitazioni
DOSSO DEL VALLONE	Valfurva (SO)	2582	59	0	-6	+8	Assenza di precipitazioni
VIALACC *	Vione (BS)	1670	8	0	N.P.	N.P.	Assenza di precipitazioni
ALPE PALU'	Chiesa in Valmalenco (SO)	2010	75	0	+0	+11	Assenza di precipitazioni
COLONIA VIGILI	Ponte di Legno (BS)	1640	52	0	-1	+13	Assenza di precipitazioni
VAL CANCANO *	Valdidentro (SO)	2409	170	0	N.P.	N.P.	Assenza di precipitazioni
CIMA MONTICELLI *	Temù (BS)	3128	147	0	N.P.	N.P.	Assenza di precipitazioni

(*) Rilievi fuori campo

L'INFORMAZIONE E' PREVENZIONE - LEGGI L'ATTUALE GRADO DI PERICOLO VALANGHE!

IL CAPO DEL CENTRO NAZIONALE METEOMONT
(Ten. Col. RFI Emanuela Gini)
FIRMA AUTOGRAFA OMESSA AI SENSI
DELL'ART.3 DEL D.LGS N.39/1993

Bollettino realizzato su scala sinottica-regionale (standard EAWS). La sua valutazione non può escludere in alcun modo la necessità di una seria e capace valutazione locale del pericolo (singolo pendio) che può essere anche sensibilmente diverso. Le previsioni meteorologiche sono relative all'orario UTC (per l'Italia +1 in inverno e +2 in estate).