TERMINILLO MONTI REATINI E LAGA OVEST

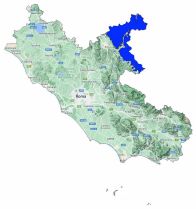

Bollettino Valanghe N. 301/2026 del 28/02/2026 ore 14.00
Validità 48 ore prossima emissione 01/03/2026

A cura del Servizio METEOMONT dell'ARMA dei CARABINIERI
In collaborazione con Servizio Meteorologico dell'Aeronautica militare

SITUAZIONE alle 14:00 del 28/02/2026

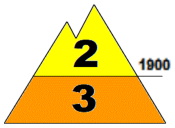

SITUAZIONE TIPO: neve a debole coesione e vento.

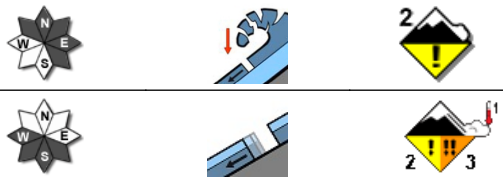

SITUAZIONE TIPO: neve da slittamento.

	Nord	Sud
Quota neve (mslm)	*1600*	*1700*

	Neve al suolo	Neve Fresca	Quota (mslm)
Altezza Neve (cm)	*045*	*000*	*1724*
	002	*000*	*1350*

VALANGHE OSSERVATE: Nessuna valanga.

PREVISIONI 01/03/2026

GRADO DI PERICOLO: MODERATO 2

SITUAZIONE TIPO: neve a debole coesione e vento.

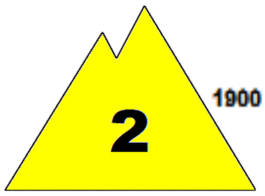

SITUAZIONE TIPO: neve da slittamento.

MANTO NEVOSO: La stabilità del manto nevoso è discreta su alcuni punti (aree) per versanti da nord ovest a sud est compresi al di sopra di 1900 mslm, possibili valanghe di dimensioni medie.
La stabilità del manto nevoso è scarsa su alcuni punti (aree) per versanti al sole al di sotto di 1900 mslm, possibili valanghe di dimensioni medie.

AVVERTENZE

Il rialzo termico diurno richiede un'attenta valutazione temporale dell'escursione che eviti l'attraversamento di pendii ripidi nelle ore più calde della giornata.

SCALA EUROPEA DEL GRADO DI PERICOLO VALANGHE

LEGENDA PROBLEMA

Bollettino realizzato su scala sinottica-regionale (standard EAWS). La sua valutazione non può escludere in alcun modo la necessità di una seria e capace valutazione locale del pericolo (singolo pendio) che può essere anche sensibilmente diverso. Le previsioni meteorologiche sono relative all'orario UTC (per l'Italia +1 in inverno e +2 in estate).

MINISTERO DELLA DIFESA

meteomont
Servizio Nazionale di previsione neve e valanghe

EAWS EUROPEAN AVALANCHE WARNING SERVICES

CARABINIERI

TERMINILLO MONTI REATINI E LAGA OVEST

PREVISIONE METEO

Quota		01/03/2026 h6:00	01/03/2026 h12:00	01/03/2026 h18:00
1000	Venti	02 Nodi da Sud	02 Nodi da Sud	02 Nodi da S-Ovest
	Temperature	+04 °C	+07 °C	+04 °C
	Temp.percepita	4 °C	7 °C	4 °C
2000	Venti	04 Nodi da Sud	03 Nodi da Sud	04 Nodi da Sud
	Temperature	+03 °C	+02 °C	+02 °C
	Temp.percepita	1 °C	0 °C	-0 °C
3000	Venti	05 Nodi da Sud	08 Nodi da S-Ovest	08 Nodi da S-Ovest
	Temperature	-02 °C	-01 °C	-02 °C
	Temp.percepita	-5 °C	-6 °C	-7 °C
Zero termico		2500-2700 m.	2600-2800 m.	2400-2600 m.
Fenomeno		—	—	—
Stato del cielo				

LEGENDA FENOMENI

— Assenza Fenomeni · Nebbia · Foschia · Pioggia debole · Pioggia moderata · Pioggia forte · Temporali

Nevicata debole · Nevicata moderata · Nevicata forte

STATO DEL CIELO

Sereno · Poco nuvoloso · Nuvoloso · Molto nuvoloso · Coperto

Parametri meteonivometrici registrati presso i campi di rilevamento il 28/02/2026.

Località	Comune	Quota (m.s.l.m.)	Altezza neve (cm)	Neve caduta nelle 24 ore (cm)	Temp. Min (°C)	Temp. Max (°C)	Condizioni del tempo
PESCHIERE	Amatrice (RI)	1270	0	0	+3	+19	Assenza di precipitazioni
M. CAIDURO	Cittareale (RI)	1300	0	0	+5	+19	Assenza di precipitazioni
VALLONINA	Leonessa (RI)	1350	2	0	+1	+18	Assenza di precipitazioni
ANELLO DI CAMPOFOROGNA *	Micigliano (RI)	1724	45	0	+3	+6	Assenza di precipitazioni

(*) Rilievi fuori campo

L'INFORMAZIONE E' PREVENZIONE - LEGGI L'ATTUALE GRADO DI PERICOLO VALANGHE!

IL CAPO DEL CENTRO NAZIONALE METEOMONT
(Ten. Col. RFI Emanuela Gini)
FIRMA AUTOGRAFA OMESSA AI SENSI
DELL'ART.3 DEL D.LGS N.39/1993

Bollettino realizzato su scala sinottica-regionale (standard EAWS). La sua valutazione non può escludere in alcun modo la necessità di una seria e capace valutazione locale del pericolo (singolo pendio) che può essere anche sensibilmente diverso. Le previsioni meteorologiche sono relative all'orario UTC (per l'Italia +1 in inverno e +2 in estate).