Bulletin d'estimation du risque d'avalanche
(valable en dehors des pistes balisées et ouvertes)

MASSIF : Maurienne

Rédigé le samedi 28 février 2026 à 16h

Estimation des risques pour le : DIMANCHE 01 MARS

MANTEAU GLOBALEMENT ASSEZ BIEN STABILISE

2

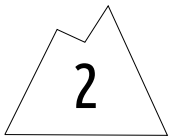

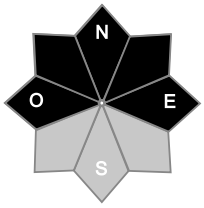

Indice de risque limité.

Départs spontanés : rares plaques de fond.

Déclenchements provoqués : rares plaques dans les versants ombragés.

Indices de risque : 5 très fort - 4 fort - 3 marqué - 2 limité - 1 faible -- En noir : les pentes les plus dangereuses

Stabilité du manteau neigeux

Situation avalancheuse typique : couche fragile persistante neige humide

Déclenchements provoqués :
- **Au-dessus de 2000/2200 m, en versants O/N/E, rares plaques dures** sur couche fragile persistante. Le déclenchement est **encore possible dans les zones moins enneigées** (abords de crête, croupes dégarnis) car la couche fragile est alors plus près de la surface. Cassure 50/70cm pouvant aller jusqu'à 1m . Ailleurs, le déclenchement est peu probable car la couche fragile est généralement profondément enfouie et donc très difficilement sollicitable par un skieur.

Départs spontanés :
- De **rares mais épaisses plaques de fond** peuvent descendre spontanément, **quelles que soient l'heure et l'orientation**. Plutôt **sous 2200/2400 m** et dans les pentes habituelles (herbe, dalle rocheuse). Le manteau neigeux actuel étant épais, les volumes mobilisés peuvent être plus conséquents que d'habitude. **taille 2 (moyenne)**.
- Rare avalanche de neige humide dans l'après midi dans une pente de basse altitude revenue en neige pourrie

Qualité de la neige

Enneigement : après les chutes de neige de mi février, l'enneigement était devenu excédentaire à toutes altitudes. Les températures anormalement douces et le tassement font renter l'enneigement dans la normale, surtout en Sud et en basse montagne où la limite d'enneigement dans ces pentes remonte vite. Ailleurs le manteau se tasse considérablement.

Limite skiable : encore skiable dès 1100 m dans les prairies orientées Nord, plutôt 1400 m en Sud.

Qualité de la neige :
En Sud, croûte portante au réveil qui ramollie plus ou moins bien en fonction de l'épaisseur de la couche nuageuse et de l'altitude.
En Nord, neige croutée sous 1900 m Plus haut, neige encore froide, poudreuse dense à l'abri du vent, cartonnée voire dure dans les secteurs ventés (à l'approche des crêtes). Elle tend à s'humidifier et devenir collante jusque vers 2300 m en cours de journée à cause des nuages plus présents que les jours précédents .

Aperçu météo pour le dimanche 01 mars

nuit	matin	après-midi	soir

Assez nuageux dans l'ensemble, quelques trouées devenant plus franches en fin de journée

Pluie-Neige				
Iso 0 °C	2 100 m	2 100 m	2 400 m	2 100 m
Vent 2000 m	5 km/h	5 km/h	10 km/h	10 km/h
Vent 3000 m	10 km/h	20 km/h	20 km/h	20 km/h

Épaisseur de neige hors-piste

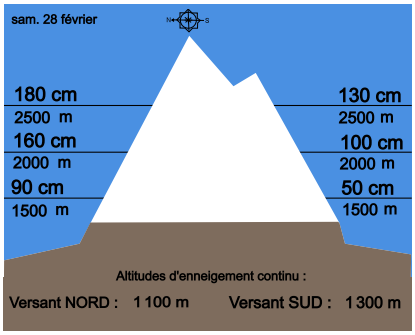

Précipitations à 1800 m

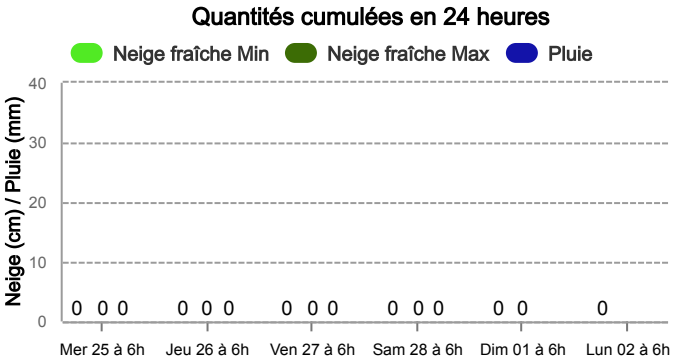

Tendance du lundi 02 mars

2

Indice de risque limité

Bon regel la nuit et beau temps doux en journée. Fonte en versant ensoleillé, peu de changement ailleurs. Risque stationnaire

Pour consulter la vigilance en cours, veuillez vous rendre sur le site https://vigilance.meteofrance.fr/fr

Météo-France - 73 avenue de Paris, 94165 Saint-Mandé cedex - Contact : contact@meteo.fr

Rédigé par Météo-France avec la contribution des observateurs du réseau nivo-météorologiques. Partenariat : ANMSM (Maires de Stations de Montagne), DSF (Domaines Skiables de France), ADSP (Directeurs de Pistes et de la Sécurité des Stations de Sports d'Hiver) et autres acteurs de la montagne.

Bulletin neige & avalanches par téléphone au
0 892 68 10 20 Service 0,35 € / min + prix appel

RÉPUBLIQUE FRANÇAISE
Liberté Égalité Fraternité

METEO FRANCE
À VOS CÔTÉS, DANS UN CLIMAT QUI CHANGE

Bulletin d'estimation du risque d'avalanche
(valable en dehors des pistes balisées et ouvertes)

MASSIF : Maurienne

Rédigé le samedi 28 février 2026 à 16h

Conditions nivo-météo des 7 derniers jours

	dim. 22/02				lun. 23/02				mar. 24/02				mer. 25/02				jeu. 26/02				ven. 27/02				sam. 28/02			
	03h	09h	15h	21h	03h	09h	15h	21h	03h	09h	15h	21h	03h	09h	15h	21h	03h	09h	15h	21h	03h	09h	15h	21h	03h	09h	15h	21h
Météo																												
Vent (km/h)	40	30	30	30	45	50	50	45	35	30	25	20	15	15	15	15	15	15	15	15	10	10	10	10	10	15	15	10
à 3000m																												
Vent (km/h)	15	10	10	10	15	15	15	10	15	10	5	5	5	5	5	5	5	5	5	5	5	5	5	5	5	5	10	5
à 2000m																												

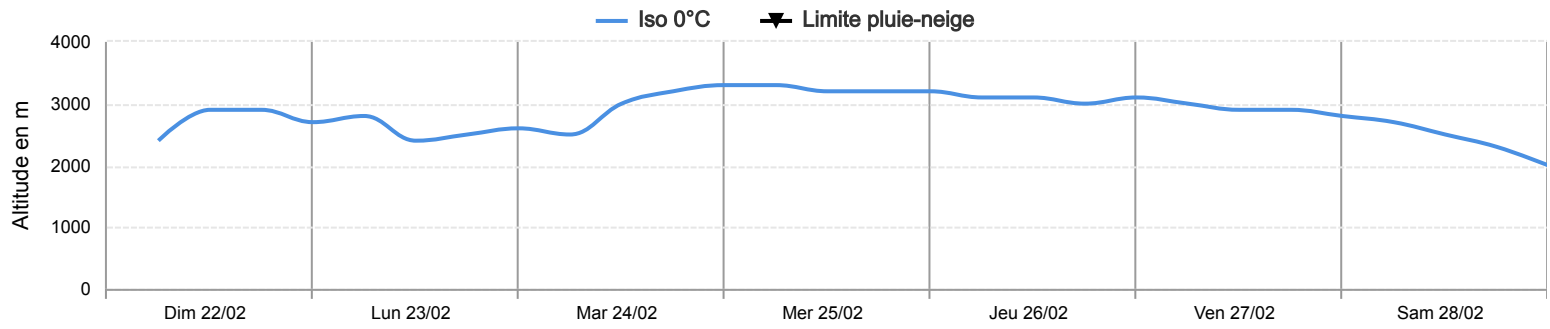

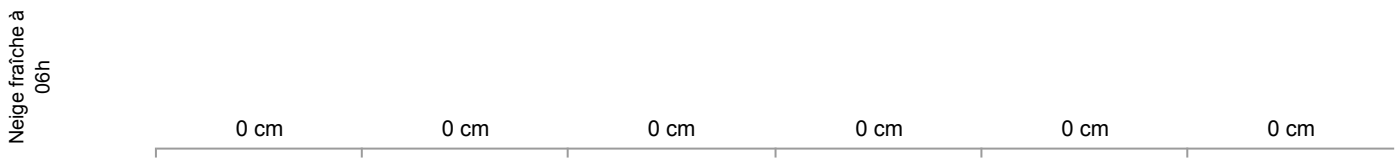

Risque d'avalanche	dim. 22/02	lun. 23/02	mar. 24/02	mer. 25/02	jeu. 26/02	ven. 27/02	sam. 28/02
	3	2	3	3	3	3	2

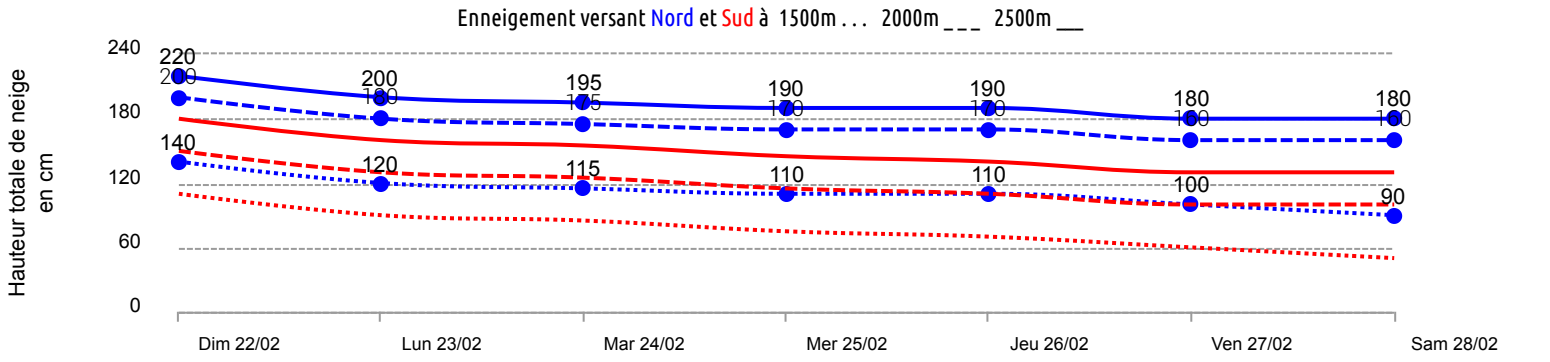

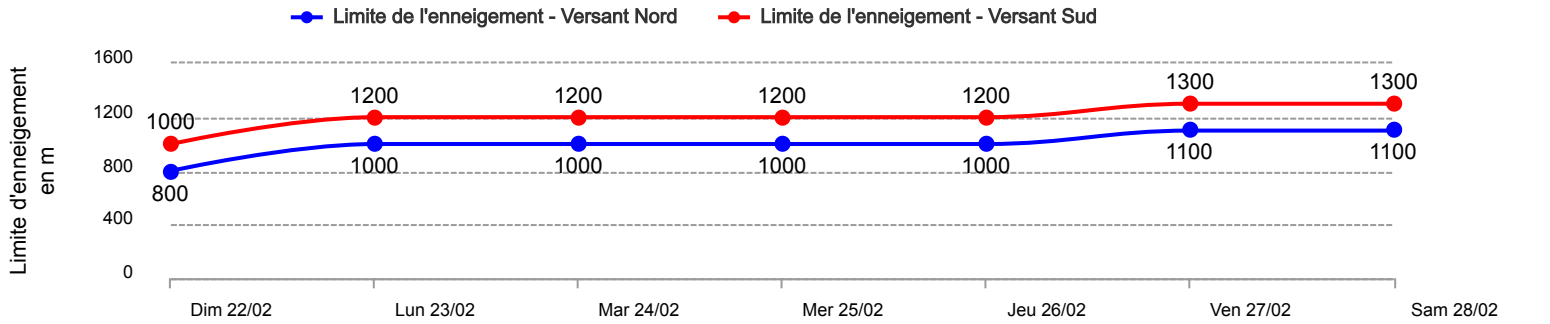

Pour consulter la vigilance en cours, veuillez vous rendre sur le site https://vigilance.meteofrance.fr/fr

Météo-France - 73 avenue de Paris, 94165 Saint-Mandé cedex - Contact : contact@meteo.fr

Bulletin neige & avalanches par téléphone au

0 892 68 10 20 Service 0,35 € / min + prix appel

Rédigé par Météo-France avec la contribution des observateurs du réseau nivo-météorologiques. Partenariat : ANMSM (Maires de Stations de Montagne), DSF (Domaines Skiables de France), ADSP (Directeurs de Pistes et de la Sécurité des Stations de Sports d'Hiver) et autres acteurs de la montagne.