GOBIERNO DE ESPAÑA
VICEPRESIDENCIA TERCERA DEL GOBIERNO
MINISTERIO PARA LA TRANSICIÓN ECOLÓGICA Y EL RETO DEMOGRÁFICO

Boletín de información nivológica y de peligro de aludes

Pirineo Navarro y Aragonés

aemet Agencia Estatal de Meteorología

domingo, 1 de marzo de 2026

Pronóstico hasta las 24 horas del lunes, día 2 de marzo

(Válido fuera de pistas de esquí balizadas y abiertas)

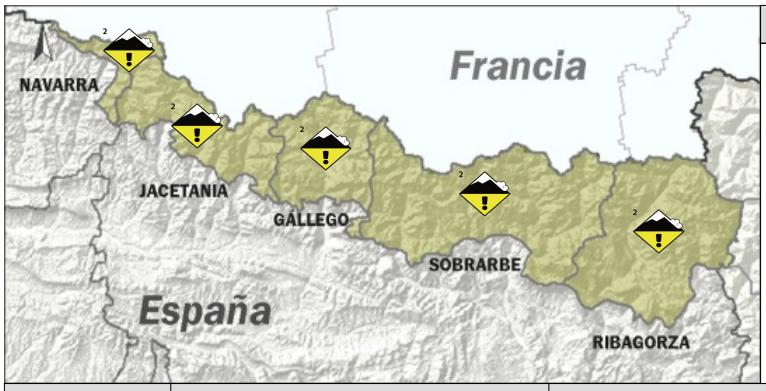

Problemas de aludes

Placas de viento

Nieve húmeda

Macizo	Peligro	Problemas de aludes, cota, orientación, tamaño	Innivación observada (m)
Navarra	2 Limitado	Placas de viento: 2000, N E S O, 2 Nieve húmeda: 2200, N E S O, 2	2026-03-01 N S Cota más baja caras N
Jacetania	2 Limitado	Placas de viento: 2000, N E S O, 2 Nieve húmeda: 2200, N E S O, 2	2026-03-01 N S Cota más baja caras N
Gállego	2 Limitado	Placas de viento: 2000, N E S O, 2 Nieve húmeda: 2200, N E S O, 2	2026-03-01 N S Cota más baja caras N

AEMET. Se autoriza la reproducción de su contenido citando la fuente.

Boletín de información nivológica y de peligro de aludes

Pirineo Navarro y Aragonés

Sobrarbe	**Limitado**	**Placas de viento** 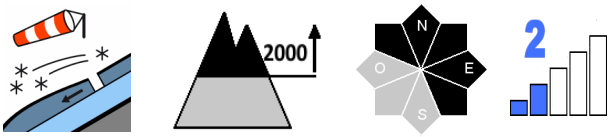 **Nieve húmeda** 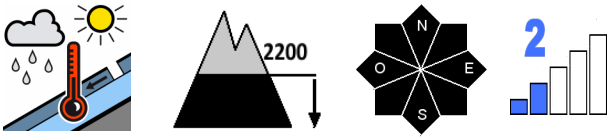	2026-03-01 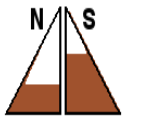 Cota más baja caras N
Ribagorza	**Limitado**	**Placas de viento** 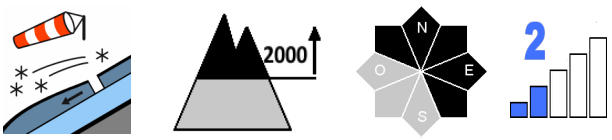 **Nieve húmeda** 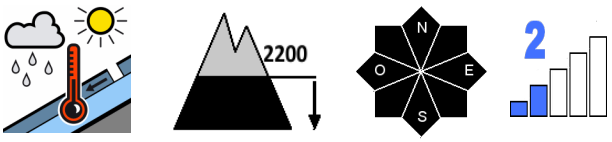	2026-03-01 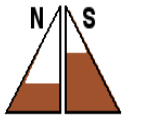 Cota más baja caras N

Estado del manto y observaciones recientes

En las últimas 24 horas se han registrado algunas precipitaciones débiles y ocasionales, en forma de nieve a partir del entorno de los 1700-1800 metros, pudiendo haber añadido algunos centímetros de nieve reciente en cotas altas. En cualquier caso, en la red de observación hoy se han vuelto a registrar nuevas pérdidas de espesor, aunque menos significativas que en los días anteriores. Aún con todo, los espesores se encuentran por encima de lo que sería habitual a estas alturas de la temporada.

El manto comienza de manera continua a unos 1300 metros en umbrías y a unos 1500 metros en solanas. Aunque a estas altitudes se puedan alcanzar los 70-80 cm de espesor, ya se observa una asimetría norte-sur, con pérdidas notables en las solanas, donde incluso se pueden encontrar zonas desprovistas de nieve. Conforme ascendemos en altitud estos van incrementando, de manera que en cotas medias los espesores son muy abundantes, superando los 200 cm a unos 1900 metros y los 300 cm a unos 2300, pudiendo alcanzar los 4 metros en ventisqueros, hoyas y otras zonas propensas a la acumulación de cotas altas.

En cotas medias y bajas, así como en solanas a mayor altitud, el manto se ha humidificado en profundidad y, por lo general, amanece encostrado. El calentamiento diurno y la intensa radiación van ablandando las costras durante la mañana en las solanas, sometiéndose a un ciclo de rehielo-fusión diario, siendo menos efectivo en umbrías de cotas medias, donde las costras suelen permanecer intactas durante toda la jornada.

En umbrías de cotas altas, la nieve se mantiene más seca y aún podemos encontrar placas de viento dispersas que no se han estabilizado por completo, que generalmente serán de tamaño pequeño y poco reactivas. Cabe destacar que se han realizado varios sondeos en estos enclaves, reaccionando a los test de estabilidad ante esfuerzos generalmente grandes, en algún caso medianos, a veces con propagación de la fractura, y en algún caso a profundidades considerables. Esto da cuenta de la posibilidad de desencadenamiento de

AEMET. Se autoriza la reproducción de su contenido citando la fuente.

aludes de tamaño mediano o incluso grande ante sobrecargas grandes, sin descartar que localmente pueda suceder con sobrecargas menores.

Hoy se han reportado varios aludes de fondo de hasta tamaño mediano en orientaciones sur de cotas medias, así como algunas avalanchas naturales húmedas puntuales, que en general han sido de tamaño pequeño, salvo una de tamaño grande. También se ha reportado un alud de placa a unos 2000 metros de altitud, de tamaño mediano en cara norte.

Evolución del manto y peligro de aludes para el lunes, día 2

Problema de nieve húmeda y deslizamientos basales. Problema de placas de viento y capas débiles persistentes en cotas altas.

En cotas medias y bajas, se espera que el rehielo no sea tan efectivo como en días anteriores, siendo probables los aludes espontáneos de nieve húmeda desde primeras horas, de tamaño 1 (pequeño) ó 2 (mediano), así como los deslizamientos basales en zonas herbosas o de roca lisa, que podrían movilizar una cantidad de nieve considerable y alcanzar localmente el tamaño 3 (grande). Cabe mencionar que, con el avance del día, el calentamiento diurno y el efecto de la insolación harán que el manto sea cada vez más inestable y, por tanto, más probable el desencadenamiento de este tipo de aludes, especialmente en las solanas.

En cotas altas, se espera que se sigan formando nuevas placas de viento, que se añadirán a las formadas en los días anteriores, preferentemente en orientaciones norte y este, debido al arrastre por el viento de la nieve recién caída en las últimas jornadas. Estas estructuras de nueva formación podrán colapsar ante sobrecargas débiles (paso de un sólo esquiador), generando aludes de tamaño 1 (pequeño) o localmente 2 (mediano). Además, todavía quedan placas de formación más antigua en todas las orientaciones que siguen sin estabilizarse por completo, sobre todo en umbrías, las cuales podrían reaccionar ante sobrecargas grandes (paso de dos o más esquiadores), sin descartar en algún caso débiles (un solo esquiador). En caso de que estas últimas colapsen, serían posibles los aludes de tamaño 2 (mediano), o incluso 3 (grande) en caso de afectar a niveles inferiores y fracturar alguna capa débil en profundidad.

Predicción meteorológica para el lunes, día 2

Pirineo navarro:
Predominio de poco nuboso con nubes altas, sin descartar algún intervalo de nubes medias y bajas. No se esperan precipitaciones. Temperaturas en ascenso, moderado o notable en las mínimas y ligero en las máximas. Heladas débiles en cumbres. Viento moderado o fuerte de componente sur, con probables rachas muy fuertes en zonas de la divisoria con Francia.

Pirineo aragonés:
Poco nuboso, aumentando la nubosidad por la tarde, cuando la visibilidad se podrá ver localmente reducida. No se esperan precipitaciones. Temperaturas mínimas en ligero o moderado ascenso, localmente notable en los macizos occidentales. Máximas sin cambios o en ligero ascenso. Heladas débiles, localmente moderadas en cotas altas y fondos de valles. Viento de componente sur, flojo o moderado. Más intenso en cotas altas y zonas expuestas, especialmente de la Jacetania, donde soplará ocasionalmente fuerte.

AEMET. Se autoriza la reproducción de su contenido citando la fuente.

Datos en la atmósfera libre:

Altitud de la isoterma de 0 ºC: 2100 m
Altitud de la isoterma de -10 ºC: 4000 m

Viento a 1500 m: SE 20 km/h
Viento a 3000 m: SW 40 km/h

Evolución para el martes día 3

Nivel de peligro con pocos cambios.

(Información elaborada a partir de los datos recibidos de los refugios de Linza, Lizara, Panticosa, Bachimaña, Góriz, Pineta, Estós, Angel Orús, La Renclusa, Cap de Llauset y Belagua, de las estaciones de esquí de Astún, Formigal y Panticosa (lagos) y de Ordesa Pradera)

Escala europea de peligro de aludes

Débil | Limitado | Notable | Fuerte | Muy Fuerte

Problemas de aludes

Nieve reciente | Placas de viento | Capas débiles persistentes | Nieve húmeda | Deslizamientos basales | Sin problema evidente

Nota1: Se recuerda que, siempre que haya nieve, la ausencia total de peligro no existe. Hay que tener presente que en circunstancias desfavorables, con aludes de tamaño 1 (alud pequeño o colada) y tamaño 2 (alud mediano), se pueden sufrir severos daños personales.

Nota2: Los BPA se elaboran en base a información meteorológica así como al estado del manto nivoso a través de sondeos puntuales. Se advierte a los usuarios de la variabilidad de esta información al extrapolarla a zonas extensas de montaña. Por ello, AEMET no se hace responsable de su uso para la toma de decisiones que conciernen a la seguridad personal, ni de los riesgos físicos o materiales de ellas derivadas.

AEMET. Se autoriza la reproducción de su contenido citando la fuente.