Sonntag 01.03.2026

Aktualisiert am 01.03.2026 um 08:00

Vormittag

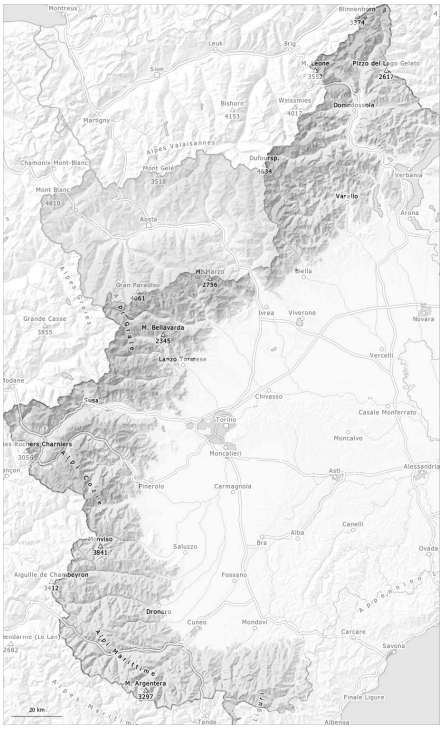

Nachmittag

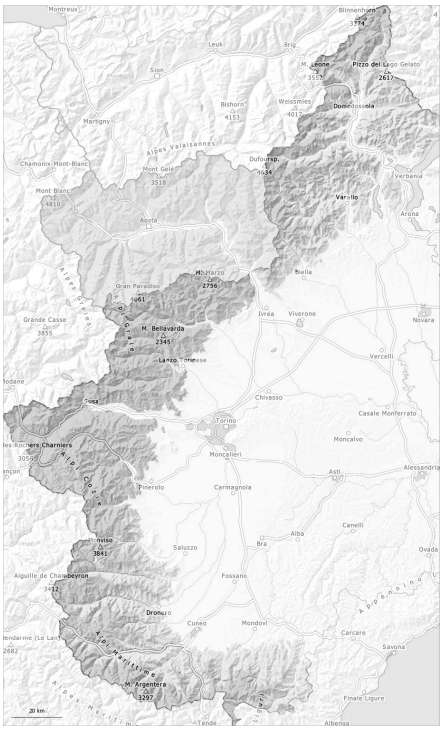

1	2	3	4	5
gering	mäßig	erheblich	groß	sehr groß

Gefahrenstufe 2 - Mäßig

AM:

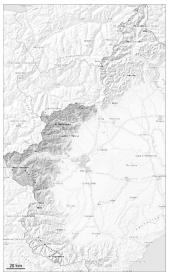

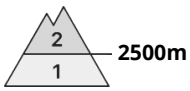

Tendenz: Lawinengefahr bleibt gleich
am Montag, den 02.03.2026

Altschnee

2500m

PM:

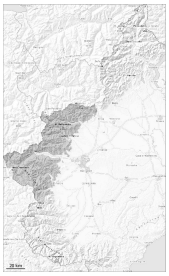

Tendenz: Lawinengefahr bleibt gleich
am Montag, den 02.03.2026

Nassschnee

2200m

Altschnee

2500m

Mit dem Regen steigt die Gefahr von feuchten und nassen Lawinen im Tagesverlauf etwas an.

In tiefen und mittleren Lagen und in tiefen und mittleren Lagen sind mit dem Regen einzelne feuchte und nasse Lawinen möglich.
Feuchte Lawinen können unterhalb von rund 2600 m bis in tiefe Schichten durchreißen und recht groß werden.

Besonders steile Schattenhänge hohe Lagen und Hochgebirge: Schwachschichten im Altschnee können besonders mit großer Zusatzbelastung ausgelöst werden.

Auf der harten Schneeoberfläche besteht Absturzgefahr. Dies besonders v.a. in hohen Lagen und im Hochgebirge.

Schneedecke

Gefahrenmuster gm.10: frühjahrssituation

Die Wetterbedingungen begünstigten eine allmähliche Verfestigung der Schneedecke. Der obere Teil der Schneedecke ist weitgehend stabil, mit einer oft tragfähigen Schmelzharschkruste an der Oberfläche. Besonders steile Schattenhänge hohe Lagen und Hochgebirge: In der Schneedecke sind Schwachschichten vorhanden.

In Gipfellagen liegen je nach Windeinfluss sehr unterschiedliche Schneehöhen.

> In windgeschützten Lagen in allen Höhenlagen liegt für die Jahreszeit viel Schnee.
> Der Regen führt im Tagesverlauf in tiefen und mittleren Lagen zu einer zunehmenden Anfeuchtung der Schneedecke.

Gefahrenstufe 2 - Mäßig

AM:

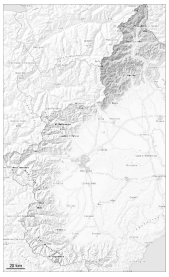

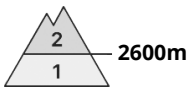

Tendenz: Lawinengefahr bleibt gleich
am Montag, den 02.03.2026

Altschnee

2600m

PM:

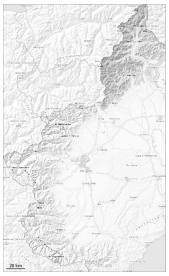

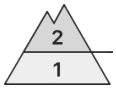

Tendenz: Lawinengefahr bleibt gleich
am Montag, den 02.03.2026

Altschnee

2600m

Allmählicher Rückgang der Gefahr von feuchten und nassen Lawinen mit der Abkühlung.

Die Wetterbedingungen begünstigten eine deutliche Stabilisierung der Schneedecke.
Die spontane Lawinenaktivität nimmt mit der Abkühlung allmählich ab.

Die Lawinen können vor allem an Schattenhängen bis in tiefe Schichten durchreißen und teils mittlere Größe erreichen. Sie können weiterhin vor allem mit großer Belastung ausgelöst werden. Vorsicht vor allem an sehr steilen Hängen und in Kammlagen, Rinnen und Mulden.

Auf der harten Schneeoberfläche besteht Absturzgefahr.

Schneedecke

Gefahrenmuster gm.10: frühjahrssituation | gm.1: bodennahe schwachschicht

In Gipfellagen liegen je nach Windeinfluss sehr unterschiedliche Schneehöhen. Zudem liegt für die Jahreszeit wenig Schnee.

Besonders steile Schattenhänge hohe Lagen und Hochgebirge: In der Altschneedecke sind Schwachschichten vorhanden.
Der obere Teil der Schneedecke ist weitgehend stabil, mit einer oft tragfähigen Schmelzharschkruste an der Oberfläche.

Es fällt lokal etwas Schnee. Der Regen führt im Tagesverlauf vor allem in tiefen Lagen teilweise zu einer leichten Anfeuchtung der Schneedecke.

Gefahrenstufe 2 - Mäßig

AM:

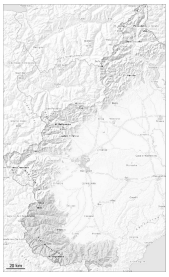

Tendenz: Lawinengefahr nimmt ab
am Montag, den 02.03.2026

PM:

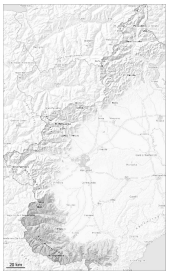

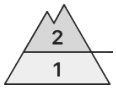

1600m

Tendenz: Lawinengefahr nimmt ab
am Montag, den 02.03.2026

Nassschnee

1600m

Leichter Anstieg der Gefahr von feuchten und nassen Lawinen mit dem Niederschlag.

Mit dem Niederschlag sind im Tagesverlauf weiterhin feuchte und nasse Lawinen möglich. Dies vor allem an Grashängen sowie in tiefen und mittleren Lagen.
Zonen mit Gleitschneerissen sollten gemieden werden.

Auf der harten Schneeoberfläche besteht Absturzgefahr. Dies vor allem an steilen Hängen im Hochgebirge.

Schneedecke

Gefahrenmuster gm.10: frühjahrssituation gm.2: gleitschnee

V.a. in Gipfellagen liegen je nach Windeinfluss sehr unterschiedliche Schneehöhen.

Die Schneeoberfläche ist tragfähig gefroren und.
Der Regen führt im Tagesverlauf zu einer leichten Anfeuchtung der Schneedecke.