Bulletin d'estimation du risque d'avalanche

(valable en dehors des pistes balisées et ouvertes)

MASSIF : Cinto Rotondo

Rédigé le dimanche 1 mars 2026 à 15h

Estimation des risques pour le : LUNDI 02 MARS

AVALANCHES DE NEIGE HUMIDE ET PLAQUES RÉSIDUELLES DANS LA NEIGE VENTÉE EN ALTITUDE

2

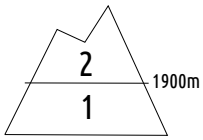

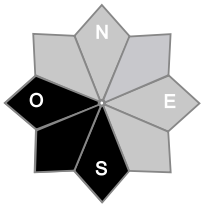

Au-dessus de 1900m indice de risque limité, plus bas indice faible.

Départs spontanés : En neige humide, départs devenant nombreux dans les versants ensoleillés au fil de la journée.

Déclenchements provoqués : Rares structures de plaques en Nord à Nord-Est au-delà de 2000 m.

Indices de risque : 5 très fort - 4 fort - 3 marqué - 2 limité - 1 faible -- En noir : les pentes les plus dangereuses

Stabilité du manteau neigeux

Situation avalancheuse typique : neige humide

Départs spontanés : Avec un regel nocturne réservé uniquement aux très hautes altitudes, l'humidification du manteau se poursuit dans les versants Sud et gagne davantage en profondeur. Après quelques heures de soleil et des températures assez douces en versants occidentaux, des coulées et avalanches de neige humide sont à attendre dans les pentes Sud à Ouest raides. Avalanches de taille petite à moyenne (taille 1 à 2), voire grande (taille 3) où le manteau neigeux s'est déjà bien humidifié en profondeur ou suite à la rupture d'une corniche.

Déclenchements provoqués : Quelques structures de plaques sont encore présentes dans la neige récente ventée, surtout dans les pentes orientées Nord à Est où persistent des couches fragiles (souvent de la neige roulée). Ces plaques se stabilisent progressivement ; elles peuvent surtout être déclenchées par une forte surcharge, plus rarement au passage d'un seul skieur ou randonneur. Déclenchements également faciles au passage d'un skieur ou randonneur de petites avalanches de neige humide dans les versants Sud à Sud-Ouest l'après-midi.

Qualité de la neige

Qualification de l'enneigement : L'enneigement est excellent pour la saison au-dessus de 1600 m. Sur la Maniccia, à 2400 m d'altitude dans le massif du Rotondo, on mesure 2m83 de hauteur totale de neige.

Limite d'enneigement skiable : autour de 1500 m.

État de la neige : En versants ensoleillés, manteau neigeux printanier jusqu'à haute altitude, neige dense, fine croûte cassante le matin. L'après-midi, elle sera généralement pourrie sous 1800/2000 m mais souvent suffisamment dense pour être portante au-dessus.
En Nord, sous 2000 m, neige plus mate, également densifiée au petit matin, ramollissant lentement en cours de journée et juste en surface. Au-dessus de 2000/2200 m, neige restant dure/cartonnée surtout en approchant des sommets avec un peu de vieille poudreuse dans les zones abritées. **Neige parfois glacée** dans les zones érodées par les forts vents.
À noter une neige colorée par endroits et des **corniches parfois volumineuses**.

Aperçu météo pour le lundi 02 mars

	nuit	matin	après-midi	soir
Temps peu nuageux en versants occidentaux, plus chargé en versants Est.				
Pluie-Neige				
Iso 0 °C	2 400 m	2 400 m	2 400 m	2 400 m
Vent 1500 m	10 km/h	15 km/h	20 km/h	10 km/h
Vent 3000 m	15 km/h	25 km/h	25 km/h	15 km/h

Épaisseur de neige hors-piste

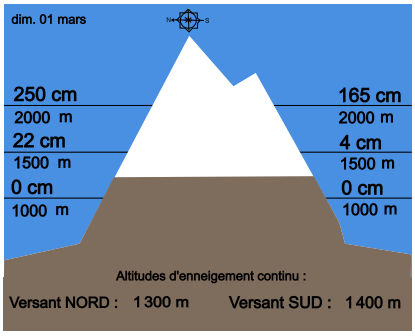

Précipitations à 1800 m

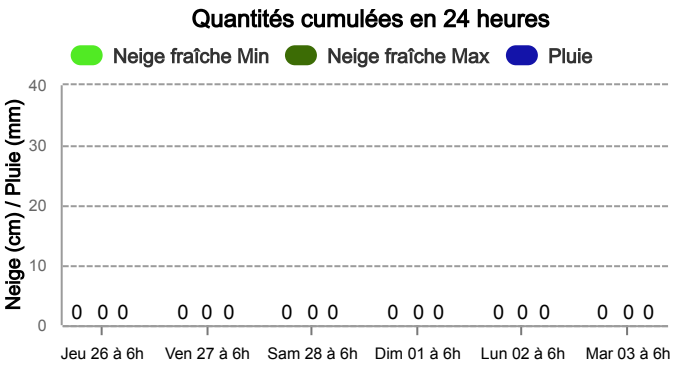

Tendance du mardi 03 mars

2

Indice de risque limité

Quelques départs dans les pentes raides exposées. Tendance du risque stationnaire.

Pour consulter la vigilance en cours, veuillez vous rendre sur le site https://vigilance.meteofrance.fr/fr

Météo-France - 73 avenue de Paris, 94165 Saint-Mandé cedex - Contact : contact@meteo.fr

Rédigé par Météo-France avec la contribution des observateurs du réseau nivo-météorologiques. Partenariat : ANMSM (Maires de Stations de Montagne), DSF (Domaines Skiables de France), ADSP (Directeurs de Pistes et de la Sécurité des Stations de Sports d'Hiver) et autres acteurs de la montagne.

Bulletin neige & avalanches par téléphone au 0 892 68 10 20 Service 0,35 € / min + prix appel

RÉPUBLIQUE FRANÇAISE
Liberté Égalité Fraternité

METEO FRANCE
À VOS CÔTÉS, DANS UN CLIMAT QUI CHANGE

Bulletin d'estimation du risque d'avalanche

(valable en dehors des pistes balisées et ouvertes)

MASSIF : Cinto Rotondo

Rédigé le dimanche 1 mars 2026 à 15h

Conditions nivo-météo des 7 derniers jours

	lun. 23/02				mar. 24/02				mer. 25/02				jeu. 26/02				ven. 27/02				sam. 28/02				dim. 01/03			
	03h	09h	15h	21h	03h	09h	15h	21h	03h	09h	15h	21h	03h	09h	15h	21h	03h	09h	15h	21h	03h	09h	15h	21h	03h	09h	15h	21h
Météo																												
Vent (km/h)	80	80	70	60	40	35	30	20	5	5	5	5	10	15	15	15	20	15	15	15	10	5	10	10	10	10	10	10
à 3000m																												
Vent (km/h)	60	50	40	30	25	20	10	5	5	5	10	5	5	5	5	5	10	10	10	5	5	5	10	5	5	5	10	5
à 1500m																												

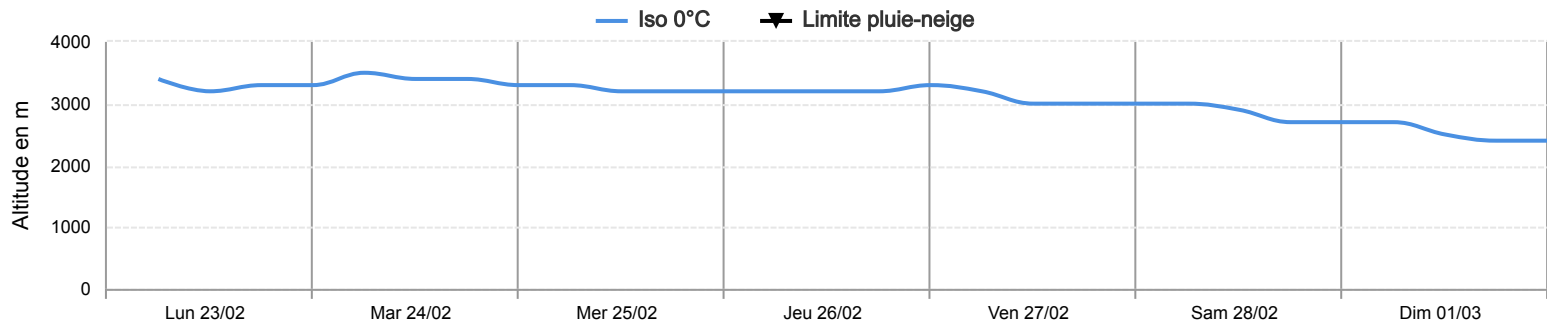

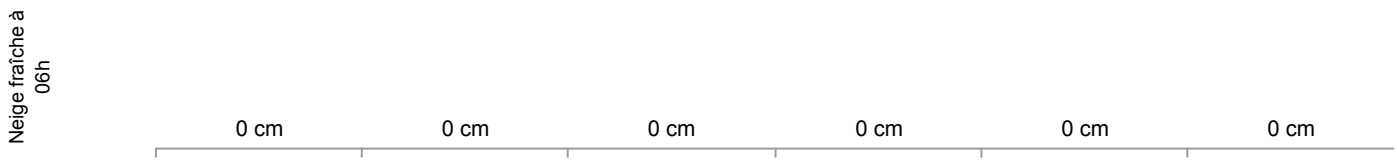

Risque d'avalanche	lun. 23/02	mar. 24/02	mer. 25/02	jeu. 26/02	ven. 27/02	sam. 28/02	dim. 01/03
	2	2	2	2	2	2	2

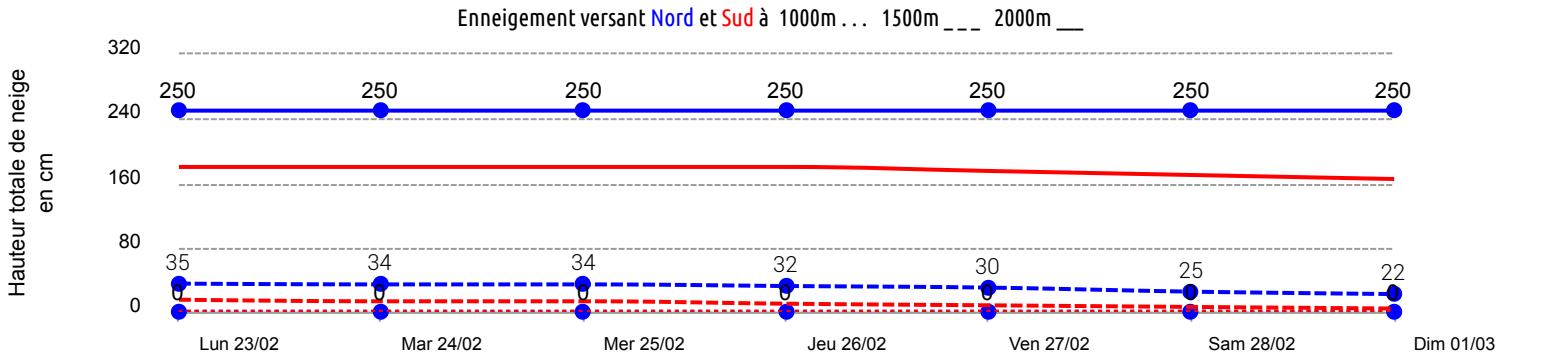

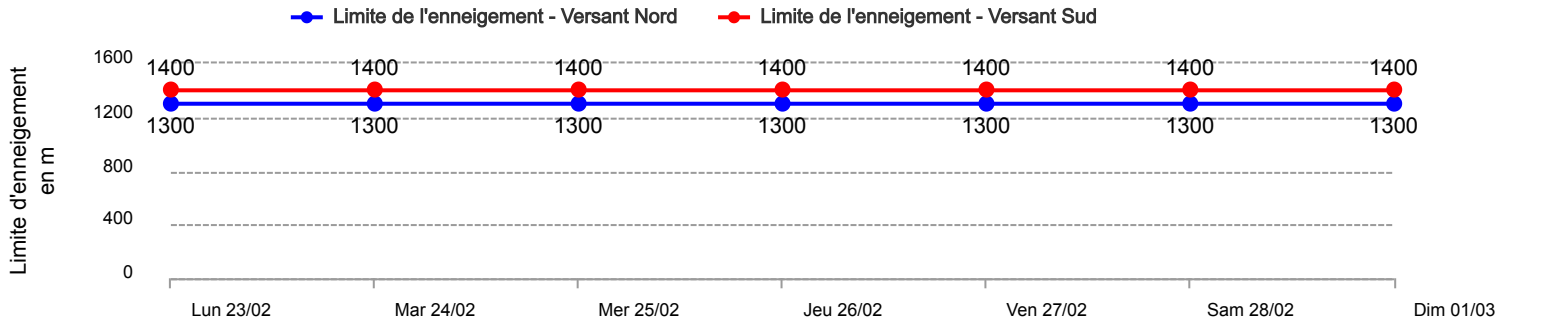

Pour consulter la vigilance en cours, veuillez vous rendre sur le site https://vigilance.meteofrance.fr/fr

Météo-France - 73 avenue de Paris, 94165 Saint-Mandé cedex - Contact : contact@meteo.fr

Rédigé par Météo-France avec la contribution des observateurs du réseau nivo-météorologiques. Partenariat : ANMSM (Maires de Stations de Montagne), DSF (Domaines Skiables de France), ADSP (Directeurs de Pistes et de la Sécurité des Stations de Sports d'Hiver) et autres acteurs de la montagne.

Bulletin neige & avalanches par téléphone au
0 892 68 10 20 Service 0,35 € / min + prix appel