Bulletin d'estimation du risque d'avalanche
(valable en dehors des pistes balisées et ouvertes)

MASSIF : Aravis

Rédigé le dimanche 1 mars 2026 à 16h

Estimation des risques pour le : LUNDI 02 MARS

MANTEAU NEIGEUX QUI SE RÉCHAUFFE AU FIL DE LA JOURNÉE.

2

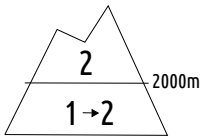

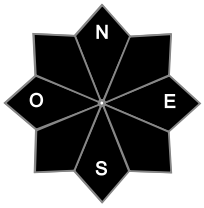

Au-dessus de 2000m indice de risque limité, plus bas indice faible évoluant en limité.

Départs spontanés : Départs humides et plaques de fond.

Déclenchements provoqués : Neige humide au fil du réchauffement diurne.

Indices de risque : 5 très fort - 4 fort - 3 marqué - 2 limité - 1 faible -- En noir : les pentes les plus dangereuses

Stabilité du manteau neigeux

Situation avalancheuse typique : neige humide — avalanches de fond

Départs spontanés :
* Au fil du réchauffement diurne : de plus en plus de départs dans la **neige humide**. Possibles en tous versants et à toute altitude, mais majoritairement dans les pentes ensoleillées. Départs ponctuels souvent dans les pentes raides et vers les rochers/falaises. Départs en plaques possibles en cascade. Taille 2 (moyenne), rarement 3 (grande).
* En tous versants : **plaques de fond**. Départs dans les pentes raides et lisses (pentes herbeuses, dalles rocheuses). Départs possibles à toute heure du jour ou de la nuit. Taille 2 (moyenne), rarement 3 (grande). Plus nombreuses au fil du réchauffement.
* Chutes de **corniches**, épaisses et volumineuses. Leurs chutes peuvent déclencher une plaque en contrebas.

Déclenchements provoqués :
* En tous versants mais principalement dans les versants au soleil : de la **neige humide** peut couler sous les skis au fil du réchauffement diurne. Taille 1 (petite) à 2 (moyenne).
* Au-dessus de 2000 m en versants E/N/O : Présence d'une **couche fragile persistante enfouie.** Difficile à déclencher mais elle peut être **sollicitée en cascade** et donner une avalanche de plus grande ampleur (cassure de 60cm/1m). La profondeur de l'enfouissement de la couche fragile varie énormément, même dans une même pente. Taille 3 (grande).

Qualité de la neige

Enneigement : bon pour la période. On peut chausser les skis vers 1200/1300 m en versants E/N/O et 1400/1500 m en versants Sud. Les corniches sont volumineuses et menaçantes. Les arêtes et les crêtes sont érodées par le vent de SW à NW.

Qualité de la neige lundi :
* Regel nocturne efficace.
* En dessous de 2000 m : Le matin, la neige est dure regelée. Au fil du réchauffement diurne, elle devient lourde et humide. Enfoncement piéton important.
* Au-dessus de 2000 m : dans les versants E/S/O, croûte de regel en surface, peu portante, même à ski. Elle se ramollit rapidement au fil de la journée. Dans les versants N, la neige est restée assez froide mais elle est tassée.

Aperçu météo pour le lundi 02 mars

nuit	matin	après-midi	soir

Belle journée ensoleillée. L'après-midi quelques cumulus se forment dans le massif. Doux.

Pluie-Neige				
Iso 0 °C	2 000 m	2 100 m	2 200 m	2 200 m
Vent 2000 m	20 km/h	20 km/h	20 km/h	10 km/h
Vent 2500 m	25 km/h	25 km/h	25 km/h	15 km/h

Épaisseur de neige hors-piste

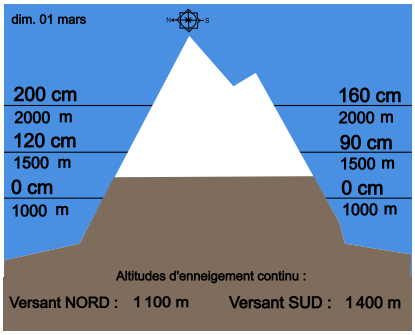

Précipitations à 1800 m

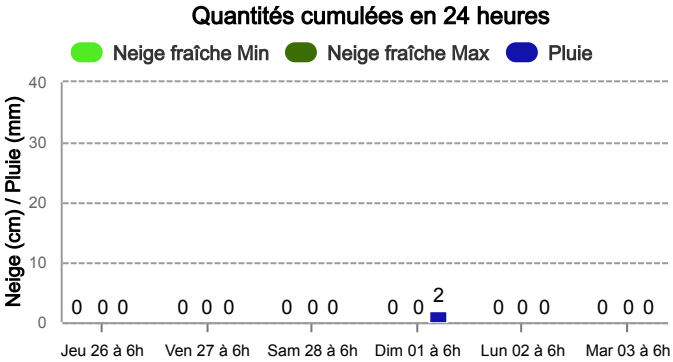

Tendance du mardi 03 mars

2

Indice de risque limité

Bon regel nocturne. La surface de la neige se réchauffe et se ramollit rapidement au soleil. La journée est ensoleillée et douce. Isotherme 0°C vers 2300 m.

Pour consulter la vigilance en cours, veuillez vous rendre sur le site https://vigilance.meteofrance.fr/fr

Météo-France - 73 avenue de Paris, 94165 Saint-Mandé cedex - Contact : contact@meteo.fr

Rédigé par Météo-France avec la contribution des observateurs du réseau nivo-météorologiques. Partenariat : ANMSM (Maires de Stations de Montagne), DSF (Domaines Skiables de France), ADSP (Directeurs de Pistes et de la Sécurité des Stations de Sports d'Hiver) et autres acteurs de la montagne.

Bulletin neige & avalanches par téléphone au
0 892 68 10 20 Service 0,35 € / min + prix appel

RÉPUBLIQUE FRANÇAISE
Liberté Égalité Fraternité

METEO FRANCE
À VOS CÔTÉS, DANS UN CLIMAT QUI CHANGE

Bulletin d'estimation du risque d'avalanche
(valable en dehors des pistes balisées et ouvertes)

MASSIF : Aravis

Rédigé le dimanche 1 mars 2026 à 16h

Conditions nivo-météo des 7 derniers jours

	lun. 23/02				mar. 24/02				mer. 25/02				jeu. 26/02				ven. 27/02				sam. 28/02				dim. 01/03			
	03h	09h	15h	21h	03h	09h	15h	21h	03h	09h	15h	21h	03h	09h	15h	21h	03h	09h	15h	21h	03h	09h	15h	21h	03h	09h	15h	21h
Météo																												
Vent (km/h)	30	20	20	25	25	25	15	15	15	15	20	20	10	10	15	15	15	15	15	25	30	35	20	15	20	20	20	25
à 2500m																												
Vent (km/h)	20	10	15	15	15	15	10	10	10	10	10	10	5	5	10	10	10	10	10	20	20	25	15	5	10	10	10	20
à 2000m																												

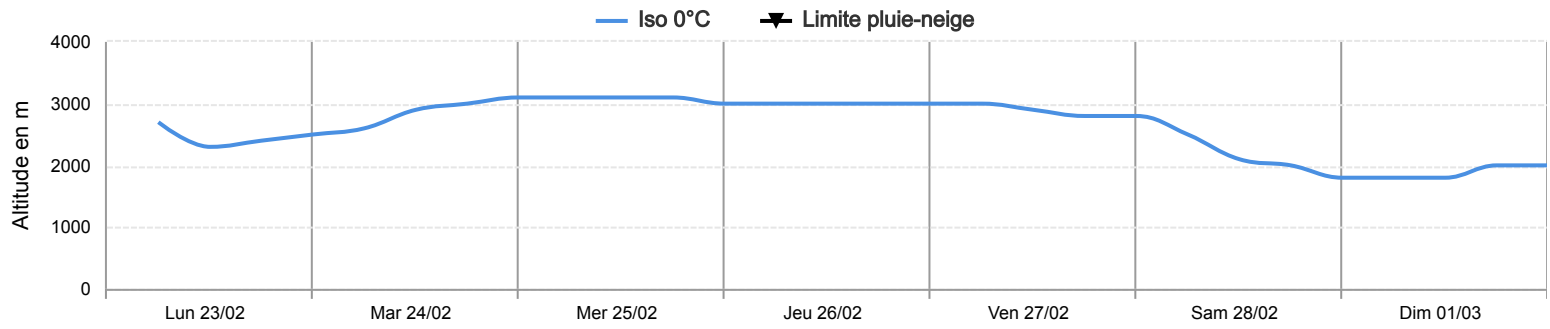

Neige fraîche à 06h

Lun 23/02	Mar 24/02	Mer 25/02	Jeu 26/02	Ven 27/02	Sam 28/02
0 cm	0 cm	0 cm	0 cm	0 cm	0 cm

Risque d'avalanche	lun. 23/02	mar. 24/02	mer. 25/02	jeu. 26/02	ven. 27/02	sam. 28/02	dim. 01/03
	2	3	3	3	3	2	2

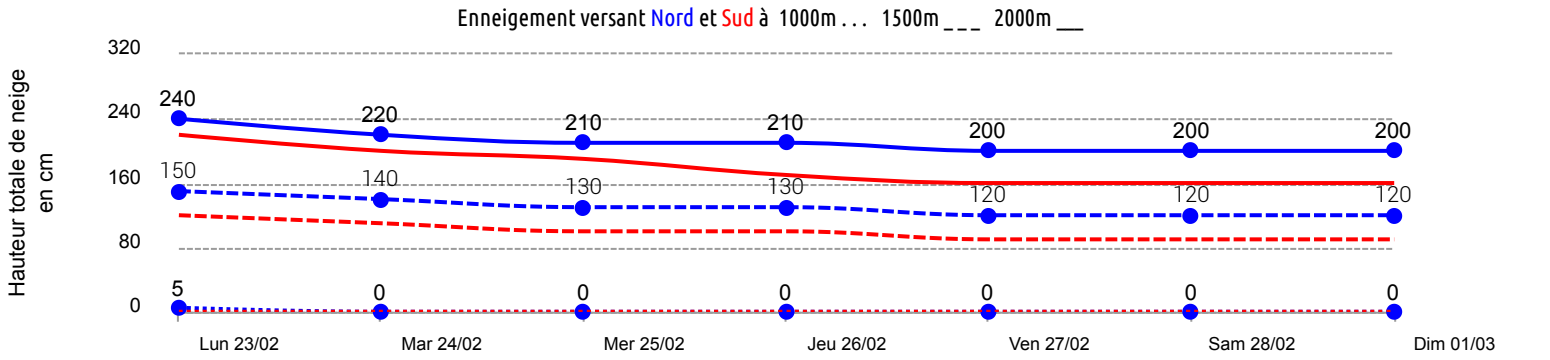

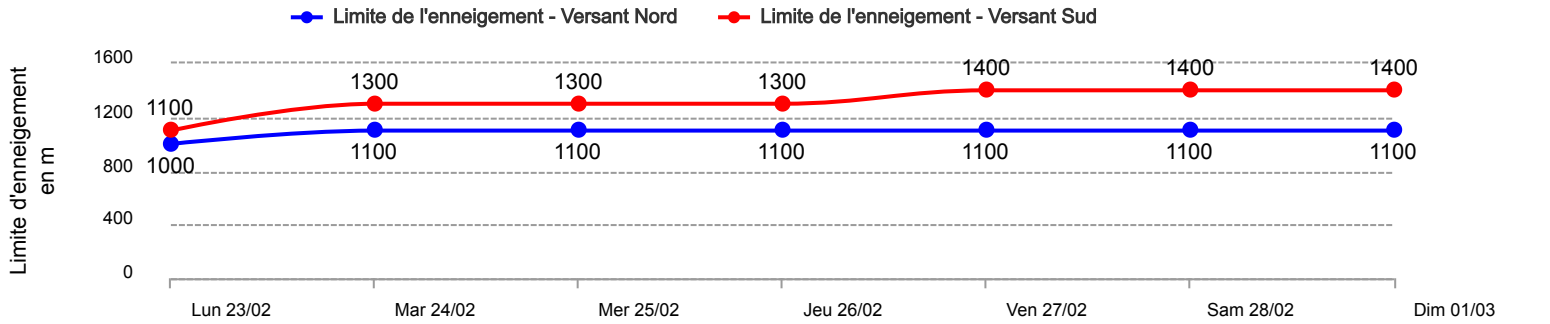

Pour consulter la vigilance en cours, veuillez vous rendre sur le site https://vigilance.meteofrance.fr/fr

Météo-France - 73 avenue de Paris, 94165 Saint-Mandé cedex - Contact : contact@meteo.fr

Rédigé par Météo-France avec la contribution des observateurs du réseau nivo-météorologiques. Partenariat : ANMSM (Maires de Stations de Montagne), DSF (Domaines Skiables de France), ADSP (Directeurs de Pistes et de la Sécurité des Stations de Sports d'Hiver) et autres acteurs de la montagne.

Bulletin neige & avalanches par téléphone au
0 892 68 10 20 Service 0,35 € / min + prix appel