Bulletin d'estimation du risque d'avalanche
(valable en dehors des pistes balisées et ouvertes)

MASSIF : Couserans

Rédigé le dimanche 1 mars 2026 à 16h

Estimation des risques pour le : LUNDI 02 MARS

PRINTANIER DANS LES VERSANTS AU SOLEIL ET QUELQUES STRUCTURES DE PLAQUES EN NORD D'ALTITUDE.

2

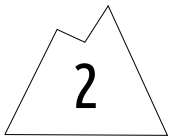

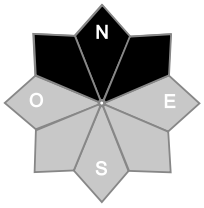

plaques en altitude

Indices de risque : 5 très fort - 4 fort - 3 marqué - 2 limité - 1 faible -- En noir : les pentes les plus dangereuses

Indice de risque limité.

Départs spontanés : Reptations épaisses présentes et humidification au soleil

Déclenchements provoqués : Sturctures de plaques encore présentes en nord d'altitude

Stabilité du manteau neigeux

Situation avalancheuse typique :

avalanches de fond

couche fragile persistante

Départs spontanés :
De rares, mais parfois épaisses plaques de fond peuvent se produire à tout moment en mobilisant des quantités conséquentes de neige lourde. Il est fait état, dans de nombreuses orientations et plutôt sous 2200 m, de larges fissures visibles (gueules de baleine) dans des pentes au sol lisse, signes avant-coureurs de telles avalanches.
Sinon, reprise de l'activité avalancheuse en neige humide avec le soleil, dans les pentes raides encore non purgées et à proximité des rochers, avec des avalanches ponctuelles restant de taille modeste.

Déclenchements provoqués :
Quelques avalanches de plaques sont encore possiblement déclenchables au passage d'un skieur, au-dessus de 2100/2200 m dans les secteurs restés en neige froide, donc plutôt orientés nord. Ces plaques sont assez fines (10/20 cm). Elles gagnent en épaisseur en altitude et deviennent alors de plus en plus difficilement déclenchables.
Observables : neige travaillée par le vent en surface, couche de neige sans cohésion à 15/30 cm de la surface, une rapide coupe du manteau en surface peut suffire à identifier ces couches fragiles.

Autre: La neige a pris des allures printanières dans de nombreux secteurs avec un risque accru de glissade sur de la neige dure ou glacée en matinée après un bon regel nocturne, parfois encore plus tardivement en versant ouest.

Qualité de la neige

Enneigement :
L'enneigement est bien excédentaire après les nombreuses perturbations neigeuses depuis le début d'année. Les vallons ombragés sont encore bien enneigés avec des quantités de neige importantes dès 1400 m notamment en versant Est. Les précipitations de samedi ont été anecdotiques et la neige reprend un cycle printanier de gel/dégel au soleil.
La limite skiable est autour de 1400 à 1600m plein Sud alors que certaines vallées ombragées sont encore enneigées dès 1200 à 1300 m.

Qualité de la neige :
Lundi matin, bon regel nocturne des pentes humidifiées dimanche avec une neige dure et portante (sauf en forêt sous le couvert des arbres). En journée, reprise de l'humidification au soleil avec une neige devenant lourde et humide à basse altitude. En altitude, à partir de 2100/2200 m, rarement plus bas, on trouvera encore de la neige restée sèche en poudre maintenant dense dans les pentes abritées du vent. Par contre, les crêtes et sommets sont souvent pelés et en neige dure en versants Ouest.

Aperçu météo pour le lundi 02 mars

nuit	matin	après-midi	soir

Belle journée ensoleillée avec toutefois un renforcement du vent de sud sur les crêtes et sommets, notamment frontaliers, jusqu'à la mi-journée.

Pluie-Neige				
Iso 0 °C	2 500 m	2 700 m	2 600 m	2 700 m
Vent 2000 m	↑ 35 km/h	↑ 40 km/h	↑ 35 km/h	↑ 30 km/h
Vent 3000 m	↑ 40 km/h	↑ 50 km/h	↑ 50 km/h	↑ 40 km/h

Épaisseur de neige hors-piste

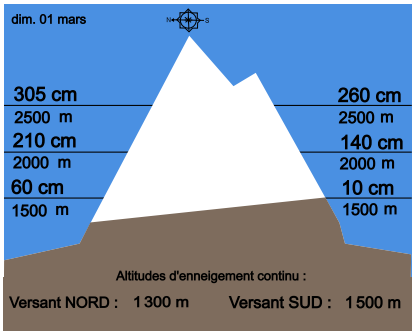

Précipitations à 1800 m

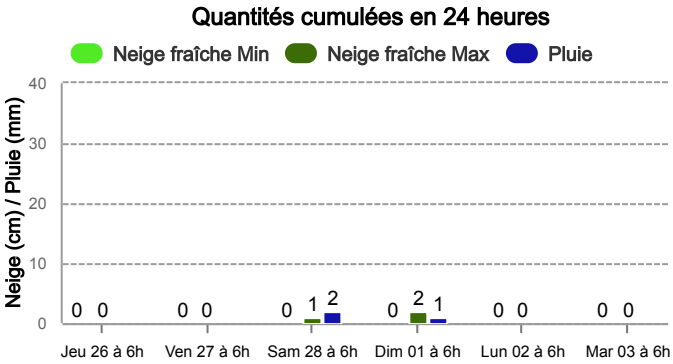

Tendance du mardi 03 mars

2

Indice de risque limité

Stationnaire pour le risque d'avalanche. Par contre des poussières désertiques remontent du Sud avec des concentrations plus importantes mardi.

Pour consulter la vigilance en cours, veuillez vous rendre sur le site https://vigilance.meteofrance.fr/fr

Météo-France - 73 avenue de Paris, 94165 Saint-Mandé cedex - Contact : contact@meteo.fr

Rédigé par Météo-France avec la contribution des observateurs du réseau nivo-météorologiques. Partenariat : ANMSM (Maires de Stations de Montagne), DSF (Domaines Skiables de France), ADSP (Directeurs de Pistes et de la Sécurité des Stations de Sports d'Hiver) et autres acteurs de la montagne.

Bulletin neige & avalanches par téléphone au
0 892 68 10 20 Service 0,35 € / min + prix appel

RÉPUBLIQUE FRANÇAISE
Liberté Égalité Fraternité

METEO FRANCE
À VOS CÔTÉS, DANS UN CLIMAT QUI CHANGE

Bulletin d'estimation du risque d'avalanche
(valable en dehors des pistes balisées et ouvertes)

MASSIF : Couserans

Rédigé le dimanche 1 mars 2026 à 16h

Conditions nivo-météo des 7 derniers jours

	lun. 23/02				mar. 24/02				mer. 25/02				jeu. 26/02				ven. 27/02				sam. 28/02				dim. 01/03			
	03h	09h	15h	21h	03h	09h	15h	21h	03h	09h	15h	21h	03h	09h	15h	21h	03h	09h	15h	21h	03h	09h	15h	21h	03h	09h	15h	21h
Météo																												
Vent (km/h)	15	15	15	15	20	20	20	20	20	25	25	20	20	15	15	15	20	20	25	30	25	20	20	15	20	30	35	40
à 3000m	↓	↓	↓	↓	↗	↑	↑	↑	→	↘	↘	↘	↘	↘	↘	↘	↘	→	↗	↗	↑	↖	↙	↙	↑	↑	↑	↑
Vent (km/h)	10	10	10	10	10	10	10	10	15	15	15	10	10	10	10	10	15	15	15	20	10	10	15	5	10	15	20	30
à 2000m	↗	→	→	↑	↑	↑	↑	↗	→	↘	↘	↘	↘	↘	↘	↘	↘	→	↗	↗	→	↘	↙	↙	↙	↑	↗	↑

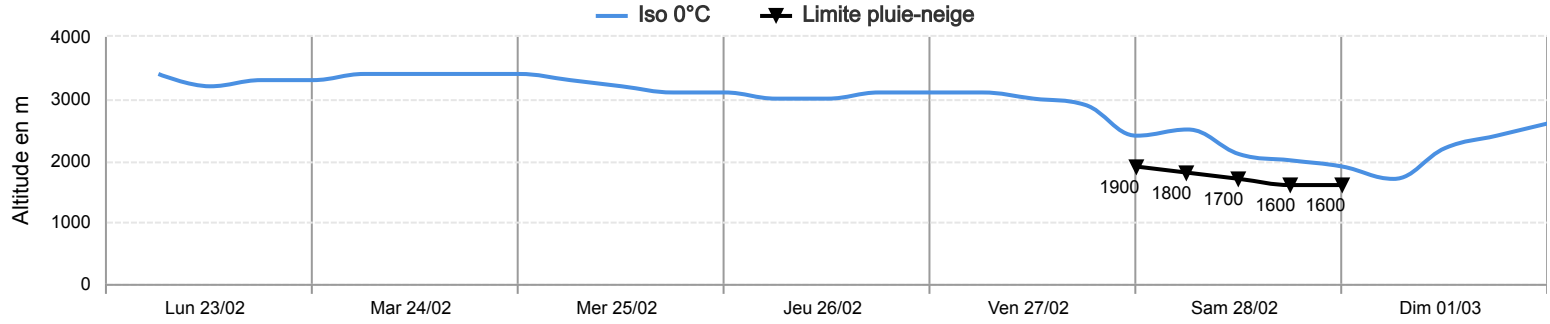

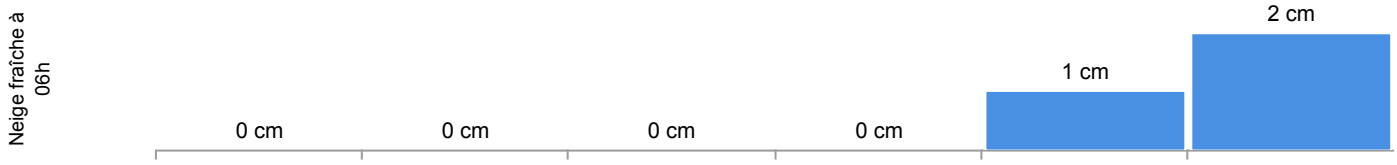

Risque d'avalanche	lun. 23/02	mar. 24/02	mer. 25/02	jeu. 26/02	ven. 27/02	sam. 28/02	dim. 01/03
	3	2	2	2	2	2	2

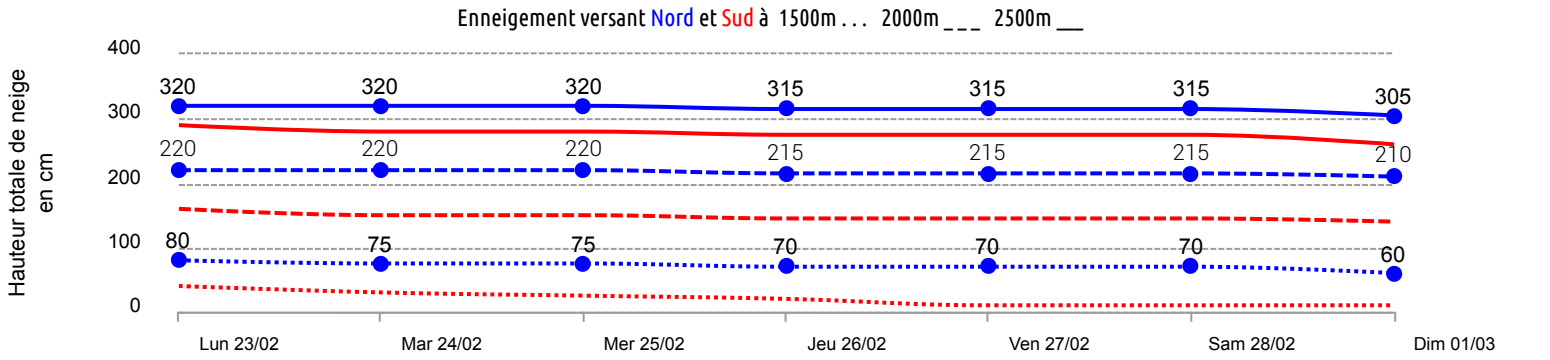

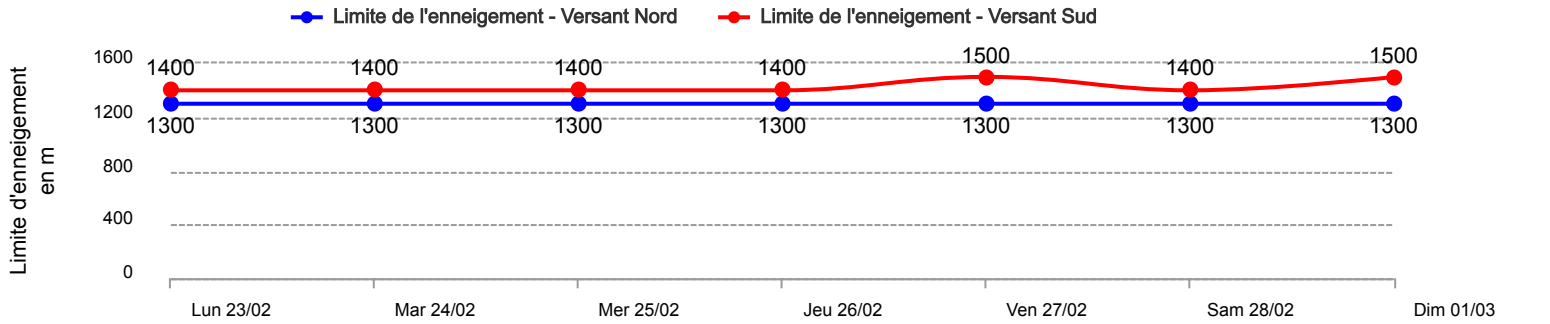

Pour consulter la vigilance en cours, veuillez vous rendre sur le site https://vigilance.meteofrance.fr/fr

Météo-France - 73 avenue de Paris, 94165 Saint-Mandé cedex - Contact : contact@meteo.fr

Rédigé par Météo-France avec la contribution des observateurs du réseau nivo-météorologiques. Partenariat : ANMSM (Maires de Stations de Montagne), DSF (Domaines Skiables de France), ADSP (Directeurs de Pistes et de la Sécurité des Stations de Sports d'Hiver) et autres acteurs de la montagne.

Bulletin neige & avalanches par téléphone au

0 892 68 10 20 Service 0,35 € / min + prix appel