Bulletin d'estimation du risque d'avalanche

(valable en dehors des pistes balisées et ouvertes)

MASSIF : Haut-Var Haut-Verdon

Rédigé le dimanche 1 mars 2026 à 16h

Estimation des risques pour le : LUNDI 02 MARS

PLAQUES ÉPAISSES DIFFICILES À DÉCLENCHER EN UBACS D'ALTITUDE - QUELQUES DÉPARTS EN NEIGE HUMIDE

2

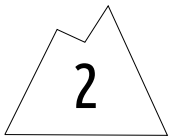

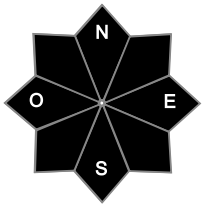

Indice de risque limité.

Départs spontanés : quelques avalanches de fond, quelques départs superficiels en neige humide.

Déclenchements provoqués : plaques épaisses en ubacs d'altitude, difficiles à déclencher.

Indices de risque : 5 très fort - 4 fort - 3 marqué - 2 limité - 1 faible -- En noir : les pentes les plus dangereuses

Stabilité du manteau neigeux

Situation avalancheuse typique :

couche fragile persistante

avalanches de fond

Déclenchements provoqués :

- **plaques localement épaisses sur couche fragile persistante enfouie** encore présentes **plutôt sur le Haut-Verdon** dans les orientations ouest / nord / est au-dessus de 2000/2200 m, non exclue à haute altitude dans les orientations sud. Déclenchement difficile au passage d'un skieur, mais restant localement possible là où le manteau neigeux est moins épais (croupes, bords de couloir), ou en cascade après un premier départ en surface. Avalanche de grande taille, cassure épaisse et large. Danger difficile à détecter.
- **en neige humide**. Un skieur peut favoriser un départ superficiel en neige fortement humidifiée en pente raide ensoleillée, généralement de petite taille.

Départs spontanés :

- **quelques avalanches de fond** suite à la rupture de reptations (gueules de baleine). Taille moyenne, voire grande. Possibles à n'importe quel moment du jour et de la nuit. En versant sud, plutôt en dessous de 2500/2700 m. En versant nord, plutôt en dessous de 2000 m.
- un rare départ en **neige humide** reste possible, mais devient rare et reste superficiel. Départs ponctuels de petite taille, rarement moyenne, dans les orientations est / sud / ouest.

Qualité de la neige

Enneigement excédentaire pour un début mars.
Données observées : 64 cm à Valberg à 1780 m, 140/150 cm vers 2000 m dans le Haut-Verdon.

Enneigement skiable dès 1400/1500 m en terrains favorables, 1600/1700 m en adrets.

État de la neige en surface : croute souvent portante le matin après un bon regel nocturne, s'humidifiant en journée au fil de l'ensoleillement. En ubacs au-dessus de 1800/2000 m environ, neige froide souvent travaillée/durcie par le vent de nord. Zones dégarnies proches des crêtes, alternant avec des corniches parfois épaisses.

Aperçu météo pour le lundi 02 mars

nuit	matin	après-midi	soir

Temps plutôt lumineux, mais l'ensoleillement est localement contrarié par quelques passages nuageux accrochant le relief.

Pluie-Neige				
Iso 0 °C	1 900 m	1 800 m	2 000 m	2 100 m
Vent 2000 m	← 10 km/h	↖ 10 km/h	← 15 km/h	← 10 km/h
Vent 3000 m	↖ 15 km/h	↖ 20 km/h	↖ 15 km/h	← 15 km/h

Épaisseur de neige hors-piste

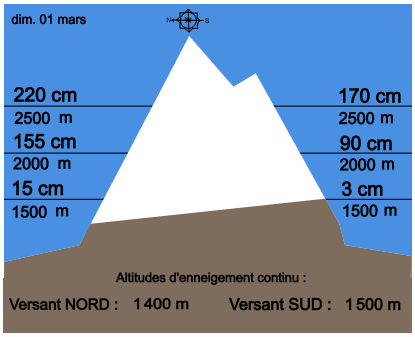

Précipitations à 1800 m

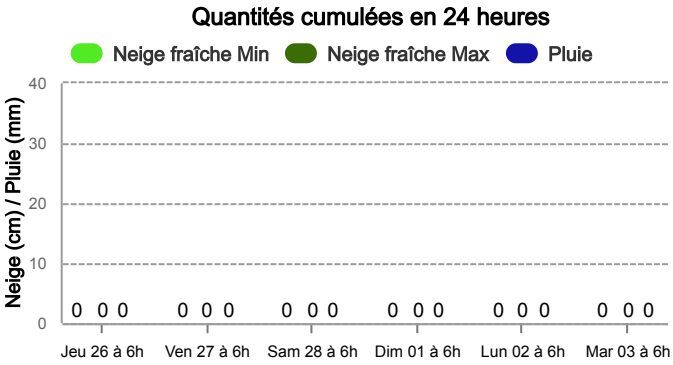

Tendance du mardi 03 mars

2

Indice de risque limité

Maintien d'un risque limité. Quelques départs en neige humide restent possibles.

Pour consulter la vigilance en cours, veuillez vous rendre sur le site https://vigilance.meteofrance.fr/fr

Météo-France - 73 avenue de Paris, 94165 Saint-Mandé cedex - Contact : contact@meteo.fr

Rédigé par Météo-France avec la contribution des observateurs du réseau nivo-météorologiques. Partenariat : ANMSM (Maires de Stations de Montagne), DSF (Domaines Skiables de France), ADSP (Directeurs de Pistes et de la Sécurité des Stations de Sports d'Hiver) et autres acteurs de la montagne.

Bulletin neige & avalanches par téléphone au

0 892 68 10 20 Service 0,35 € / min + prix appel

RÉPUBLIQUE FRANÇAISE
Liberté Égalité Fraternité

METEO FRANCE
À VOS CÔTÉS, DANS UN CLIMAT QUI CHANGE

Bulletin d'estimation du risque d'avalanche

(valable en dehors des pistes balisées et ouvertes)

MASSIF : Haut-Var Haut-Verdon

Rédigé le dimanche 1 mars 2026 à 16h

Conditions nivo-météo des 7 derniers jours

	lun. 23/02				mar. 24/02				mer. 25/02				jeu. 26/02				ven. 27/02				sam. 28/02				dim. 01/03			
	03h	09h	15h	21h	03h	09h	15h	21h	03h	09h	15h	21h	03h	09h	15h	21h	03h	09h	15h	21h	03h	09h	15h	21h	03h	09h	15h	21h
Météo																												
Vent (km/h)	45	40	30	25	35	25	10	10	15	10	10	10	10	10	10	10	10	10	10	10	10	15	20	15	20	15	20	25
à 3000m																												
Vent (km/h)	30	30	25	15	15	10	5	5	10	5	5	5	5	5	5	5	5	5	5	5	5	5	10	5	5	5	15	10
à 2000m																												

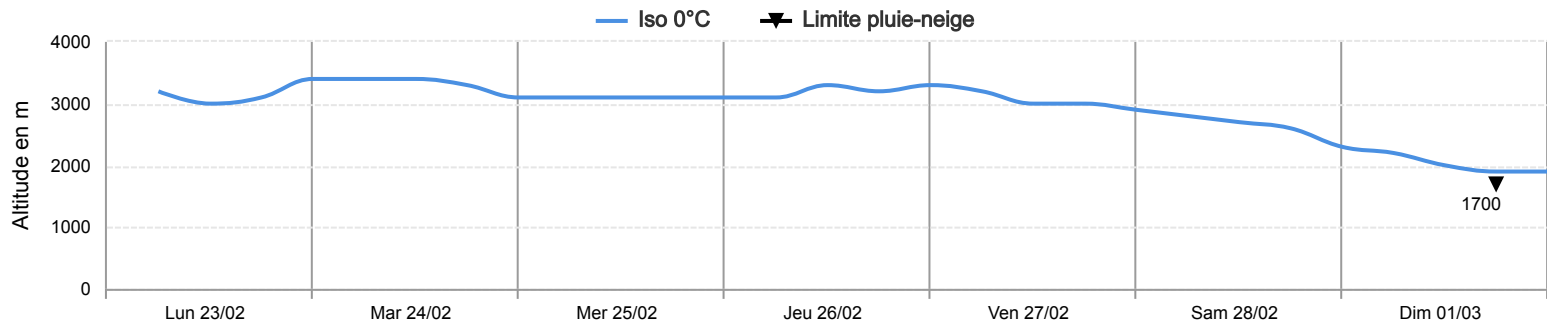

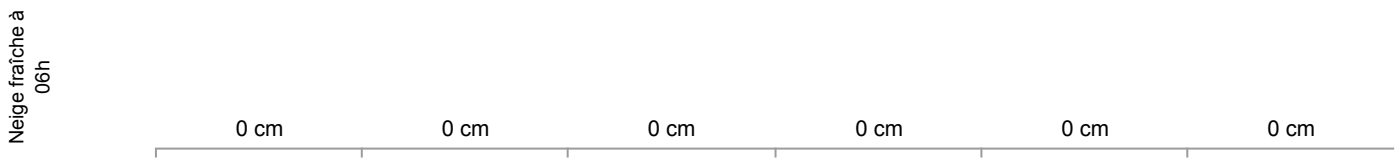

Risque d'avalanche	lun. 23/02	mar. 24/02	mer. 25/02	jeu. 26/02	ven. 27/02	sam. 28/02	dim. 01/03
	3	3	3	3	2	2	2

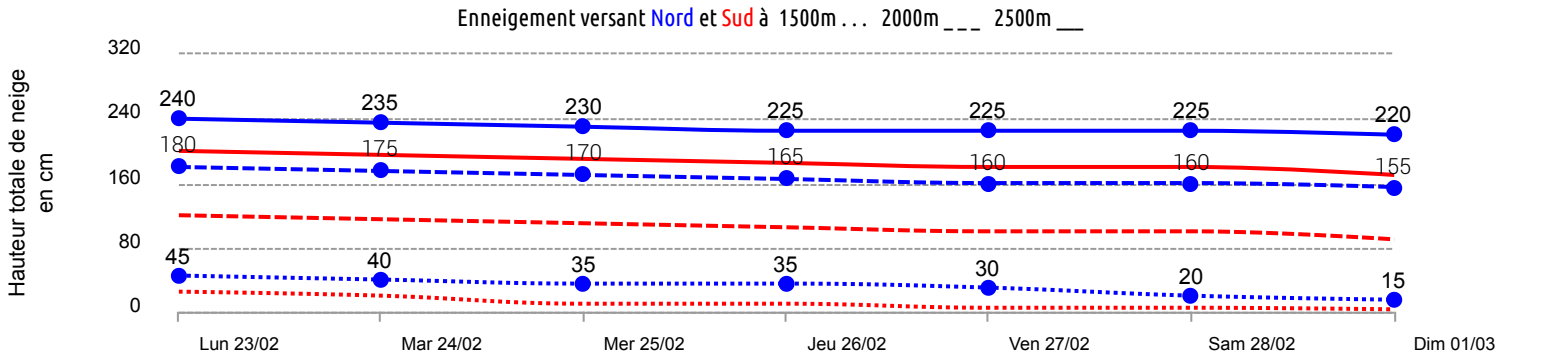

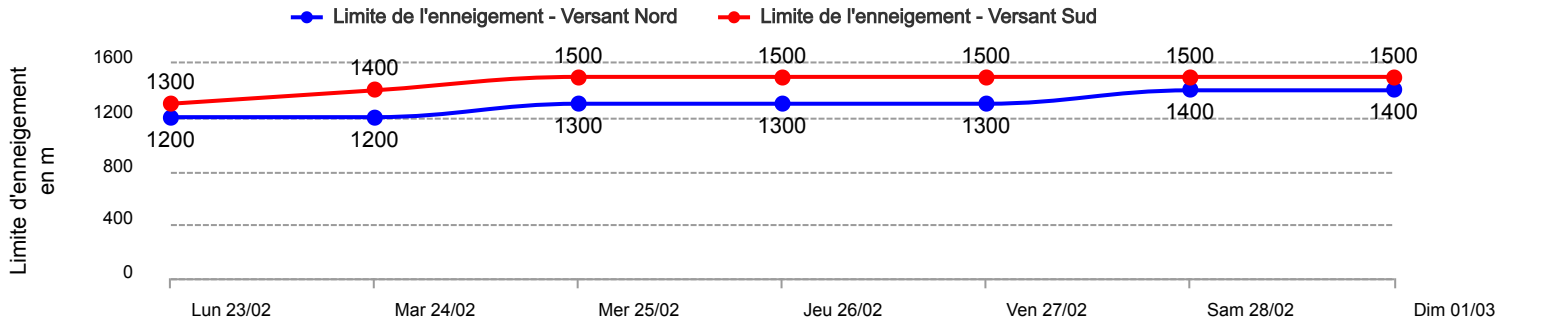

Pour consulter la vigilance en cours, veuillez vous rendre sur le site https://vigilance.meteofrance.fr/fr

Météo-France - 73 avenue de Paris, 94165 Saint-Mandé cedex - Contact : contact@meteo.fr

Rédigé par Météo-France avec la contribution des observateurs du réseau nivo-météorologiques. Partenariat : ANMSM (Maires de Stations de Montagne), DSF (Domaines Skiables de France), ADSP (Directeurs de Pistes et de la Sécurité des Stations de Sports d'Hiver) et autres acteurs de la montagne.

Bulletin neige & avalanches par téléphone au
0 892 68 10 20 Service 0,35 € / min + prix appel