Bulletin d'estimation du risque d'avalanche

(valable en dehors des pistes balisées et ouvertes)

MASSIF : Haute-Bigorre

Rédigé le dimanche 1 mars 2026 à 16h

Estimation des risques pour le : LUNDI 02 MARS

STRUCTURES DE PLAQUES ENCORE POSSIBLES À L'OMBRE EN ALTITUDE.

2

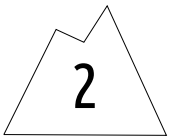

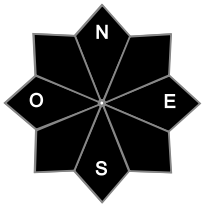

Avalanches de fond.

Indice de risque limité.

Départs spontanés : AVALANCHES de GLISSEMENT (DE FOND)

Déclenchements provoqués : PLAQUES PERSISTANTS EN SECTEURS OMBRÉS D'ALTITUDE

Indices de risque : 5 très fort - 4 fort - 3 marqué - 2 limité - 1 faible -- En noir : les pentes les plus dangereuses

Stabilité du manteau neigeux

Situation avalancheuse typique : avalanches de fond neige humide

Déclenchements provoqués : **Au-dessus de 2300 m vers les pentes LARGE Nord**, des plaques à vent peu épaisses qui se sont formées la semaine passée, peuvent se déclencher plus difficilement par le passage d'un skieur, elles génèrent des avalanches de petites tailles, plus rarement moyennes (cassusres de 20-50 cm). Les plaques plus épaisses, reposant sur les sous-couches fragiles bien enfouies, sont généralement difficilement déclenchables.
Sous 2200 m le manteau neigeux est bien humidifié avec une bonne cohésion de regel en fin de nuit mais il devient plus instable et meuble avec l'ensoleillement.

Départs spontanés : **Risque prégnant d'avalanches de fond (de glissement)**, plus présent à partir de l'après-midi et persistant ensuite, **jour et nuit**, possibles **en toutes orientations** en moyenne montagne mais surtout sur pentes raides d'origine herbeuse ou près des rochers affleurants. Ces avalanches peuvent parfois s'approcher des bas de pente. Risque d'avalanches de taille 2 (épaisseur de cassure 50 cm), plus rarement une grande avalanche possible (épaisseur du manteau jusqu'à 1 m). Signes parfois à observer : **gueules de baleine** (fissures qui s'ouvrent dans le manteau perpendiculaires à la pente). Trouées d'avalanche récentes jusqu'à l'herbe, à proximité.
Des **glissements ponctuels en surface** sur les pentes ensoleillées sous les skis ou les raquettes sont probables.

Qualité de la neige

Enneigement : Rare ou faible enneigement sous 1500 m, l'enneigement est bon au-dessus de 1800 m mais bien irrégulièrement réparti, crêtes dégarnies, combes plus chargées et corniches restant souvent imposantes.
Limites skiables : à partir de 1600/1700 m en versants froid .
État de la neige : Un petit peu de neige fraîche sur une sous-couche souvent compacte ou regelée, et localement un peu de neige meuble sur les versants ombrés au-dessus 2300 m.

Aperçu météo pour le lundi 02 mars

	nuit	matin	après-midi	soir

Soleil, à peine finement voilé. Vent de sud encore soutenu. Début d'épisode de poussières sahariennes.

Pluie-Neige				
Iso 0 °C	2 600 m	2 700 m	2 700 m	2 600 m
Vent 2000 m	30 km/h	30 km/h	30 km/h	20 km/h
Vent 3000 m	40 km/h	45 km/h	50 km/h	40 km/h

Épaisseur de neige hors-piste

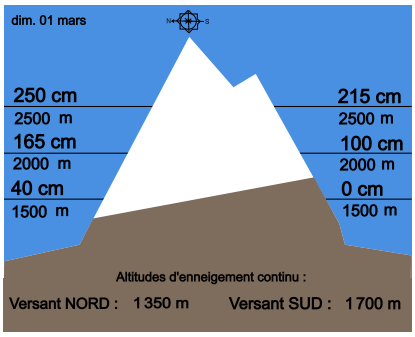

Précipitations à 1800 m

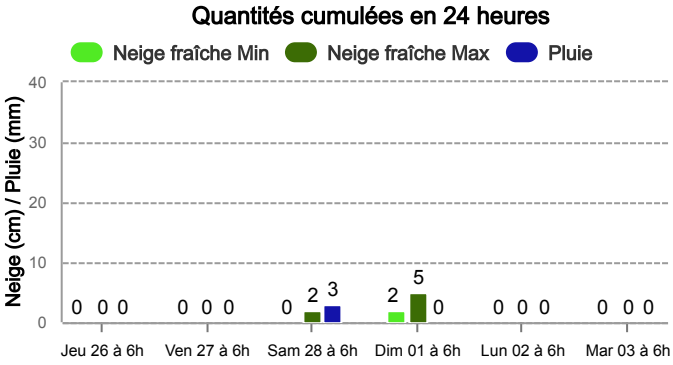

Tendance du mardi 03 mars

2

Indice de risque limité

Risques maintenus.

Pour consulter la vigilance en cours, veuillez vous rendre sur le site https://vigilance.meteofrance.fr/fr

Météo-France - 73 avenue de Paris, 94165 Saint-Mandé cedex - Contact : contact@meteo.fr

Rédigé par Météo-France avec la contribution des observateurs du réseau nivo-météorologiques. Partenariat : ANMSM (Maires de Stations de Montagne), DSF (Domaines Skiables de France), ADSP (Directeurs de Pistes et de la Sécurité des Stations de Sports d'Hiver) et autres acteurs de la montagne.

Bulletin neige & avalanches par téléphone au
0 892 68 10 20 Service 0,35 € / min + prix appel

Bulletin d'estimation du risque d'avalanche

(valable en dehors des pistes balisées et ouvertes)

MASSIF : Haute-Bigorre

Rédigé le dimanche 1 mars 2026 à 16h

Conditions nivo-météo des 7 derniers jours

	lun. 23/02				mar. 24/02				mer. 25/02				jeu. 26/02				ven. 27/02				sam. 28/02				dim. 01/03			
	03h	09h	15h	21h	03h	09h	15h	21h	03h	09h	15h	21h	03h	09h	15h	21h	03h	09h	15h	21h	03h	09h	15h	21h	03h	09h	15h	21h
Météo																												
Vent (km/h)	25	15	25	20	60	45	35	30	30	25	30	30	30	30	35	45	40	40	30	30	25	20	15	10	20	25	40	45
à 3000m																												
Vent (km/h)	10	5	20	15	30	25	20	20	15	15	15	15	15	15	20	30	20	25	20	10	10	10	10	5	10	15	25	30
à 2000m																												

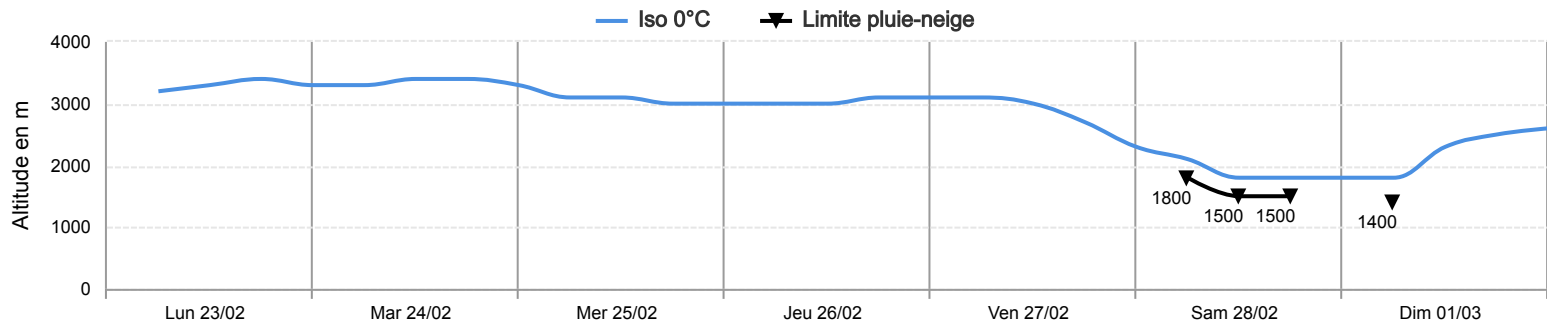

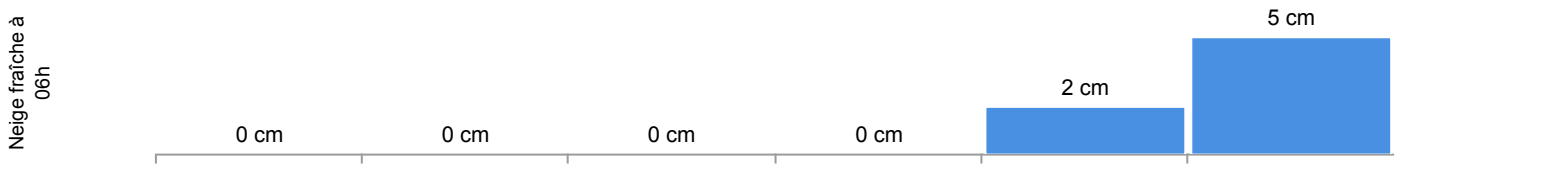

Risque d'avalanche	lun. 23/02	mar. 24/02	mer. 25/02	jeu. 26/02	ven. 27/02	sam. 28/02	dim. 01/03
	3	2	2	2	2	2	2

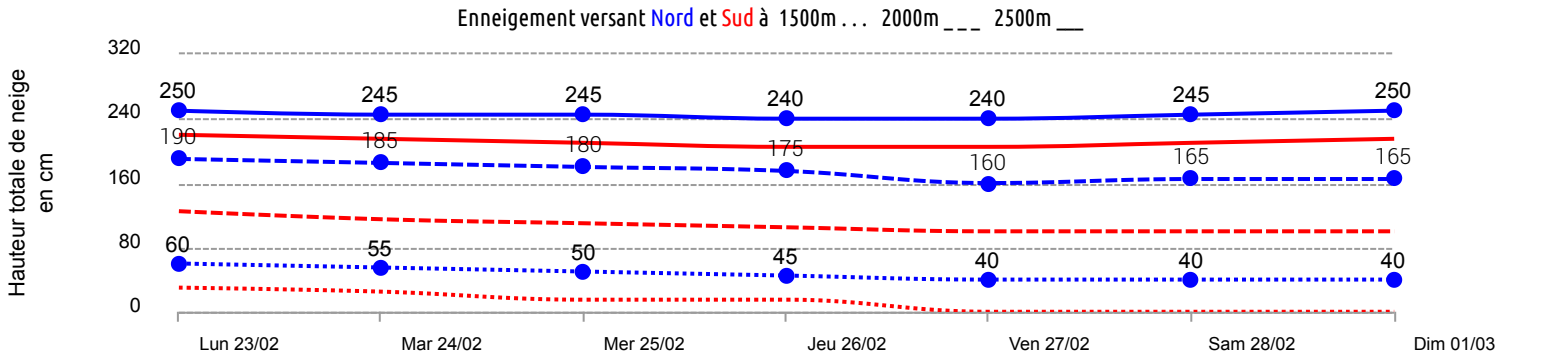

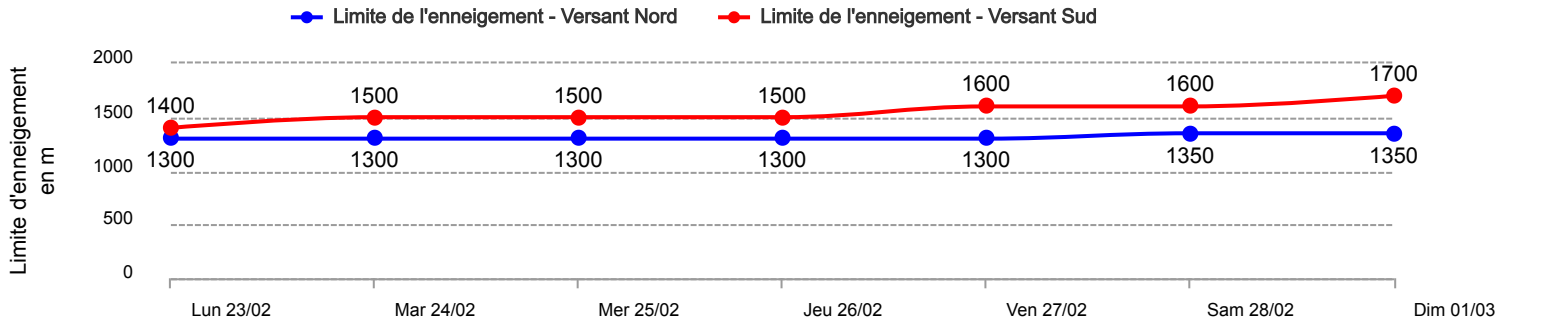

Pour consulter la vigilance en cours, veuillez vous rendre sur le site https://vigilance.meteofrance.fr/fr

Météo-France - 73 avenue de Paris, 94165 Saint-Mandé cedex - Contact : contact@meteo.fr

Rédigé par Météo-France avec la contribution des observateurs du réseau nivo-météorologiques. Partenariat : ANMSM (Maires de Stations de Montagne), DSF (Domaines Skiables de France), ADSP (Directeurs de Pistes et de la Sécurité des Stations de Sports d'Hiver) et autres acteurs de la montagne.

Bulletin neige & avalanches par téléphone au

0 892 68 10 20 Service 0,35 € / min + prix appel