Bulletin d'estimation du risque d'avalanche

(valable en dehors des pistes balisées et ouvertes)

MASSIF : Haute-Maurienne

Rédigé le dimanche 1 mars 2026 à 16h

Estimation des risques pour le : LUNDI 02 MARS

MANTEAU PLUTÔT STABLE LE MATIN, DÉSTABILISÉ PAR L'HUMIDIFICATION EN JOURNÉE, QUI RÉACTIVE LES COUCHES FRAGILES ENFOUIES.

3

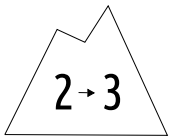

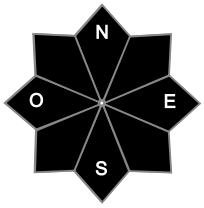

Indice de risque limité évoluant en marqué.

Départs spontanés : rares départs humides l'après-midi, rares plaques de fond.

Déclenchements provoqués : plaques humides au soleil, rares plaques dans les versants ombragés.

Indices de risque : 5 très fort - 4 fort - 3 marqué - 2 limité - 1 faible -- En noir : les pentes les plus dangereuses

Stabilité du manteau neigeux

Situation avalancheuse typique : neige humide couche fragile persistante

Déclenchements provoqués :

- Dans les **pentes ensoleillées hébergeant des couches fragiles enfouies (E/O et S d'altitude)**, après plusieurs heures de soleil, l'enfoncement dans la neige humide devient important, rendant à nouveau probable la sollicitation d'une couche fragile enfouie. Dès lors, une **avalanche de neige humide avec grande propagation** est possible. Taille 2 (moyenne), rarement 3 (grande).
- **Au-dessus de 2000/2200 m, en versants ombragés (NO/N/NE), rares plaques** parfois réactives, **surtout dans les zones moins enneigées** (abords de crête, croupes dégarnis, anciennes plaques faiblement recouverte) car la couche fragile est plus près de la surface. Taille 1 à 2 (petite à moyenne) avec cassure 50/70 cm.

Départs spontanés :

- **Quelques avalanches de neige humide** dans les pentes ayant chauffées plusieurs heures. Taille 1 à 2, rarement 3 lorsque l'humidification atteint une couche fragile enfouie.
- **Rares mais épaisses plaques de fond** pouvant descendre spontanément, **quelles que soient l'heure et l'orientation**. Plutôt **sous 2200/2400 m** et dans les pentes habituelles (herbe, dalle rocheuse). Le manteau neigeux actuel étant épais, les volumes mobilisés peuvent être plus conséquents que d'habitude. **Taille 2 (moyenne)**.

Qualité de la neige

Enneigement : Les températures anormalement douces et le tassement font rentrer l'enneigement dans la normale, surtout en Sud et en basse montagne où la limite d'enneigement dans ces pentes remonte vite. Ailleurs le manteau se tasse considérablement.

Limite skiable : encore skiable dès 1100 m dans les prairies orientées Nord, plutôt 1500 m en Sud.

Qualité de la neige : Saupoudrage près des sommets frontaliers. Ailleurs : En Sud, Est, Ouest, conditions de printemps idéales avec bon regel le matin et *"décaillage"* suivant la course du soleil. En Nord, neige croutée sous 2000 m (parfois plus haut). Au-dessus, neige encore froide, poudreuse dense à l'abri du vent, cartonnée voire dure dans les secteurs ventés (à l'approche des crêtes).

Aperçu météo pour le lundi 02 mars

	nuit	matin	après-midi	soir

Beau temps et grande douceur. Nuages plus nombreux près de la crête frontalière.

Pluie-Neige	1 300 m			
Iso 0 °C	1 900 m	2 000 m	2 300 m	2 000 m
Vent 2500 m	↖ 10 km/h	↖ 25 km/h	↖ 25 km/h	↖ 20 km/h
Vent 3500 m	↗ 15 km/h	↑ 15 km/h	↑ 10 km/h	↑ 10 km/h

Épaisseur de neige hors-piste

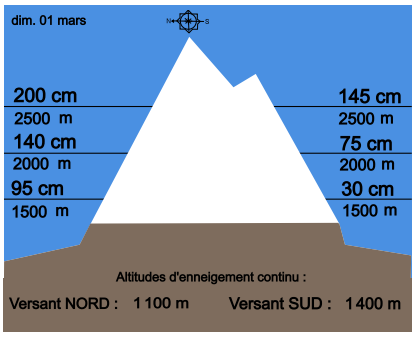

Précipitations à 1800 m

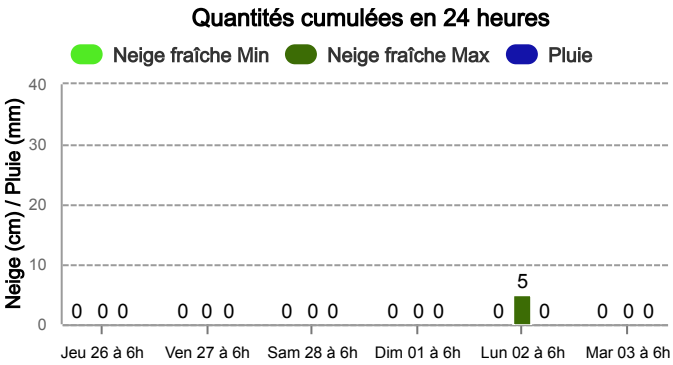

Tendance du mardi 03 mars

3

Indice de risque marqué

Risque stationnaire. Bon regel le matin puis humidification marquée induisant rapidement un risque d'avalanche humide.

Pour consulter la vigilance en cours, veuillez vous rendre sur le site https://vigilance.meteofrance.fr/fr

Météo-France - 73 avenue de Paris, 94165 Saint-Mandé cedex - Contact : contact@meteo.fr

Rédigé par Météo-France avec la contribution des observateurs du réseau nivo-météorologiques. Partenariat : ANMSM (Maires de Stations de Montagne), DSF (Domaines Skiables de France), ADSP (Directeurs de Pistes et de la Sécurité des Stations de Sports d'Hiver) et autres acteurs de la montagne.

Bulletin neige & avalanches par téléphone au

0 892 68 10 20 Service 0,35 € / min + prix appel

RÉPUBLIQUE FRANÇAISE
Liberté Égalité Fraternité

METEO FRANCE
À VOS CÔTÉS, DANS UN CLIMAT QUI CHANGE

Bulletin d'estimation du risque d'avalanche
(valable en dehors des pistes balisées et ouvertes)
MASSIF : Haute-Maurienne

Rédigé le dimanche 1 mars 2026 à 16h

Conditions nivo-météo des 7 derniers jours

	lun. 23/02				mar. 24/02				mer. 25/02				jeu. 26/02				ven. 27/02				sam. 28/02				dim. 01/03			
	03h	09h	15h	21h	03h	09h	15h	21h	03h	09h	15h	21h	03h	09h	15h	21h	03h	09h	15h	21h	03h	09h	15h	21h	03h	09h	15h	21h
Météo																												
Vent (km/h)	65	60	55	45	35	35	30	25	20	20	20	15	15	15	15	15	15	15	20	20	20	25	30	25	20	20	20	15
à 3500m																												
Vent (km/h)	50	45	40	30	20	15	15	10	5	5	5	5	5	5	5	5	5	5	10	10	10	10	15	10	5	10	5	10
à 2500m																												

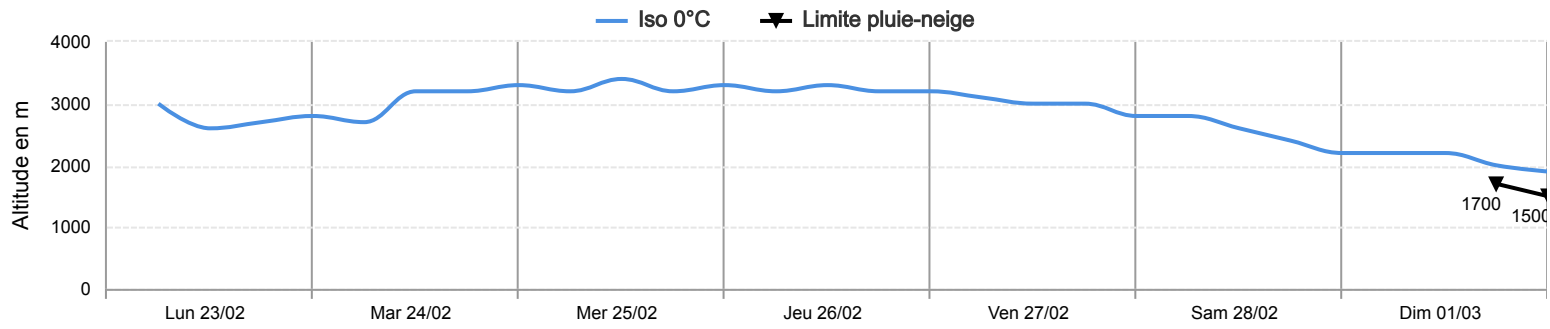

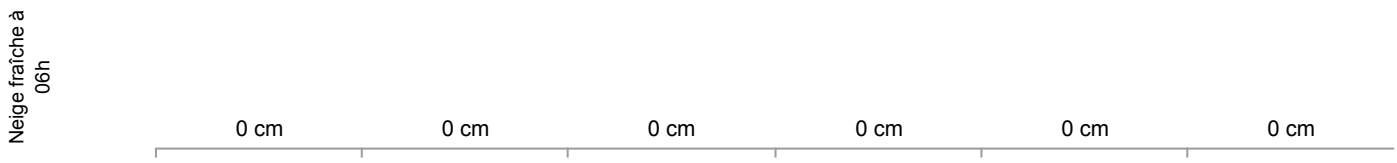

Risque d'avalanche	lun. 23/02	mar. 24/02	mer. 25/02	jeu. 26/02	ven. 27/02	sam. 28/02	dim. 01/03
	3	3	3	3	3	2	3

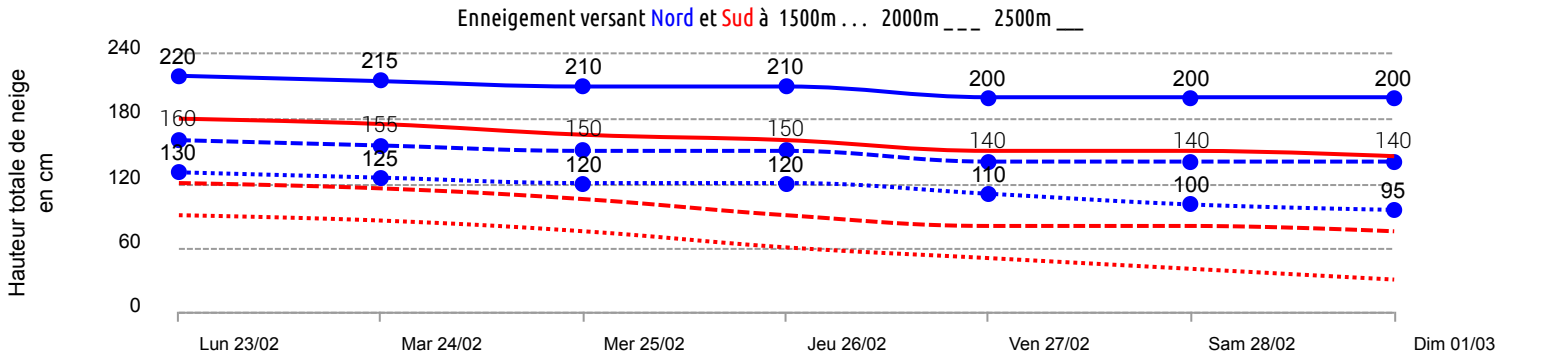

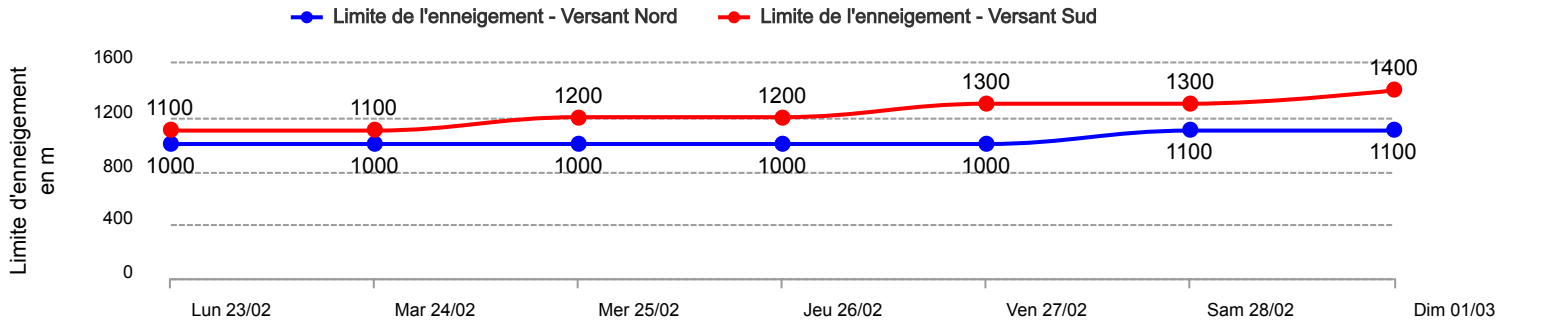

Pour consulter la vigilance en cours, veuillez vous rendre sur le site https://vigilance.meteofrance.fr/fr

Météo-France - 73 avenue de Paris, 94165 Saint-Mandé cedex - Contact : contact@meteo.fr

Rédigé par Météo-France avec la contribution des observateurs du réseau nivo-météorologiques. Partenariat : ANMSM (Maires de Stations de Montagne), DSF (Domaines Skiables de France), ADSP (Directeurs de Pistes et de la Sécurité des Stations de Sports d'Hiver) et autres acteurs de la montagne.

Bulletin neige & avalanches par téléphone au

0 892 68 10 20 Service 0,35 € / min + prix appel