# Bulletin d'estimation du risque d'avalanche
(valable en dehors des pistes balisées et ouvertes)

# MASSIF : Mercantour

Rédigé le dimanche 1 mars 2026 à 16h

## Estimation des risques pour le : LUNDI 02 MARS

**QUELQUES DÉPARTS EN NEIGE HUMIDE**

2

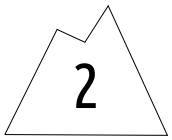


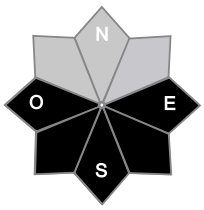


Indice de risque limité.

**Départs spontanés :** quelques avalanches de fond, rares départs superficiels en neige humide.

**Déclenchements provoqués :** départs en neige humide.

Indices de risque : 5 très fort - 4 fort - 3 marqué - 2 limité - 1 faible -- En noir : les pentes les plus dangereuses

## Stabilité du manteau neigeux

**Situation avalancheuse typique :** avalanches de fond neige humide

**Départs spontanés :**
- **quelques avalanches de fond** suite à la rupture de reptations (gueules de baleine). Taille moyenne, voire grande. Possibles à n'importe quel moment du jour et de la nuit. En versant sud, plutôt en dessous de 2500/2700 m. En versant nord, plutôt en dessous de 2000 m.
- un rare départ en **neige humide** reste possible, mais devient rare et reste superficiel. Départs ponctuels de petite taille, rarement moyenne, dans les orientations est / sud / ouest.

**Déclenchements provoqués :**
- un rare départ en **neige humide** reste possible, mais devient rare et reste superficiel. Départs ponctuels de petite taille, rarement moyenne, dans les orientations est / sud / ouest.

## Qualité de la neige

**Enneigement** excédentaire pour un début mars.
Données observées : 137 cm à la nivôse de Millefonts à 2430 m, 110 cm à Isola 2000 à 1912 m.

**Enneigement skiable** dès 1400/1500 m en ubacs en terrains favorables et 1600/1800 m en adrets

**État de la neige en surface** : croute souvent portante le matin après un bon regel nocturne, s'humidifiant en journée au fil de l'ensoleillement. En ubacs au-dessus de 2000/2200 m environ, neige froide souvent travaillée/durcie par le vent de nord. Zones dégarnies proches des crêtes, alternant avec des corniches parfois épaisses.

## Aperçu météo pour le lundi 02 mars

| nuit | matin | après-midi | soir |
|---|---|---|---|

Temps lumineux, mais l'ensoleillement peut être contrarié par quelques passages nuageux accrochant le relief. Quelques flocons possibles.

| | | | | |
|---|---|---|---|---|
| **Pluie-Neige** | | | 1 700 m | |
| **Iso 0 °C** | 1 900 m | 1 800 m | 1 900 m | 1 900 m |
| **Vent 2000 m** | ↗ 5 km/h | ↖ 10 km/h | ↑ 15 km/h | ↓ 10 km/h |
| **Vent 3000 m** | ↗ 15 km/h | ↑ 15 km/h | ↑ 15 km/h | ↗ 10 km/h |

## Épaisseur de neige hors-piste

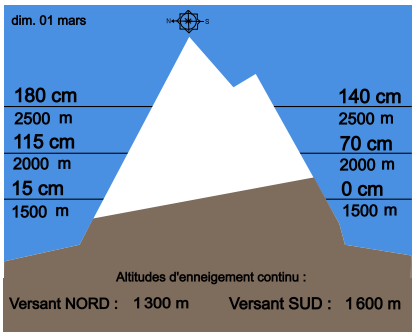


## Précipitations à 1800 m

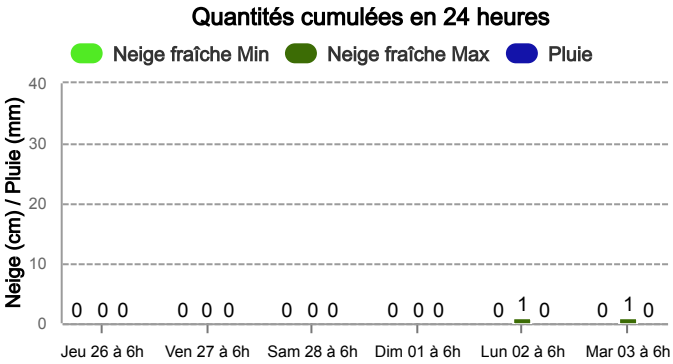


## Tendance du mardi 03 mars

2

**Indice de risque limité**

Maintien d'un risque limité. Des départs en neige humide restent possibles.

Pour consulter la vigilance en cours, veuillez vous rendre sur le site https://vigilance.meteofrance.fr/fr

Météo-France - 73 avenue de Paris, 94165 Saint-Mandé cedex - Contact : contact@meteo.fr

Rédigé par Météo-France avec la contribution des observateurs du réseau nivo-météorologiques. Partenariat : ANMSM (Maires de Stations de Montagne), DSF (Domaines Skiables de France), ADSP (Directeurs de Pistes et de la Sécurité des Stations de Sports d'Hiver) et autres acteurs de la montagne.

Bulletin neige & avalanches par téléphone au 0 892 68 10 20 Service 0,35 € / min + prix appel

RÉPUBLIQUE FRANÇAISE
*Liberté Égalité Fraternité*

METEO FRANCE
À VOS CÔTÉS, DANS UN CLIMAT QUI CHANGE

# Bulletin d'estimation du risque d'avalanche
## (valable en dehors des pistes balisées et ouvertes)

# MASSIF : Mercantour

Rédigé le dimanche 1 mars 2026 à 16h

## Conditions nivo-météo des 7 derniers jours

| | lun. 23/02 | | | | mar. 24/02 | | | | mer. 25/02 | | | | jeu. 26/02 | | | | ven. 27/02 | | | | sam. 28/02 | | | | dim. 01/03 | | | |
|---|---|---|---|---|---|---|---|---|---|---|---|---|---|---|---|---|---|---|---|---|---|---|---|---|---|---|---|---|
| | 03h | 09h | 15h | 21h | 03h | 09h | 15h | 21h | 03h | 09h | 15h | 21h | 03h | 09h | 15h | 21h | 03h | 09h | 15h | 21h | 03h | 09h | 15h | 21h | 03h | 09h | 15h | 21h |
| Météo | | | | | | | | | | | | | | | | | | | | | | | | | | | | |
| Vent (km/h) | 50 | 45 | 25 | 20 | 30 | 25 | 10 | 10 | 15 | 15 | 15 | 15 | 15 | 15 | 15 | 10 | 10 | 10 | 10 | 10 | 15 | 20 | 25 | 15 | 15 | 20 | 20 | 20 |
| à 3000m | | | | | | | | | | | | | | | | | | | | | | | | | | | | |
| Vent (km/h) | 25 | 20 | 15 | 15 | 15 | 10 | 5 | 10 | 10 | 10 | 10 | 10 | 10 | 5 | 10 | 10 | 5 | 5 | 10 | 5 | 5 | 10 | 15 | 5 | 5 | 5 | 15 | 10 |
| à 2000m | | | | | | | | | | | | | | | | | | | | | | | | | | | | |

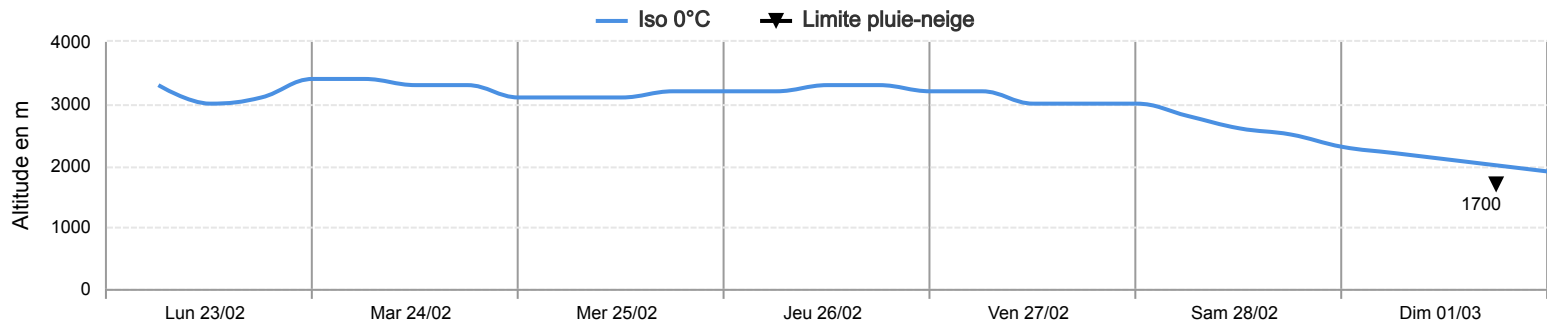


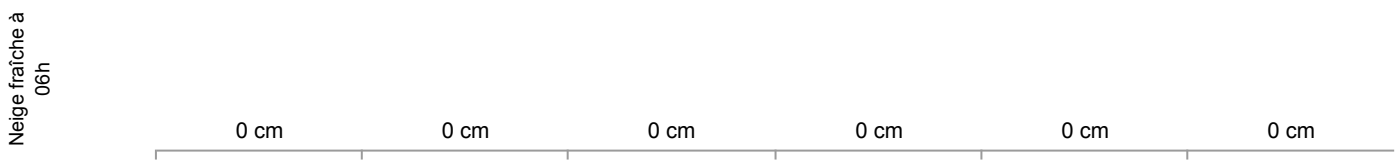


| Risque d'avalanche | lun. 23/02 | mar. 24/02 | mer. 25/02 | jeu. 26/02 | ven. 27/02 | sam. 28/02 | dim. 01/03 |
|---|---|---|---|---|---|---|---|
| | 3 | 2 | 2 | 2 | 2 | 2 | 2 |

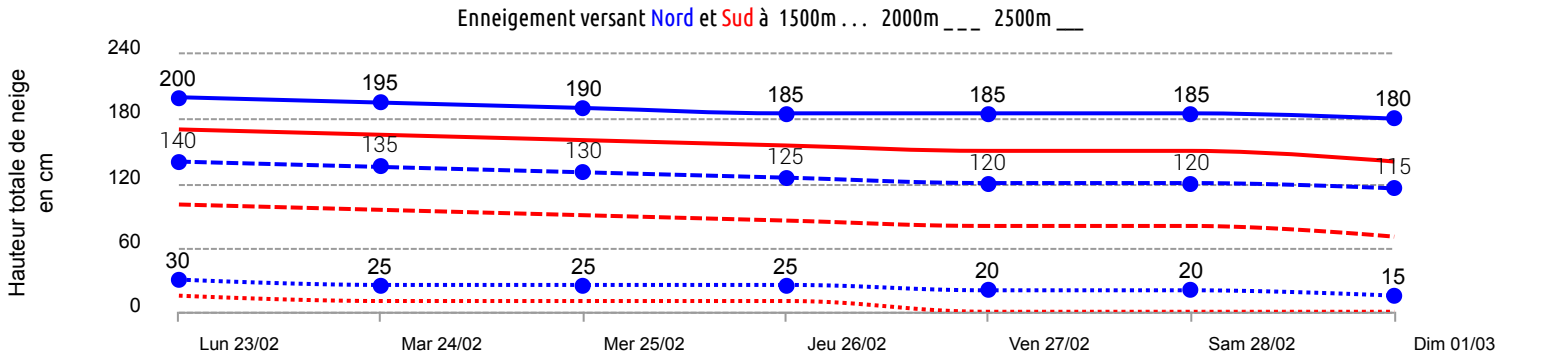


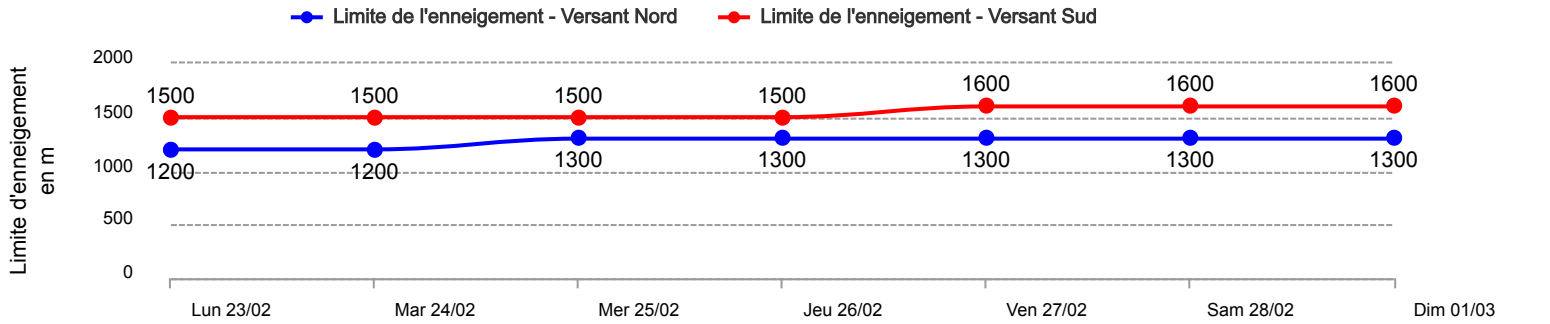


Pour consulter la vigilance en cours, veuillez vous rendre sur le site https://vigilance.meteofrance.fr/fr


Météo-France - 73 avenue de Paris, 94165 Saint-Mandé cedex - Contact : contact@meteo.fr


Bulletin neige & avalanches par téléphone au
0 892 68 10 20 Service 0,35 € / min + prix appel


Rédigé par Météo-France avec la contribution des observateurs du réseau nivo-météorologiques. Partenariat : ANMSM (Maires de Stations de Montagne), DSF (Domaines Skiables de France), ADSP (Directeurs de Pistes et de la Sécurité des Stations de Sports d'Hiver) et autres acteurs de la montagne.