Bulletin d'estimation du risque d'avalanche
(valable en dehors des pistes balisées et ouvertes)
MASSIF : Mont-Blanc

Rédigé le dimanche 1 mars 2026 à 16h

Estimation des risques pour le : LUNDI 02 MARS

MANTEAU NEIGEUX QUI SE RÉCHAUFFE AU FIL DE LA JOURNÉE.

2

2

N O E S

Indice de risque limité.

Départs spontanés : Départs humides et plaques de fond.

Déclenchements provoqués : Neige humide en moyenne montagne, au fil du réchauffement diurne.

Indices de risque : 5 très fort - 4 fort - 3 marqué - 2 limité - 1 faible -- En noir : les pentes les plus dangereuses

Stabilité du manteau neigeux

Situation avalancheuse typique : neige humide — avalanches de fond

Départs spontanés :
* Au fil du réchauffement diurne : de plus en plus de départs dans la **neige humide**. Possibles en tous versants, mais majoritairement dans les pentes ensoleillées, sous 2400 m. Départs ponctuels souvent dans les pentes raides et vers les rochers/falaises. Départs en plaques possibles en cascade. Taille 2 (moyenne), rarement 3 (grande).
* En tous versant, principalement sous 2400 m : **plaques de fond**. Départs dans les pentes raides et lisses (pentes herbeuses, dalles rocheuses). Départs possibles à toute heure du jour ou de la nuit. Taille 2 (moyenne), à 3 (grande). Plus nombreuses au fil du réchauffement.
* Chutes de **corniches**, épaisses et volumineuses. Leurs chutes peuvent déclencher une plaque en contrebas.

Déclenchements provoqués :
* En dessous de 2400 m en tous versants mais principalement dans les versants au soleil : de la **neige humide** peut couler sous les skis au fil du réchauffement diurne. Taille 1(petite) à 2 (moyenne).
* Au-dessus de 2000 m en versants E/N/O : Présence d'une **couche fragile persistante enfouie.** Difficile à déclencher mais elle peut être **sollicitée en cascade** et donner une avalanche de plus grande ampleur (cassure de 80/150 cm). La profondeur de l'enfouissement de la couche fragile varie énormément, même dans une même pente. Taille 3 (grande).
* En haute montagne : **rares plaques à vent** formées par le **vent de SW** de ces derniers jours dans la neige récente restée légère. Principalement présentes vers les crêtes/arêtes. Taille 2 (moyenne).

Qualité de la neige

Enneigement : bon pour la période. On peut chausser les skis vers 1200/1300 m en versants E/N/O et 1400/1500 m en versants Sud. Les corniches sont volumineuses et menaçantes. Les arêtes et les crêtes de moyenne montagne sont érodées par le vent de SW à NW.

Qualité de la neige lundi :
* regel nocturne efficace.
* Sous 1800 m : Le matin, la neige est dure regelée. Au fil du réchauffement diurne, elle devient lourde et humide. Enfoncement piéton important.
* Entre 1800 m et 3000 m : dans les versants E/S/O, croûte de regel en surface, peu portante, même à ski. Elle se ramollit rapidement au fil de la journée. Dans les versants N, la neige est restée assez froide mais elle est tassée.
* Au-dessus de 3000 m : neige froide, souvent dure travaillée par le vent de NW à SW, mais encore légère dans quelques pentes peu exposées au vent.

Aperçu météo pour le lundi 02 mars

	nuit	matin	après-midi	soir

Belle journée ensoleillée. L'après-midi quelques cumulus se forment dans le massif. Doux.

Pluie-Neige				
Iso 0 °C	2 000 m	2 100 m	2 200 m	2 200 m
Vent 2000 m	10 km/h	10 km/h	10 km/h	10 km/h
Vent 4000 m	15 km/h	15 km/h	15 km/h	15 km/h

Épaisseur de neige hors-piste

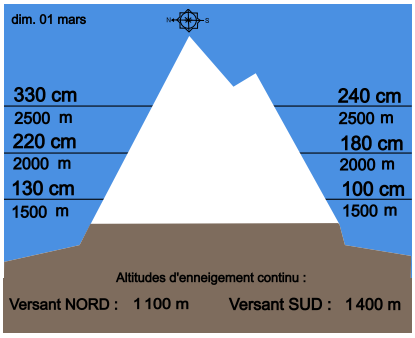

Précipitations à 1800 m

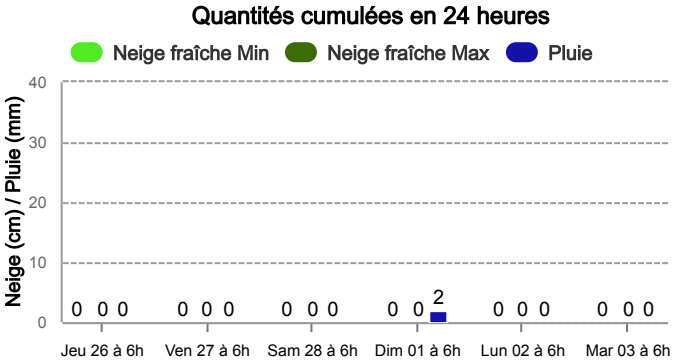

Tendance du mardi 03 mars

2

Indice de risque limité

Bon regel nocturne. La surface de la neige se réchauffe et se ramollit rapidement au soleil. La journée est ensoleillée et douce.
Isotherme 0°C vers 2300 m.

Pour consulter la vigilance en cours, veuillez vous rendre sur le site https://vigilance.meteofrance.fr/fr

Météo-France - 73 avenue de Paris, 94165 Saint-Mandé cedex - Contact : contact@meteo.fr

Rédigé par Météo-France avec la contribution des observateurs du réseau nivo-météorologiques. Partenariat : ANMSM (Maires de Stations de Montagne), DSF (Domaines Skiables de France), ADSP (Directeurs de Pistes et de la Sécurité des Stations de Sports d'Hiver) et autres acteurs de la montagne.

Bulletin neige & avalanches par téléphone au 0 892 68 10 20 Service 0,35 € / min + prix appel

RÉPUBLIQUE FRANÇAISE
Liberté Égalité Fraternité

METEO FRANCE
À VOS CÔTÉS, DANS UN CLIMAT QUI CHANGE

Bulletin d'estimation du risque d'avalanche

(valable en dehors des pistes balisées et ouvertes)

MASSIF : Mont-Blanc

Rédigé le dimanche 1 mars 2026 à 16h

Conditions nivo-météo des 7 derniers jours

	lun. 23/02				mar. 24/02				mer. 25/02				jeu. 26/02				ven. 27/02				sam. 28/02				dim. 01/03			
	03h	09h	15h	21h	03h	09h	15h	21h	03h	09h	15h	21h	03h	09h	15h	21h	03h	09h	15h	21h	03h	09h	15h	21h	03h	09h	15h	21h
Météo																												
Vent (km/h)	60	60	60	70	70	60	40	30	20	20	20	20	20	20	30	30	30	30	30	40	50	60	50	40	40	40	25	20
à 4000m																												
Vent (km/h)	25	25	25	20	10	10	10	10	10	10	10	10	10	10	10	10	10	10	10	10	10	15	10	10	10	10	10	5
à 2000m																												

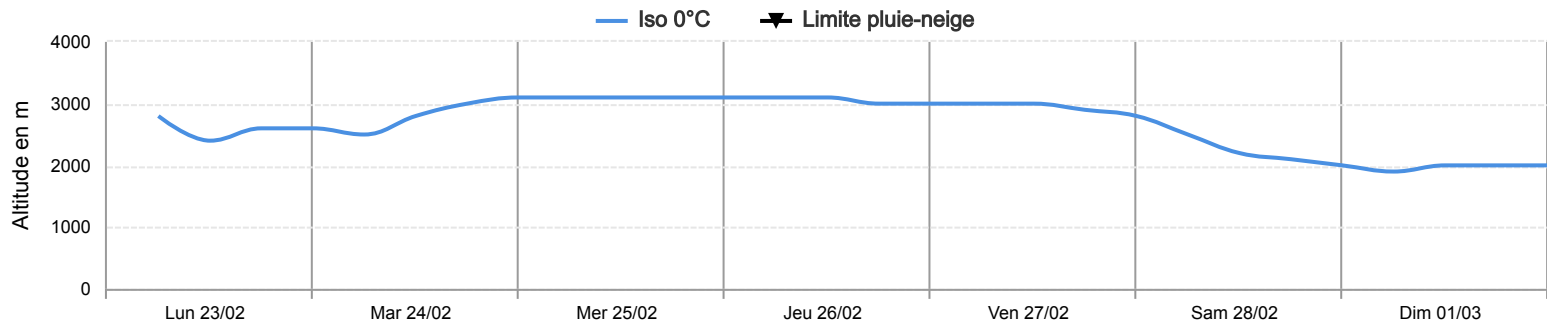

Neige fraîche à 06h

Lun 23/02	Mar 24/02	Mer 25/02	Jeu 26/02	Ven 27/02	Sam 28/02
0 cm	0 cm	0 cm	0 cm	0 cm	0 cm

Risque d'avalanche	lun. 23/02	mar. 24/02	mer. 25/02	jeu. 26/02	ven. 27/02	sam. 28/02	dim. 01/03
	3	3	3	3	3	2	2

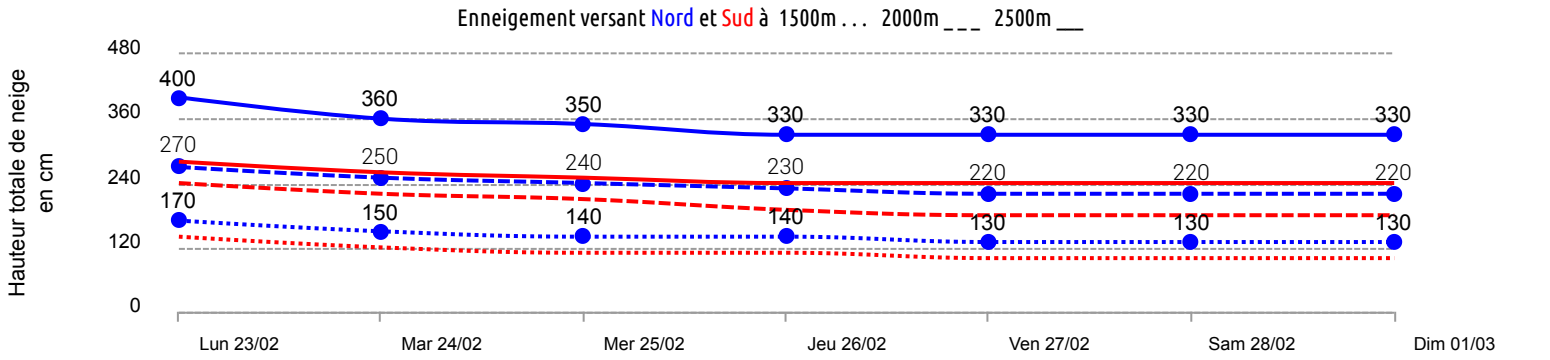

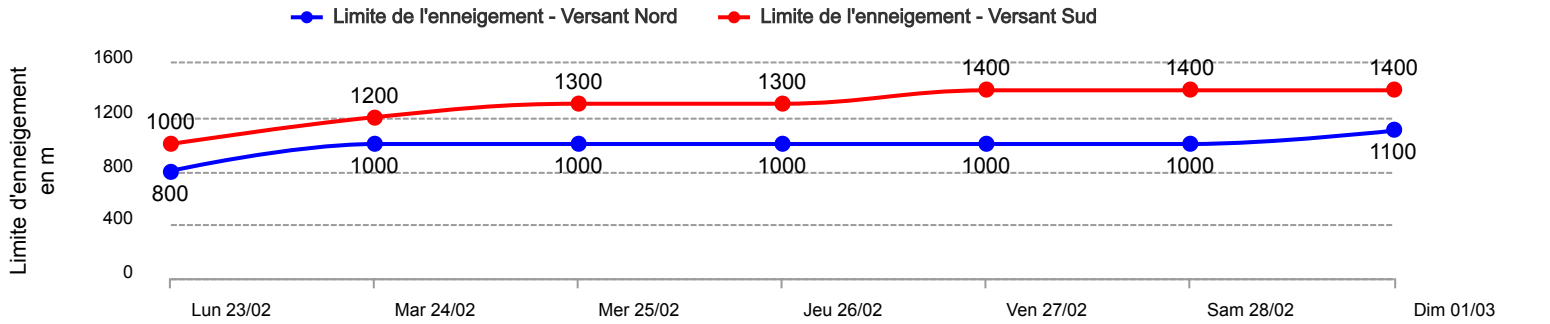

Pour consulter la vigilance en cours, veuillez vous rendre sur le site https://vigilance.meteofrance.fr/fr

Météo-France - 73 avenue de Paris, 94165 Saint-Mandé cedex - Contact : contact@meteo.fr

Rédigé par Météo-France avec la contribution des observateurs du réseau nivo-météorologiques. Partenariat : ANMSM (Maires de Stations de Montagne), DSF (Domaines Skiables de France), ADSP (Directeurs de Pistes et de la Sécurité des Stations de Sports d'Hiver) et autres acteurs de la montagne.

Bulletin neige & avalanches par téléphone au
0 892 68 10 20 Service 0,35 € / min + prix appel