Bulletin d'estimation du risque d'avalanche
(valable en dehors des pistes balisées et ouvertes)

MASSIF : Pays-Basque

Rédigé le dimanche 1 mars 2026 à 16h

Estimation des risques pour le : LUNDI 02 MARS

MANTEAU HUMIDE.

1

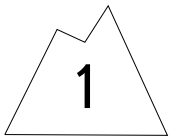

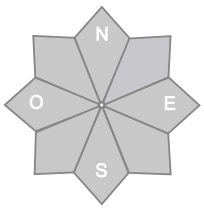

Avalanches de fond

Indice de risque faible.

Départs spontanés : Quelques avalanches de fond ou de surface.

Déclenchements provoqués : Peu probable.

Indices de risque : 5 très fort - 4 fort - 3 marqué - 2 limité - 1 faible -- En noir : les pentes les plus dangereuses

Stabilité du manteau neigeux

Situation avalancheuse typique : avalanches de fond neige humide

Départs spontanés : Des avalanches de fond plus probables avec le redoux persistant et l'ensoleillement généreux, surtout l'après-midi et possibles la nuit suivante, en toutes orientations même si plus fréquentes en versants ensoleillés. Avalanches de tailles 1 à 2 (moyenne), une rare plus grande reste malgré tout envisageable partant d'une pente chargée. Glissement ponctuel de surface possible sous le soleil en neige humide.

Déclenchements provoqués : Bonne cohésion de regel sur ce massif, quelques glissements de surface possibles au soleil en journée sous raquettes ou skis, les fines plaques en versants froid sont humidifiées.

Qualité de la neige

Enneigement : faible enneigement sous 1500 m, l'enneigement est bon au-dessus de 1800 m mais bien irrégulièrement réparti, crêtes dégarnies, combes plus chargées, et corniches parfois imposantes.
Limites skiables : à partir de 1600/1700 m en versants froids.
État de la neige : Neige humidifiée, regelée au matin et portante, devenant molle et gorgée en après-midi sous le soleil.

Aperçu météo pour le lundi 02 mars

nuit	matin	après-midi	soir

Soleil, à peine finement voilé. Vent de sud encore soutenu. Début d'épisode de poussières sahariennes.

Pluie-Neige				
Iso 0 °C	2 600 m	2 700 m	2 700 m	2 600 m
Vent 1000 m	60 km/h	55 km/h	45 km/h	40 km/h
Vent 2000 m	85 km/h	80 km/h	80 km/h	70 km/h

Épaisseur de neige hors-piste

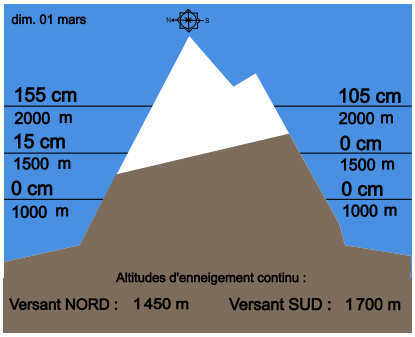

Précipitations à 1800 m

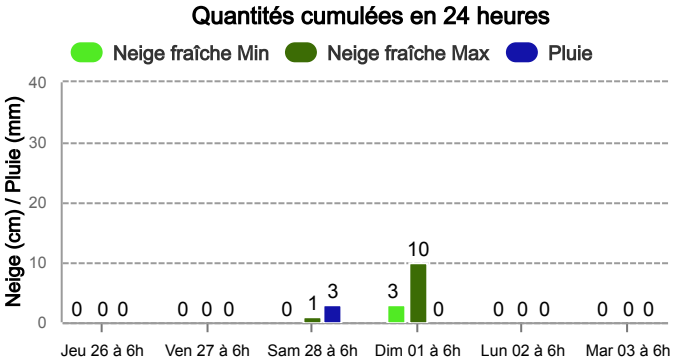

Tendance du mardi 03 mars

1

Indice de risque faible

Risques maintenus.

Pour consulter la vigilance en cours, veuillez vous rendre sur le site https://vigilance.meteofrance.fr/fr

Météo-France - 73 avenue de Paris, 94165 Saint-Mandé cedex - Contact : contact@meteo.fr

Rédigé par Météo-France avec la contribution des observateurs du réseau nivo-météorologiques. Partenariat : ANMSM (Maires de Stations de Montagne), DSF (Domaines Skiables de France), ADSP (Directeurs de Pistes et de la Sécurité des Stations de Sports d'Hiver) et autres acteurs de la montagne.

Bulletin neige & avalanches par téléphone au 0 892 68 10 20 Service 0,35 € / min + prix appel

Bulletin d'estimation du risque d'avalanche

(valable en dehors des pistes balisées et ouvertes)

MASSIF : Pays-Basque

Rédigé le dimanche 1 mars 2026 à 16h

Conditions nivo-météo des 7 derniers jours

	lun. 23/02				mar. 24/02				mer. 25/02				jeu. 26/02				ven. 27/02				sam. 28/02				dim. 01/03			
	03h	09h	15h	21h	03h	09h	15h	21h	03h	09h	15h	21h	03h	09h	15h	21h	03h	09h	15h	21h	03h	09h	15h	21h	03h	09h	15h	21h
Météo																												
Vent (km/h)	15	15	20	45	60	55	40	35	35	35	35	35	35	35	45	50	50	55	45	30	25	25	25	25	30	50	75	85
à 2000m																												
Vent (km/h)	5	5	10	15	20	15	15	15	15	15	15	15	20	20	25	30	40	40	25	15	10	10	15	15	15	25	50	55
à 1000m																												

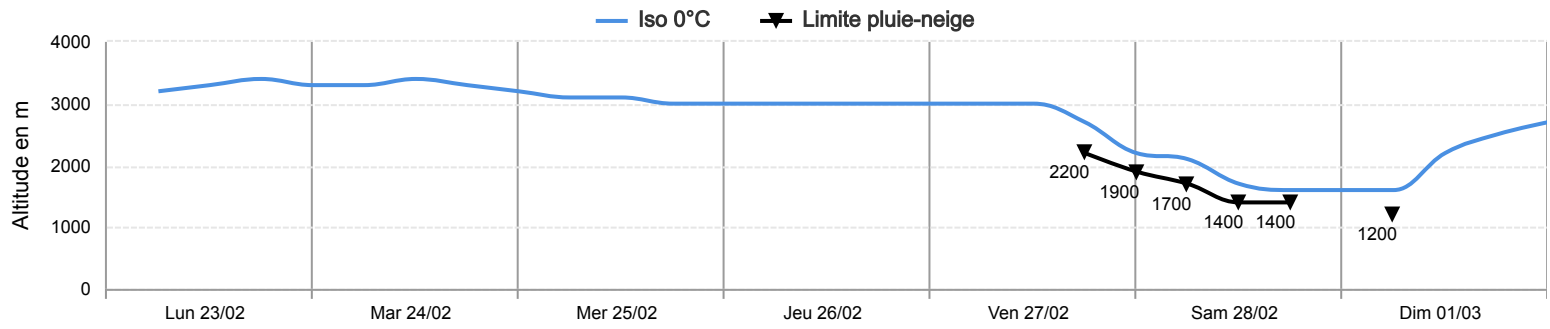

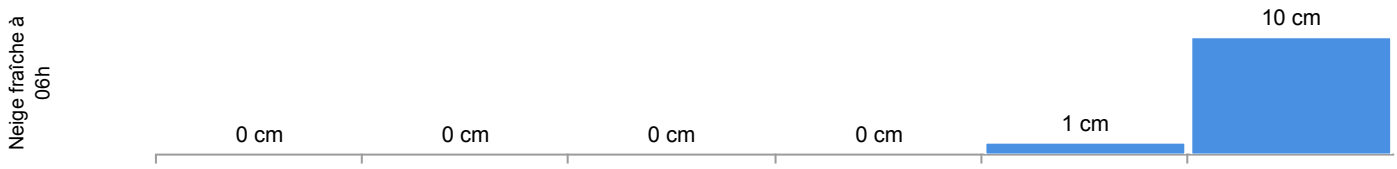

Risque d'avalanche	lun. 23/02	mar. 24/02	mer. 25/02	jeu. 26/02	ven. 27/02	sam. 28/02	dim. 01/03
	2	2	1	1	1	1	1

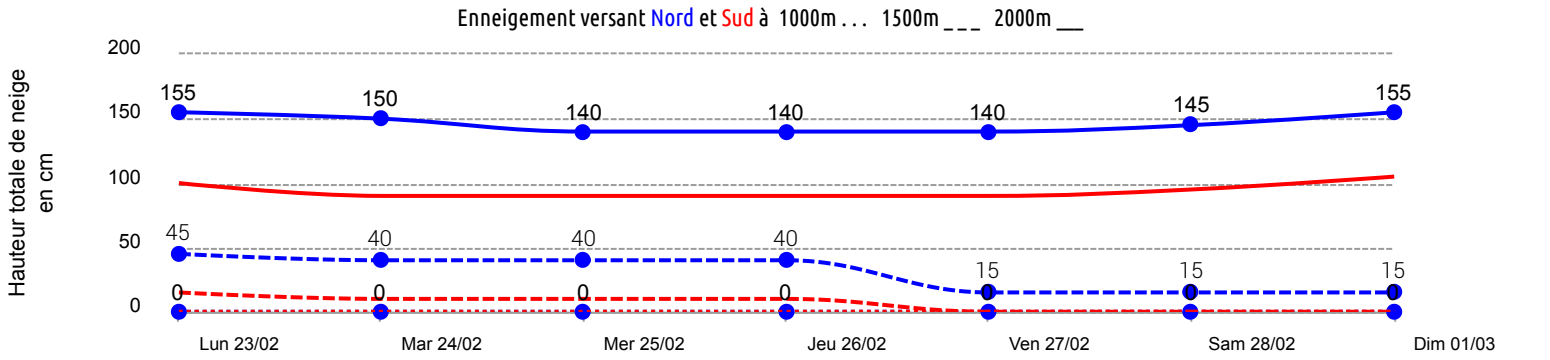

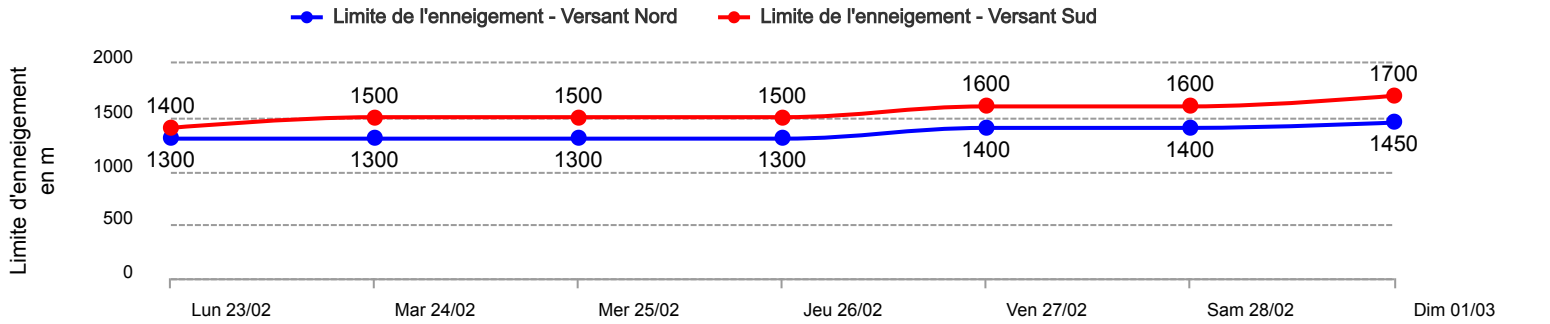

Pour consulter la vigilance en cours, veuillez vous rendre sur le site https://vigilance.meteofrance.fr/fr

Météo-France - 73 avenue de Paris, 94165 Saint-Mandé cedex - Contact : contact@meteo.fr

Bulletin neige & avalanches par téléphone au

0 892 68 10 20 Service 0,35 € / min + prix appel

Rédigé par Météo-France avec la contribution des observateurs du réseau nivo-météorologiques. Partenariat : ANMSM (Maires de Stations de Montagne), DSF (Domaines Skiables de France), ADSP (Directeurs de Pistes et de la Sécurité des Stations de Sports d'Hiver) et autres acteurs de la montagne.