Bulletin d'estimation du risque d'avalanche

(valable en dehors des pistes balisées et ouvertes)

MASSIF : Thabor

Rédigé le dimanche 1 mars 2026 à 16h

Estimation des risques pour le : LUNDI 02 MARS

PLAQUES EN ALTITUDE, DIFFICILES À SOLLICITER - FAIBLE ACTIVITÉ EN NEIGE HUMIDE

2

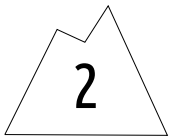

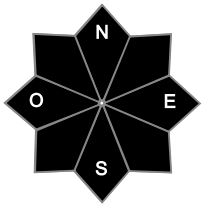

Indice de risque limité.

Départs spontanés : rares départs en neige humide ou avalanches de fond

Déclenchements provoqués : avalanches de plaque difficiles à déclencher, mais pouvant engendrer d'épaisses cassures

Indices de risque : 5 très fort - 4 fort - 3 marqué - 2 limité - 1 faible -- En noir : les pentes les plus dangereuses

Stabilité du manteau neigeux

Situation avalancheuse typique : couche fragile persistante neige humide

Déclenchements provoqués : - même si le déclenchement semble difficile, une avalanche de plaque reste encore possible au-dessus de 2200 m environ, dans les pentes où la neige est restée froide (large nord) ou présente un aspect humide (versants ensoleillés humidifiés). Sollicitation peu probable en milieu de pente, mais possible dans les endroits peu enneigés ou dans les transitions entre secteurs très enneigés et peu enneigés (abords des croupes, bords des couloirs, à proximité des rochers, etc...). Cassures épaisses, parfois larges en ubacs, pouvant se propager dans les grandes pentes très enneigées, emportant la quasi-totalité du manteau neigeux en place (présence des couches fragiles persistantes enfouies à la base du manteau neigeux).
- le passage d'un skieur dans une pente raide ayant trop chauffé peut aussi favoriser un départ ponctuel en neige humide.

Départs spontanés : - l'activité en neige humide au soleil reste limitée. Rares avalanches de taille petite à moyenne dans les pentes raides très ensoleillées, au fil de la journée plutôt près des rochers, parfois jusqu'au sol en neige pourrie.
- une avalanche de fond ou une reptation emportant la totalité du manteau neigeux en place jusqu'au sol peut céder spontanément à toute heure du jour ou de la nuit sur terrain favorable (pentes herbeuses, dalles rocheuses). Avalanche de taille moyenne.

Qualité de la neige

L'enneigement est excédentaire. Les limites d'enneigement remontent dans les pentes bien exposées au soleil.
Hauteurs de neige observées vers 2500 m : 187 cm dans le vallon du Chardonnet, 126 cm à la nivose des Rochilles, 84 cm à la nivose du Galibier (secteur venté).

Limite d'enneigement skiable en fond de vallées en ubacs, 1500/1600 m en adrets pas trop raides.

État de la neige de surface : rares cm de neige fraiche. Après un regel correct, manteau neigeux en adrets, croûté, humidification en journée plus marquée aux basses altitudes. En versants nord-est, nord et nord-ouest, la neige reste sèche, ou humidifiée / regelée seulement en surface sous 2000/2200 m. Plus haut, la neige est plus ou moins durcie, mais évolue de plus en plus en vieille neige meuble dans les pentes ou combes plutôt abritées.

Aperçu météo pour le lundi 02 mars

	nuit	matin	après-midi	soir

Près de l'Italie, débordements nuageux (nebbia). Visibilité moyenne avec des poussières désertiques en suspension dans l'atmosphère.

Pluie-Neige				
Iso 0 °C	1 700 m	1 700 m	2 000 m	1 700 m
Vent 2000 m	↑ 10 km/h	↖ 10 km/h	↖ 15 km/h	↑ 10 km/h
Vent 3000 m	↖ 20 km/h	↖ 25 km/h	↖ 25 km/h	↖ 20 km/h

Épaisseur de neige hors-piste

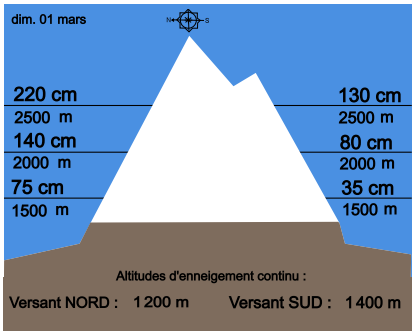

Précipitations à 1800 m

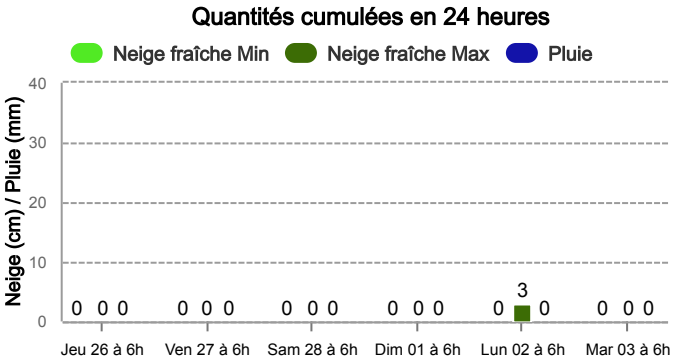

Tendance du mardi 03 mars

2

Indice de risque limité

Risque limité. Encore des plaques difficiles à déclencher en altitude. Activité en neige humide limitée.

Pour consulter la vigilance en cours, veuillez vous rendre sur le site https://vigilance.meteofrance.fr/fr

Météo-France - 73 avenue de Paris, 94165 Saint-Mandé cedex - Contact : contact@meteo.fr

Rédigé par Météo-France avec la contribution des observateurs du réseau nivo-météorologiques. Partenariat : ANMSM (Maires de Stations de Montagne), DSF (Domaines Skiables de France), ADSP (Directeurs de Pistes et de la Sécurité des Stations de Sports d'Hiver) et autres acteurs de la montagne.

Bulletin neige & avalanches par téléphone au 0 892 68 10 20 Service 0,35 € / min + prix appel

RÉPUBLIQUE FRANÇAISE
Liberté Égalité Fraternité

METEO FRANCE
À VOS CÔTÉS, DANS UN CLIMAT QUI CHANGE

Bulletin d'estimation du risque d'avalanche
(valable en dehors des pistes balisées et ouvertes)

MASSIF : Thabor

Rédigé le dimanche 1 mars 2026 à 16h

Conditions nivo-météo des 7 derniers jours

	lun. 23/02				mar. 24/02				mer. 25/02				jeu. 26/02				ven. 27/02				sam. 28/02				dim. 01/03			
	03h	09h	15h	21h	03h	09h	15h	21h	03h	09h	15h	21h	03h	09h	15h	21h	03h	09h	15h	21h	03h	09h	15h	21h	03h	09h	15h	21h
Météo																												
Vent (km/h)	50	50	50	45	30	15	5	10	15	10	10	10	10	10	10	10	10	5	10	15	20	20	25	20	15	20	20	20
à 3000m																												
Vent (km/h)	10	20	15	15	10	5	0	5	5	5	5	5	5	5	5	5	5	5	5	5	5	10	15	10	5	10	15	10
à 2000m																												

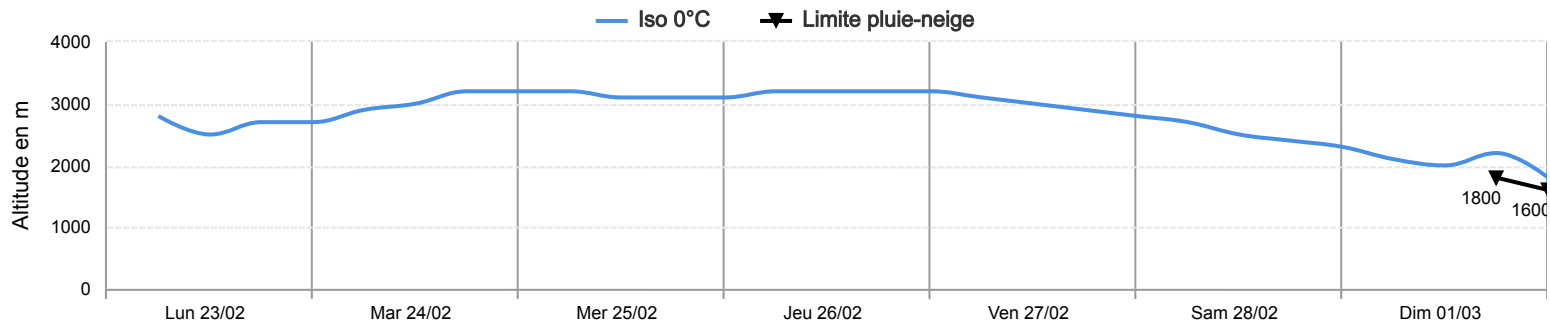

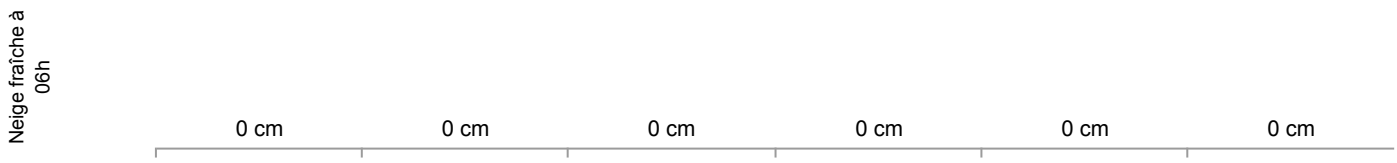

Risque d'avalanche	lun. 23/02	mar. 24/02	mer. 25/02	jeu. 26/02	ven. 27/02	sam. 28/02	dim. 01/03
	3	3	3	3	2	2	2

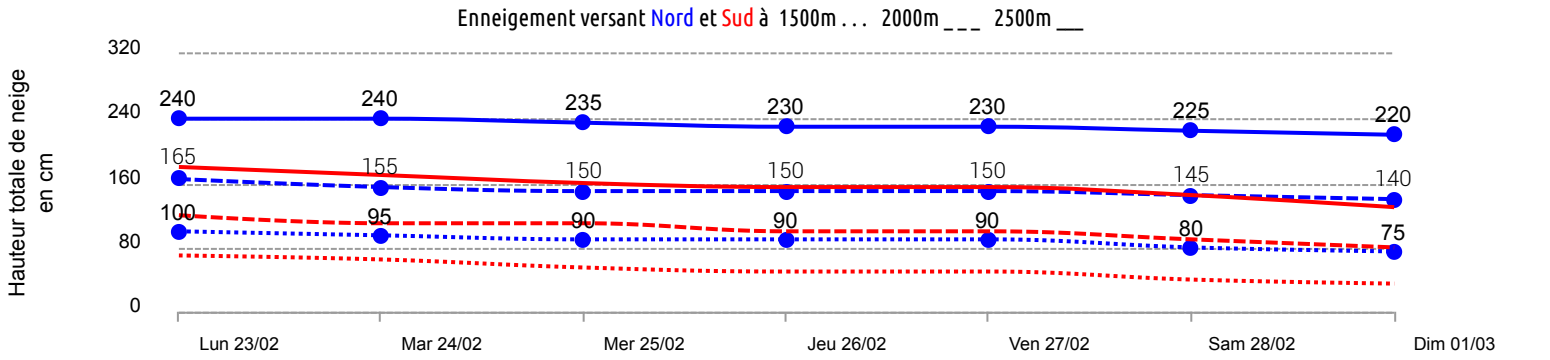

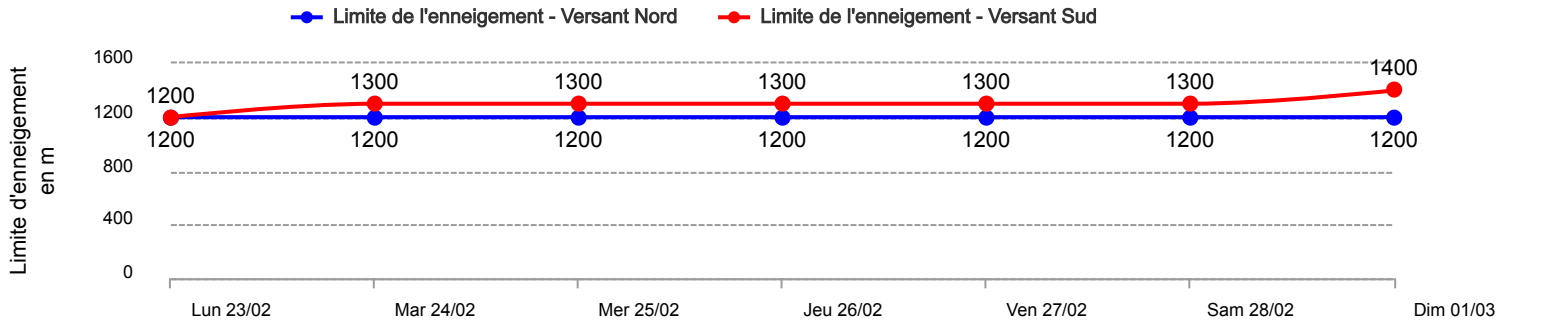

Pour consulter la vigilance en cours, veuillez vous rendre sur le site https://vigilance.meteofrance.fr/fr

Météo-France - 73 avenue de Paris, 94165 Saint-Mandé cedex - Contact : contact@meteo.fr

Rédigé par Météo-France avec la contribution des observateurs du réseau nivo-météorologiques. Partenariat : ANMSM (Maires de Stations de Montagne), DSF (Domaines Skiables de France), ADSP (Directeurs de Pistes et de la Sécurité des Stations de Sports d'Hiver) et autres acteurs de la montagne.

Bulletin neige & avalanches par téléphone au
0 892 68 10 20 Service 0,35 € / min + prix appel