GOBIERNO DE ESPAÑA
VICEPRESIDENCIA TERCERA DEL GOBIERNO
MINISTERIO PARA LA TRANSICIÓN ECOLÓGICA Y EL RETO DEMOGRÁFICO

Boletín de información nivológica y de peligro de aludes

Pirineo Navarro y Aragonés

aemet Agencia Estatal de Meteorología

lunes, 2 de marzo de 2026

Pronóstico hasta las 24 horas del martes, día 3 de marzo

(Válido fuera de pistas de esquí balizadas y abiertas)

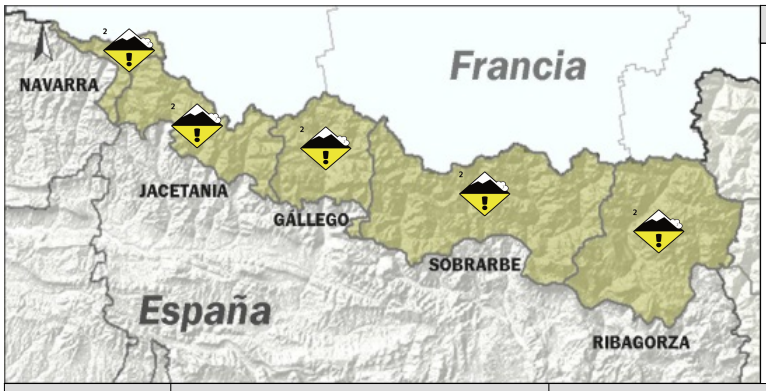

Problemas de aludes

Placas de viento

Nieve húmeda

Macizo	Peligro	Problemas de aludes, cota, orientación, tamaño	Innivación observada (m)
Navarra	2 Limitado	Placas de viento: 2000; N, E, S; 2 Nieve húmeda: 2000; N, O, E, S; 2	2026-03-02 N S Cota más baja caras N
Jacetania	2 Limitado	Placas de viento: 2200; N, E, S; 2 Nieve húmeda: 2200; N, O, E, S; 2	2026-03-02 N S Cota más baja caras N
Gállego	2 Limitado	Placas de viento: 2200; N, E, S; 2 Nieve húmeda: 2200; N, O, E, S; 2	2026-03-02 N S Cota más baja caras N

AEMET. Se autoriza la reproducción de su contenido citando la fuente.

Boletín de información nivológica y de peligro de aludes

Pirineo Navarro y Aragonés

Sobrarbe	**Limitado**	**Placas de viento** 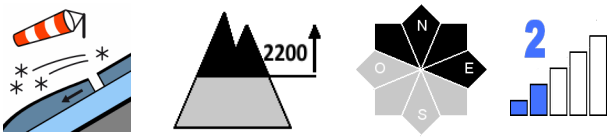 **Nieve húmeda** 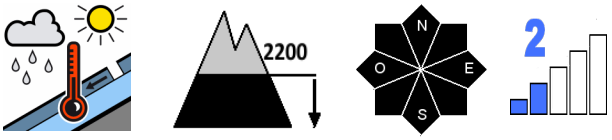	2026-03-02 Cota más baja caras N
Ribagorza	**Limitado**	**Placas de viento** 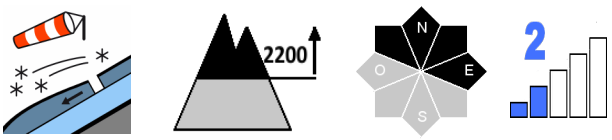 **Nieve húmeda** 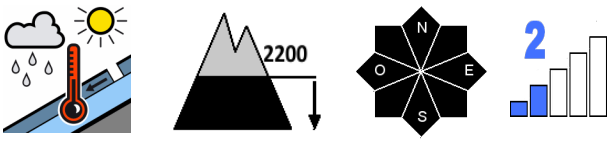	2026-03-02 Cota más baja caras N

Estado del manto y observaciones recientes

En la red de observación hoy se han vuelto a registrar nuevas pérdidas de espesor, en torno a 5-10 cm. Aún con todo, los espesores se encuentran por encima de lo que sería habitual a estas alturas de la temporada.
Nieve continúa desde 1300-1400 m en N, 1500-1600 m en S. Muy abundante desde cotas medias, aunque con perdida notable en las solanas inclinadas.
Manto primaveral en solanas, con buen rehielo nocturno y humedecimiento durante el día en cotas medias y altas. En umbrías manto seco, venteado con placas sobre facetas y costras a la vista en cotas medias y altas.
En cotas altas, hay aún algunas placas de viento, en zonas específicas protegidas del viento. Estas placas son poco reactivas y de tamaños pequeños generalmente, aunque en algún caso aislado pueden ser medianas. Bajo estas placas se encuentra un "sándwich" de costras y facetas. En las zonas erosionadas por el viento, este "sándwich" está directamente en superficie.
En umbrías de cotas altas la base del manto aún presenta capas débiles persistentes, pero de momento sin actividad natural ni accidental.

No se han reportado aludes en las últimas 24 h.

Evolución del manto y peligro de aludes para el martes, día 3

Problema de nieve húmeda y deslizamientos basales. Problema de placas de viento y capas débiles persistentes en cotas altas.

En cotas medias y bajas, se espera que el rehielo no sea tan efectivo como en días anteriores, siendo probables los aludes espontáneos de nieve húmeda desde primeras horas, de tamaño 1 (pequeño) ó 2 (mediano), así como los deslizamientos basales en zonas herbosas o de roca lisa, que podrían movilizar una cantidad de nieve considerable y alcanzar localmente el

AEMET. Se autoriza la reproducción de su contenido citando la fuente.

tamaño 3 (grande).

Mañana martes podrán caer algunos chubascos de nieve por encima de 1700-1800 m, con vientos del sureste, con lo que se podrían formar algunas placas de viento. Así, en cotas altas podría caer algún alud de placa de viento, de tamaño 1, pequeño, sin capacidad de enterrar a una persona, pero sí de hacernos perder el equilibrio. Además, todavía quedan placas de formación más antigua, sobre todo en umbrías, que podrían reaccionar ante sobrecargas fuertes (paso de dos o más esquiadores sin respetar la distancia de seguridad) y en caso de que colapsen serían posibles los aludes de tamaño 2 (mediano), o incluso 3 (grande) en caso de afectar a niveles inferiores y fracturar alguna capa débil en profundidad.

Predicción meteorológica para el martes, día 3

Pirineo navarro:
Intervalos nubosos, tendiendo a poco nuboso o despejado a últimas horas. Calima. No se descartan chubascos ocasionales por la tarde que podrían venir acompañados de barro. Cota de nieve: 1800-2000 metros.
No se descarta alguna tormenta acompañando a los chubascos.
Temperaturas sin apenas cambios. Alguna helada débil en cumbres.
Viento flojo o moderado del sureste.
Pirineo aragonés:
Intervalos nubosos, tendiendo a poco nuboso o despejado a últimas horas. Calima. No se descartan precipitaciones débiles y ocasionales, que podrían ser en forma de chubascos y venir acompañadas de barro. Cota de nieve en torno a 1700-2000 metros.
Temperaturas mínimas en ligero o moderado ascenso. Máximas sin cambios o en ligero ascenso. Heladas débiles en cotas altas, localmente moderadas en cumbres.
Viento generalmente flojo, con predominio del sureste.

Datos en la atmósfera libre:

Altitud de la isoterma de 0 ºC: 2500 m
Altitud de la isoterma de -10 ºC: 3900 m

Viento a 1500 m: SE 10 km/h
Viento a 3000 m: SE 20 km/h

Evolución para el miércoles día 4

Nivel de peligro sin cambios o en ligero ascenso.

(Información elaborada a partir de los datos recibidos de los refugios de Linza, Lizara, Panticosa, Góriz, Pineta, Estós, Angel Orús, Cap de Llauset y Belagua, de las estaciones de esquí de Formigal y Panticosa (lagos), de la estación de esquí de fondo de Llanos del Hospital y de Ordesa Pradera)

Escala europea de peligro de aludes

Débil Limitado Notable Fuerte Muy Fuerte

Problemas de aludes

Nieve reciente Placas de viento Capas débiles persistentes Nieve húmeda Deslizamientos basales Sin problema evidente

Nota1: Se recuerda que, siempre que haya nieve, la ausencia total de peligro no existe. Hay que tener presente que en circunstancias desfavorables, con aludes de tamaño 1 (alud pequeño o colada) y tamaño 2 (alud mediano), se pueden sufrir severos daños personales.

AEMET. Se autoriza la reproducción de su contenido citando la fuente.

Nota2: Los BPA se elaboran en base a información meteorológica así como al estado del manto nivoso a través de sondeos puntuales. Se advierte a los usuarios de la variabilidad de esta información al extrapolarla a zonas extensas de montaña. Por ello, AEMET no se hace responsable de su uso para la toma de decisiones que conciernen a la seguridad personal, ni de los riesgos físicos o materiales de ellas derivadas.

AEMET. Se autoriza la reproducción de su contenido citando la fuente.