Dienstag 03.03.2026

Veröffentlicht am 02.03.2026 um 17:00

Vormittag

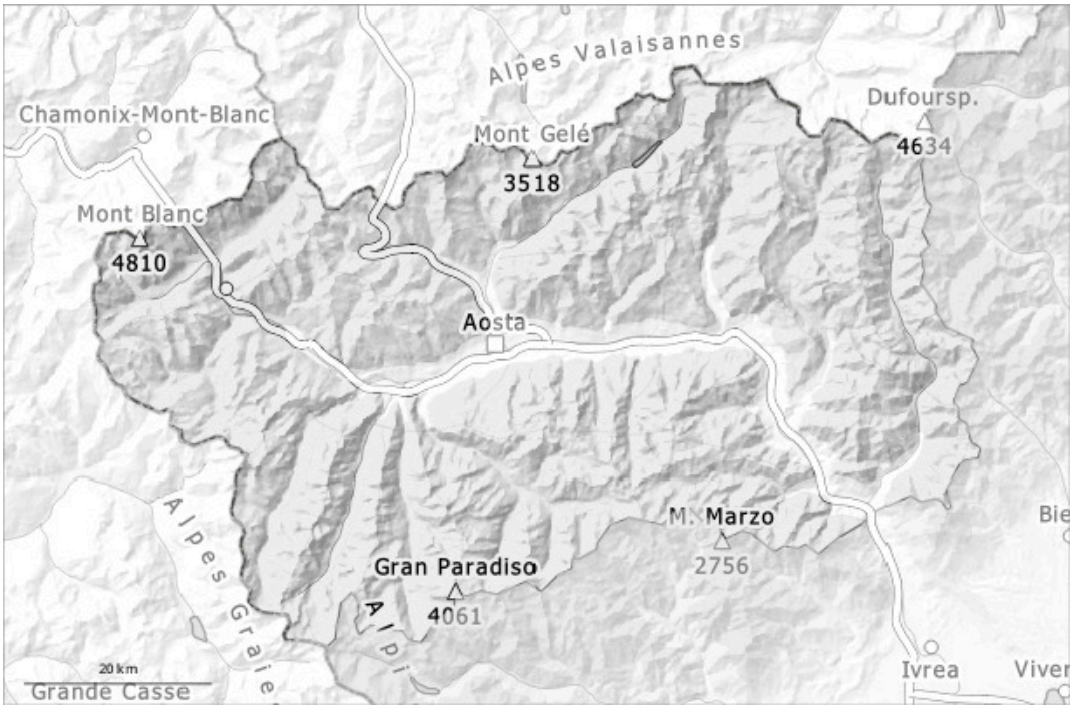

Nachmittag

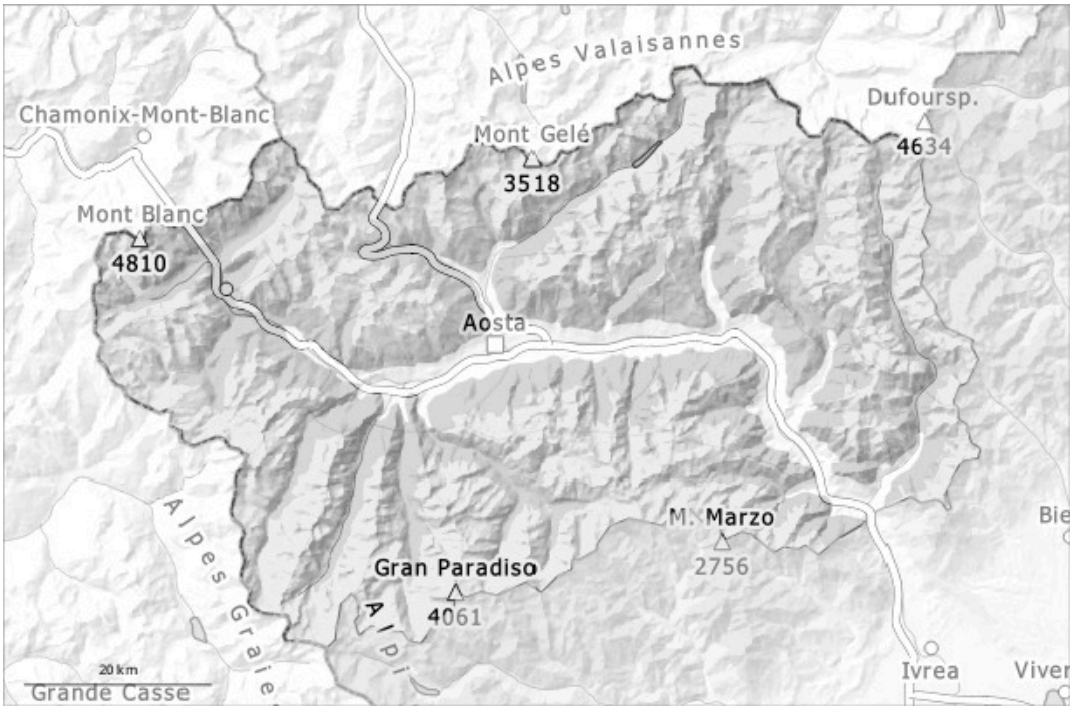

1	2	3	4	5
gering	mäßig	erheblich	groß	sehr groß

Gefahrenstufe 2 - Mäßig

AM:

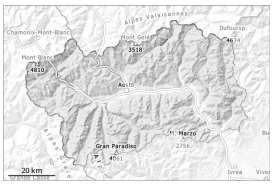

Tendenz: Lawinengefahr bleibt gleich
am Mittwoch, den 04.03.2026

Altschnee

2400m

PM:

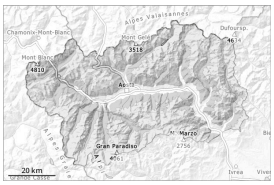

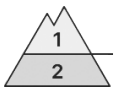

2400m

Tendenz: Lawinengefahr bleibt gleich
am Mittwoch, den 04.03.2026

Nassschnee

2400m
2100m

Altschnee

2400m

Die Tourenverhältnisse sind meist günstig.

Auf der harten Schneeoberfläche besteht im Steilgelände Absturzgefahr.
Tiefer in der Schneedecke sind Schwachschichten vorhanden. Lawinen können sehr vereinzelt in tiefen Schichten ausgelöst werden und mittlere Größe erreichen. Diese Gefahrenstellen liegen besonders an Übergängen von wenig zu viel Schnee sowie an Übergängen in Rinnen und Mulden.
In tiefen und mittleren Lagen sind im Tagesverlauf nur noch vereinzelt kleine und vereinzelt mittlere feuchte und nasse Lawinen möglich, v.a. aus extrem steilen noch nicht vollständig entladenen Einzugsgebieten.

Schneedecke

Gefahrenmuster gm.1: bodennahe schwachschicht | gm.10: frühjahrssituation

Die Wetterbedingungen begünstigten v.a. an sehr steilen Sonnenhängen eine Verfestigung der Schneedecke. Der obere Teil der Schneedecke ist weitgehend stabil, mit einer oft tragfähigen Schmelzharschkruste an der Oberfläche.
Seit gestern fielen oberhalb von rund 1600 m 2 bis 5 cm Schnee, lokal auch weniger. Bis zu 10 cm in den Grenzgebieten zum Piemont.
Besonders steile Schattenhänge hohe Lagen und Hochgebirge: In der Altschneedecke sind Schwachschichten vorhanden.
In Kamm- und Passlagen liegen je nach Windeinfluss sehr unterschiedliche Schneehöhen.

Tendenz

> Die Verhältnisse für Touren und zum Freeriden sind recht günstig. Auf der harten Schneeoberfläche besteht im Steilgelände Absturzgefahr.