Dienstag 03.03.2026

Veröffentlicht am 02.03.2026 um 17:00

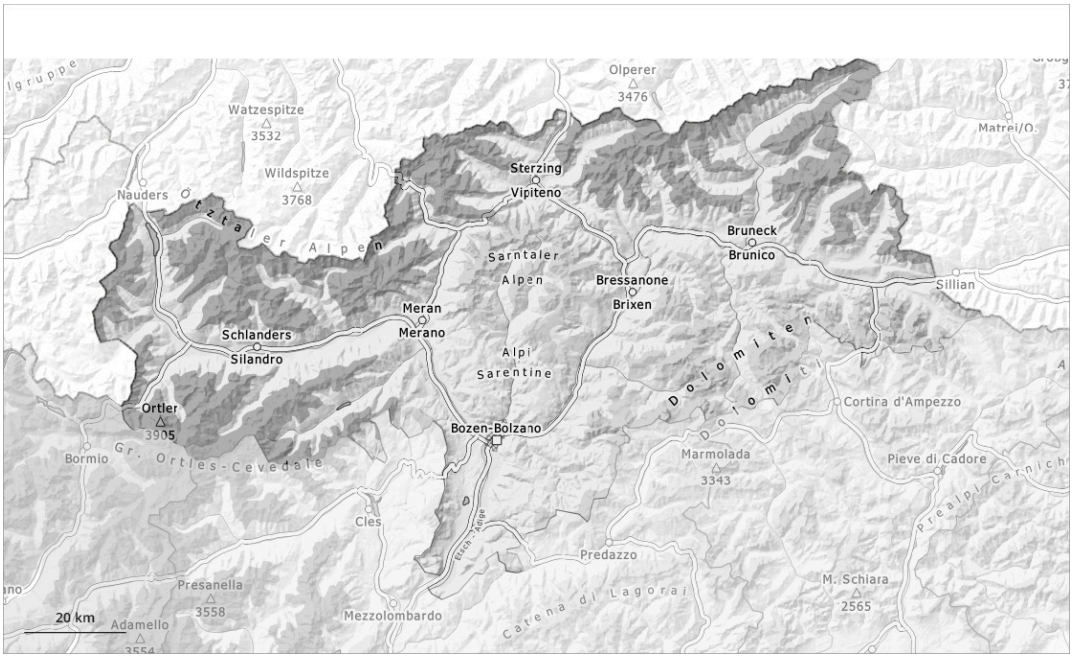

1	2	3	4	5
gering	mäßig	erheblich	groß	sehr groß

Gefahrenstufe 3 - Erheblich

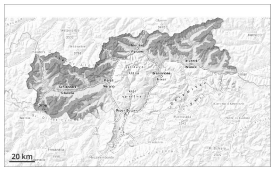

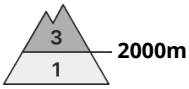

Tendenz: Lawinengefahr bleibt gleich
am Mittwoch, den 04.03.2026

Altschnee

Schwacher Altschnee ist die Hauptgefahr.

Lawinen können im Altschnee ausgelöst werden und groß werden. Dies bereits durch einzelne Wintersportler. Die Gefahrenstellen liegen besonders an West-, Nord- und Osthängen oberhalb von rund 2000 m sowie an allen Expositionen in der Höhe. Vorsicht vor allem an Übergängen von wenig zu viel Schnee. Wummgeräusche können auf die Gefahr hinweisen. Fernauslösungen sind möglich. In der Sturzbahn können Lawinen den nassen Schnee mitreißen. Dies verlängert die Auslaufstrecken der Lawinen.

Die nächtliche Abstrahlung ist stark eingeschränkt. Es sind unterhalb von rund 2200 m einzelne kleine und vereinzelt mittlere nasse Lawinen möglich.

Schneedecke

Gefahrenmuster gm.1: bodennahe schwachschicht | gm.10: frühjahrssituation

Schattenhänge: In der Altschneedecke sind vor allem an West-, Nord- und Osthängen ausgeprägte Schwachschichten vorhanden.

Die Schneeoberfläche gefriert nur knapp. Die Wetterbedingungen führten unterhalb von rund 2200 m zu einer Durchnässung der Schneedecke.

Tendenz

Vorsicht vor schwachem Altschnee. Einzelne Wintersportler können weiterhin Lawinen auslösen.

Leichter Anstieg der Gefahr von nassen Lawinen mit der tageszeitlichen Erwärmung und der Sonneneinstrahlung.

Gefahrenstufe 2 - Mäßig

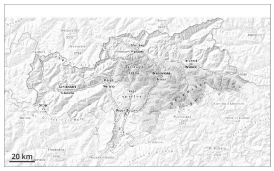

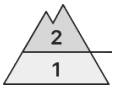

Tendenz: Lawinengefahr bleibt gleich
am Mittwoch, den 04.03.2026

Altschnee

Schwachen Altschnee beachten.

Lawinen können teilweise im Altschnee ausgelöst werden und an West-, Nord- und Osthängen recht groß werden. Dies teilweise schon durch einzelne Wintersportler. Die Gefahrenstellen liegen vor allem oberhalb von rund 2000 m. Vorsicht vor allem an Übergängen von wenig zu viel Schnee wie z.B. bei der Einfahrt in Rinnen und Mulden. Solche Gefahrenstellen sind für Anfänger kaum zu erkennen. Im selten befahrenen Tourengelände ist die Auslösebereitschaft höher.

Die nächtliche Abstrahlung ist reduziert. Es sind unterhalb von rund 2200 m einzelne meist kleine nasse Lawinen möglich.

Schneedecke

Gefahrenmuster gm.1: bodennahe schwachschicht | gm.10: frühjahrssituation

Schattenhänge: In der Altschneedecke sind vor allem an West-, Nord- und Osthängen ausgeprägte Schwachschichten vorhanden. Dies besonders oberhalb von rund 2000 m.

Die Schneeoberfläche gefriert nur knapp. Die Wetterbedingungen führten unterhalb von rund 2200 m zu einer Durchnässung der Schneedecke.

Tendenz

Schwachen Altschnee beachten. Leichter Anstieg der Gefahr von nassen Lawinen mit der tageszeitlichen Erwärmung und der Sonneneinstrahlung.

Gefahrenstufe 2 - Mäßig

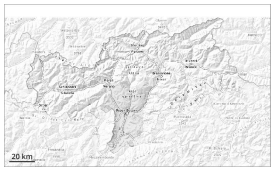

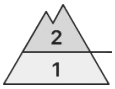

Waldgrenze

Tendenz: Lawinengefahr bleibt gleich
am Mittwoch, den 04.03.2026

Altschnee

Waldgrenze

Schwachschichten im Altschnee können vereinzelt noch ausgelöst werden.

Lawinen können vereinzelt im Altschnee ausgelöst werden und an Nordwest-, Nord- und Nordosthängen vereinzelt mittlere Größe erreichen. Dies durch einzelne Wintersportler. In der Sturzbahn können Lawinen den nassen Schnee mitreißen.

Mit der tageszeitlichen Erwärmung sind einzelne nasse Lawinen möglich.

Schneedecke

Gefahrenmuster gm.1: bodennahe schwachschicht | gm.10: frühjahrssituation

In der Altschneedecke sind vor allem an West-, Nord- und Osthängen ausgeprägte Schwachschichten vorhanden.

Die nächtliche Abstrahlung ist reduziert. Die Wetterbedingungen führen im Tagesverlauf zu einer Durchnässung der Schneedecke.

Tendenz

Schwachen Altschnee und Nassschnee beachten.