ICGC Institut Cartogràfic i Geològic de Catalunya

Servei Meteorològic de Catalunya meteo.cat

Boletín de peligro de aludes para el Pirineo de Catalunya
Del 02/03/2026 al 03/03/2026

(Válido fuera pistas de esquí y zonas no controladas)

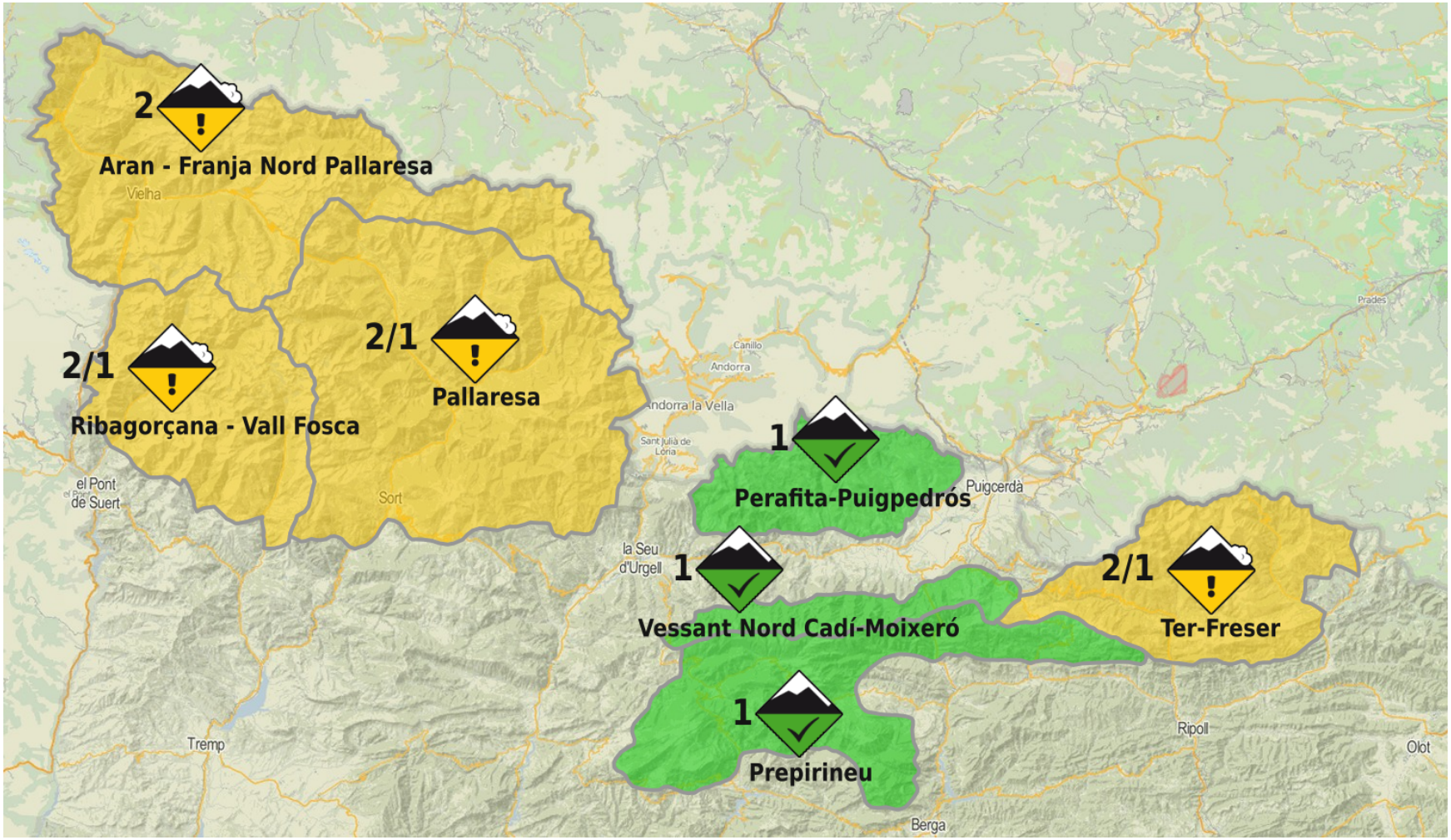

5 MUY FUERTE	4 FUERTE	3 NOTABLE	2 LIMITADO	1 DÉBIL

ICGC Institut Cartogràfic i Geològic de Catalunya

Servei Meteorològic de Catalunya

Boletín de peligro de aludes Aran - Franja Nord Pallaresa Del 02/03/2026 al 03/03/2026

(Válido fuera pistas de esquí y zonas no controladas)

LIMITADO (2).

Situación primaria

Deslizamientos basales **Distribución** **Tamaño** **Origen** **Tendencia**

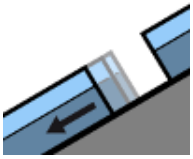

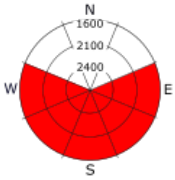

Situación secundaria

Nieve húmeda **Distribución** **Tamaño** **Origen** **Tendencia**

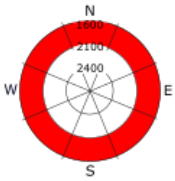

Estado del manto nivoso

Tras el ciclo de deslizamientos basales de la semana pasada, estos volverán a reactivarse progresivamente. Son más probables a partir de mediodía, mientras que por la mañana, si la noche no se ha nublado por completo, el manto quizá el martes se presente rehelado. Serán de tamaño 2, mediano, suficiente para enterrar a una persona, puntualmente mayor. Se desprenden de terreno soleado, de fuerte pendiente, liso y herboso o rocoso, y al pie de paredes rocosas. Se debe evitar el terreno bajo grietas, pueden indicar condiciones de deslizamiento del manto sobre el suelo. El martes podría caer algún chubasco de nieve por encima de 1.700-1.900 m, pero no afectará a la estabilidad del manto por encima de esta cota; en condiciones de lluvia o niebla, por debajo de 2.000 m podría caer algún alud de nieve húmeda de tamaño 1, pequeño, sin capacidad de enterrar a una persona, pero sí de hacernos perder el equilibrio. No se descarta en cotas más altas y umbrías algún alud de placa a nuestro paso.

Distribución del manto nivoso

Hay nieve por encima de unos 1.400 m a umbrías y 1.600 m a solanas. Los espesores a unos 2.200 m son superiores a los normales y rondan los 120-140 cm en el norte de Aran y los 160-200 cm en la Franja Norte Pallaresa y en el sur de Aran, puntualmente superiores.

Tendencia para las próximas 48-72h

En los próximos días se puede acumular algo de nieve reciente húmeda y formarse alguna pequeña placa de viento por viento del S y del E. Peligro EN LEVE AUMENTO.

El próximo boletín será emitido el día 2026-03-03

5 MUY FUERTE	4 FUERTE	3 NOTABLE	2 LIMITADO	1 DÉBIL

EAWS EUROPEAN AVALANCHE WARNING SERVICES

ICGC Institut Cartogràfic i Geològic de Catalunya

Servei Meteorològic de Catalunya

Boletín de peligro de aludes Ribagorçana - Vall Fosca Del 02/03/2026 al 03/03/2026

(Válido fuera pistas de esquí y zonas no controladas)

LIMITADO (2) de mediodía hasta el anochecer. DÉBIL (1) durante el resto.

Situación primaria

Deslizamientos basales

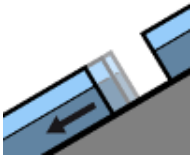

Distribución

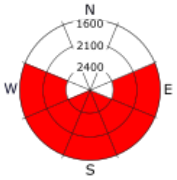

Tamaño

Origen

Tendencia

Estado del manto nivoso

Tras el ciclo de deslizamientos basales de la semana pasada, estos volverán a reactivarse progresivamente. Son más probables a partir de mediodía, mientras que por la mañana el manto estará bastante estable por rehielo nocturno. Serán poco frecuentes y alcanzarán tamaño 2, mediano, suficiente para enterrar a una persona, puntualmente mayor. Se desprenden de terreno soleado, de fuerte pendiente, liso y herboso o rocoso, y al pie de paredes rocosas. Se debe evitar el terreno bajo grietas, ya que pueden indicar condiciones de deslizamiento del manto sobre el suelo. El martes podría caer aisladamente algún chubasco de nieve por encima de 1.700-1.900 m, pero no afectará a la estabilidad del manto por encima de esta cota; en estas condiciones de lluvia o niebla, por debajo de 2.000 m podría caer algún alud de nieve húmeda de tamaño 1, pequeño, sin capacidad de enterrar a una persona, pero sí de hacernos perder el equilibrio.

Distribución del manto nivoso

Hay nieve en el suelo a 1.500 m en terreno umbrío, y por encima de unos 1.700-1.800 m en laderas soleadas. El manto es esquiable por encima de unos 1.600 m en umbrías. Los espesores alcanzan los 100-140 cm en cotas medias. Estos valores son superiores a los normales para la época.

Tendencia para las próximas 48-72h

En los próximos días se puede acumular algo de nieve reciente húmeda y formarse alguna pequeña placa de viento por viento del S y del E. Peligro EN LEVE AUMENTO.

El próximo boletín será emitido el día 2026-03-03

5 MUY FUERTE	4 FUERTE	3 NOTABLE	2 LIMITADO	1 DÉBIL

EAWS EUROPEAN AVALANCHE WARNING SERVICES

ICGC Institut Cartogràfic i Geològic de Catalunya

Servei Meteorològic de Catalunya

Boletín de peligro de aludes Pallaresa
Del 02/03/2026 al 03/03/2026

(Válido fuera pistas de esquí y zonas no controladas)

LIMITADO (2) de mediodía hasta el anochecer. DÉBIL (1) durante el resto.

Situación primaria

Deslizamientos basales

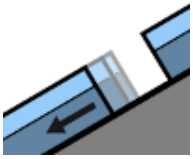

Distribución

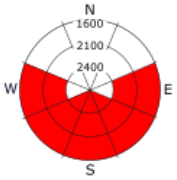

Tamaño

Origen

Tendencia

Estado del manto nivoso

Tras el ciclo de deslizamientos basales de la semana pasada, estos volverán a reactivarse progresivamente. Son más probables a partir de mediodía, mientras que por la mañana el manto estará bastante estable por rehielo nocturno. Serán poco frecuentes y alcanzarán tamaño 2, mediano, suficiente para enterrar a una persona, puntualmente mayor. Se desprenden de terreno soleado, de fuerte pendiente, liso y herboso o rocoso, y al pie de paredes rocosas. Se debe evitar el terreno bajo grietas, ya que pueden indicar condiciones de deslizamiento del manto sobre el suelo. El martes podría caer aisladamente algún chubasco de nieve por encima de 1.700-1.900 m, pero no afectará a la estabilidad del manto por encima de esta cota; en estas condiciones de lluvia o niebla, por debajo de 2.000 m podría caer algún alud de nieve húmeda de tamaño 1, pequeño, sin capacidad de enterrar a una persona, pero sí de hacernos perder el equilibrio.

Distribución del manto nivoso

Hay nieve en el suelo a 1.500 m en terreno umbrío, esquiable por encima de unos 1.600 m; en orientaciones soleadas la nieve está presente por encima de unos 1.700-1.800 m. Los espesores alcanzan los 110-150 cm en cotas medias.

Tendencia para las próximas 48-72h

En los próximos días se puede acumular algo de nieve reciente húmeda y formarse alguna pequeña placa de viento por viento del S y del E. Peligro EN LEVE AUMENTO.

El próximo boletín será emitido el día 2026-03-03

5 MUY FUERTE	4 FUERTE	3 NOTABLE	2 LIMITADO	1 DÉBIL

EAWS EUROPEAN AVALANCHE WARNING SERVICES

ICGC Institut Cartogràfic i Geològic de Catalunya

Servei Meteorològic de Catalunya meteo.cat

Boletín de peligro de aludes Perafita-Puigpedrós Del 02/03/2026 al 03/03/2026

(Válido fuera pistas de esquí y zonas no controladas)

DÉBIL (1).

Situación primaria

Nieve húmeda

Distribución

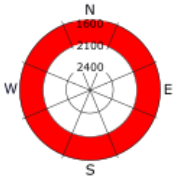

Tamaño

Origen

Tendencia

Estado del manto nivoso

El manto es estable y no hay condiciones para la actividad de aludes, más allá de alguna purga o alud de nieve húmeda de tamaño 1, pequeño, en caso de que el martes caiga algún chubasco, en forma de lluvia por debajo de unos 1.900 m. La madrugada del lunes se ha formado un poco de escarcha en las umbrías, pero no se prevé que vaya a más. Durante el lunes el manto ha estado rehelado y endurecido, ablandándose superficialmente por fusión a mediodía. La madrugada del martes quizá esté más nublada y el rehielo no sería tan eficiente. El martes podría caer algún chubasco de nieve por encima de 1.700-1.900 m, pero no afectará a la estabilidad del manto por encima de esta cota; en estas condiciones de lluvia o niebla por debajo de 2.000 m, podría caer puntualmente algún alud de nieve húmeda de tamaño 1, pequeño, sin capacidad de enterrar a una persona, pero sí de hacernos perder el equilibrio.

Distribución del manto nivoso

Hay nieve en el suelo por encima de unos 1.600 m, aunque en las solanas más derechas el manto va retrocediendo y la nieve está presente por encima de 1.800 m. Los espesores, aunque irregulares, rondan los 70-100 cm en cotas medias, con frecuentes deflaciones en orientaciones norte y oeste por encima del nivel del bosque. Son grosores muy por encima de los habituales por la época.

Tendencia para las próximas 48-72h

En los próximos días se puede acumular algo de nieve reciente húmeda y formarse alguna pequeña placa de viento por viento del S y del E. Peligro EN LEVE AUMENTO.

El próximo boletín será emitido el día 2026-03-03

5 MUY FUERTE	4 FUERTE	3 NOTABLE	2 LIMITADO	1 DÉBIL

EAWS EUROPEAN AVALANCHE WARNING SERVICES

ICGC Institut Cartogràfic i Geològic de Catalunya

Servei Meteorològic de Catalunya

Boletín de peligro de aludes
Vessant Nord Cadí-Moixeró
Del 02/03/2026 al 03/03/2026

(Válido fuera pistas de esquí y zonas no controladas)

DÉBIL (1).

Situación primaria

Nieve húmeda

Distribución

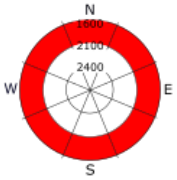

Tamaño

Origen

Tendencia

Estado del manto nivoso

El manto es estable y no hay condiciones para la actividad de aludes, más allá de alguna purga o alud de nieve húmeda tamaño 1, pequeño, en caso de que el martes caiga algún chubasco, en forma de lluvia por debajo de unos 1.900 m. Durante el lunes el manto ha estado rehelado y endurecido, ablandándose superficialmente por fusión a mediodía. La madrugada del martes quizá esté más nublada y el rehielo no sería tan eficiente. El martes podría caer algún chubasco de nieve por encima de 1.700-1.900 m, pero no afectará a la estabilidad del manto por encima de esta cota; en estas condiciones de lluvia o niebla por debajo de 2.000 m, podría caer puntualmente algún alud de nieve húmeda de tamaño 1, pequeño, sin capacidad de enterrar a una persona, pero sí de hacernos perder el equilibrio.

Distribución del manto nivoso

En umbrías hay nieve por encima de 1.500 m, esquiable por encima de unos 1.700 m. En solanas la nieve está presente por encima de 1.700 m. Los espesores están alrededor de 130-160 cm en cotas medias. Estos valores siguen siendo muy excedentarios para la época del año.

Tendencia para las próximas 48-72h

En los próximos días se puede acumular algo de nieve reciente húmeda y formarse alguna pequeña placa de viento por viento del S y del E. Peligro EN LEVE AUMENTO.

El próximo boletín será emitido el día 2026-03-03

5 MUY FUERTE	4 FUERTE	3 NOTABLE	2 LIMITADO	1 DÉBIL

EAWS EUROPEAN AVALANCHE WARNING SERVICES

ICGC Institut Cartogràfic i Geològic de Catalunya

Servei Meteorològic de Catalunya

Boletín de peligro de aludes Prepirineu
Del 02/03/2026 al 03/03/2026

(Válido fuera pistas de esquí y zonas no controladas)

DÉBIL (1).

Situación primaria

Nieve húmeda

Distribución

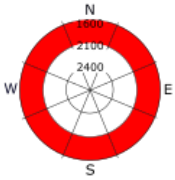

Tamaño

Origen

Tendencia

Estado del manto nivoso

El manto es estable y no hay condiciones para la actividad de aludes, más allá de alguna purga o alud de nieve húmeda tamaño 1, pequeño, en caso de que el martes caiga algún chubasco, en forma de lluvia por debajo de unos 1.900 m. Durante el lunes el manto ha sido rehelado y endurecido, ablandándose superficialmente por fusión a mediodía. La madrugada del martes quizá esté más nublada y el rehielo no sería tan eficiente. El martes podría caer algún chubasco de nieve por encima de 1.700-1.900 m, pero no afectará a la estabilidad del manto por encima de esta cota; en estas condiciones de lluvia o niebla por debajo de 2.000 m, podría caer puntualmente algún alud de nieve húmeda de tamaño 1, pequeño, sin capacidad de enterrar a una persona, pero sí de hacernos perder el equilibrio.

Distribución del manto nivoso

Hay nieve desde 1.500 a 1.600 m esquiable a partir de unos 1.700 m en orientaciones umbrías. En solanas el manto está presente a partir de unos 1.700-1.800 m. Los grosores están alrededor de 90-110 cm a unos 2.200 m. Aparecen deflaciones por encima del nivel del bosque, sobre todo en lugares bien expuestos al viento de norte y oeste.

Tendencia para las próximas 48-72h

En los próximos días se puede acumular algo de nieve reciente húmeda y formarse alguna pequeña placa de viento por viento del S y del E. Peligro EN LEVE AUMENTO.

El próximo boletín será emitido el día 2026-03-03

5 MUY FUERTE	4 FUERTE	3 NOTABLE	2 LIMITADO	1 DÉBIL

EAWS EUROPEAN AVALANCHE WARNING SERVICES

ICGC Institut Cartogràfic i Geològic de Catalunya

Servei Meteorològic de Catalunya meteo.cat

Boletín de peligro de aludes Ter-Freser Del 02/03/2026 al 03/03/2026

(Válido fuera pistas de esquí y zonas no controladas)

LIMITADO (2) de mediodía hasta el anochecer. DÉBIL (1) durante el resto.

Situación primaria

Deslizamientos basales **Distribución** **Tamaño** **Origen** **Tendencia**

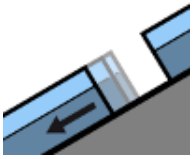

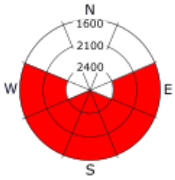

Situación secundaria

Nieve venteada **Distribución** **Tamaño** **Origen** **Tendencia**

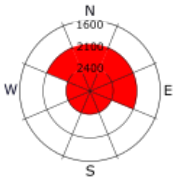

Estado del manto nivoso

Tras el ciclo de deslizamientos basales de la semana pasada, estos volverán a reactivarse progresivamente. Son más probables a partir de mediodía, mientras que por la mañana el manto estará bastante estable por rehielo nocturno. Serán poco frecuentes y alcanzarán tamaño 2, mediano, suficiente para enterrar a una persona, puntualmente mayor. Se desprenden de terreno soleado, de fuerte pendiente, liso y herboso o rocoso, y al pie de paredes rocosas. Se debe evitar el terreno bajo grietas, ya que pueden indicar condiciones de deslizamiento del manto sobre el suelo. Aparte, el martes podría caer algún chubasco de nieve por encima de 1.700-1.900 m, con viento de sur y este; se podría formar alguna placa de viento sobre algo de nieve granulada que cayó el sábado. Así en cotas altas podría caer algún alud de placa de viento, de tamaño 1, pequeño, sin capacidad de enterrar a una persona, pero sí de hacernos perder el equilibrio.

Distribución del manto nivoso

El manto nivoso presenta grosores muy excedentarios para la época del año. En lugares no afectados por el viento los grosores oscila entre 80-100 cm a unos 2.000 m y 200 cm por encima de 2.400 m. Es esquiable a partir de unos 1.600 m. Aparecen deflaciones por encima del nivel del bosque, sobre todo en lugares bien expuestos al viento de norte y oeste.

Tendencia para las próximas 48-72h

En los próximos días se puede acumular nieve reciente húmeda y formarse más placas de viento por viento del S y del E. Peligro EN AUMENTO.

El próximo boletín será emitido el día 2026-03-03

5 MUY FUERTE	4 FUERTE	3 NOTABLE	2 LIMITADO	1 DÉBIL

EAWS EUROPEAN AVALANCHE WARNING SERVICES