BUTLLETÍ DEL PERILL D'ALLAUS DEL PRINCIPAT D'ANDORRA

Elaborat el 02/03/2026 16:00
Propera actualització 03/03/2026 a les 16h

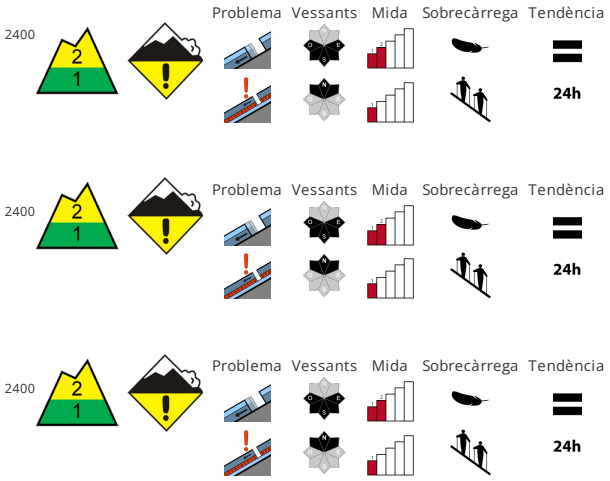

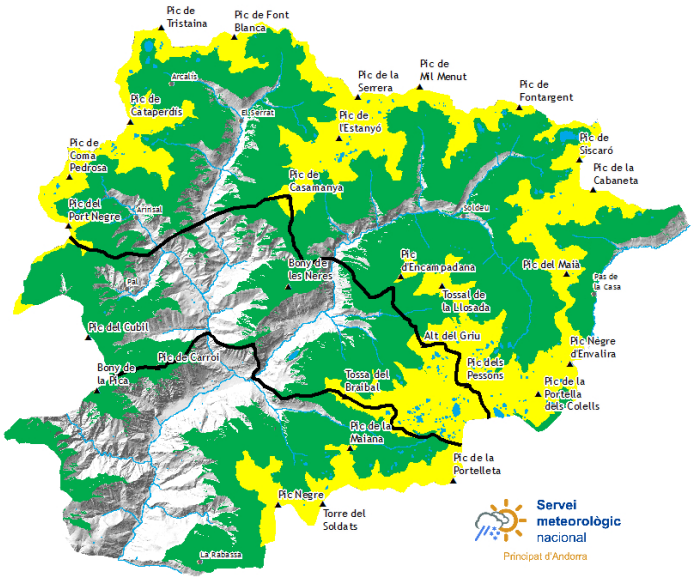

ESTABILITAT DEL MANTELL NIVAL

Poden desencadenar-se allaus de lliscament basal a qualsevol hora del dia o de la nit. Encara als vessants molt inclinats orientats a nord a la part central del mantell de neu hi ha capes febles. Això es dona especialment en vessants extremadament drets i per sobre dels 2400 m aproximadament. Aquestes poden de manera aïllada ser desencadenades de manera aïllada com a mínim per una sobrecàrrega forta i assolir mida mitjana. Després d'una nit serena, al matí les condicions són majoritàriament favorables. A causa de la crosta dura hi ha el perill de relliscar i caure als vessants inclinats. Amb l'augment de la temperatura diürna i la radiació solar, són possibles purgues de neu humida de mida petita.

QUALITAT DE LA NEU

Les condicions són primaverals. El refredament nocturn serà bo. Els gruixos de neu varien molt per sobre dels 2500 m aproximadament per la influència del vent. Evitar les zones amb esquerdes de lliscament basal.

GRUIXOS DEL MANTELL NIVAL FORA DE PISTA

Zona nord		Gruix neu		
Mantell Nival		1500m	2000m	2500m
N	1600 m	30 cm	150 cm	200 cm
S	1900 m	0 cm	100 cm	150 cm

Zona centre		Gruix neu		
Mantell Nival		1500m	2000m	2500m
N	1600 m	20 cm	150 cm	200 cm
S	1900 m	0 cm	100 cm	150 cm

Zona sud		Gruix neu		
Mantell Nival		1500m	2000m	2500m
N	1600 m	20 cm	120 cm	150 cm
S	1900 m	0 cm	60 cm	100 cm

Govern d'Andorra

EAWS EUROPEAN AVALANCHE WARNING SERVICES

Aquest butlletí ha estat elaborat seguint les normes i recomanacions de l'**European Avalanche Warning Services**, del qual el **Servei meteorològic Nacional** n'és membre

BUTLLETÍ DEL PERILL D'ALLAUS DEL PRINCIPAT D'ANDORRA

Servei meteorològic nacional
Principat d'Andorra

Informació detallada per espais naturals protegits

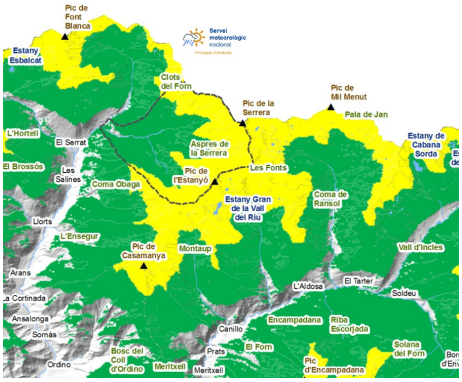

SORTENY

La neu poca neu nova del cap de setmana no ha canviat les condicions d´estabilitat. Trobem neu a tots els camins des de Llorts i l´accés amb esquís fins al Refugi és continu. La neu és dura al matí als vessants sud, es recomana anar equipat amb material de punxes per circular-hi. Als vessants nord hi ha neu pols reciclada (grans facetats) molt agradable d´esquiar. Aquesta neu reposa a sobre de plaques que amaguen algunes capes febles persistents als indrets més alts i escarpats. Tot i que aquestes només les tenim identificades en alguns indrets molt inclinats orientats al nord (obacs), les hem de tenir en compte per escollir el nostre itinerari amb seguretat i no perdre el costum de circular per indrets segurs.

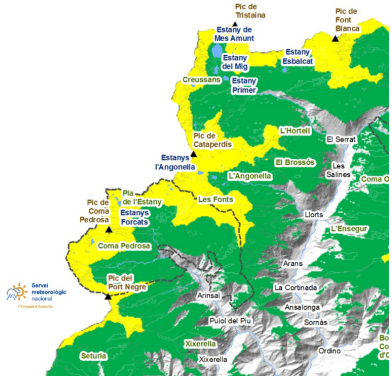

COMAPEDROSA

Haurem de vigilar a no relliscar a causa de la crosta de regel als vessants sud o a cotes baixes, però també als vessants obacs, on la neu pols amaga una crosta ventada dura. L´accés des d´Arinsal està quedant cada vegada amb menys neu, ja que el sol de tarda escalfa molt i la neu contínua cada vegada la trobem més amunt. A les parts altes del Parc, però, les condicions són molt bones i es poden fer nombroses excursions, sempre mantenint l´elecció acurada de l´itinerari i l´horari de les excursions.

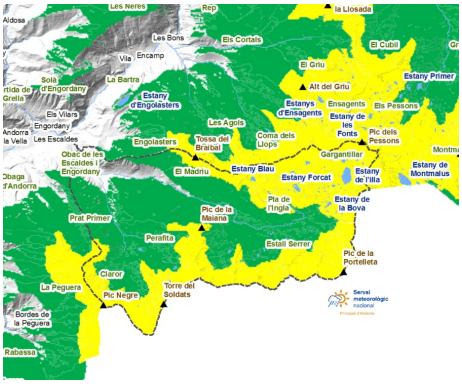

MADRIU-PERAFITA-CLAROR

Als vessants sud i a cotes baixes les condicions són primaverals, neu dura al matí i tova al migdia, amb formes típiques de fusió quan el sol incideix perpendicularment a la pendent. Als vessants nord i als indrets plans la neu es manté pols.

Govern d'Andorra

EAWS
EUROPEAN AVALANCHE WARNING SERVICES

Aquest butlletí ha estat elaborat seguint les normes i recomanacions de l'**European Avalanche Warning Services**, del qual el **Servei meteorològic Nacional** n'és membre

BUTLLETÍ DEL PERILL D'ALLAUS DEL PRINCIPAT D'ANDORRA

Servei meteorològic nacional
Principat d'Andorra

Gruixos de neu nova dels darrers dies (de les últimes 24h mesurat a les 06:00h UTC)

	26/02/2026	27/02/2026	28/02/2026	01/03/2026
FEDA (Central)	0 cm	0 cm	0 cm	0 cm
Engolasters - FEDA	0 cm	0 cm	0 cm	0 cm
Bony de les Neres	0 cm	0 cm	0 cm	0 cm
Sorteny	0 cm	0 cm	2 cm	0 cm
Perafita	0 cm	0 cm	0 cm	0 cm
Tossa Espiolets	0 cm	0 cm	1 cm	0 cm
Grau Roig - FEDA	0 cm	0 cm	0 cm	0 cm
Fontverd	0 cm	0 cm	0 cm	0 cm
Ransol - FEDA	0 cm	0 cm	2 cm	0 cm
Setúria	0 cm	0 cm	0 cm	0 cm
Caborreu	0 cm	0 cm	0 cm	0 cm
La Solana	0 cm	0 cm	5 cm	0 cm
Envalira Antenes	0 cm	0 cm	0 cm	0 cm
Vall del Riu FEDA	0 cm	0 cm	0 cm	0 cm