BUTLLETÍ DEL PERILL D'ALLAUS DEL PRINCIPAT D'ANDORRA

Elaborado el 02/03/2026 16:00
Proxima actualización 03/03/2026 a las 16h

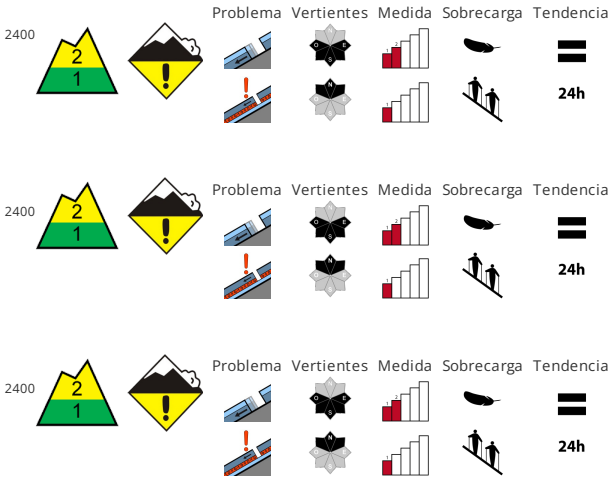

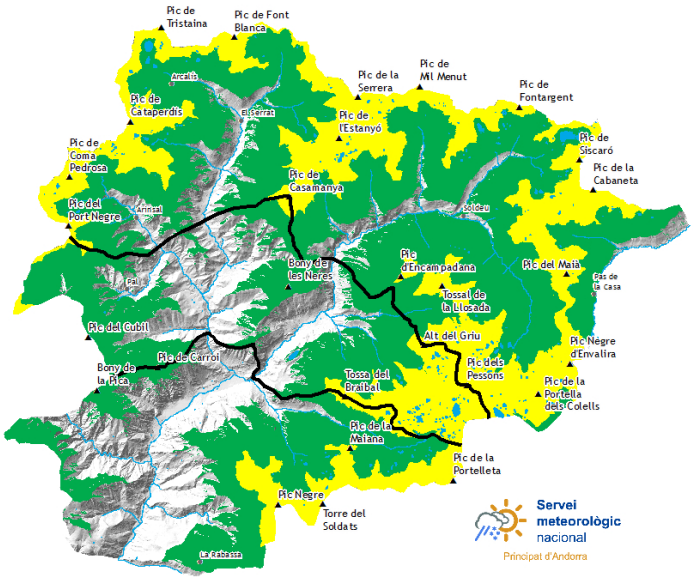

CALIDAD DE LA NIEVE

Pueden desencadenarse aludes de deslizamiento basal a cualquier hora del día o de la noche. Todavía en las laderas muy inclinadas orientadas a norte en la parte central del manto de nieve hay capas débiles. Esto se da especialmente en las laderas extremadamente pendientes y por encima de los 2400 m aproximadamente. Estos pueden de manera aislada ser desencadenadas de manera aislada como mínimo por una sobrecarga fuerte y alcanzar un tamaño mediano. Luego de una noche serena, por la mañana las condiciones son en su mayoría favorables. Debido a la costra dura hay el peligro de resbalar y caer en las laderas inclinadas. Con la subida de la temperatura diurna y la radiación solar, son posibles purgas de nieve húmeda de tamaño pequeño.

ESTABILIDAD DEL MANTO NIVOSO

Las condiciones son primaverales. El enfriamiento nocturno será bueno. Los espesores de nieve varían mucho por encima de los 2500 m aproximadamente por la influencia del viento. Evitar las zonas con grietas de deslizamiento basal.

ESPESORES DEL MANTO NIVOSO FUERA DE PISTA

Zona norte		Espesor nieve		
Manto Nival		1500m	2000m	2500m
N	1600 m	30 cm	150 cm	200 cm
S	1900 m	0 cm	100 cm	150 cm

zona centro		Espesor nieve		
Manto Nival		1500m	2000m	2500m
N	1600 m	20 cm	150 cm	200 cm
S	1900 m	0 cm	100 cm	150 cm

Zona sur		Espesor nieve		
Manto Nival		1500m	2000m	2500m
N	1600 m	20 cm	120 cm	150 cm
S	1900 m	0 cm	60 cm	100 cm

Govern d'Andorra

EAWS EUROPEAN AVALANCHE WARNING SERVICES

Aquest butlletí ha estat elaborat seguint les normes i recomanacions de l'**European Avalanche Warning Services**, del qual el **Servei meteorològic Nacional** n'és membre

BUTLLETÍ DEL PERILL D'ALLAUS DEL PRINCIPAT D'ANDORRA

Servei meteorològic nacional
Principat d'Andorra

Información detallada por espacios naturales protegidos

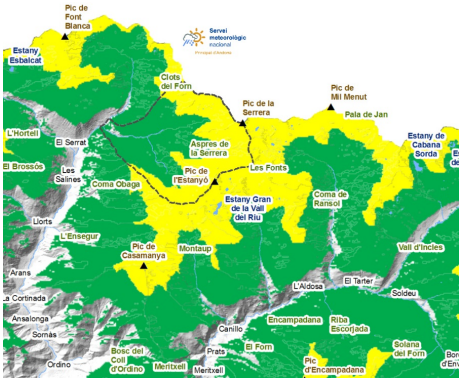

SORTENY

La nieve poca nieve nueva del fin de semana no ha cambiado las condiciones de estabilidad. Encontramos nieve en todos los caminos desde Llorts y el acceso con esquís hasta el Refugi es continuo. La nieve es dura por la mañana en las vertientes sur, se recomienda ir equipado con material de pinchos para circular. En las vertientes norte hay nieve polvo reciclado (grandes facetados) muy agradable de esquiar. Esta nieve reposa sobre placas que esconden algunas capas débiles persistentes en los lugares más altos y escarpados. Aunque éstas sólo las tenemos identificadas en algunos lugares muy inclinados orientados al norte (umbrías), debemos tenerlas en cuenta para escoger nuestro itinerario con seguridad y no perder la costumbre de circular por lugares seguros.

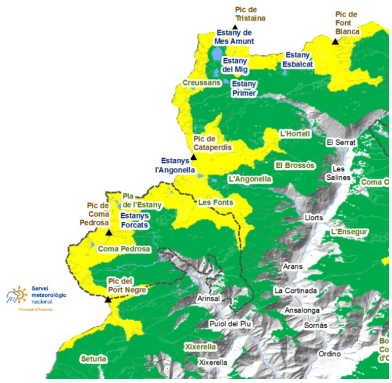

COMAPEDROSA

Deberemos vigilar a no resbalar debido a la corteza de rehielo en las vertientes sur o en cotas bajas, pero también en las vertientes umbrías, donde la nieve polvo esconde una corteza venteada dura. El acceso desde Arinsal está quedando cada vez con menos nieve, ya que el sol de tarde calienta mucho y la nieve continua cada vez la encontramos más arriba. Sin embargo, en las partes altas del Parque las condiciones son muy buenas y se pueden hacer numerosas excursiones, siempre manteniendo la elección cuidadosa del itinerario y el horario de las excursiones.

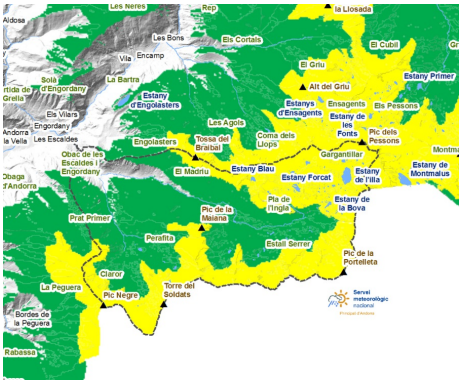

MADRIU-PERAFITA-CLAROR

En las vertientes sur y en cotas bajas las condiciones son primaverales, nieve dura por la mañana y blanda al mediodía, con formas típicas de fusión cuando el sol incide perpendicularmente a la pendiente. En las vertientes norte y en los lugares planos la nieve se mantiene polvo.

Govern d'Andorra

EAWS
EUROPEAN AVALANCHE WARNING SERVICES

Aquest butlletí ha estat elaborat seguint les normes i recomanacions de l'**European Avalanche Warning Services**, del qual el **Servei meteorològic Nacional** n'és membre

BUTLLETÍ DEL PERILL D'ALLAUS DEL PRINCIPAT D'ANDORRA

Servei meteorològic nacional
Principat d'Andorra

Espesores de nieve nueva de los últimos días (de las ultimas 24h mesurado a las 06:00h UTC)

	26/02/2026	27/02/2026	28/02/2026	01/03/2026
FEDA (Central)	0 cm	0 cm	0 cm	0 cm
Engolasters - FEDA	0 cm	0 cm	0 cm	0 cm
Bony de les Neres	0 cm	0 cm	0 cm	0 cm
Sorteny	0 cm	0 cm	2 cm	0 cm
Perafita	0 cm	0 cm	0 cm	0 cm
Tossa Espiolets	0 cm	0 cm	1 cm	0 cm
Grau Roig - FEDA	0 cm	0 cm	0 cm	0 cm
Fontverd	0 cm	0 cm	0 cm	0 cm
Ransol - FEDA	0 cm	0 cm	2 cm	0 cm
Setúria	0 cm	0 cm	0 cm	0 cm
Caborreu	0 cm	0 cm	0 cm	0 cm
La Solana	0 cm	0 cm	5 cm	0 cm
Envalira Antenes	0 cm	0 cm	0 cm	0 cm
Vall del Riu FEDA	0 cm	0 cm	0 cm	0 cm