BUTLLETÍ DEL PERILL D'ALLAUS DEL PRINCIPAT D'ANDORRA

Préparé le 02/03/2026 16:00
Prochaine mise à jour le 03/03/2026 à 16h

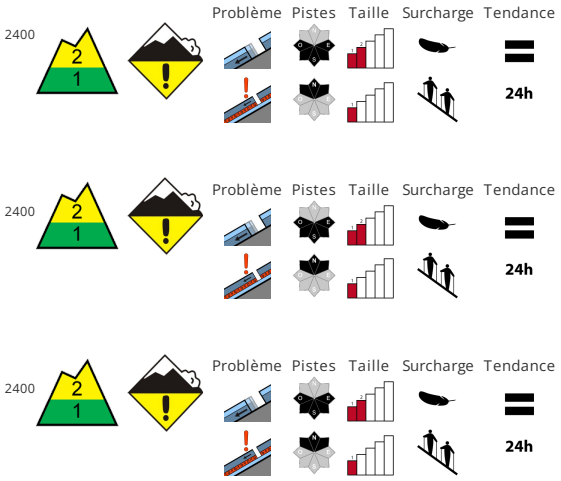

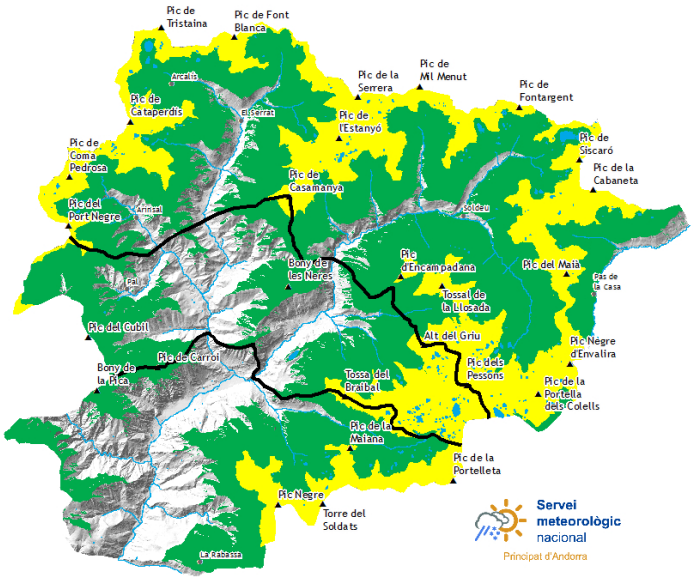

STABILITÉ DU MANTEAU NEIGEUX

Les avalanches de glissement peuvent se déclencher à tout moment du jour et de la nuit.. Au milieu du manteau neigeux des couches fragiles sont présentes ils se rencontrent , aussi sur les pentes très raides exposées au nord. Ceci surtout en terrain raide extrême et au-dessus d'environ 2400 m. Celles-ci peuvent de manière isolée être déchaîné de manière isolée avec en général une surcharge importante et atteindre une taille moyenne.. Les conditions sont en général favorables le matin après une nuit claire. Sur la croûte dure il existe en terrain raide un risque de chute.. Des coulées humides de petite taille sont ils sont possibles avec le réchauffement diurne et le rayonnement solaire.

QUALITÈ DE LA NEIGE

Les conditions sont printanières. Le rayonnement nocturne est bon.. On trouve suivant l'influence du vent des hauteurs de neiges très différentes au-dessus d'environ 2500 m. Les zones présentant des fissures de glissement doivent être évitées..

EPAISSEUR DE NEIGE HORS PISTE

Zone nord		Epaisseur de neige		
Nival manteau		1500m	2000m	2500m
N	1600 m	30 cm	150 cm	200 cm
S	1900 m	0 cm	100 cm	150 cm

Zone centre		Epaisseur de neige		
Nival manteau		1500m	2000m	2500m
N	1600 m	20 cm	150 cm	200 cm
S	1900 m	0 cm	100 cm	150 cm

Zone sud		Epaisseur de neige		
Nival manteau		1500m	2000m	2500m
N	1600 m	20 cm	120 cm	150 cm
S	1900 m	0 cm	60 cm	100 cm

BUTLLETÍ DEL PERILL D'ALLAUS DEL PRINCIPAT D'ANDORRA

Servei meteorològic nacional
Principat d'Andorra

Des informations détaillées par espace naturel protégé

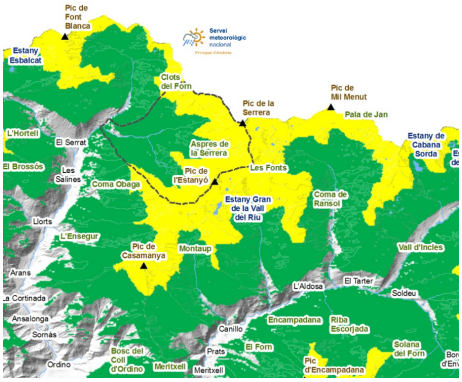

SORTENY

La petite neige fraîche du week-end n'a pas modifié les conditions de stabilité. Nous trouvons de la neige sur tous les sentiers depuis Llorts et l'accès à skis au Refuge est continu. La neige est dure le matin sur le versant sud, il est recommandé de s'équiper de matériel à crampons pour y circuler. Sur le versant nord on trouve de la poudreuse recyclée (grandes facettes) très agréable à skier. Cette neige repose sur des plaques qui cachent des couches fragiles persistantes dans les endroits les plus hauts et les plus raides. Bien que nous ne les ayons identifiés que dans certains endroits très inclinés orientés vers le nord (obacs), nous devons en tenir compte pour choisir notre itinéraire en toute sécurité et ne pas perdre l'habitude de conduire dans des endroits sûrs. , , , , , , , , , , ,

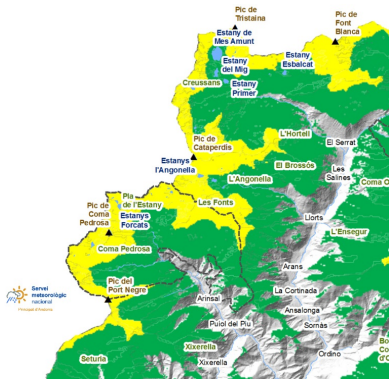

COMAPEDROSA

Il faudra faire attention à ne pas glisser à cause de la croûte de glace sur les versants sud ou à basse altitude, mais aussi sur les pentes opaques, où la poudreuse cache une croûte dure et venteuse. L'accès depuis Arinsal reçoit de moins en moins de neige, à mesure que le soleil de l'après-midi se réchauffe beaucoup et que nous trouvons de la neige continue plus haut. Dans les parties supérieures du Parc, cependant, les conditions sont très bonnes et de nombreuses excursions peuvent être réalisées, en respectant toujours le choix minutieux de l'itinéraire et du calendrier des excursions. , , , , ,

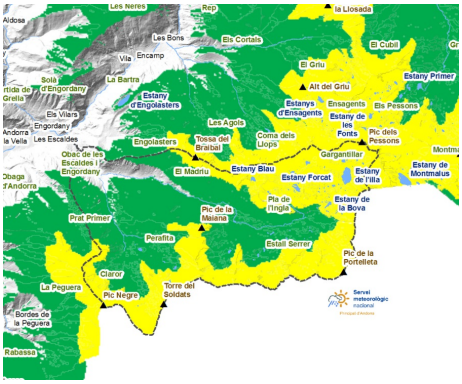

MADRIU-PERAFITA-CLAROR

Sur le versant sud et à basse altitude, les conditions sont printanières, neige dure le matin et neige molle l'après-midi, avec des formes typiques de fonte lorsque le soleil frappe perpendiculairement à la pente. Sur les versants nord et les plaines, la neige reste poudreuse. , , ,

Govern d'Andorra

EAWS
EUROPEAN AVALANCHE WARNING SERVICES

Aquest butlletí ha estat elaborat seguint les normes i recomanacions de l'**European Avalanche Warning Services**, del qual el **Servei meteorològic Nacional** n'és membre

BUTLLETÍ DEL PERILL D'ALLAUS DEL PRINCIPAT D'ANDORRA

Servei meteorològic nacional
Principat d'Andorra

Couche de neige fraiche des derniers jours (De 24 h mesurée à 06:00 h UTC)

	26/02/2026	27/02/2026	28/02/2026	01/03/2026
FEDA (Central)	0 cm	0 cm	0 cm	0 cm
Engolasters - FEDA	0 cm	0 cm	0 cm	0 cm
Bony de les Neres	0 cm	0 cm	0 cm	0 cm
Sorteny	0 cm	0 cm	2 cm	0 cm
Perafita	0 cm	0 cm	0 cm	0 cm
Tossa Espiolets	0 cm	0 cm	1 cm	0 cm
Grau Roig - FEDA	0 cm	0 cm	0 cm	0 cm
Fontverd	0 cm	0 cm	0 cm	0 cm
Ransol - FEDA	0 cm	0 cm	2 cm	0 cm
Setúria	0 cm	0 cm	0 cm	0 cm
Caborreu	0 cm	0 cm	0 cm	0 cm
La Solana	0 cm	0 cm	5 cm	0 cm
Envalira Antenes	0 cm	0 cm	0 cm	0 cm
Vall del Riu FEDA	0 cm	0 cm	0 cm	0 cm