Bulletin d'estimation du risque d'avalanche

(valable en dehors des pistes balisées et ouvertes)

MASSIF : Cinto Rotondo

Rédigé le lundi 2 mars 2026 à 15h

Estimation des risques pour le : MARDI 03 MARS

CONDITIONS PRINTANIÈRES DANS LES VERSANTS AU SOLEIL; QUELQUES STRUCTURES DE PLAQUES EN ALTITUDE EN VERSANTS OMBRAGÉS.

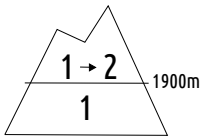

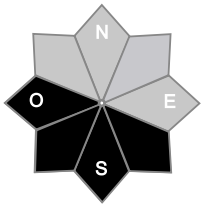

Au-dessus de 1900m indice de risque faible évoluant en limité, plus bas indice faible.

Départs spontanés : En neige humide, départs devenant nombreux dans les versants ensoleillés au fil de la journée.

Déclenchements provoqués : Rares structures de plaques en Nord à Nord-Est au-delà de 2000 m difficiles à déclencher.

Indices de risque : 5 très fort - 4 fort - 3 marqué - 2 limité - 1 faible -- En noir : les pentes les plus dangereuses

Stabilité du manteau neigeux

Situation avalancheuse typique : neige humide

Départs spontanés : après un bon regel nocturne en altitude à la faveur d'une nuit quasiment claire et encore longue, l'humidification reprend en journée avec les éclaircies matinales. Elle devrait toutefois être ralentie et limitée par l'arrivée de nuages. Quelques départs spontanés d'avalanches de taille petite à moyenne (taille 1 à 2) de neige humide restent possibles dans les pentes raides encore chargées et ensoleillées (parfois sablées) et vers les rochers/falaises. Une avalanche de fond de taille 2 (moyenne) sur les dalles rocheuses emportant la totalité du manteau neigeux en place jusqu'au sol peut céder spontanément .

Déclenchements provoqués : de rares plaques persistent dans les versants nord-ouest, nord et nord-est au-dessus de 2000/2200 mètres. Elles ont gagné en résistance mais elles reposent généralement sur des couches de neige sans cohésion (neige roulée). Souvent résistantes à de fortes surcharges, dans certaines secteurs bien ombragés et maintenus froids, un déclenchement est possible par surcharge répétée. Des glissements ponctuels en surface sur les pentes ensoleillées sous les skis ou les raquettes sont possibles..

Qualité de la neige

Qualification de l'enneigement : L'enneigement est excellent pour la saison au-dessus de 1600 m. Sur la Maniccia, à 2400 m d'altitude dans le massif du Rotondo, on mesure 2m80 de hauteur totale de neige.

Limite d'enneigement skiable : autour de 1500 m.

État de la neige : Mardi matin, bon regel nocturne des pentes humidifiées surtout en altitude et en versants ombragés avec une neige portante parfois dure (sauf en forêt et sur les zones en neige colorée). En journée, reprise de l'humidification au soleil avec une neige devenant lourde et humide (parfois pourrie) à basse altitude. En Nord, sous 2000 m, la surface du manteau neigeux ramollit lentement en cours de journée. Au-dessus de 2000/2200 m, neige restant dure/cartonnée surtout en approchant des sommets avec un peu de vieille poudreuse dense dans les zones abritées. Neige parfois glacée dans les zones érodées par les forts vents.
À noter la présence de corniches parfois volumineuses.

Aperçu météo pour le mardi 03 mars

	nuit	matin	après-midi	soir
Pluie-Neige				
Iso 0 °C	2 400 m	2 500 m	2 600 m	2 600 m
Vent 1500 m	10 km/h	15 km/h	20 km/h	15 km/h
Vent 3000 m	15 km/h	10 km/h	10 km/h	10 km/h

Épaisseur de neige hors-piste

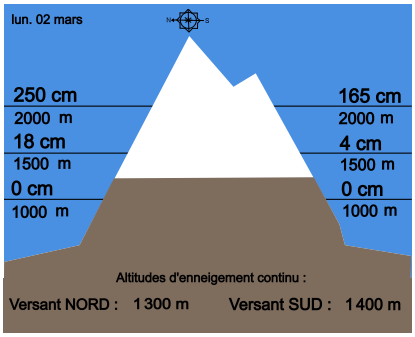

Précipitations à 1800 m

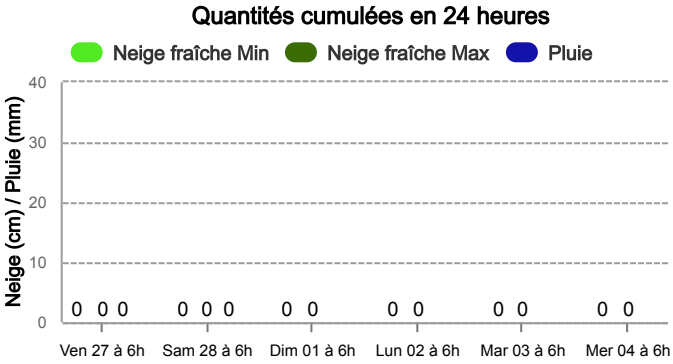

Tendance du mercredi 04 mars

Indice de risque limité

Des départs en neige humide restent possibles.

Pour consulter la vigilance en cours, veuillez vous rendre sur le site https://vigilance.meteofrance.fr/fr

Météo-France - 73 avenue de Paris, 94165 Saint-Mandé cedex - Contact : contact@meteo.fr

Rédigé par Météo-France avec la contribution des observateurs du réseau nivo-météorologiques. Partenariat : ANMSM (Maires de Stations de Montagne), DSF (Domaines Skiables de France), ADSP (Directeurs de Pistes et de la Sécurité des Stations de Sports d'Hiver) et autres acteurs de la montagne.

Bulletin neige & avalanches par téléphone au
0 892 68 10 20 Service 0,35 € / min + prix appel

RÉPUBLIQUE FRANÇAISE
Liberté Égalité Fraternité

METEO FRANCE
À VOS CÔTÉS, DANS UN CLIMAT QUI CHANGE

Bulletin d'estimation du risque d'avalanche

(valable en dehors des pistes balisées et ouvertes)

MASSIF : Cinto Rotondo

Rédigé le lundi 2 mars 2026 à 15h

Conditions nivo-météo des 7 derniers jours

	mar. 24/02				mer. 25/02				jeu. 26/02				ven. 27/02				sam. 28/02				dim. 01/03				lun. 02/03			
	03h	09h	15h	21h	03h	09h	15h	21h	03h	09h	15h	21h	03h	09h	15h	21h	03h	09h	15h	21h	03h	09h	15h	21h	03h	09h	15h	21h
Météo																												
Vent (km/h)	40	35	30	20	5	5	5	5	10	15	15	15	20	15	15	15	10	5	10	10	10	10	10	10	15	25	25	15
à 3000m																												
Vent (km/h)	25	20	10	5	5	5	10	5	5	5	5	5	10	10	10	5	5	5	10	5	5	5	10	5	10	15	20	10
à 1500m																												

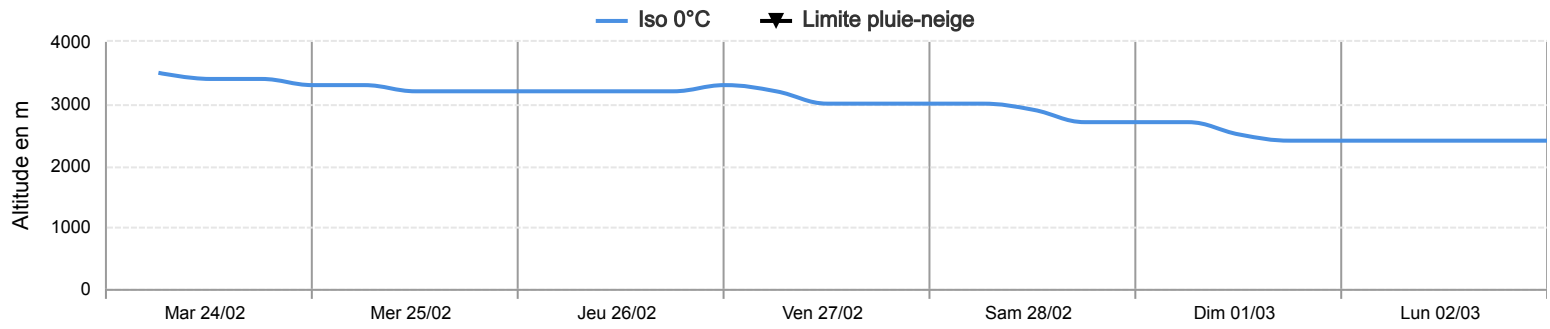

Neige fraîche à 06h

0 cm	0 cm	0 cm	0 cm	0 cm	0 cm

Risque d'avalanche	mar. 24/02	mer. 25/02	jeu. 26/02	ven. 27/02	sam. 28/02	dim. 01/03	lun. 02/03
	2	2	2	2	2	2	2

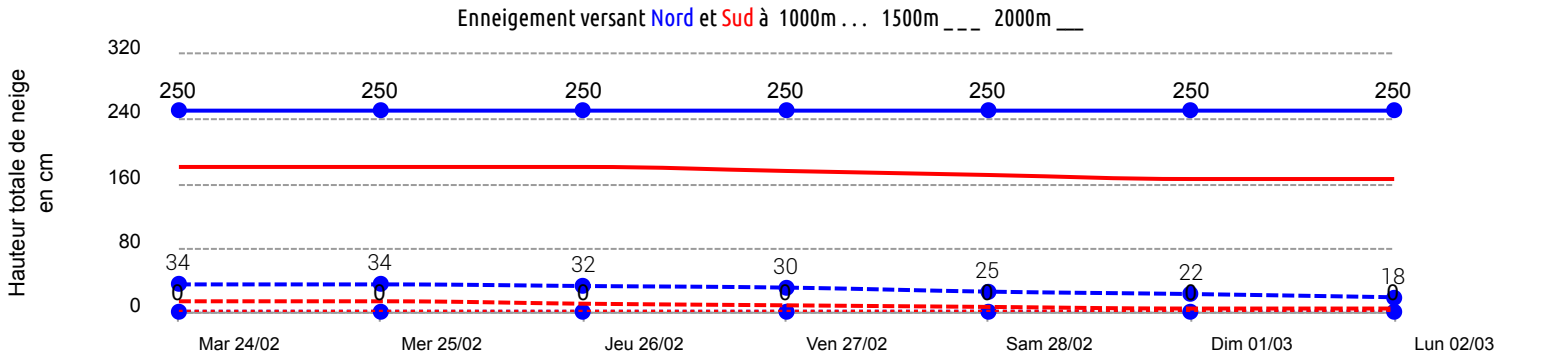

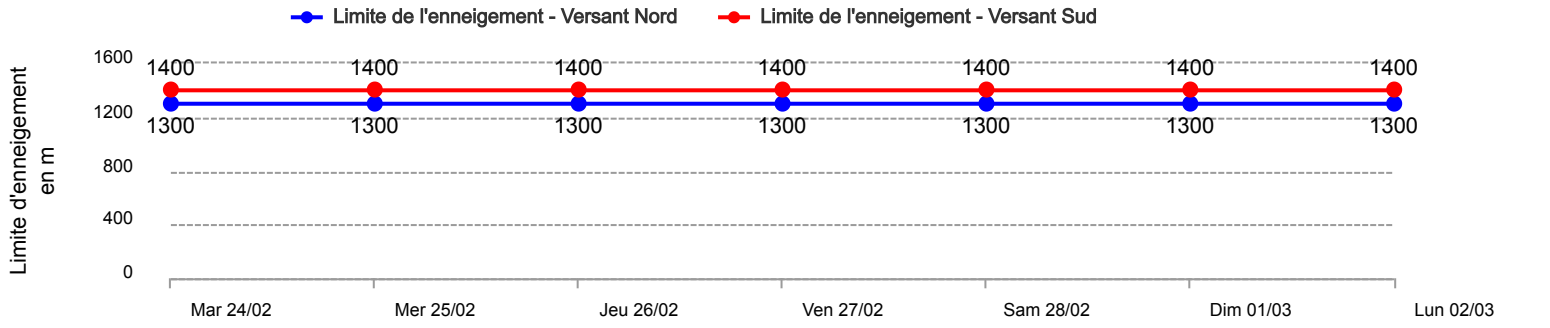

Pour consulter la vigilance en cours, veuillez vous rendre sur le site https://vigilance.meteofrance.fr/fr

Météo-France - 73 avenue de Paris, 94165 Saint-Mandé cedex - Contact : contact@meteo.fr

Rédigé par Météo-France avec la contribution des observateurs du réseau nivo-météorologiques. Partenariat : ANMSM (Maires de Stations de Montagne), DSF (Domaines Skiables de France), ADSP (Directeurs de Pistes et de la Sécurité des Stations de Sports d'Hiver) et autres acteurs de la montagne.

Bulletin neige & avalanches par téléphone au
0 892 68 10 20 Service 0,35 € / min + prix appel