Bulletin d'estimation du risque d'avalanche
(valable en dehors des pistes balisées et ouvertes)

MASSIF : Thabor

Rédigé le lundi 2 mars 2026 à 15h

Estimation des risques pour le : MARDI 03 MARS

PLAQUES EN ALTITUDE, DIFFICILES À SOLLICITER - FAIBLE ACTIVITÉ EN NEIGE HUMIDE

2

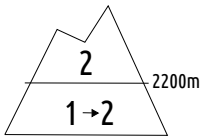

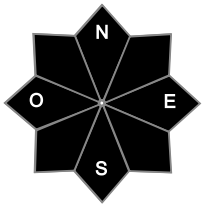

Au-dessus de 2200m indice de risque limité, plus bas indice faible évoluant en limité.

Départs spontanés : rares départs en neige humide en journée ou avalanches de fond

Déclenchements provoqués : plaques difficiles à déclencher en altitude, mais pouvant engendrer d'épaisses cassures

Indices de risque : 5 très fort - 4 fort - 3 marqué - 2 limité - 1 faible -- En noir : les pentes les plus dangereuses

Stabilité du manteau neigeux

Situation avalancheuse typique : couche fragile persistante neige humide

Déclenchements provoqués :

- **plaques épaisses sur couche fragile persistante enfouie** encore présentes dans les orientations ouest / nord / est au-dessus de 2000/2200 m, voir en versant sud au-dessus de 2500/2700 m. Déclenchement difficile au passage d'un skieur, mais restant possible là où le manteau neigeux est moins épais (croupes, bords de couloir). Avalanche de grande taille en ubac avec des cassures épaisses et large, plutôt de taille moyenne en adret d'altitude. Danger difficile à détecter, neige pouvant être en vielle poudreuse ou en neige humide en surface.
- **en neige humide.** Un skieur peut favoriser un départ superficiel de neige fortement humidifiée en pente raide ensoleillée, généralement de petite taille.

Départs spontanés :

- **avalanches de neige humide,** peu probables au levé du jour, puis quelques départs superficiels au soleil au fil de la journée en orientations est / sud / ouest. Départs ponctuels de petite taille, rarement moyenne.
- **rares avalanches de fond** suite à la rupture de reptations (gueules de baleine). Avalanches de taille moyenne, voire grande, possibles à n'importe quel moment du jour et de la nuit.

Qualité de la neige

L'enneigement est excédentaire. Les limites d'enneigement remontent dans les pentes bien exposées au soleil.
Hauteurs de neige observées vers 2500 m : 187 cm dans le vallon du Chardonnet, 126 cm à la nivose des Rochilles, 84 cm à la nivose du Galibier (secteur venté).

Limite d'enneigement skiable en fond de vallées en ubacs, 1500/1600 m en adrets pas trop raides.

État de la neige de surface : croute souvent portante le matin après un bon regel nocturne, s'humidifiant en journée au fil de l'ensoleillement. En versants nord-est à nord-ouest au-dessus de 2100/2200 m, vieille poudreuse encore meuble, plus travaillée par le vent proche des crêtes.

Aperçu météo pour le mardi 03 mars

	nuit	matin	après-midi	soir

Temps sec avec des passage de nuages élevés.

Pluie-Neige				
Iso 0 °C	2 000 m	2 300 m	2 400 m	2 200 m
Vent 2000 m	↑ 10 km/h	↖ 5 km/h	↙ 10 km/h	↑ 5 km/h
Vent 3000 m	↖ 20 km/h	↖ 10 km/h	↖ 10 km/h	↑ 10 km/h

Épaisseur de neige hors-piste

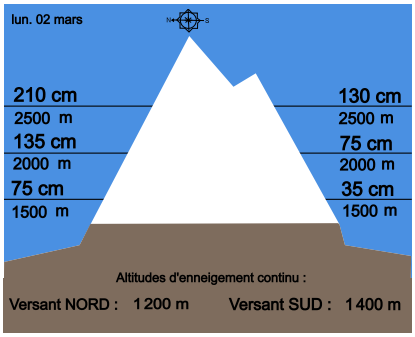

Précipitations à 1800 m

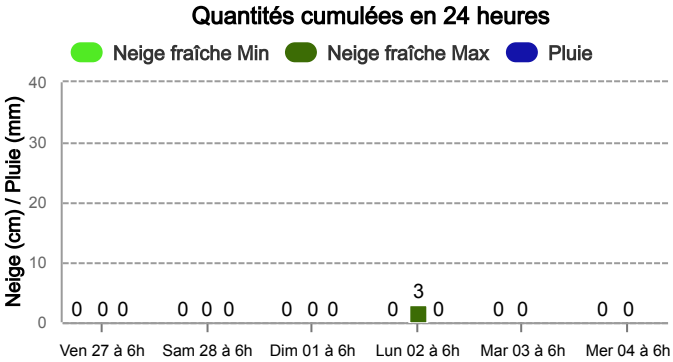

Tendance du mercredi 04 mars

2

Indice de risque limité

Risque limité. Encore des plaques difficiles à déclencher en altitude. Activité en neige humide limitée en journée.

Pour consulter la vigilance en cours, veuillez vous rendre sur le site https://vigilance.meteofrance.fr/fr

Météo-France - 73 avenue de Paris, 94165 Saint-Mandé cedex - Contact : contact@meteo.fr

Rédigé par Météo-France avec la contribution des observateurs du réseau nivo-météorologiques. Partenariat : ANMSM (Maires de Stations de Montagne), DSF (Domaines Skiables de France), ADSP (Directeurs de Pistes et de la Sécurité des Stations de Sports d'Hiver) et autres acteurs de la montagne.

Bulletin neige & avalanches par téléphone au
0 892 68 10 20 Service 0,35 € / min + prix appel

RÉPUBLIQUE FRANÇAISE
Liberté Égalité Fraternité

METEO FRANCE
À VOS CÔTÉS, DANS UN CLIMAT QUI CHANGE

Bulletin d'estimation du risque d'avalanche
(valable en dehors des pistes balisées et ouvertes)

MASSIF : Thabor

Rédigé le lundi 2 mars 2026 à 15h

Conditions nivo-météo des 7 derniers jours

	mar. 24/02				mer. 25/02				jeu. 26/02				ven. 27/02				sam. 28/02				dim. 01/03				lun. 02/03			
	03h	09h	15h	21h	03h	09h	15h	21h	03h	09h	15h	21h	03h	09h	15h	21h	03h	09h	15h	21h	03h	09h	15h	21h	03h	09h	15h	21h
Météo																												
Vent (km/h)	30	15	5	10	15	10	10	10	10	10	10	10	10	5	10	15	20	20	25	20	15	20	20	20	20	25	25	20
à 3000m																												
Vent (km/h)	10	5	0	5	5	5	5	5	5	5	5	5	5	5	5	5	5	10	15	10	5	10	15	10	10	10	15	10
à 2000m																												

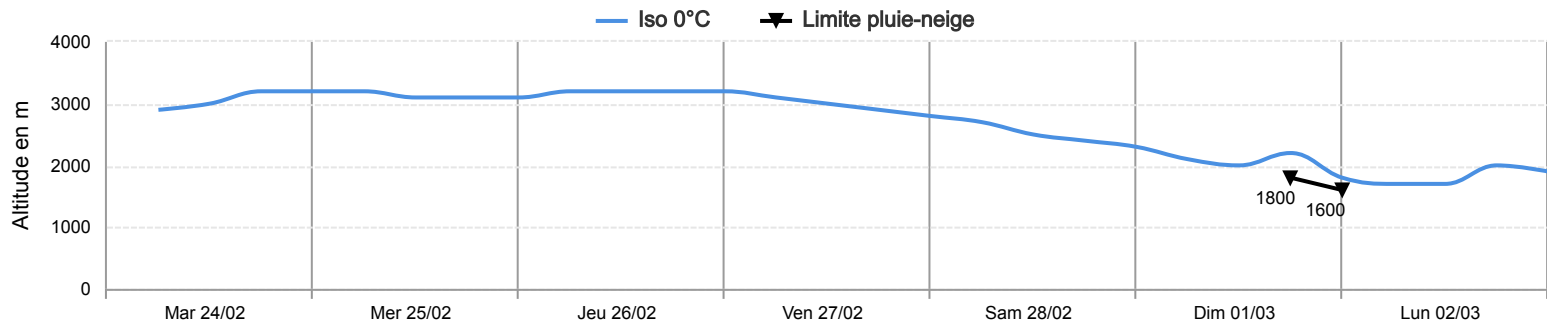

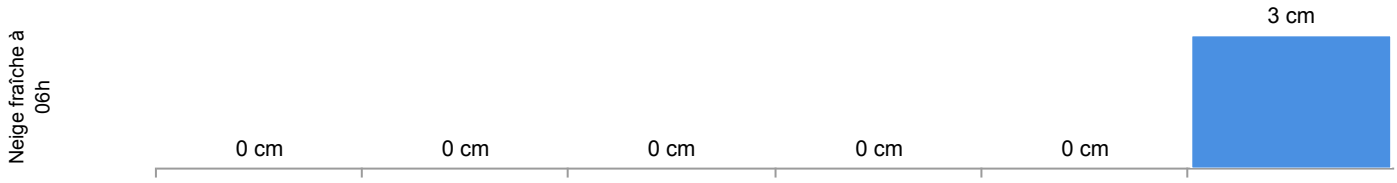

Risque d'avalanche	mar. 24/02	mer. 25/02	jeu. 26/02	ven. 27/02	sam. 28/02	dim. 01/03	lun. 02/03
	3	3	3	2	2	2	2

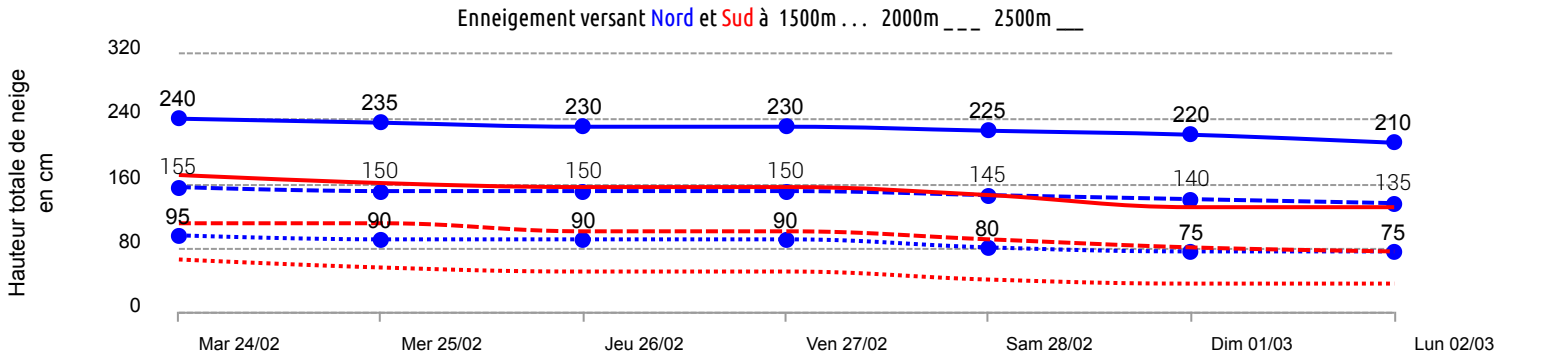

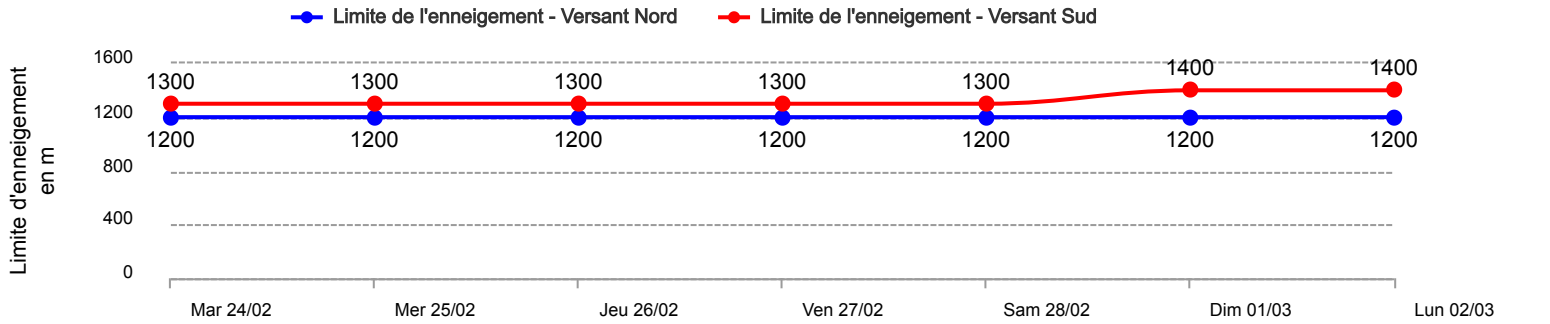

Pour consulter la vigilance en cours, veuillez vous rendre sur le site https://vigilance.meteofrance.fr/fr

Météo-France - 73 avenue de Paris, 94165 Saint-Mandé cedex - Contact : contact@meteo.fr

Rédigé par Météo-France avec la contribution des observateurs du réseau nivo-météorologiques. Partenariat : ANMSM (Maires de Stations de Montagne), DSF (Domaines Skiables de France), ADSP (Directeurs de Pistes et de la Sécurité des Stations de Sports d'Hiver) et autres acteurs de la montagne.

Bulletin neige & avalanches par téléphone au

0 892 68 10 20 Service 0,35 € / min + prix appel