Bulletin d'estimation du risque d'avalanche

(valable en dehors des pistes balisées et ouvertes)

MASSIF : Aspe Ossau

Rédigé le lundi 2 mars 2026 à 16h

Estimation des risques pour le : MARDI 03 MARS

AVALANCHES DE FOND AU SOLEIL, PLAQUES À L'OBRE EN ALTITUDE

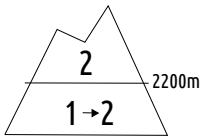

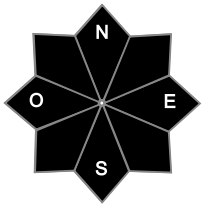

Plaques et soleil

Au-dessus de 2200m indice de risque limité, plus bas indice faible évoluant en limité.

Départs spontanés : Avalanches de fond parfois grandes, surtout au soleil

Déclenchements provoqués : Plaques persistant en secteurs ombragés d'altitude

Indices de risque : 5 très fort - 4 fort - 3 marqué - 2 limité - 1 faible -- En noir : les pentes les plus dangereuses

Stabilité du manteau neigeux

Situation avalancheuse typique : avalanches de fond couche fragile persistante

Départs spontanés : En neige humide. **Risque d'avalanches de fond (de glissement)**, plus présent à partir de l'après-midi et persistant ensuite, possibles **en toutes orientations** en moyenne montagne mais surtout en versants ensoleillés plus haut. Important l'intégralité du manteau, elles peuvent atteindre une taille moyenne à grande.
Signes parfois à observer : **gueules de baleine** (fissures qui s'ouvrent dans le manteau perpendiculairement à la pente). Trouées d'avalanche récentes jusqu'à l'herbe, à proximité.
Des départs ponctuels en versants ensoleillés sont aussi attendus, mais restent de taille petite à moyenne.

Déclenchements provoqués : **Au-dessus de 2200 m vers les pentes d'un large secteur Nord**, le manteau neigeux est encore hivernal. Des couches fragiles sont enfouies dans le manteau neigeux, souvent difficilement sollicitables à cause de leur profondeur, mais le déclenchement d'une avalanche est encore possible aux zones où le manteau est plus mince, rapprochant les couches fragiles de la surface : entrées des combes, ruptures de pentes par exemple.

Autres : Les expositions nord d'altitude, en particulier nord-ouest sont souvent glacées et très glissantes.

Qualité de la neige

Enneigement : La fonte commence à faire son effet sous 1600m, l'enneigement est bon au-dessus de 1800 m mais bien irrégulièrement réparti, crêtes dégarnies en particulier à l'ouest, combes plus chargées et corniches restant souvent imposantes.
Limites skiables : à partir de 1600/1700 m, parfois 1400/1500 en versants froids.
État de la neige : Manteau printanier en sud et sous 2200m en nord, bien regelé le matin, ramollissant au soleil ensuite. En nord, au-dessus de 2200m, alternance de neige sèche et meuble et de zones en neige très dure ou en glace.

Aperçu météo pour le mardi 03 mars

	nuit	matin	après-midi	soir

Bien ensoleillé le matin, arrivée d'un voile devenant épais par le sud-est l'après-midi. Plus nuageux en soirée, quelques gouttes possbiles.

Pluie-Neige				
Iso 0 °C	2 600 m	2 400 m	2 400 m	2 500 m
Vent 1500 m	↑ 25 km/h	↖ 15 km/h	↖ 15 km/h	↖ 10 km/h
Vent 3000 m	↑ 35 km/h	↑ 15 km/h	↑ 15 km/h	↖ 15 km/h

Épaisseur de neige hors-piste

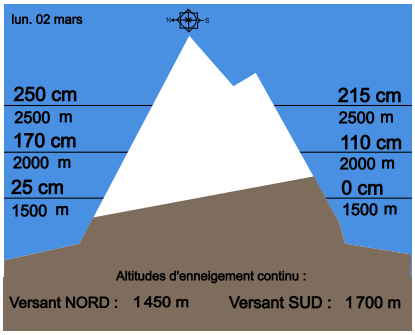

Précipitations à 1800 m

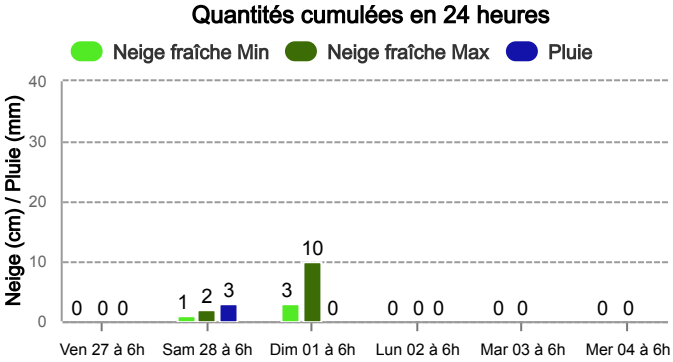

Tendance du mercredi 04 mars

Indice de risque limité

Peu d'évolution des conditions.

Pour consulter la vigilance en cours, veuillez vous rendre sur le site https://vigilance.meteofrance.fr/fr

Météo-France - 73 avenue de Paris, 94165 Saint-Mandé cedex - Contact : contact@meteo.fr

Rédigé par Météo-France avec la contribution des observateurs du réseau nivo-météorologiques. Partenariat : ANMSM (Maires de Stations de Montagne), DSF (Domaines Skiables de France), ADSP (Directeurs de Pistes et de la Sécurité des Stations de Sports d'Hiver) et autres acteurs de la montagne.

Bulletin neige & avalanches par téléphone au **0 892 68 10 20** Service 0,35 € / min + prix appel

RÉPUBLIQUE FRANÇAISE
Liberté Égalité Fraternité

METEO FRANCE
À VOS CÔTÉS, DANS UN CLIMAT QUI CHANGE

Bulletin d'estimation du risque d'avalanche

(valable en dehors des pistes balisées et ouvertes)

MASSIF : Aspe Ossau

Rédigé le lundi 2 mars 2026 à 16h

Conditions nivo-météo des 7 derniers jours

	mar. 24/02				mer. 25/02				jeu. 26/02				ven. 27/02				sam. 28/02				dim. 01/03				lun. 02/03			
	03h	09h	15h	21h	03h	09h	15h	21h	03h	09h	15h	21h	03h	09h	15h	21h	03h	09h	15h	21h	03h	09h	15h	21h	03h	09h	15h	21h
Météo																												
Vent (km/h)	60	45	35	25	25	25	30	30	30	30	30	35	40	45	30	25	15	10	10	10	15	20	60	65	55	45	50	40
à 3000m																												
Vent (km/h)	25	20	15	15	10	10	15	15	15	15	15	15	25	25	20	10	10	10	15	5	10	15	35	45	40	35	30	30
à 1500m																												

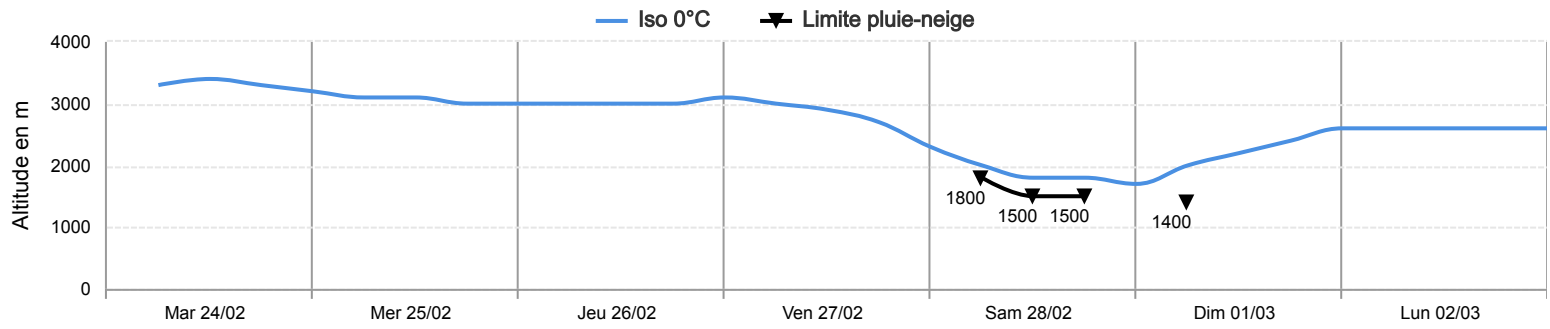

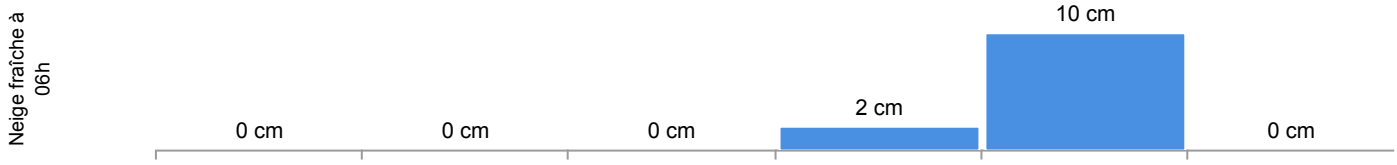

Risque d'avalanche	mar. 24/02	mer. 25/02	jeu. 26/02	ven. 27/02	sam. 28/02	dim. 01/03	lun. 02/03
	2	2	2	2	2	2	2

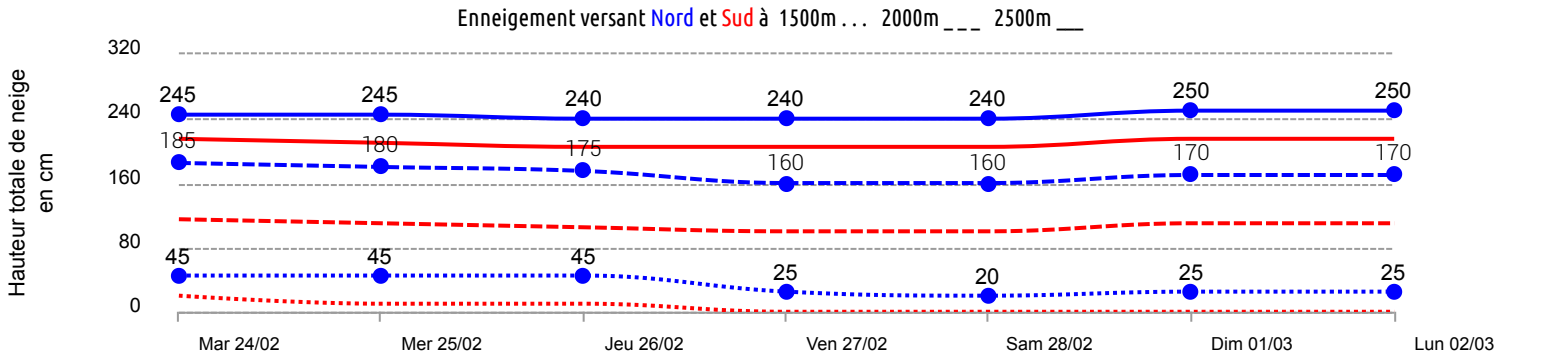

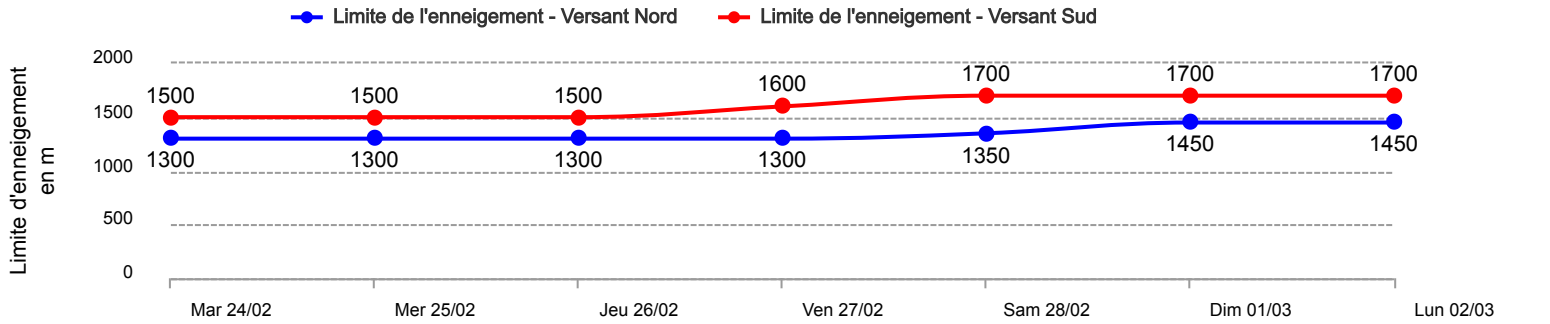

Pour consulter la vigilance en cours, veuillez vous rendre sur le site https://vigilance.meteofrance.fr/fr

Météo-France - 73 avenue de Paris, 94165 Saint-Mandé cedex - Contact : contact@meteo.fr

Bulletin neige & avalanches par téléphone au

0 892 68 10 20 Service 0,35 € / min + prix appel

Rédigé par Météo-France avec la contribution des observateurs du réseau nivo-météorologiques. Partenariat : ANMSM (Maires de Stations de Montagne), DSF (Domaines Skiables de France), ADSP (Directeurs de Pistes et de la Sécurité des Stations de Sports d'Hiver) et autres acteurs de la montagne.