Bulletin d'estimation du risque d'avalanche
(valable en dehors des pistes balisées et ouvertes)

MASSIF : Belledonne

Rédigé le lundi 2 mars 2026 à 16h

Estimation des risques pour le : MARDI 03 MARS

NOUVELLE DÉSTABILISATION POSSIBLE AU SOLEIL.

2

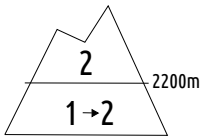

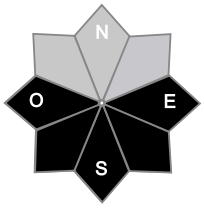

Au-dessus de 2200m indice de risque limité, plus bas indice faible évoluant en limité.

Départs spontanés : Avalanches de neige humide et plaques de fond.

Déclenchements provoqués : Très rares plaques en versant froid de haute altutde

Indices de risque : 5 très fort - 4 fort - 3 marqué - 2 limité - 1 faible -- En noir : les pentes les plus dangereuses

Stabilité du manteau neigeux

Situation avalancheuse typique : neige humide — avalanches de fond

Sous l'effet de plus d'une semaine de soleil et de douceur, le manteau neigeux s'est considérablement tassé et il est bien consolidé en dessous de 2200/2400 m selon les versants. A plus haute altitude, il reste de rares instabilités en neige froide.
Départs spontanés : l'humidification du manteau neigeux reprend mardi dès les premières heures de soleil en augmentant significativement le risque de départ spontané d'avalanches de neige lourde pouvant emmener des volumes de neige conséquents. Dans les versants sud-est à sud-ouest , on peut s'attendre à une déstabilisation de la totalité de la neige en place, gorgée d'eau du haut en bas du manteau.
Déclenchements provoqués : Dans les versants ombragés de haute montagne, on ne peut pas exclure la possibilité de déclencher une plaque de neige compactée par le vent qui reposerait sur une couche fragile insuffisamment enfouie, par exemple en bordure de zone d'accumulation ou à proximité des rochers. Le risque est de plus en plus faible, mais en cas d'avalanche la cassure peut facilement dépasser un mètre. Attention également dans les pentes chauffées par le soleil, car le passage d'un skieur à une heure trop tardive pourrait mettre en mouvement de grosses quantités de neige lourde.

Qualité de la neige

Qualification de l'enneigement : L'enneigement régresse en partie basse, mais il est toujours bon pour la saison dès 1300 m, voire très bon au dessus de 1500 m environ, notamment dans les combes d'altitude. On trouve des crêtes un peu dégarnies par le vent, ou au contraire des corniches assez conséquentes.

Limites skiables : vers 1300/1600 m.

Qualité de la neige mardi : Sous 2200 m voire plus haut en sud, manteau neigeux de type printanier avec une neige croûtée par le regel nocturne, s'humidifiant en journée parfois profondément selon l'orientation.. Dans les versants ombragés au-dessus de 2200 m, neige restée davantage froide, bien que de plus en plus densifiée au fil des jours. A proximité des crêtes, neige parfois soufflée ou travaillée par le vent.

Aperçu météo pour le mardi 03 mars

	nuit	matin	après-midi	soir
Pluie-Neige				
Iso 0 °C	2 200 m	2 300 m	2 400 m	2 300 m
Vent 2000 m	10 km/h	10 km/h	10 km/h	10 km/h
Vent 3000 m	20 km/h	15 km/h	15 km/h	5 km/h

Épaisseur de neige hors-piste

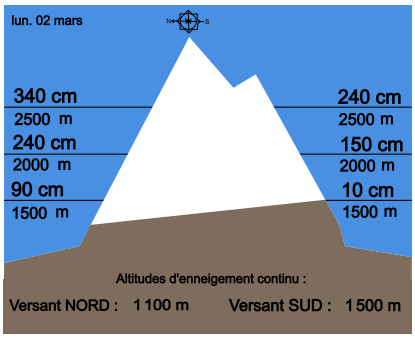

Précipitations à 1800 m

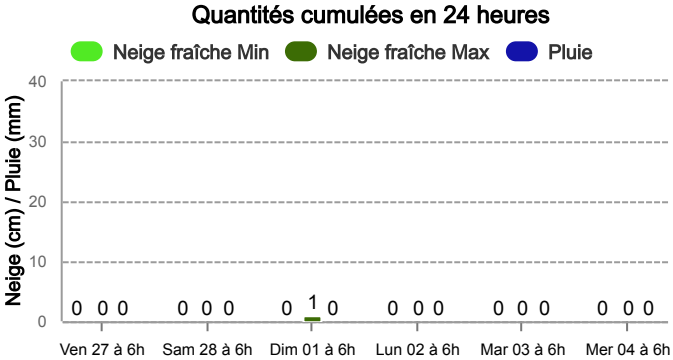

Tendance du mercredi 04 mars

2

Indice de risque limité

Mercredi, reprise de l'humidification et augmentation du risque d'avalanches de neige lourde en cours de journée.

Pour consulter la vigilance en cours, veuillez vous rendre sur le site https://vigilance.meteofrance.fr/fr

Météo-France - 73 avenue de Paris, 94165 Saint-Mandé cedex - Contact : contact@meteo.fr

Rédigé par Météo-France avec la contribution des observateurs du réseau nivo-météorologiques. Partenariat : ANMSM (Maires de Stations de Montagne), DSF (Domaines Skiables de France), ADSP (Directeurs de Pistes et de la Sécurité des Stations de Sports d'Hiver) et autres acteurs de la montagne.

Bulletin neige & avalanches par téléphone au
0 892 68 10 20 Service 0,35 € / min + prix appel

RÉPUBLIQUE FRANÇAISE
Liberté Égalité Fraternité

METEO FRANCE
À VOS CÔTÉS, DANS UN CLIMAT QUI CHANGE

Bulletin d'estimation du risque d'avalanche

(valable en dehors des pistes balisées et ouvertes)

MASSIF : Belledonne

Rédigé le lundi 2 mars 2026 à 16h

Conditions nivo-météo des 7 derniers jours

	mar. 24/02				mer. 25/02				jeu. 26/02				ven. 27/02				sam. 28/02				dim. 01/03				lun. 02/03			
	03h	09h	15h	21h	03h	09h	15h	21h	03h	09h	15h	21h	03h	09h	15h	21h	03h	09h	15h	21h	03h	09h	15h	21h	03h	09h	15h	21h
Météo																												
Vent (km/h)	45	35	15	10	10	10	15	5	0	5	5	5	10	5	15	20	25	30	30	25	25	30	35	40	45	40	30	25
à 3000m																												
Vent (km/h)	15	15	10	5	5	5	10	5	5	5	0	5	5	5	0	5	10	10	15	10	15	20	20	30	35	30	15	10
à 2000m																												

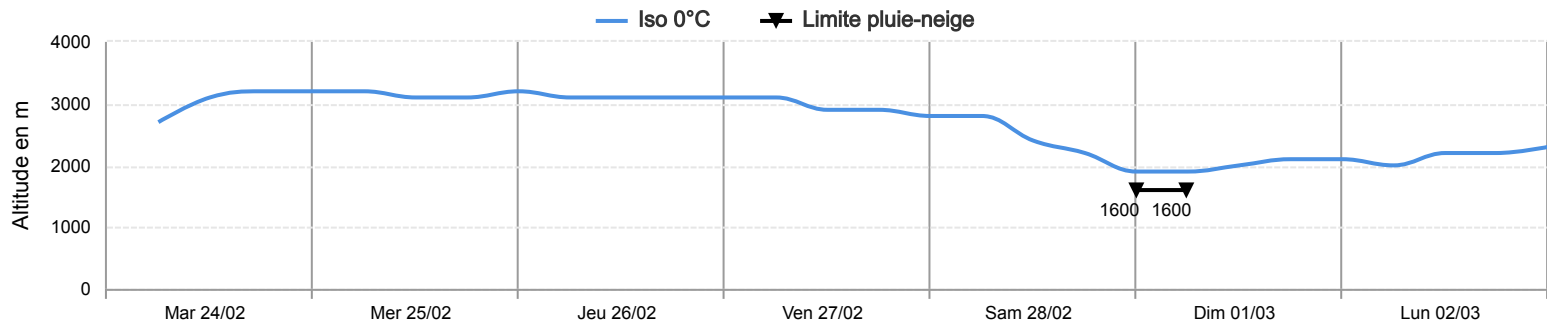

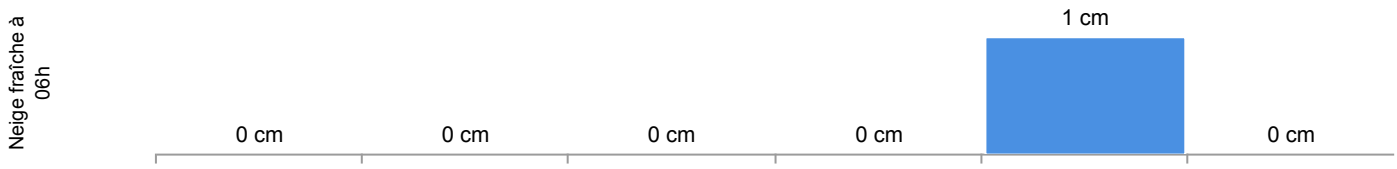

Risque d'avalanche	mar. 24/02	mer. 25/02	jeu. 26/02	ven. 27/02	sam. 28/02	dim. 01/03	lun. 02/03
	3	3	3	2	2	2	2

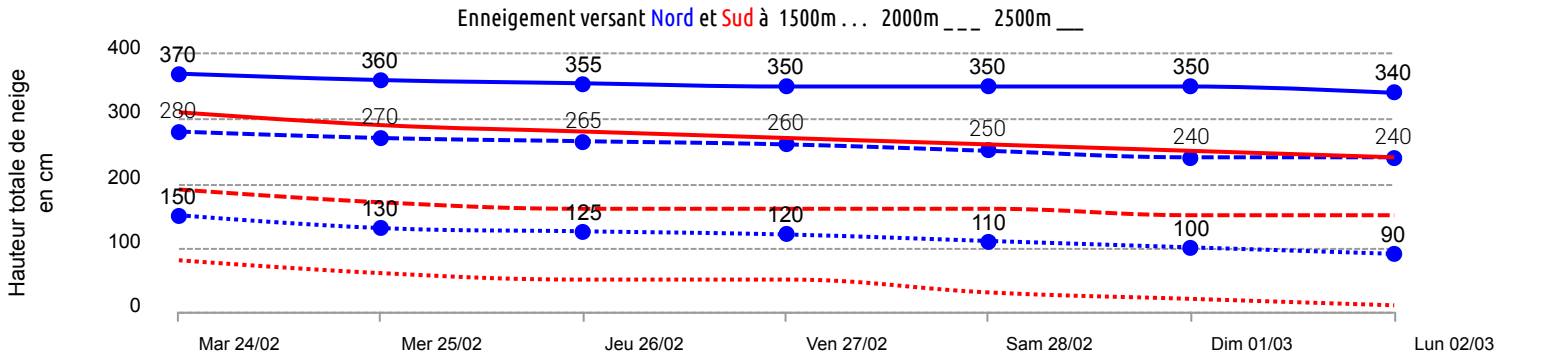

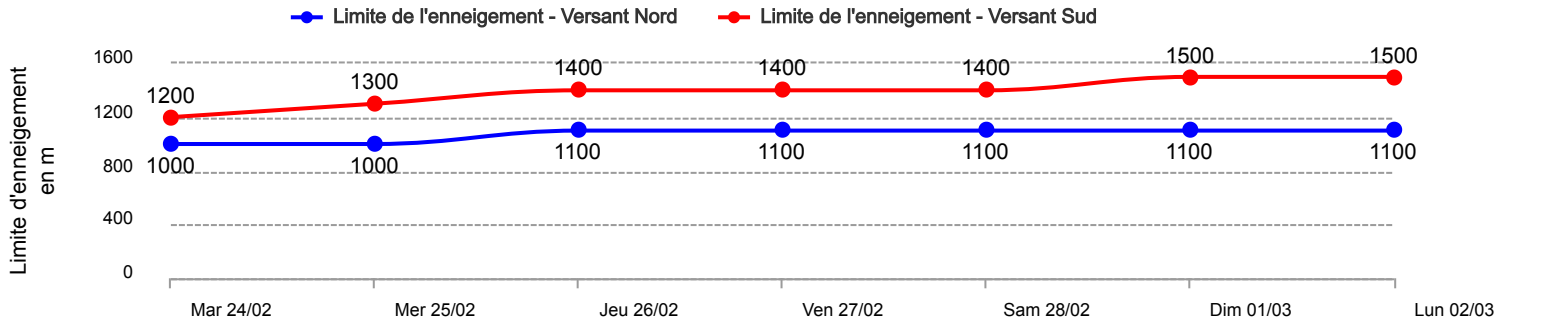

Pour consulter la vigilance en cours, veuillez vous rendre sur le site https://vigilance.meteofrance.fr/fr

Météo-France - 73 avenue de Paris, 94165 Saint-Mandé cedex - Contact : contact@meteo.fr

Rédigé par Météo-France avec la contribution des observateurs du réseau nivo-météorologiques. Partenariat : ANMSM (Maires de Stations de Montagne), DSF (Domaines Skiables de France), ADSP (Directeurs de Pistes et de la Sécurité des Stations de Sports d'Hiver) et autres acteurs de la montagne.

Bulletin neige & avalanches par téléphone au

0 892 68 10 20 Service 0,35 € / min + prix appel