Bulletin d'estimation du risque d'avalanche

(valable en dehors des pistes balisées et ouvertes)

MASSIF : Haute-Maurienne

Rédigé le lundi 2 mars 2026 à 16h

Estimation des risques pour le : MARDI 03 MARS

MANTEAU PLUTÔT STABLE LE MATIN, DÉSTABILISÉ PAR L'HUMIDIFICATION EN JOURNÉE.

3

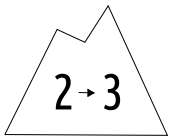

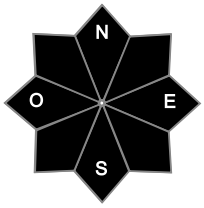

Indice de risque limité évoluant en marqué.

Départs spontanés : rares départs humides l'après-midi, rares plaques de fond.

Déclenchements provoqués : plaques humides au soleil, rares plaques dans les versants ombragés.

Indices de risque : 5 très fort - 4 fort - 3 marqué - 2 limité - 1 faible -- En noir : les pentes les plus dangereuses

Stabilité du manteau neigeux

Situation avalancheuse typique : neige humide couche fragile persistante

Déclenchements provoqués :

- Dans les **pentes ensoleillées hébergeant des couches fragiles enfouies (E/O et S d'altitude)**, après plusieurs heures de soleil, l'enfoncement dans la neige humide devient important, rendant à nouveau possible la sollicitation d'une couche fragile enfouie. Dès lors, une **avalanche de neige humide avec propagation efficace** est possible. Taille 2 (moyenne), rarement 3 (grande).
- **Au-dessus de 2000 m, en versants ombragés (NO/N/NE), rares plaques dures** sur couche fragile persistante. Le déclenchement est **encore possible dans les zones moins enneigées** (abords de crête, croupes dégarnis) car la couche fragile est plus près de la surface. Taille 2, rarement 3, avec cassure 50/70 cm.

Départs spontanés :

- Rare avalanche de neige humide dans les pentes ayant chauffées au Soleil plusieurs heures. Taille 1 à 2, très rarement 3 lorsque l'humidification atteint une couche fragile enfouie.
- Rares plaques de fond, quelles que soient l'heure et l'orientation, plutôt sous 2400 m. Taille 2.

Qualité de la neige

Enneigement : Les températures anormalement douces et le tassement font rentrer l'enneigement dans la normale, surtout en Sud et en basse montagne où la limite d'enneigement dans ces pentes remonte vite. Ailleurs le manteau se tasse considérablement.

Limite skiable : encore skiable dès 1100 m dans les prairies orientées Nord, plutôt 1500 m en Sud.

Qualité de la neige : en Sud, Est, Ouest, conditions de printemps idéales avec bon regel le matin et *"décaillage"* suivant la course du soleil. En Nord, neige croutée sous 2000 m. Au-dessus, neige encore froide, poudreuse dense à l'abri du vent, cartonnée voire dure dans les secteurs ventés (à l'approche des crêtes).

Aperçu météo pour le mardi 03 mars

nuit	matin	après-midi	soir

Belle journée printanière.

Pluie-Neige				
Iso 0 °C	2 000 m	2 400 m	2 600 m	2 200 m
Vent 2500 m	↗ 10 km/h	↘ 5 km/h	→ 5 km/h	→ 5 km/h
Vent 3500 m	↗ 15 km/h	→ 10 km/h	→ 10 km/h	→ 10 km/h

Épaisseur de neige hors-piste

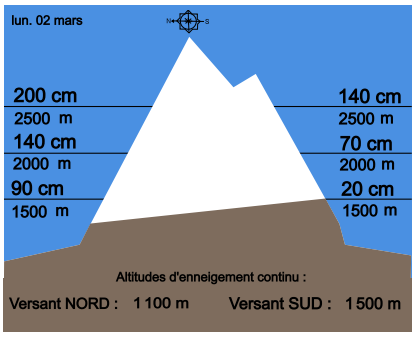

Précipitations à 1800 m

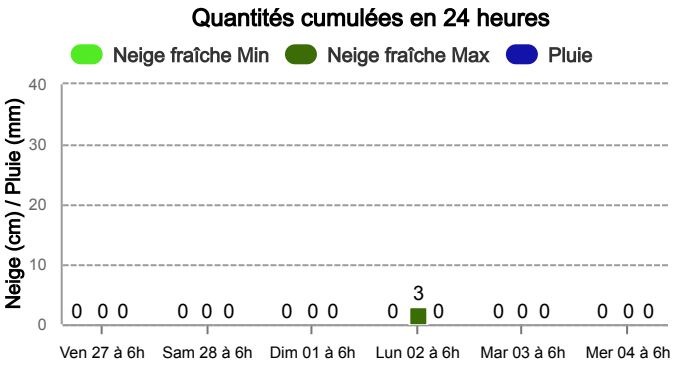

Tendance du mercredi 04 mars

3

Indice de risque marqué

Risque stationnaire. Bon regel le matin puis humidification marquée induisant rapidement un risque d'avalanche humide.

Pour consulter la vigilance en cours, veuillez vous rendre sur le site https://vigilance.meteofrance.fr/fr

Météo-France - 73 avenue de Paris, 94165 Saint-Mandé cedex - Contact : contact@meteo.fr

Rédigé par Météo-France avec la contribution des observateurs du réseau nivo-météorologiques. Partenariat : ANMSM (Maires de Stations de Montagne), DSF (Domaines Skiables de France), ADSP (Directeurs de Pistes et de la Sécurité des Stations de Sports d'Hiver) et autres acteurs de la montagne.

Bulletin neige & avalanches par téléphone au 0 892 68 10 20 Service 0,35 € / min + prix appel

RÉPUBLIQUE FRANÇAISE
Liberté Égalité Fraternité

METEO FRANCE
À VOS CÔTÉS, DANS UN CLIMAT QUI CHANGE

Bulletin d'estimation du risque d'avalanche
(valable en dehors des pistes balisées et ouvertes)
MASSIF : Haute-Maurienne

Rédigé le lundi 2 mars 2026 à 16h

Conditions nivo-météo des 7 derniers jours

	mar. 24/02				mer. 25/02				jeu. 26/02				ven. 27/02				sam. 28/02				dim. 01/03				lun. 02/03			
	03h	09h	15h	21h	03h	09h	15h	21h	03h	09h	15h	21h	03h	09h	15h	21h	03h	09h	15h	21h	03h	09h	15h	21h	03h	09h	15h	21h
Météo																												
Vent (km/h)	35	35	30	25	20	20	20	15	15	15	15	15	15	15	20	20	20	25	30	25	20	20	20	15	20	25	25	20
à 3500m																												
Vent (km/h)	20	15	15	10	5	5	5	5	5	5	5	5	5	5	10	10	10	10	15	10	5	10	5	10	15	20	20	15
à 2500m																												

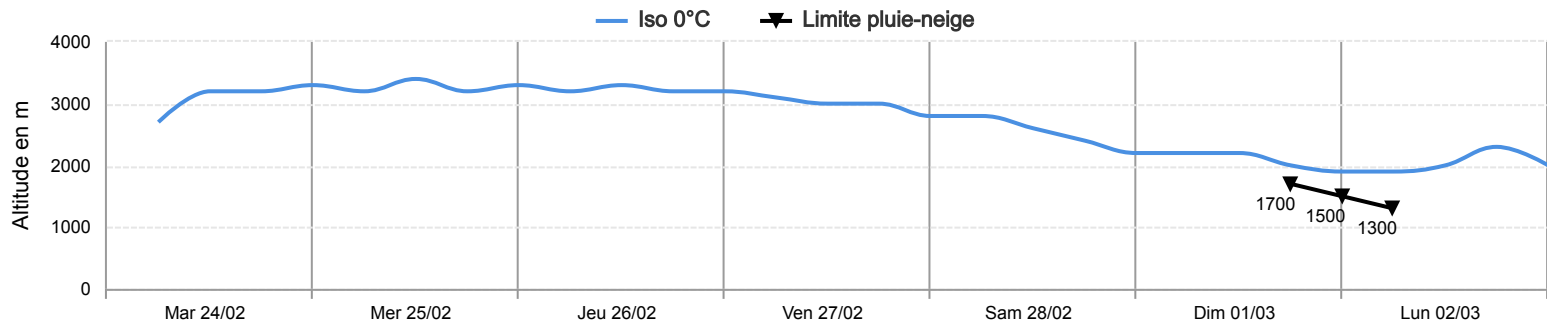

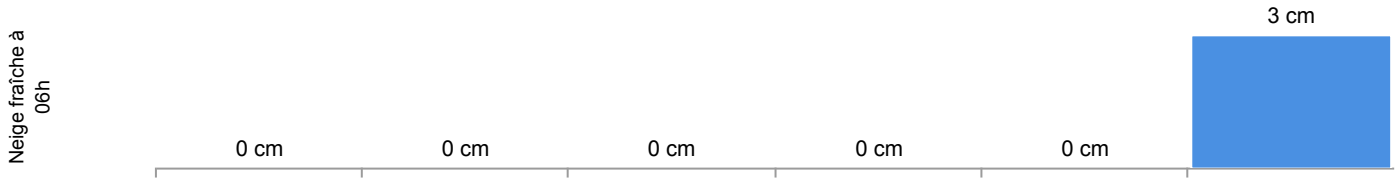

Risque d'avalanche	mar. 24/02	mer. 25/02	jeu. 26/02	ven. 27/02	sam. 28/02	dim. 01/03	lun. 02/03
	3	3	3	3	2	3	3

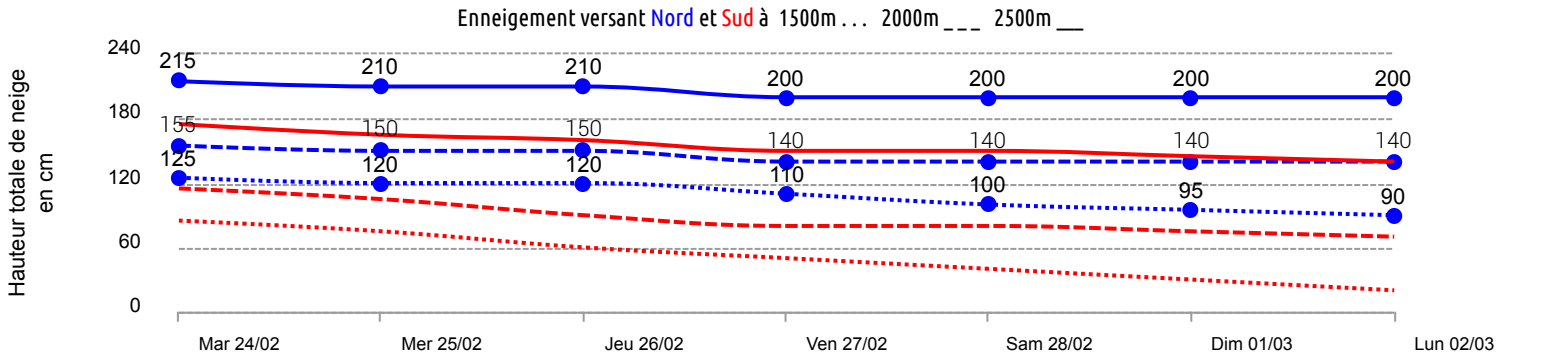

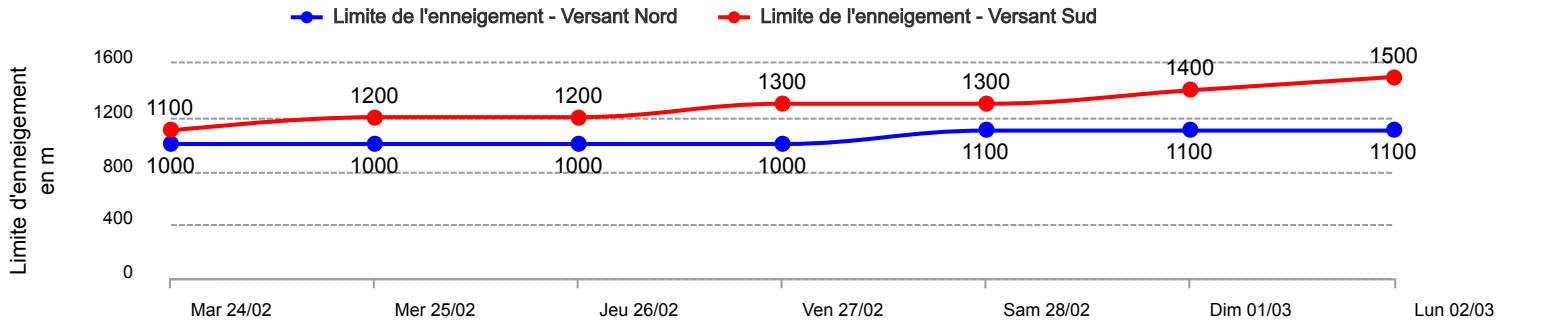

Pour consulter la vigilance en cours, veuillez vous rendre sur le site https://vigilance.meteofrance.fr/fr

Météo-France - 73 avenue de Paris, 94165 Saint-Mandé cedex - Contact : contact@meteo.fr

Rédigé par Météo-France avec la contribution des observateurs du réseau nivo-météorologiques. Partenariat : ANMSM (Maires de Stations de Montagne), DSF (Domaines Skiables de France), ADSP (Directeurs de Pistes et de la Sécurité des Stations de Sports d'Hiver) et autres acteurs de la montagne.

Bulletin neige & avalanches par téléphone au

0 892 68 10 20 Service 0,35 € / min + prix appel