Bulletin d'estimation du risque d'avalanche

(valable en dehors des pistes balisées et ouvertes)

MASSIF : Mercantour

Rédigé le lundi 2 mars 2026 à 16h

Estimation des risques pour le : MARDI 03 MARS

QUELQUES DÉPARTS EN NEIGE HUMIDE

2

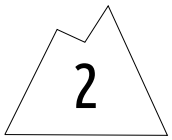

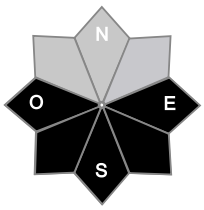

Indice de risque limité.

Départs spontanés : rare avalanche de fond possible, quelques départs superficiels en neige humide.

Déclenchements provoqués : départs en neige humide.

Indices de risque : 5 très fort - 4 fort - 3 marqué - 2 limité - 1 faible -- En noir : les pentes les plus dangereuses

Stabilité du manteau neigeux

Situation avalancheuse typique : avalanches de fond neige humide

Déclenchements provoqués :
- un skieur en pente raide ensoleillée peut provoquer un départ superficiel en neige fortement humidifiée, généralement de petite taille.

Départs spontanés :
- **une rare avalanche de fond** peut se déclencher suite à la rupture d'une reptation (gueule de baleine), de taille moyenne, voire grande. Possibles à n'importe quel moment du jour et de la nuit, en terrain favorable (pentes herbeuses ou dalles rocheuses). Plutôt en dessous de 2500/2700 m en versants ensoleillés, et en dessous de 2000 m en versants nord.
- quelques départs en **neige humide** sont possibles : d'abord peu probables en début de journée après le regel nocturne, puis par départs ponctuels en pentes raides au fil de l'ensoleillement. Avalanches de petite taille, rarement moyenne.

Qualité de la neige

Enneigement excédentaire pour un début mars.
Données observées : 136 cm à la nivôse de Millefonts à 2430 m.

Enneigement skiable dès 1400/1500 m en ubacs en terrains favorables et 1600/1800 m en adrets

État de la neige en surface : croute souvent portante le matin après un bon regel nocturne, s'humidifiant en journée au fil de l'ensoleillement. En ubacs au-dessus de 2000/2200 m environ, neige froide souvent travaillée/durcie par le vent de nord. Zones dégarnies proches des crêtes, alternant avec des corniches parfois épaisses.

Aperçu météo pour le mardi 03 mars

nuit	matin	après-midi	soir

Beau temps. Voile nuageux parfois accentué par la présence de poussières désertiques.

Pluie-Neige				
Iso 0 °C	2 200 m	2 400 m	2 400 m	2 400 m
Vent 2000 m	10 km/h	10 km/h	15 km/h	10 km/h
Vent 3000 m	15 km/h	10 km/h	10 km/h	10 km/h

Épaisseur de neige hors-piste

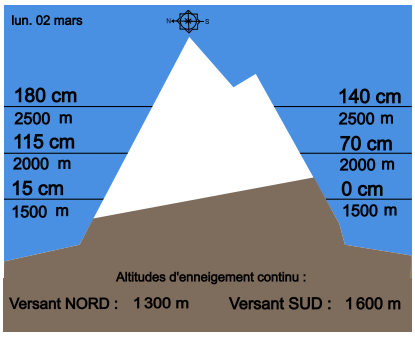

Précipitations à 1800 m

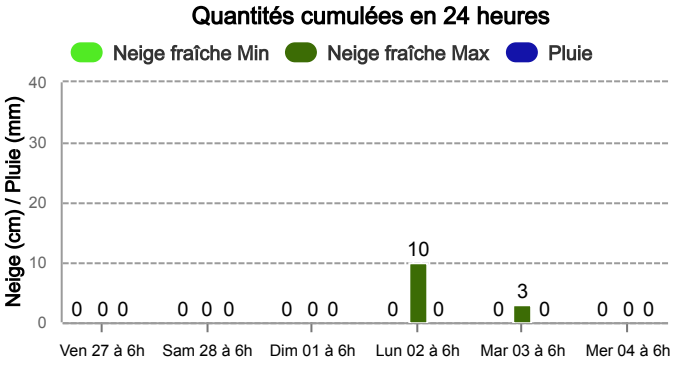

Tendance du mercredi 04 mars

2

Indice de risque limité

maintien d'un risque limité, avec peu d'évolution des conditions.

Pour consulter la vigilance en cours, veuillez vous rendre sur le site https://vigilance.meteofrance.fr/fr

Météo-France - 73 avenue de Paris, 94165 Saint-Mandé cedex - Contact : contact@meteo.fr

Rédigé par Météo-France avec la contribution des observateurs du réseau nivo-météorologiques. Partenariat : ANMSM (Maires de Stations de Montagne), DSF (Domaines Skiables de France), ADSP (Directeurs de Pistes et de la Sécurité des Stations de Sports d'Hiver) et autres acteurs de la montagne.

Bulletin neige & avalanches par téléphone au
0 892 68 10 20 Service 0,35 € / min + prix appel

RÉPUBLIQUE FRANÇAISE
Liberté Égalité Fraternité

METEO FRANCE
À VOS CÔTÉS, DANS UN CLIMAT QUI CHANGE

Bulletin d'estimation du risque d'avalanche
(valable en dehors des pistes balisées et ouvertes)

MASSIF : Mercantour

Rédigé le lundi 2 mars 2026 à 16h

Conditions nivo-météo des 7 derniers jours

	mar. 24/02				mer. 25/02				jeu. 26/02				ven. 27/02				sam. 28/02				dim. 01/03				lun. 02/03			
	03h	09h	15h	21h	03h	09h	15h	21h	03h	09h	15h	21h	03h	09h	15h	21h	03h	09h	15h	21h	03h	09h	15h	21h	03h	09h	15h	21h
Météo																												
Vent (km/h)	30	25	10	10	15	15	15	15	15	15	15	10	10	10	10	10	15	20	25	15	15	20	20	20	15	15	15	10
à 3000m																												
Vent (km/h)	15	10	5	10	10	10	10	10	10	5	10	10	5	5	10	5	5	10	15	5	5	5	15	10	5	10	15	10
à 2000m																												

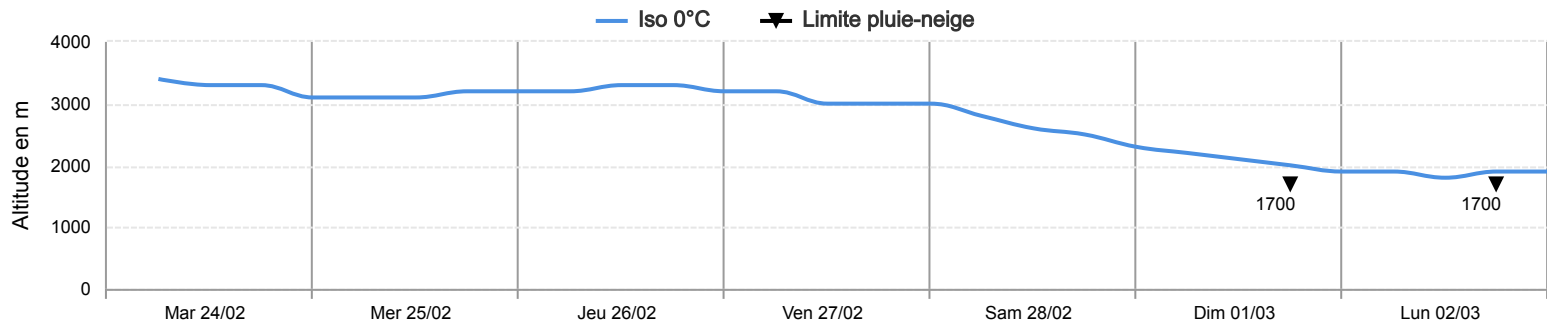

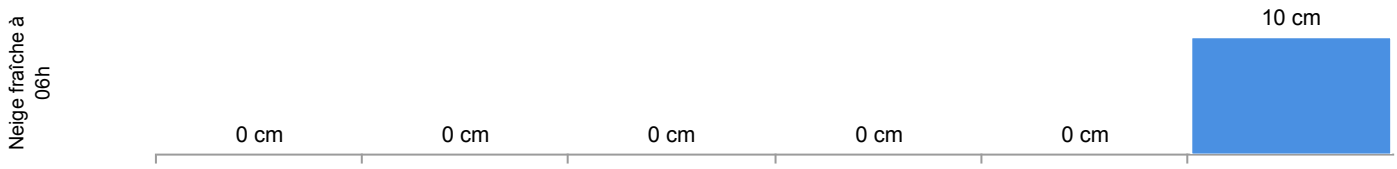

Risque d'avalanche	mar. 24/02	mer. 25/02	jeu. 26/02	ven. 27/02	sam. 28/02	dim. 01/03	lun. 02/03
	2	2	2	2	2	2	2

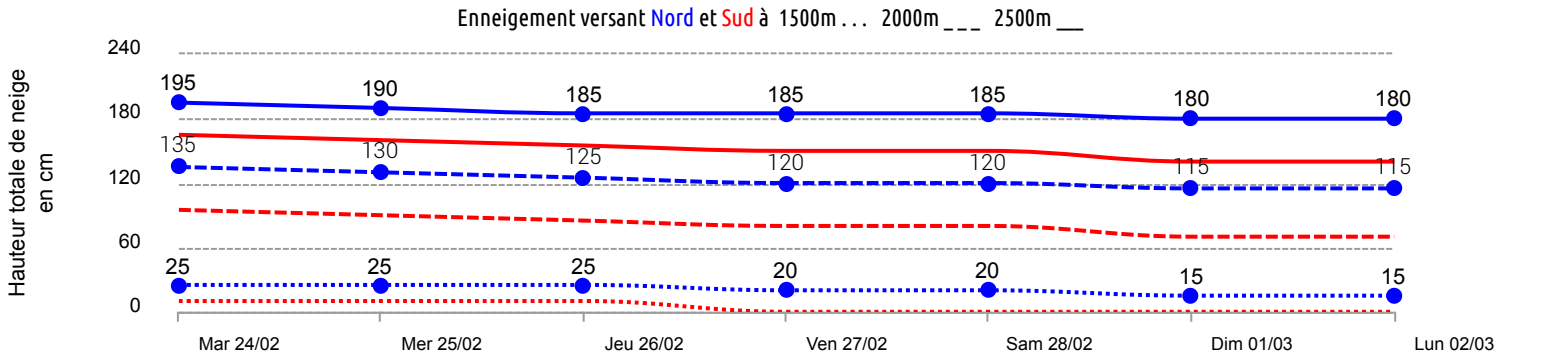

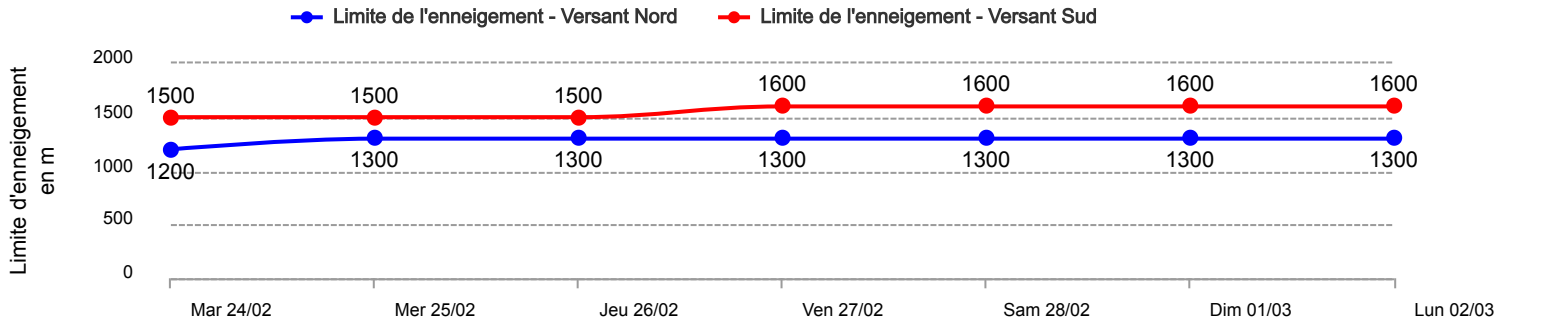

Pour consulter la vigilance en cours, veuillez vous rendre sur le site https://vigilance.meteofrance.fr/fr

Météo-France - 73 avenue de Paris, 94165 Saint-Mandé cedex - Contact : contact@meteo.fr

Rédigé par Météo-France avec la contribution des observateurs du réseau nivo-météorologiques. Partenariat : ANMSM (Maires de Stations de Montagne), DSF (Domaines Skiables de France), ADSP (Directeurs de Pistes et de la Sécurité des Stations de Sports d'Hiver) et autres acteurs de la montagne.

Bulletin neige & avalanches par téléphone au
0 892 68 10 20 Service 0,35 € / min + prix appel