Bulletin d'estimation du risque d'avalanche

(valable en dehors des pistes balisées et ouvertes)

MASSIF : Mont-Blanc

Rédigé le lundi 2 mars 2026 à 16h

Estimation des risques pour le : MARDI 03 MARS

EPAIS MANTEAU NEIGEUX QUI SE RÉCHAUFFE AU SOLEIL

2

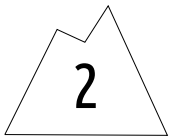

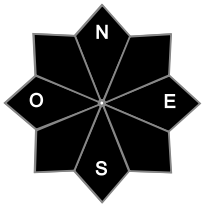

Indice de risque limité.

Départs spontanés : Départs humides et plaques de fond.

Déclenchements provoqués : Neige humide en moyenne montagne, au fil du réchauffement diurne.

Indices de risque : 5 très fort - 4 fort - 3 marqué - 2 limité - 1 faible -- En noir : les pentes les plus dangereuses

Stabilité du manteau neigeux

Situation avalancheuse typique : neige humide avalanches de fond

Déclenchements provoqués :

* Au fil de l'ensoleillement, coulées sous les skis. Taille 1 à 2 (petite à moyenne).
* Au-dessus de 2000 m en versants E/N/O : Présence d'une **couche fragile persistante enfouie.** Difficile à déclencher mais possible **en cascade** et donner une avalanche de plus grande ampleur (cassure de 80/150 cm). La profondeur de l'enfouissement de la couche fragile varie énormément, même dans une même pente. Cette **couche fragile est parfois (plus rarement) présente en Sud en altitude** et peut être sollicitée par un enfoncement important dans la neige humide. Une avalanche en plaque (même d'aspect humide en surface) avec une bonne propagation est possible. Taille 2, rarement 3 (moyenne, rarement grande).
* En haute montagne : **rares plaques à vent** formées par le **vent de SW** le weekend dernier dans la neige récente restée légère. Principalement présentes vers les crêtes/arêtes. Taille 2 (moyenne).

Départs spontanés :

* Avalanche de **neige humide** au fil du réchauffement. Très rare départ en plaque si humidification de la couche fragile persistante. Taille 1 à 2, très rarement 3.
* En tous versant, principalement sous 2400 m : **plaques de fond**. Départs dans les pentes raides et lisses (pentes herbeuses, dalles rocheuses). Départs possibles à toute heure du jour ou de la nuit. Taille 2 (moyenne), à 3 (grande).
* Chutes de **corniches**, épaisses et volumineuses. Leurs chutes peuvent déclencher une plaque en contrebas.

Qualité de la neige

Enneigement : bon pour la période. On peut chausser les skis vers 1200/1300 m en versants E/N/O et 1400/1500 m en versants Sud. Les corniches sont volumineuses et menaçantes. Les arêtes et les crêtes de moyenne montagne sont érodées par le vent de SW à NW.

Qualité de la neige mardi :

* Regel inégal, qui dépendra du voile de la fin de nuit.
* Conditions printanières tous versants (regel le matin et décaille avec le soleil). En Nord dès 2000 m parfois froide, parfois croûtée..
* Au-dessus de 3000 m : neige froide, souvent dure travaillée par le vent de NW à SW, mais encore légère dans des pentes peu exposées au vent.

Aperçu météo pour le mardi 03 mars

	nuit	matin	après-midi	soir
Fin de nuit voilée. Entre de belles éclaircies et un voile plus ou moins épais en journée. Douceur.				
Pluie-Neige				
Iso 0 °C	2 200 m	2 300 m	2 300 m	2 300 m
Vent 2000 m	← 5 km/h	↗ 5 km/h	→ 10 km/h	← 10 km/h
Vent 4000 m	↑ 10 km/h	↑ 10 km/h	→ 10 km/h	↑ 10 km/h

Épaisseur de neige hors-piste

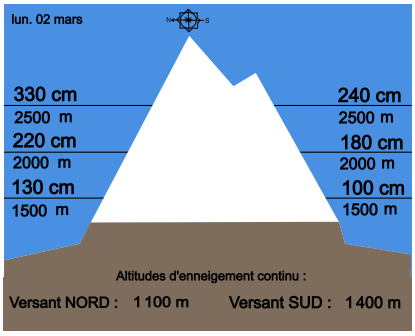

Précipitations à 1800 m

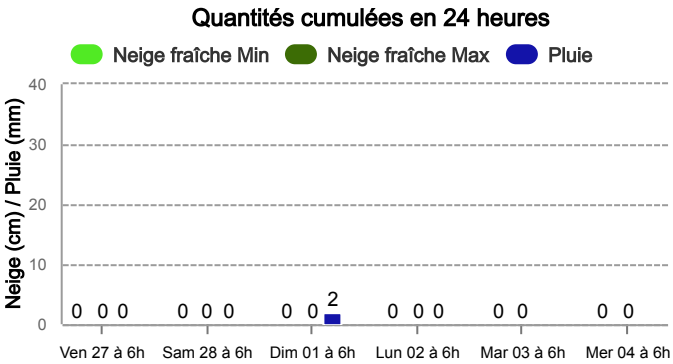

Tendance du mercredi 04 mars

2

Indice de risque limité

Risque stationnaire. Les instabilités augmentent au fil de l'humidification en journée.

Pour consulter la vigilance en cours, veuillez vous rendre sur le site https://vigilance.meteofrance.fr/fr

Météo-France - 73 avenue de Paris, 94165 Saint-Mandé cedex - Contact : contact@meteo.fr

Rédigé par Météo-France avec la contribution des observateurs du réseau nivo-météorologiques. Partenariat : ANMSM (Maires de Stations de Montagne), DSF (Domaines Skiables de France), ADSP (Directeurs de Pistes et de la Sécurité des Stations de Sports d'Hiver) et autres acteurs de la montagne.

Bulletin neige & avalanches par téléphone au

0 892 68 10 20 Service 0,35 € / min + prix appel

RÉPUBLIQUE FRANÇAISE
Liberté Égalité Fraternité

METEO FRANCE
À VOS CÔTÉS, DANS UN CLIMAT QUI CHANGE

Bulletin d'estimation du risque d'avalanche
(valable en dehors des pistes balisées et ouvertes)

MASSIF : Mont-Blanc

Rédigé le lundi 2 mars 2026 à 16h

Conditions nivo-météo des 7 derniers jours

	mar. 24/02				mer. 25/02				jeu. 26/02				ven. 27/02				sam. 28/02				dim. 01/03				lun. 02/03			
	03h	09h	15h	21h	03h	09h	15h	21h	03h	09h	15h	21h	03h	09h	15h	21h	03h	09h	15h	21h	03h	09h	15h	21h	03h	09h	15h	21h
Météo																												
Vent (km/h)	70	60	40	30	20	20	20	20	20	20	30	30	30	30	30	40	50	60	50	40	40	40	25	20	15	15	15	15
à 4000m	↓	↓	↓	↓	↓	↑	↑	↑	↗	↗	↗	↗	↗	↗	↗	↗	↗	↗	↗	↗	↗	↗	↗	↑	↗	↖	↗	↑
Vent (km/h)	10	10	10	10	10	10	10	10	10	10	10	10	10	10	10	10	10	15	10	10	10	10	10	5	10	10	10	10
à 2000m	↗	↙	↙	←	↑	↑	↑	↑	↑	↑	↗	↑	↑	↗	↗	↗	↗	↗	↗	↗	↗	↗	↗	↻	↙	↙	↙	↙

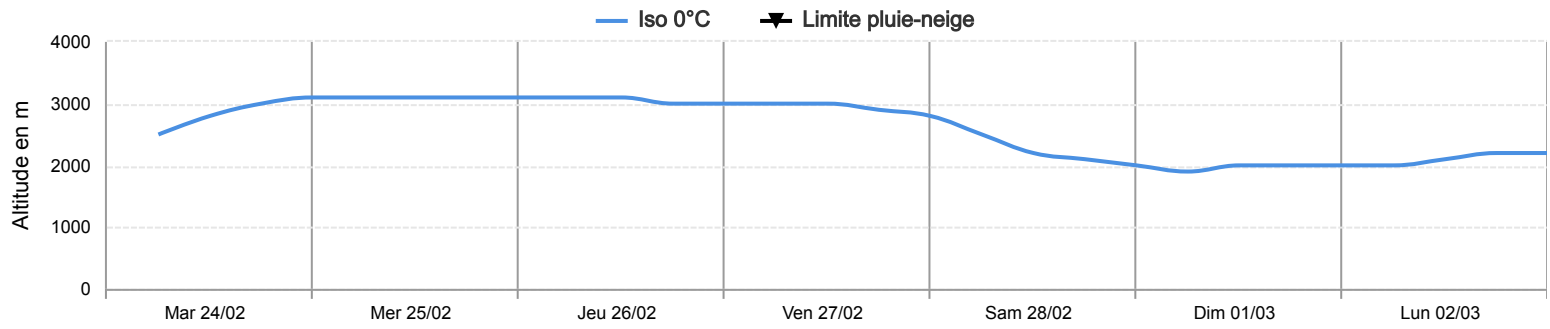

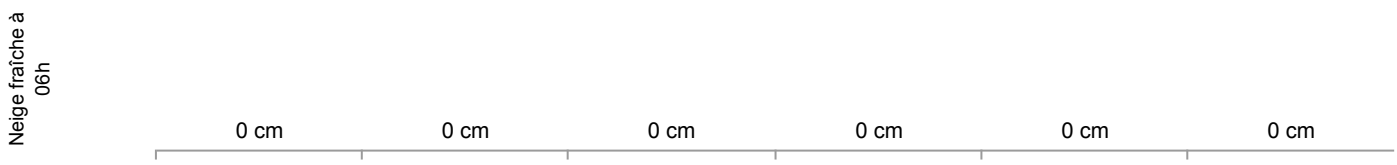

Risque d'avalanche	mar. 24/02	mer. 25/02	jeu. 26/02	ven. 27/02	sam. 28/02	dim. 01/03	lun. 02/03
	3	3	3	3	2	2	2

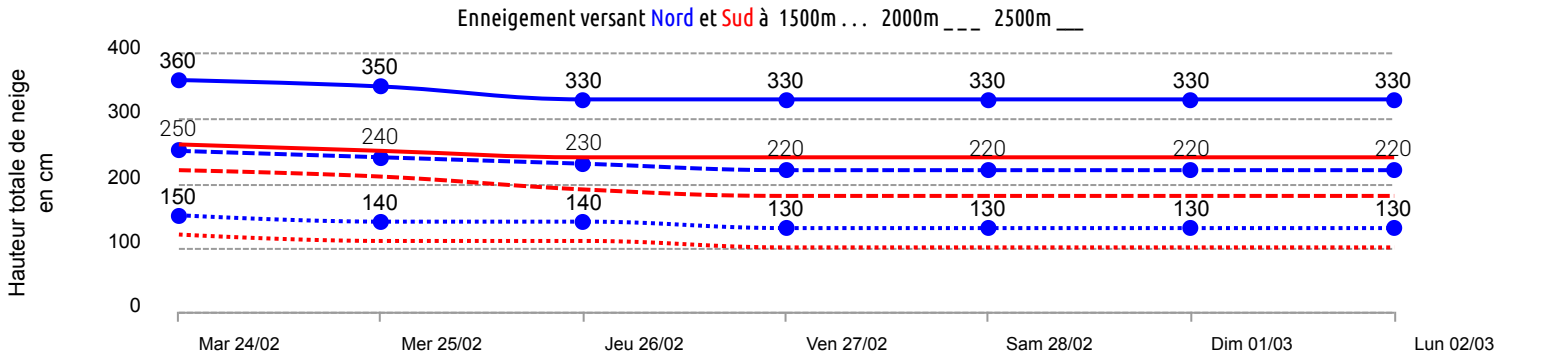

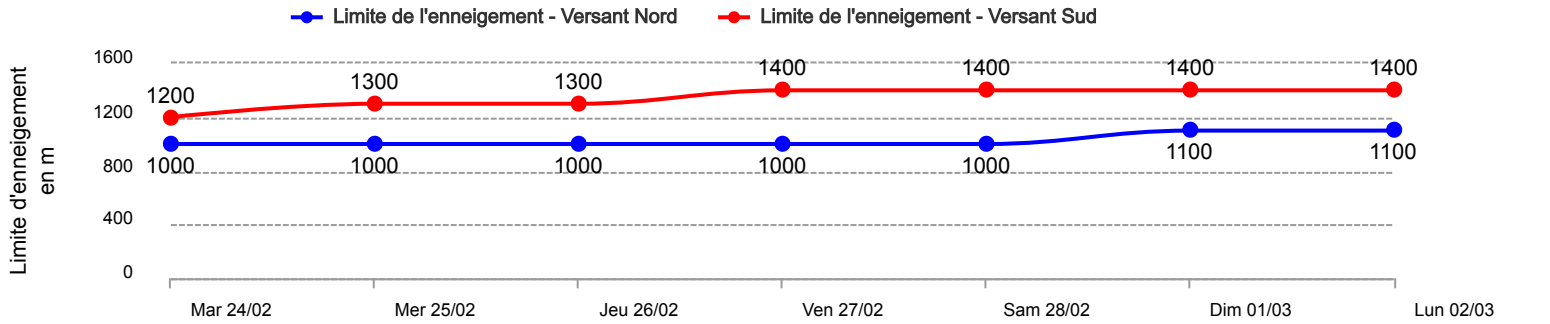

Pour consulter la vigilance en cours, veuillez vous rendre sur le site https://vigilance.meteofrance.fr/fr

Météo-France - 73 avenue de Paris, 94165 Saint-Mandé cedex - Contact : contact@meteo.fr

Rédigé par Météo-France avec la contribution des observateurs du réseau nivo-météorologiques. Partenariat : ANMSM (Maires de Stations de Montagne), DSF (Domaines Skiables de France), ADSP (Directeurs de Pistes et de la Sécurité des Stations de Sports d'Hiver) et autres acteurs de la montagne.

Bulletin neige & avalanches par téléphone au
0 892 68 10 20 Service 0,35 € / min + prix appel