# Bulletin d'estimation du risque d'avalanche
(valable en dehors des pistes balisées et ouvertes)

# MASSIF : Vanoise

Rédigé le lundi 2 mars 2026 à 16h

## Estimation des risques pour le : MARDI 03 MARS

**ÉPAIS MANTEAU STABLE DANS UN BON NOMBRE DE PENTES LE MATIN, DÉSTABILISÉ PAR LE SOLEIL ENSUITE.**

2

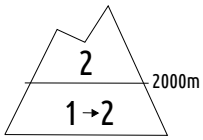


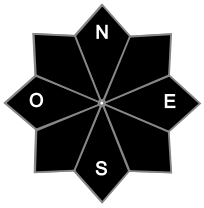


Au-dessus de 2000m indice de risque limité, plus bas indice faible évoluant en limité.

**Départs spontanés :** rares départs humides l'après-midi, rares plaques de fond.

**Déclenchements provoqués :** plaques humides au soleil, rares plaques dures dans les versants ombragés.

Indices de risque : 5 très fort - 4 fort - 3 marqué - 2 limité - 1 faible -- En noir : les pentes les plus dangereuses

## Stabilité du manteau neigeux

**Situation avalancheuse typique :** neige humide couche fragile persistante

**Déclenchements provoqués :**
- Dans les **pentes ensoleillées hébergeant des couches fragiles enfouies (E/O et S d'altitude)**, après plusieurs heures de soleil, l'enfoncement dans la neige humide devient important, rendant à nouveau possible la sollicitation d'une couche fragile enfouie. Dès lors, une **avalanche de neige humide avec propagation efficace** est possible. Taille 2 (moyenne), rarement 3 (grande).
- **Au-dessus de 2000 m, en versants ombragés (NO/N/NE), rares plaques dures** sur couche fragile persistante. Le déclenchement est **encore possible dans les zones moins enneigées** (abords de crête, croupes dégarnis) car la couche fragile est plus près de la surface. Taille 2, rarement 3, avec cassure 50/70 cm.

**Départs spontanés :**
- Rare avalanche de neige humide dans les pentes ayant chauffées au Soleil plusieurs heures. Taille 1 à 2, très rarement 3 lorsque l'humidification atteint une couche fragile enfouie.
- Rares plaques de fond, quelles que soient l'heure et l'orientation, plutôt sous 2400 m. Taille 2.

## Qualité de la neige

**Enneigement :** Les températures anormalement douces et le tassement font rentrer l'enneigement dans la normale, surtout en Sud et en basse montagne où la limite d'enneigement dans ces pentes remonte vite. Ailleurs le manteau se tasse considérablement.

**Limite skiable :** encore skiable dès 1100 m dans les prairies orientées Nord, plutôt 1500 m en Sud.

**Qualité de la neige :** en Sud, Est, Ouest, conditions de printemps idéales avec bon regel le matin et *"décaillage"* suivant la course du soleil. En Nord, neige croutée sous 2000 m (parfois plus haut). Au-dessus, neige encore froide, poudreuse dense à l'abri du vent, cartonnée voire dure dans les secteurs ventés (à l'approche des crêtes).

## Aperçu météo pour le mardi 03 mars

| nuit | matin | après-midi | soir |
|---|---|---|---|

Belle journée printanière.

| Pluie-Neige | | | | |
|---|---|---|---|---|
| Iso 0 °C | 2 200 m | 2 400 m | 2 600 m | 2 300 m |
| Vent 2500 m | ↗ 15 km/h | ↘ 10 km/h | → 5 km/h | → 5 km/h |
| Vent 3500 m | ↗ 20 km/h | → 15 km/h | → 10 km/h | → 10 km/h |

## Épaisseur de neige hors-piste

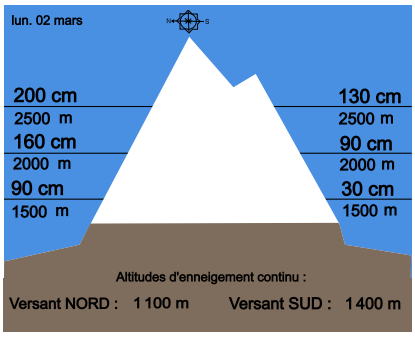


## Précipitations à 1800 m

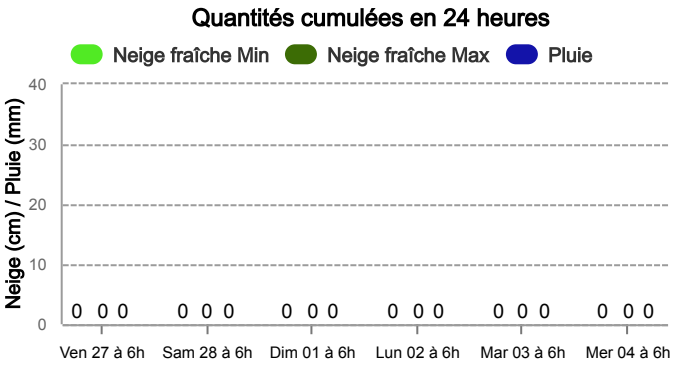


## Tendance du mercredi 04 mars

2

**Indice de risque limité**

Risque stationnaire. Bon regel le matin puis humidification marquée induisant rapidement un risque d'avalanche humide.

Pour consulter la vigilance en cours, veuillez vous rendre sur le site https://vigilance.meteofrance.fr/fr

Météo-France - 73 avenue de Paris, 94165 Saint-Mandé cedex - Contact : contact@meteo.fr

Rédigé par Météo-France avec la contribution des observateurs du réseau nivo-météorologiques. Partenariat : ANMSM (Maires de Stations de Montagne), DSF (Domaines Skiables de France), ADSP (Directeurs de Pistes et de la Sécurité des Stations de Sports d'Hiver) et autres acteurs de la montagne.

Bulletin neige & avalanches par téléphone au 0 892 68 10 20 Service 0,35 € / min + prix appel

RÉPUBLIQUE FRANÇAISE
*Liberté Égalité Fraternité*

METEO FRANCE
À VOS CÔTÉS, DANS UN CLIMAT QUI CHANGE

# Bulletin d'estimation du risque d'avalanche

## (valable en dehors des pistes balisées et ouvertes)

# MASSIF : Vanoise

Rédigé le lundi 2 mars 2026 à 16h

## Conditions nivo-météo des 7 derniers jours

| | mar. 24/02 | | | | mer. 25/02 | | | | jeu. 26/02 | | | | ven. 27/02 | | | | sam. 28/02 | | | | dim. 01/03 | | | | lun. 02/03 | | | |
|---|---|---|---|---|---|---|---|---|---|---|---|---|---|---|---|---|---|---|---|---|---|---|---|---|---|---|---|---|
| | 03h | 09h | 15h | 21h | 03h | 09h | 15h | 21h | 03h | 09h | 15h | 21h | 03h | 09h | 15h | 21h | 03h | 09h | 15h | 21h | 03h | 09h | 15h | 21h | 03h | 09h | 15h | 21h |
| Météo | | | | | | | | | | | | | | | | | | | | | | | | | | | | |
| Vent (km/h) | 45 | 40 | 30 | 25 | 20 | 20 | 20 | 15 | 15 | 15 | 15 | 15 | 15 | 15 | 25 | 30 | 25 | 25 | 30 | 25 | 25 | 20 | 20 | 15 | 15 | 20 | 25 | 25 |
| à 3500m | | | | | | | | | | | | | | | | | | | | | | | | | | | | |
| Vent (km/h) | 20 | 15 | 15 | 10 | 5 | 5 | 5 | 5 | 5 | 5 | 5 | 5 | 5 | 5 | 10 | 10 | 10 | 10 | 10 | 5 | 5 | 10 | 10 | 10 | 10 | 15 | 20 | 20 |
| à 2500m | | | | | | | | | | | | | | | | | | | | | | | | | | | | |

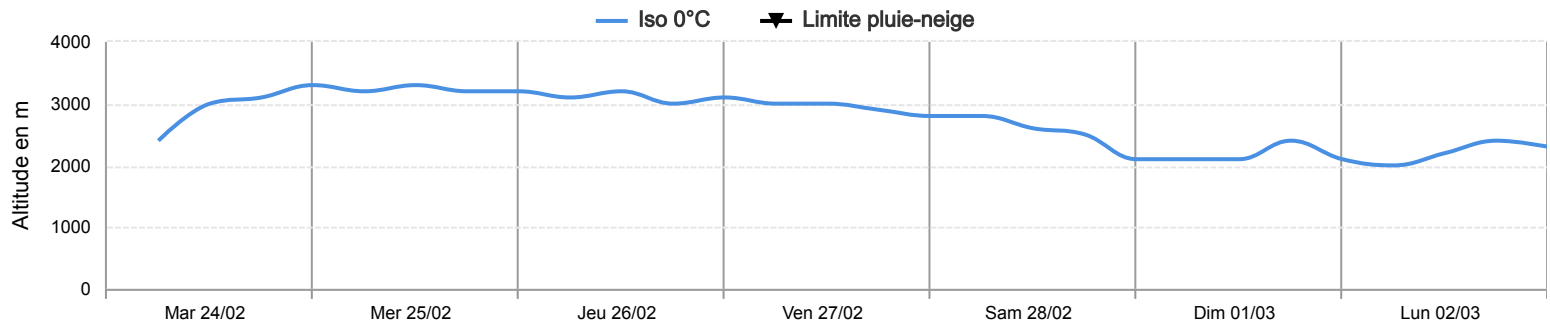


Neige fraîche à 06h

| Mar 24/02 | Mer 25/02 | Jeu 26/02 | Ven 27/02 | Sam 28/02 | Dim 01/03 | Lun 02/03 |
|---|---|---|---|---|---|---|
| 0 cm | 0 cm | 0 cm | 0 cm | 0 cm | 0 cm | |

| Risque d'avalanche | mar. 24/02 | mer. 25/02 | jeu. 26/02 | ven. 27/02 | sam. 28/02 | dim. 01/03 | lun. 02/03 |
|---|---|---|---|---|---|---|---|
| | 3 | 3 | 3 | 3 | 2 | 2 | 2 |

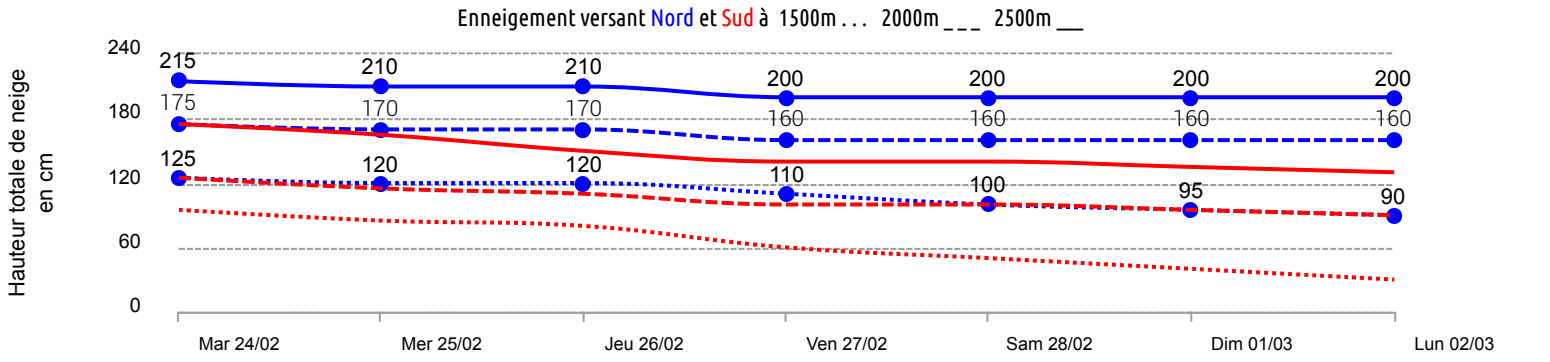


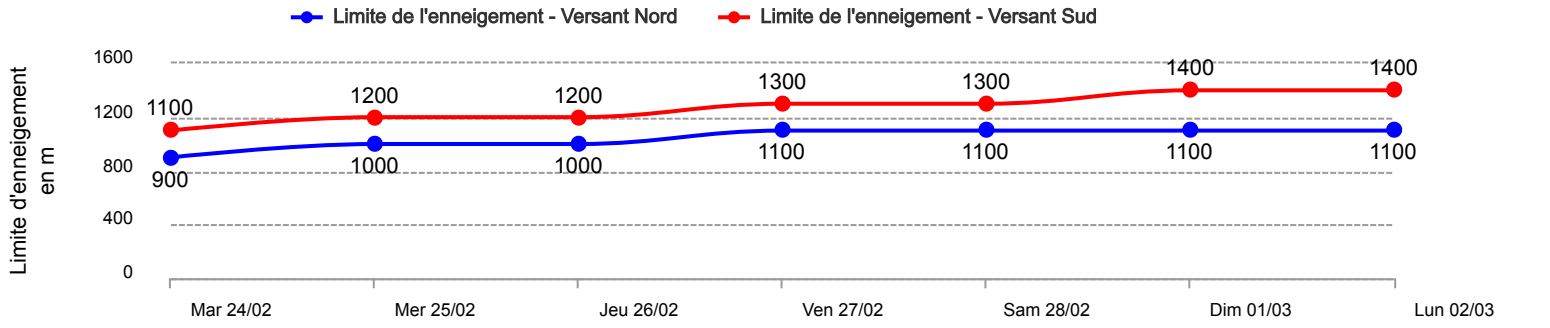


Pour consulter la vigilance en cours, veuillez vous rendre sur le site https://vigilance.meteofrance.fr/fr


Météo-France - 73 avenue de Paris, 94165 Saint-Mandé cedex - Contact : contact@meteo.fr


Bulletin neige & avalanches par téléphone au

0 892 68 10 20 Service 0,35 € / min + prix appel


Rédigé par Météo-France avec la contribution des observateurs du réseau nivo-météorologiques. Partenariat : ANMSM (Maires de Stations de Montagne), DSF (Domaines Skiables de France), ADSP (Directeurs de Pistes et de la Sécurité des Stations de Sports d'Hiver) et autres acteurs de la montagne.