Bulletin d'estimation du risque d'avalanche
(valable en dehors des pistes balisées et ouvertes)

MASSIF : Cerdagne Canigou

Rédigé le lundi 2 mars 2026 à 17h

Estimation des risques pour le : MARDI 03 MARS

MANTEAU NEIGEUX BIEN STABILISÉ, RARES STRUCTURES DE PLAQUES EN NORD-EST D'ALTITUDE

2

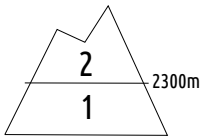

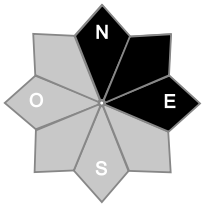

Au-dessus de 2300m indice de risque limité, plus bas indice faible.

Départs spontanés : Quelques avalanches de fond possibles par humidification

Déclenchements provoqués : Peu probables avec de rares structures de plaques en neige froide à haute altitude.

Indices de risque : 5 très fort - 4 fort - 3 marqué - 2 limité - 1 faible -- En noir : les pentes les plus dangereuses

Stabilité du manteau neigeux

Situation avalancheuse typique : neige humide — avalanches de fond

Départs spontanés :
Peu probable le matin puis l'activité avalancheuse peut reprendre au fil de la journée dans les pentes raides prenant le soleil ou sous les nuages, notamment à proximité des rochers. Ces départs en neige humide sont le plus souvent ponctuels.
En dessous de 2200 m principalement, des avalanches de fond sont encore possibles à toute heure, de taille petite à moyenne avec des fissures, reptations ou gueules de baleine visibles actuellement.

Déclenchements provoqués :
Peu probables ou alors par forte surcharge sur le manteau neigeux. Il reste dans quelques couloirs ombragés des versants nord-est, plus chargés en neige, quelques structures de plaques, mais leur déclenchement nécessitent de fortes contraintes en général.

Autre: Risque de glissade/dévissage en raison de la présence de neige parfois très dure voire de glace vive notamment sur les crêtes pelées par le vent.

Qualité de la neige

Enneigement :
L'enneigement est largement supérieur à celui des cinq dernières années et se situe au plus haut par rapport aux statistiques plus anciennes. Malgré la douceur de la semaine passée, la neige a plutôt bien résisté avec de bonnes quantités permettant de chausser dès 1500 à 1600m d'altitude.

Qualité de la neige :
Mardi matin, assez bon regel nocturne des pentes humidifiées dimanche avec une neige dure et portante. En journée selon l'ennuagement humidification progressive du manteau neigeux d'où une neige devenant lourde et humide sous 2300m. Dans quelques secteurs d'altitude ombragés au-dessus de 2300 m, on trouvera encore de la neige restée sèche en poudre maintenant dense dans les pentes abritées du vent. Proche des crêtes et sommet, l'enneigement est toutefois très hétérogène avec des secteurs bien soufflés et parfois glacés, particulièrement sur les flancs ouest.

Aperçu météo pour le mardi 03 mars

Rares averses dans l'après-midi

	nuit	matin	après-midi	soir
Pluie-Neige			2 100 m	
Iso 0 °C	2 500 m	2 400 m	2 500 m	2 500 m
Vent 2000 m	30 km/h	25 km/h	20 km/h	15 km/h
Vent 3000 m	45 km/h	35 km/h	25 km/h	25 km/h

Épaisseur de neige hors-piste

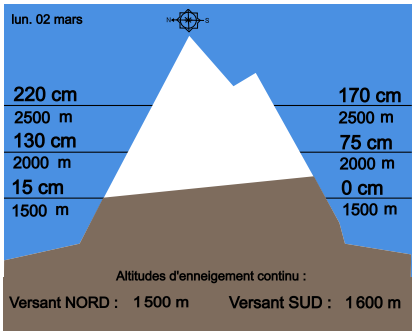

Précipitations à 1800 m

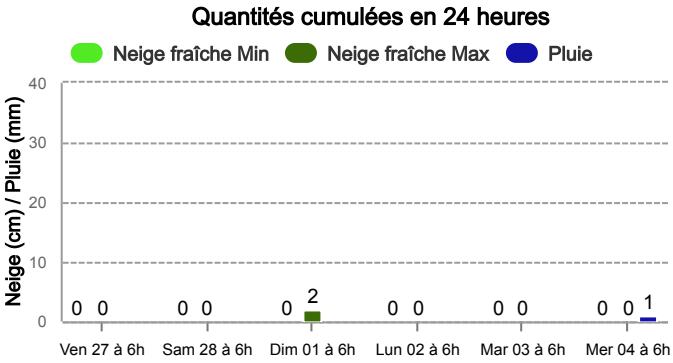

Tendance du mercredi 04 mars

2

Indice de risque limité

Risque stationnaire les conditions nivologiques évoluant très peu

Pour consulter la vigilance en cours, veuillez vous rendre sur le site https://vigilance.meteofrance.fr/fr

Météo-France - 73 avenue de Paris, 94165 Saint-Mandé cedex - Contact : contact@meteo.fr

Rédigé par Météo-France avec la contribution des observateurs du réseau nivo-météorologiques. Partenariat : ANMSM (Maires de Stations de Montagne), DSF (Domaines Skiables de France), ADSP (Directeurs de Pistes et de la Sécurité des Stations de Sports d'Hiver) et autres acteurs de la montagne.

Bulletin neige & avalanches par téléphone au
0 892 68 10 20 Service 0,35 € / min + prix appel

RÉPUBLIQUE FRANÇAISE
Liberté Égalité Fraternité

METEO FRANCE
À VOS CÔTÉS, DANS UN CLIMAT QUI CHANGE

Bulletin d'estimation du risque d'avalanche

(valable en dehors des pistes balisées et ouvertes)

MASSIF : Cerdagne Canigou

Rédigé le lundi 2 mars 2026 à 17h

Conditions nivo-météo des 7 derniers jours

	mar. 24/02				mer. 25/02				jeu. 26/02				ven. 27/02				sam. 28/02				dim. 01/03				lun. 02/03			
	03h	09h	15h	21h	03h	09h	15h	21h	03h	09h	15h	21h	03h	09h	15h	21h	03h	09h	15h	21h	03h	09h	15h	21h	03h	09h	15h	21h
Météo																												
Vent (km/h)	20	20	20	25	20	25	25	20	20	15	15	15	20	20	25	30	30	30	30	20	20	25	25	25	40	50	50	40
à 3000m																												
Vent (km/h)	10	10	10	15	15	15	15	10	10	10	10	10	15	15	15	20	15	15	20	10	10	15	20	15	20	30	30	25
à 2000m																												

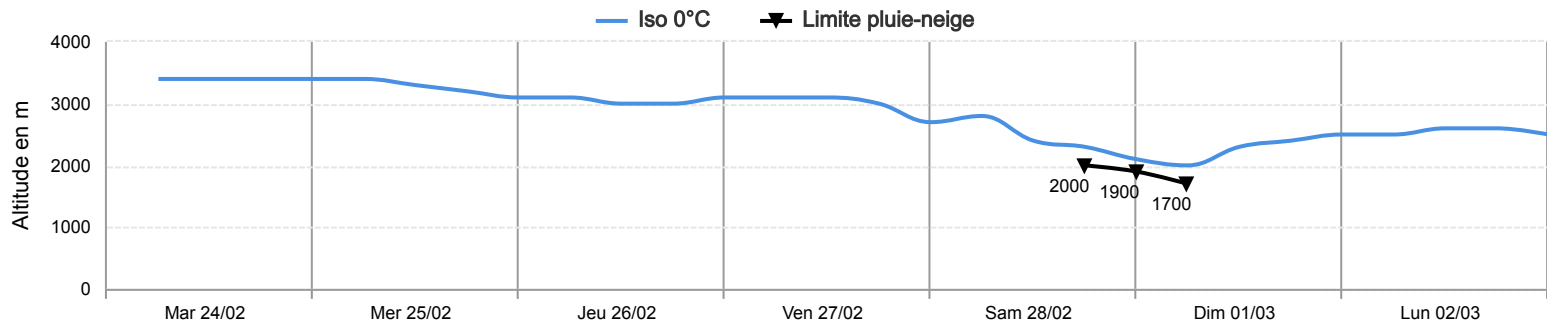

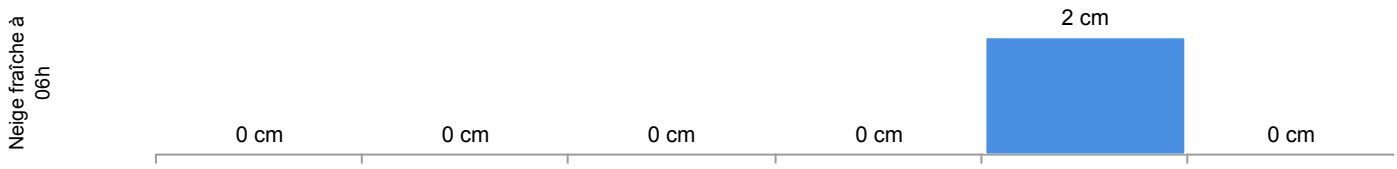

Risque d'avalanche	mar. 24/02	mer. 25/02	jeu. 26/02	ven. 27/02	sam. 28/02	dim. 01/03	lun. 02/03
	2	2	2	2	2	2	2

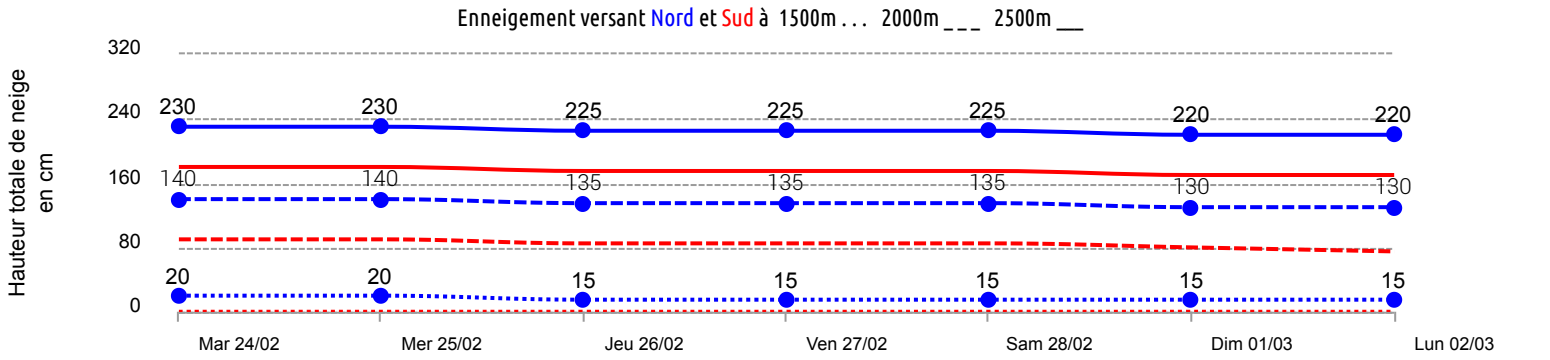

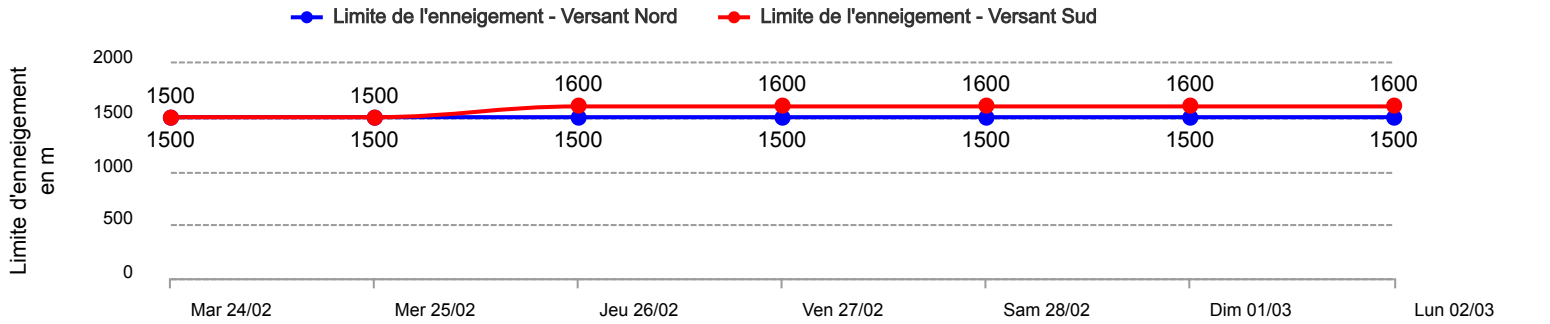

Pour consulter la vigilance en cours, veuillez vous rendre sur le site https://vigilance.meteofrance.fr/fr

Météo-France - 73 avenue de Paris, 94165 Saint-Mandé cedex - Contact : contact@meteo.fr

Rédigé par Météo-France avec la contribution des observateurs du réseau nivo-météorologiques. Partenariat : ANMSM (Maires de Stations de Montagne), DSF (Domaines Skiables de France), ADSP (Directeurs de Pistes et de la Sécurité des Stations de Sports d'Hiver) et autres acteurs de la montagne.

Bulletin neige & avalanches par téléphone au
0 892 68 10 20 Service 0,35 € / min + prix appel