Bulletin d'estimation du risque d'avalanche

(valable en dehors des pistes balisées et ouvertes)

MASSIF : Haute-Ariege

Rédigé le lundi 2 mars 2026 à 17h

Estimation des risques pour le : MARDI 03 MARS

MANTEAU NEIGEUX PRINTANIER DANS LES VERSANTS AU SOLEIL ET QUELQUES STRUCTURES DE PLAQUES EN NORD D'ALTITUDE.

2

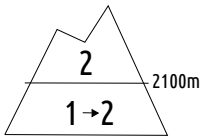

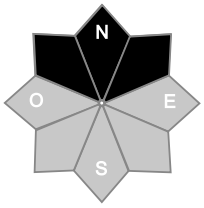

plaques en altitude

Au-dessus de 2100m indice de risque limité, plus bas indice faible évoluant en limité.

Départs spontanés : Avalanches de fond, rarement grandes, surtout au soleil

Déclenchements provoqués : Sturctures de plaques encore présentes

Indices de risque : 5 très fort - 4 fort - 3 marqué - 2 limité - 1 faible -- En noir : les pentes les plus dangereuses

Stabilité du manteau neigeux

Situation avalancheuse typique :

avalanches de fond

couche fragile persistante

Départs spontanés :

De rares, mais parfois épaisses avalanches de fond peuvent se produire en mobilisant des quantités conséquentes de neige lourde. Il est fait état, dans de nombreuses orientations et plutôt sous 2200 m, de larges fissures visibles (gueules de baleine) dans des pentes au sol souvent lisse, signes avant-coureurs de telles avalanches. Le départ de ces avalanches de fond est plus fréquent de l'après-midi à la soirée mais peut aussi se produire à d'autres moments de la journée.
Reprise également de l'activité avalancheuse en neige humide avec le soleil, dans les pentes raides encore non purgées et à proximité des rochers, avec des avalanches en départ le plus souvent ponctuel et restant de taille modeste.

Déclenchements provoqués :

Quelques avalanches de plaques sont encore possiblement déclenchables au passage d'un skieur, au-dessus de 2000/2200 m dans les secteurs restés en neige froide, donc plutôt orientés nord. Ces plaques sont souvent assez fines (10/20 cm). Elles gagnent en épaisseur en altitude et deviennent alors de plus en plus difficilement déclenchables.
Observables : neige travaillée par le vent en surface surplombant une couche de neige sans cohésion.

Autre: Risque de glissade/dévissage en raison de la présence de neige parfois très dure voire de glace vive notamment sur les crêtes pelées par le vent.

Qualité de la neige

Enneigement :

L'enneigement est encore légèrement excédentaire dès la moyenne montagne après les nombreuses perturbations neigeuses depuis le début de l'année. Les vallons ombragés sont encore bien enneigés avec des quantités de neige importantes dès 1400 m notamment en versant Est.
La limite skiable est autour de 1500 à 1600m plein Sud alors que certaines vallées ombragées sont encore enneigées dès 1300m.

Qualité de la neige :

Mardi matin, assez bon regel nocturne des pentes humidifiées avec une neige dure et portante. En journée, reprise de l'humidification au soleil puis sous les nuages avec une neige devenant lourde et humide jusqu'à 2000/2200m en tous versants.
En altitude, à partir de 2000/2200 m, rarement plus bas, on trouvera encore de la neige restée sèche en poudre maintenant dense dans les pentes abritées du vent. Par contre, les crêtes et sommets sont souvent pelés ou en neige dure, parfois en glace, en versants Ouest principalement.

Aperçu météo pour le mardi 03 mars

	nuit	matin	après-midi	soir
Rares averses dans l'après-midi				
Pluie-Neige			2 100 m	
Iso 0 °C	2 700 m	2 600 m	2 500 m	2 500 m
Vent 2000 m	↑ 35 km/h	↑ 25 km/h	↑ 20 km/h	↑ 15 km/h
Vent 3000 m	↑ 35 km/h	↑ 25 km/h	↗ 20 km/h	↑ 20 km/h

Épaisseur de neige hors-piste

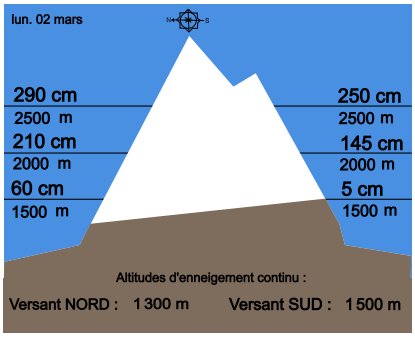

Précipitations à 1800 m

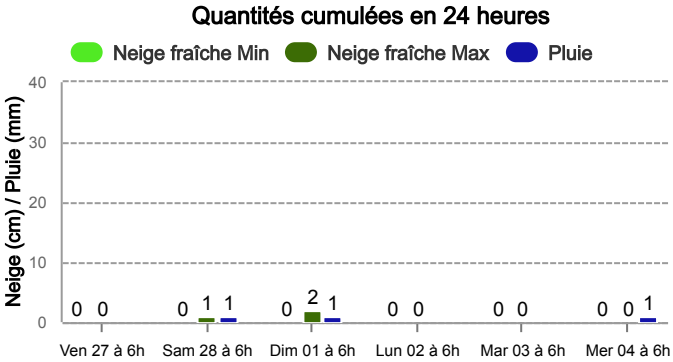

Tendance du mercredi 04 mars

2

Indice de risque limité

Risque stationnaire les conditions nivologiques évoluant très peu

Pour consulter la vigilance en cours, veuillez vous rendre sur le site https://vigilance.meteofrance.fr/fr

Météo-France - 73 avenue de Paris, 94165 Saint-Mandé cedex - Contact : contact@meteo.fr

Rédigé par Météo-France avec la contribution des observateurs du réseau nivo-météorologiques. Partenariat : ANMSM (Maires de Stations de Montagne), DSF (Domaines Skiables de France), ADSP (Directeurs de Pistes et de la Sécurité des Stations de Sports d'Hiver) et autres acteurs de la montagne.

Bulletin neige & avalanches par téléphone au

0 892 68 10 20 Service 0,35 € / min + prix appel

RÉPUBLIQUE FRANÇAISE
Liberté Égalité Fraternité

METEO FRANCE
À VOS CÔTÉS, DANS UN CLIMAT QUI CHANGE

Bulletin d'estimation du risque d'avalanche

(valable en dehors des pistes balisées et ouvertes)

MASSIF : Haute-Ariege

Rédigé le lundi 2 mars 2026 à 17h

Conditions nivo-météo des 7 derniers jours

	mar. 24/02				mer. 25/02				jeu. 26/02				ven. 27/02				sam. 28/02				dim. 01/03				lun. 02/03			
	03h	09h	15h	21h	03h	09h	15h	21h	03h	09h	15h	21h	03h	09h	15h	21h	03h	09h	15h	21h	03h	09h	15h	21h	03h	09h	15h	21h
Météo																												
Vent (km/h)	20	20	25	25	20	25	25	20	20	15	15	15	20	20	25	30	30	20	20	15	20	25	30	40	40	50	50	45
à 3000m																												
Vent (km/h)	10	10	15	15	15	15	15	10	10	10	10	10	15	15	15	20	10	10	15	5	10	20	25	30	30	35	35	30
à 2000m																												

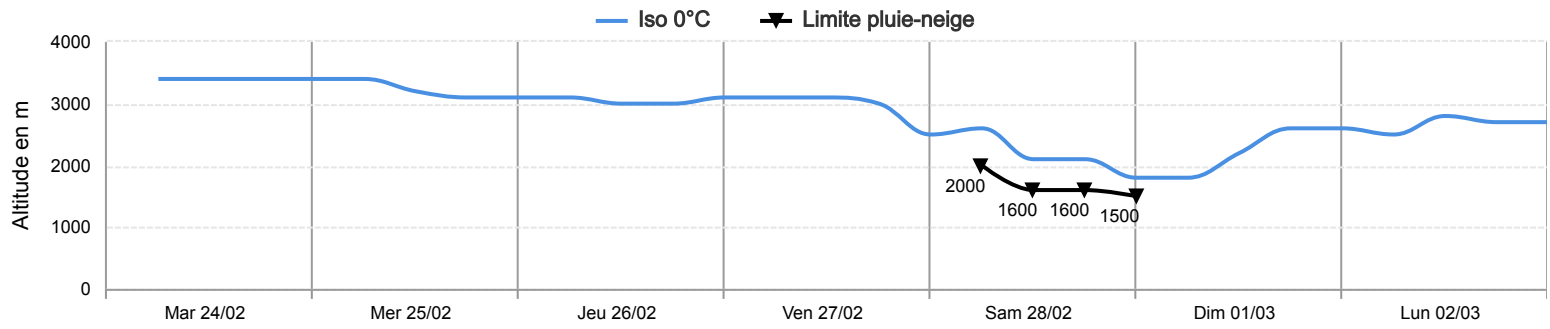

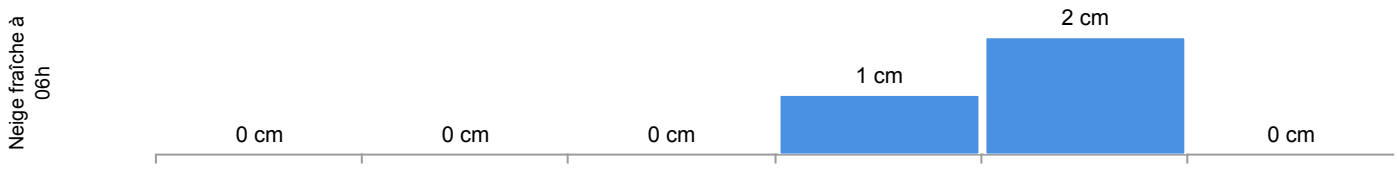

Risque d'avalanche	mar. 24/02	mer. 25/02	jeu. 26/02	ven. 27/02	sam. 28/02	dim. 01/03	lun. 02/03
	2	2	2	2	2	2	2

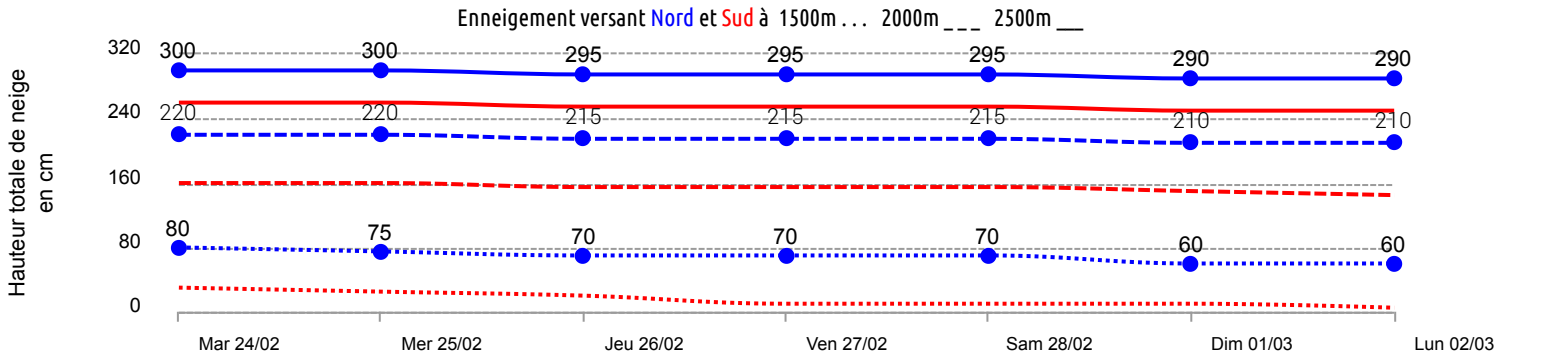

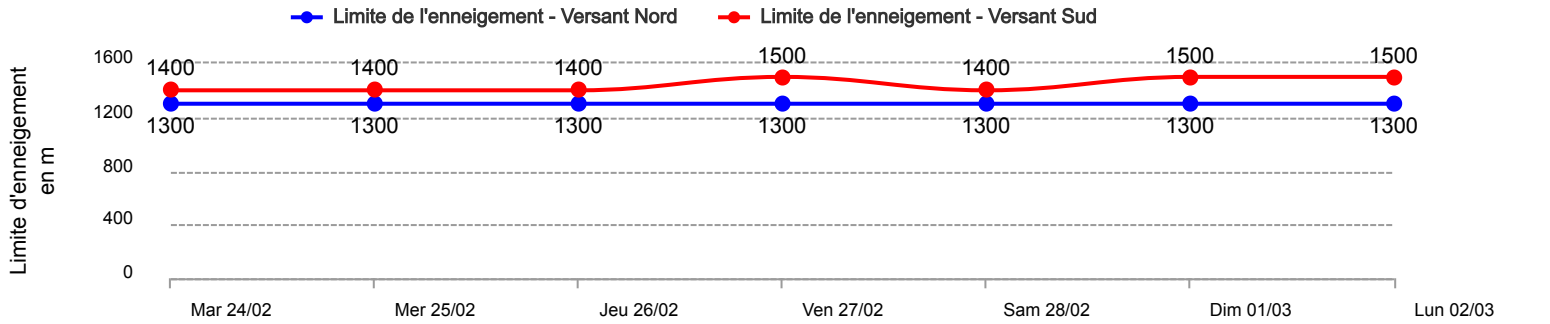

Pour consulter la vigilance en cours, veuillez vous rendre sur le site https://vigilance.meteofrance.fr/fr

Météo-France - 73 avenue de Paris, 94165 Saint-Mandé cedex - Contact : contact@meteo.fr

Rédigé par Météo-France avec la contribution des observateurs du réseau nivo-météorologiques. Partenariat : ANMSM (Maires de Stations de Montagne), DSF (Domaines Skiables de France), ADSP (Directeurs de Pistes et de la Sécurité des Stations de Sports d'Hiver) et autres acteurs de la montagne.

Bulletin neige & avalanches par téléphone au
0 892 68 10 20 Service 0,35 € / min + prix appel