ICGC Institut Cartogràfic i Geològic de Catalunya

Servei Meteorològic de Catalunya meteo.cat

Boletín de peligro de aludes para el Pirineo de Catalunya
Del 03/03/2026 al 04/03/2026

(Válido fuera pistas de esquí y zonas no controladas)

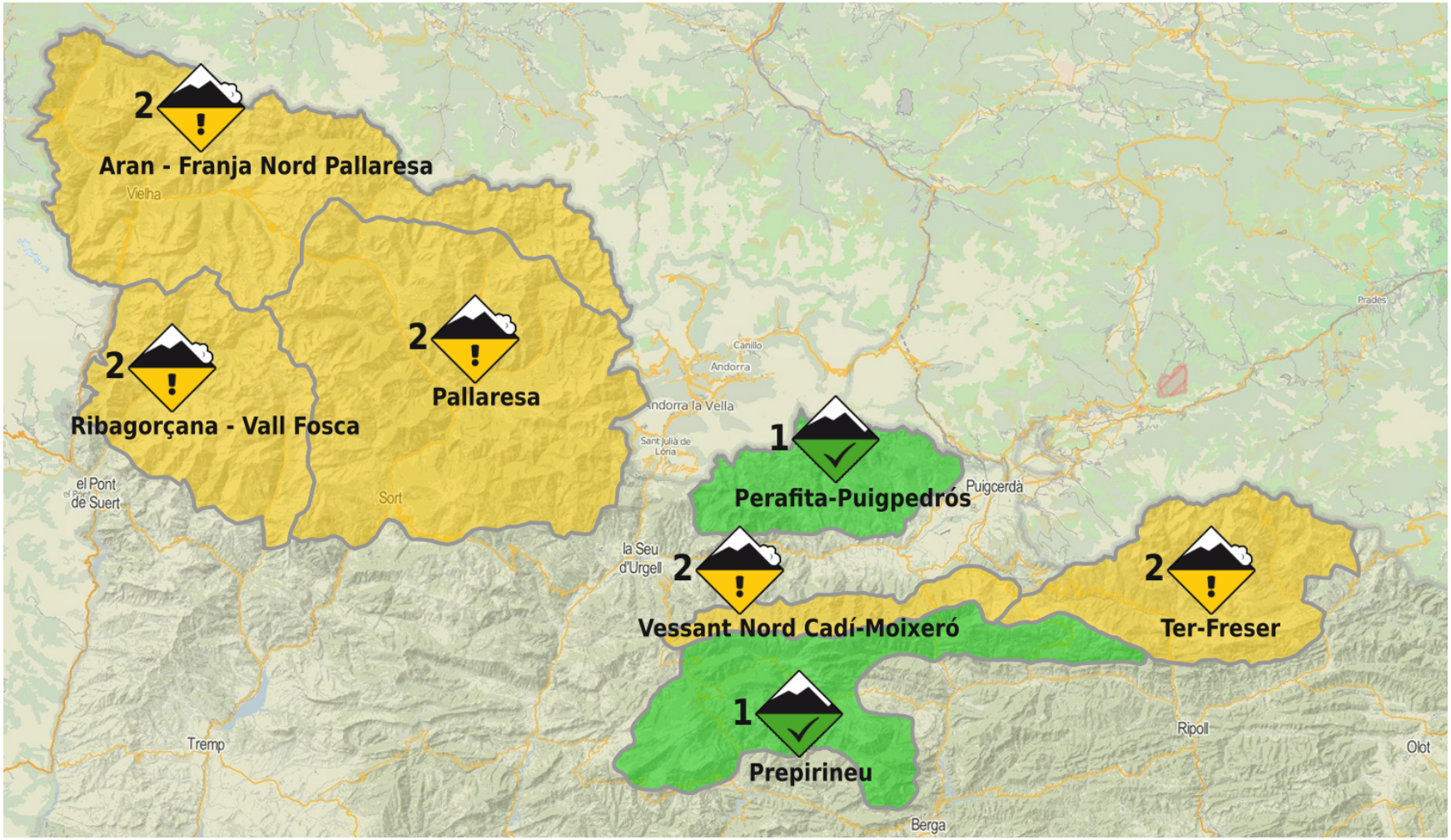

5 MUY FUERTE	4 FUERTE	3 NOTABLE	2 LIMITADO	1 DÉBIL

ICGC Institut Cartogràfic i Geològic de Catalunya

Servei Meteorològic de Catalunya

Boletín de peligro de aludes Aran - Franja Nord Pallaresa Del 03/03/2026 al 04/03/2026

(Válido fuera pistas de esquí y zonas no controladas)

LIMITADO (2).

Situación primaria

Deslizamientos basales **Distribución** **Tamaño** **Origen** **Tendencia**

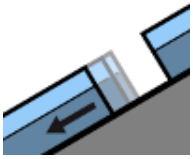

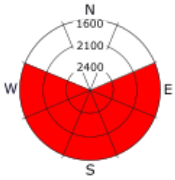

Situación secundaria

Nieve húmeda **Distribución** **Tamaño** **Origen** **Tendencia**

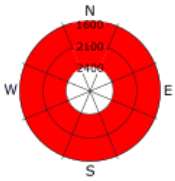

Estado del manto nivoso

El manto se humedece y pierde cohesión por debajo de 2.200-2.300 m debido a lloviznas y nieblas y por algunos centímetros de nieve reciente húmeda en cotas altas. Los deslizamientos basales volverán a reactivarse progresivamente. Son más probables a partir del mediodía. Serán de tamaño 2, mediano, suficiente para enterrar a una persona, puntualmente mayor. Se desprenden en terreno herboso y liso; evitad situaros bajo fisuras en el manto. En las cotas más elevadas se está formando alguna pequeña placa de viento en orientaciones norte que se podría desprender al paso de una persona, en caso de chubascos de nieve más intensos. El martes y el miércoles pueden caer algunos aludes de nieve húmeda de tamaño 1, pequeño, sin capacidad de enterrar a una persona, pero sí de hacernos perder el equilibrio. El miércoles por la mañana, debido a la abundante nubosidad, el manto difícilmente rehelará por la mañana, y, de hecho, las costras existentes poco a poco se irán ablandando y debilitando.

Distribución del manto nivoso

Hay nieve por encima de unos 1.400 ma umbrías y 1.600 ma solanas. Los espesores a unos 2.200 m son superiores a los normales y rondan los 120-140 cm en el norte de Aran y los 160-200 cm en la Franja Norte Pallaresa y en el sur de Aran, puntualmente superiores.

Tendencia para las próximas 48-72h

Para el jueves y el viernes aumentaría la actividad de aludes, por una mayor acumulación de nieve reciente húmeda en cotas altas y por la formación de placas de viento por viento del E y del S. Peligro EN AUMENTO.

El próximo boletín será emitido el día 2026-03-04

5 MUY FUERTE	4 FUERTE	3 NOTABLE	2 LIMITADO	1 DÉBIL

EAWS EUROPEAN AVALANCHE WARNING SERVICES

ICGC Institut Cartogràfic i Geològic de Catalunya

Servei Meteorològic de Catalunya meteo.cat

Boletín de peligro de aludes Ribagorçana - Vall Fosca Del 03/03/2026 al 04/03/2026

(Válido fuera pistas de esquí y zonas no controladas)

LIMITADO (2).

Situación primaria

Nieve húmeda

Distribución

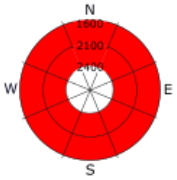

Tamaño

Origen

Tendencia

Situación secundaria

Deslizamientos basales

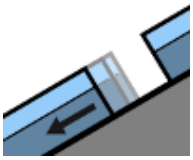

Distribución

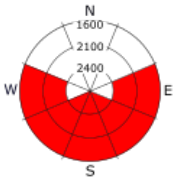

Tamaño

Origen

Tendencia

Estado del manto nivoso

El manto se humedece y pierde cohesión por debajo de 2.200-2.300 m debido a lloviznas y nieblas y por algunos centímetros de nieve reciente húmeda en cotas altas. Los deslizamientos basales volverán a reactivarse progresivamente. Son más probables a partir del mediodía. Serán de tamaño 2, mediano, suficiente para enterrar a una persona, puntualmente mayor. Se desprenden en terreno herboso y liso; evitad situaros bajo fisuras en el manto. En las cotas más elevadas se está formando alguna pequeña placa de viento en orientaciones norte que se podría desprender al paso de una persona, en caso de chubascos de nieve más intensos. El martes y el miércoles pueden caer algunos aludes de nieve húmeda de tamaño 1, pequeño, sin capacidad de enterrar a una persona, pero sí de hacernos perder el equilibrio. El miércoles por la mañana, debido a la abundante nubosidad, el manto difícilmente rehelará por la mañana, y, de hecho, las costras existentes poco a poco se irán ablandando y debilitando.

Distribución del manto nivoso

Hay nieve en el suelo a 1.500 m en terreno umbrío, y por encima de unos 1.700-1800 m en laderas soleadas. El manto es esquiable por encima de unos 1.600 m en umbrías. Los espesores alcanzan los 100-140 cm en cotas medias. Estos valores son superiores a los normales para la época.

Tendencia para las próximas 48-72h

Para el jueves y el viernes aumentaría la actividad de aludes, por una mayor acumulación de nieve reciente húmeda en cotas altas y por la formación de placas de viento por viento del E y del S. Peligro EN AUMENTO.

El próximo boletín será emitido el día 2026-03-04

5 MUY FUERTE	4 FUERTE	3 NOTABLE	2 LIMITADO	1 DÉBIL

EAWS EUROPEAN AVALANCHE WARNING SERVICES

ICGC Institut Cartogràfic i Geològic de Catalunya

Servei Meteorològic de Catalunya meteo.cat

Boletín de peligro de aludes Pallaresa
Del 03/03/2026 al 04/03/2026

(Válido fuera pistas de esquí y zonas no controladas)

LIMITADO (2).

Situación primaria

Nieve húmeda

Distribución

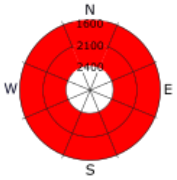

Tamaño

Origen

Tendencia

Situación secundaria

Deslizamientos basales

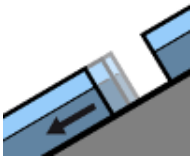

Distribución

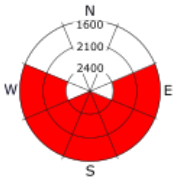

Tamaño

Origen

Tendencia

Estado del manto nivoso

El manto se humedece y pierde cohesión por debajo de 2.200-2.300 m debido a lloviznas y nieblas y por algunos centímetros de nieve reciente húmeda en cotas altas. Los deslizamientos basales volverán a reactivarse progresivamente. Son más probables a partir del mediodía. Serán de tamaño 2, mediano, suficiente para enterrar a una persona, puntualmente mayor. Se desprenden en terreno herboso y liso; evitatd situaros bajo fisuras en el manto. En las cotas más elevadas se está formando alguna pequeña placa de viento en orientaciones norte que se podría desprender al paso de una persona, en caso de chubascos de nieve más intensos. El martes y el miércoles pueden caer algunos aludes de nieve húmeda de tamaño 1, pequeño, sin capacidad de enterrar a una persona, pero sí de hacernos pierde el equilibrio. El miércoles por la mañana, debido a la abundante nubosidad, el manto difícilmente rehelará por la mañana, y, de hecho, las costras existentes poco a poco se irán ablandando y debilitando.

Distribución del manto nivoso

Hay nieve en el suelo a 1.500 m en terreno umbrío, esquiable por encima de unos 1.600 m; en orientaciones soleadas la nieve está presente por encima de unos 1.700-1.800 m. Los espesores alcanzan los 110-150 cm en cotas medias.

Tendencia para las próximas 48-72h

Para el jueves y el viernes aumentaría la actividad de aludes, por una mayor acumulación de nieve reciente húmeda en cotas altas y por la formación de placas de viento de viento por viento del E y del S. Peligro EN AUMENTO.

El próximo boletín será emitido el día 2026-03-04

5 MUY FUERTE	4 FUERTE	3 NOTABLE	2 LIMITADO	1 DÉBIL

EAWS EUROPEAN AVALANCHE WARNING SERVICES

ICGC Institut Cartogràfic i Geològic de Catalunya

Servei Meteorològic de Catalunya

Boletín de peligro de aludes Perafita-Puigpedrós Del 03/03/2026 al 04/03/2026

(Válido fuera pistas de esquí y zonas no controladas)

DÉBIL (1).

Situación primaria

Nieve húmeda

Distribución

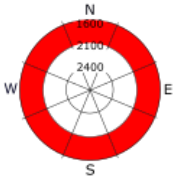

Tamaño

Origen

Tendencia

Estado del manto nivoso

El manto se va humedeciendo y perdiendo cohesión superficialmente por debajo de 2.200-2.300 m debido a lloviznas y nieblas y por algunos centímetros de nieve reciente húmeda en cotas altas. El martes y el miércoles caerán purgas y algún alud de nieve húmeda de tamaño 1, pequeño, sin capacidad de enterrar a una persona, pero sí de hacernos pierde el equilibrio. Bajo collados y cordales en las cotas más elevadas no se descarta que se forme alguna pequeña placa de viento en orientaciones norte que podría desprenderse al paso de una persona, en caso de chubascos de nieve más intensos. El miércoles por la mañana, debido a la abundante nubosidad, el manto difícilmente regelará por la mañana, y, de hecho, las costras existentes poco a poco se irán ablandando y debilitando.

Distribución del manto nivoso

Hay nieve en el suelo por encima de unos 1.600 m, si bien en las solanas más derechas el manto sigue retrocediendo y la nieve está presente por encima de 1.800 m. Los espesores, aunque irregulares, rondan los 70-90 cm en cotas medias, con frecuentes deflaciones en orientaciones norte y oeste por encima del nivel del bosque. Son grosores muy por encima de los habituales por la época.

Tendencia para las próximas 48-72h

Para el jueves y el viernes ya se espera actividad de aludes, por una mayor acumulación de nieve reciente húmeda en cotas altas y por la formación de placas de viento por viento del E y del S. Peligro EN AUMENTO.

El próximo boletín será emitido el día 2026-03-04

5 MUY FUERTE	4 FUERTE	3 NOTABLE	2 LIMITADO	1 DÉBIL

EAWS EUROPEAN AVALANCHE WARNING SERVICES

ICGC Institut Cartogràfic i Geològic de Catalunya

Servei Meteorològic de Catalunya

Boletín de peligro de aludes
Vessant Nord Cadí-Moixeró
Del 03/03/2026 al 04/03/2026

(Válido fuera pistas de esquí y zonas no controladas)

LIMITADO (2).

Situación primaria

Nieve húmeda

Distribución

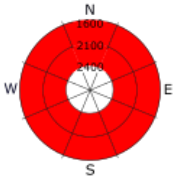

Tamaño

Origen

Tendencia

Estado del manto nivoso

El manto se va humedeciendo y perdiendo cohesión superficialmente por debajo de 2.200-2.300 m debido a lloviznas y nieblas y por algunos centímetros de nieve reciente húmeda en cotas altas. El martes y el miércoles por las canales pueden caer algunos aludes de nieve húmeda de tamaño 1, pequeño, sin capacidad de enterrar a una persona, pero sí de hacernos perder el equilibrio. Bajo collados y cordales en las cotas más elevadas se puede ir formando alguna pequeña placa de viento en orientaciones norte que se podría desprender al paso de una persona, en caso de chubascos de nieve más intensos. El miércoles por la mañana, debido a la abundante nubosidad, el manto difícilmente rehelará por la mañana, y, de hecho, las costras existentes poco a poco se irán ablandando y debilitando.

Distribución del manto nivoso

En umbrías hay nieve por encima de 1.500 m, esquiable por encima de unos 1.700 m. En solanas la nieve está presente por encima de 1.700 m. Los espesores están alrededor de 130-160 cm en cotas medias. Estos valores siguen siendo muy excedentarios para la época del año.

Tendencia para las próximas 48-72h

Para el jueves y el viernes aumentaría la actividad de aludes, por una mayor acumulación de nieve reciente húmeda en cotas altas y por la formación de placas de viento por viento del E y del S. Peligro EN AUMENTO.

El próximo boletín será emitido el día 2026-03-04

5 MUY FUERTE	4 FUERTE	3 NOTABLE	2 LIMITADO	1 DÉBIL

EAWS EUROPEAN AVALANCHE WARNING SERVICES

ICGC Institut Cartogràfic i Geològic de Catalunya

Servei Meteorològic de Catalunya

Boletín de peligro de aludes Prepirineu
Del 03/03/2026 al 04/03/2026

(Válido fuera pistas de esquí y zonas no controladas)

DÉBIL (1).

Situación primaria

Nieve húmeda

Distribución

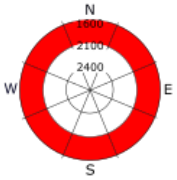

Tamaño

Origen

Tendencia

Estado del manto nivoso

El manto se va humedeciendo y perdiendo cohesión superficialmente por debajo de 2.200-2.300 m debido a lloviznas y nieblas y por algunos centímetros de nieve reciente húmeda en cotas altas. El martes y el miércoles caerán purgas y algún alud de nieve húmeda de tamaño 1, pequeño, sin capacidad de enterrar a una persona, pero sí de hacernos perder el equilibrio. Bajo collados y cordales en las cotas más elevadas no se descarta que se forme alguna pequeña placa de viento en orientaciones norte que podría desprenderse al paso de una persona, en caso de chubascos de nieve más intensos. El miércoles por la mañana, debido a la abundante nubosidad, el manto difícilmente rehelará por la mañana, y, de hecho, las costras existentes poco a poco se irán ablandando y debilitando.

Distribución del manto nivoso

Hay nieve en el suelo por encima de unos 1.600 m, si bien en las solanas más derechas el manto sigue retrocediendo y la nieve está presente por encima de 1.800 m. Los espesores, aunque irregulares, rondan los 70-90 cm en cotas medias, con frecuentes deflaciones en orientaciones norte y oeste por encima del nivel del bosque.

Tendencia para las próximas 48-72h

Para el jueves y el viernes ya se espera actividad de aludes, por una mayor acumulación de nieve reciente húmeda en cotas altas y por la formación de placas de viento por viento del E y del S. Peligro EN AUMENTO.

El próximo boletín será emitido el día 2026-03-04

5 MUY FUERTE	4 FUERTE	3 NOTABLE	2 LIMITADO	1 DÉBIL

EAWS EUROPEAN AVALANCHE WARNING SERVICES

ICGC Institut Cartogràfic i Geològic de Catalunya

Servei Meteorològic de Catalunya

Boletín de peligro de aludes Ter-Freser
Del 03/03/2026 al 04/03/2026

(Válido fuera pistas de esquí y zonas no controladas)

LIMITADO (2).

Situación primaria

Nieve húmeda

Distribución

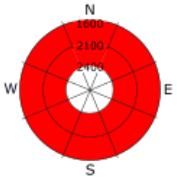

Tamaño

Origen

Tendencia

Situación secundaria

Deslizamientos basales

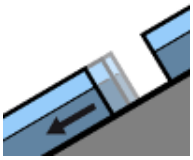

Distribución

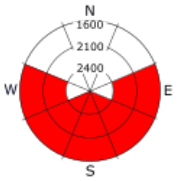

Tamaño

Origen

Tendencia

Estado del manto nivoso

El manto se humedece y pierde cohesión por debajo de 2.200-2.300 m debido a lloviznas y nieblas y por algunos centímetros de nieve reciente húmeda en cotas altas. Los deslizamientos basales volverán a reactivarse progresivamente. Son más probables a partir del mediodía. Serán de tamaño 2, mediano, suficiente para enterrar a una persona, puntualmente mayor. Se desprenden en terreno herboso y liso; evitad situaros bajo fisuras en el manto. En las cotas más elevadas se está formando alguna pequeña placa de viento en orientaciones norte que se podría desprender al paso de una persona, en caso de chubascos de nieve más intensos. El martes y el miércoles pueden caer algunos aludes de nieve húmeda de tamaño 1, pequeño, sin capacidad de enterrar a una persona, pero sí de hacernos perder el equilibrio. El miércoles por la mañana, debido a la abundante nubosidad, el manto difícilmente rehelará por la mañana, y, de hecho, las costras existentes poco a poco se irán ablandando y debilitando.

Distribución del manto nivoso

El manto nivoso presenta grosores muy excedentarios para la época del año. En lugares no afectados por el viento los grosores oscila entre 80-100 cm a unos 2.000 my 180-200 cm por encima de 2.400 m. Es esquiable a partir de unos 1600 m. Aparecen deflaciones por encima del nivel del bosque, sobre todo en lugares bien expuestos al viento de norte y oeste.

Tendencia para las próximas 48-72h

Para el jueves y el viernes aumentaría la actividad de aludes, por una mayor acumulación de nieve reciente húmeda en cotas altas y por la formación de placas de viento por viento del E y del S. Peligro EN AUMENTO.

El próximo boletín será emitido el día 2026-03-04

5 MUY FUERTE	4 FUERTE	3 NOTABLE	2 LIMITADO	1 DÉBIL

EAWS EUROPEAN AVALANCHE WARNING SERVICES