MINISTERO DELLA DIFESA

meteomont
Servizio Nazionale di previsione neve e valanghe

EAWS EUROPEAN AVALANCHE WARNING SERVICES

CARABINIERI

AERONAUTICA MILITARE SERVIZIO METEOROLOGICO

ALPI OROBICHE

Bollettino Valanghe N. 362/2026 del 03/03/2026 ore 14.00
Validità 48 ore prossima emissione 04/03/2026

A cura del Servizio METEOMONT dell'ARMA dei CARABINIERI
In collaborazione con Servizio Meteorologico dell'Aeronautica militare

SITUAZIONE alle 14:00 del 03/03/2026

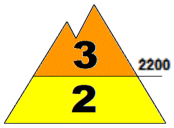

SITUAZIONE TIPO: passaggio da poca a molta neve.



SITUAZIONE TIPO: situazione primaverile.

Quota neve (mslm)	Nord	Sud
	1300 - 1600	1400 - 1800

Altezza Neve (cm)	Neve al suolo	Neve Fresca	Quota (mslm)
	130	000	2080
	051	0	1635

VALANGHE OSSERVATE: Nessuna valanga.

PREVISIONI 04/03/2026

GRADO DI PERICOLO: MARCATO 3

SITUAZIONE TIPO: passaggio da poca a molta neve.

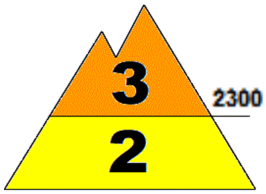



SITUAZIONE TIPO: situazione primaverile.

MANTO NEVOSO: La stabilità del manto nevoso è scarsa su alcuni punti (aree) per versanti da ovest a est al di sopra di 2300 mslm, possibili valanghe di dimensioni grandi.
La stabilità del manto nevoso è scarsa su alcuni punti (aree) per versanti da est a ovest al di sotto di 2300 mslm, possibili valanghe di dimensioni medie.

AVVERTENZE

Il rialzo termico diurno richiede un'attenta valutazione temporale dell'escursione che eviti l'attraversamento di pendii ripidi nelle ore più calde della giornata.

SCALA EUROPEA DEL GRADO DI PERICOLO VALANGHE

LEGENDA PROBLEMA

Bollettino realizzato su scala sinottica-regionale (standard EAWS). La sua valutazione non può escludere in alcun modo la necessità di una seria e capace valutazione locale del pericolo (singolo pendio) che può essere anche sensibilmente diverso. Le previsioni meteorologiche sono relative all'orario UTC (per l'Italia +1 in inverno e +2 in estate).

MINISTERO DELLA DIFESA

meteomont
Servizio Nazionale di previsione neve e valanghe

EAWS EUROPEAN AVALANCHE WARNING SERVICES

CARABINIERI

ALPI OROBICHE

PREVISIONE METEO

Quota		04/03/2026 h6:00	04/03/2026 h12:00	04/03/2026 h18:00
1000	Venti	02 Nodi da Nord	01 Nodi da S-Ovest	01 Nodi da Nord
	Temperature	-01 °C	+00 °C	+04 °C
	Temp.percepita	-1 °C	0 °C	4 °C
2000	Venti	01 Nodi da Nord	01 Nodi da Ovest	01 Nodi da Nord
	Temperature	+00 °C	+00 °C	+03 °C
	Temp.percepita	0 °C	0 °C	3 °C
3000	Venti	02 nodi da N-Ovest	02 Nodi da Nord	01 nodi da N-Ovest
	Temperature	-05 °C	-03 °C	-03 °C
	Temp.percepita	-5 °C	-3 °C	-3 °C
Zero termico		1400-1600 m.	1800-2000 m.	2400-2600 m.
Fenomeno		—	—	—
Stato del cielo				

LEGENDA FENOMENI

— Assenza Fenomeni · Nebbia · Foschia · Pioggia debole · Pioggia moderata · Pioggia forte · Temporali

Nevicata debole · Nevicata moderata · Nevicata forte

STATO DEL CIELO

Sereno · Poco nuvoloso · Nuvoloso · Molto nuvoloso · Coperto

Parametri meteonivometrici registrati presso i campi di rilevamento il 03/03/2026.

Località	Comune	Quota (m.s.l.m.)	Altezza neve (cm)	Neve caduta nelle 24 ore (cm)	Temp. Min (°C)	Temp. Max (°C)	Condizioni del tempo
VODALA	Gromo (BG)	1635	51	0	-1	+2	Assenza di precipitazioni
QUARTA BAITA	Foppolo (BG)	1760	62	6	-4	+2	Assenza di precipitazioni
CIMA BIANCA	Colere (BG)	2080	130	0	-3	+5	Assenza di precipitazioni
ALPE NEEL *	Ardesio (BG)	1650	65	0	N.P.	N.P.	Assenza di precipitazioni
PIZZO DI RODES *	Ponte in Valtellina (SO)	2800	130	4	N.P.	N.P.	Assenza di precipitazioni

(*) Rilievi fuori campo

L'INFORMAZIONE E' PREVENZIONE - LEGGI L'ATTUALE GRADO DI PERICOLO VALANGHE!

IL CAPO DEL CENTRO NAZIONALE METEOMONT
(Ten. Col. RFI Emanuela Gini)
FIRMA AUTOGRAFA OMESSA AI SENSI
DELL'ART.3 DEL D.LGS N.39/1993