MINISTERO DELLA DIFESA

meteomont Servizio Nazionale di previsione neve e valanghe

EAWS EUROPEAN AVALANCHE WARNING SERVICES

CARABINIERI

In collaborazione con: MARCHE

# APPENNINO UMBRO-MARCHIG. MERID. - MONTI SIBILLINI

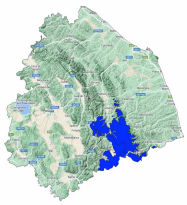

Bollettino Valanghe N. 315/2026 del 02/03/2026 ore 14.00
Validità 48 ore prossima emissione 03/03/2026

**A cura del Servizio METEOMONT dell'ARMA dei CARABINIERI**
**In collaborazione con Servizio Meteorologico dell'Aeronautica militare**

## SITUAZIONE alle 14:00 del 02/03/2026

**SITUAZIONE TIPO: situazione primaverile.**

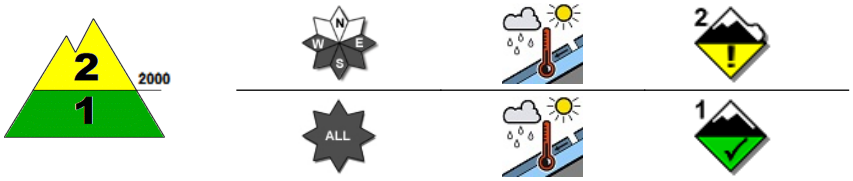


**SITUAZIONE TIPO: situazione primaverile.**

| Quota neve (mslm) | Nord | Sud |
|---|---|---|
| | 1600 | 1800 |

| Altezza Neve (cm) | Neve al suolo | Neve Fresca | Quota (mslm) |
|---|---|---|---|
| | 80-100 | 00 | 2000 |
| | 25 | 00 | 1700 |

**VALANGHE OSSERVATE: Valanghe di piccole dimensioni, Valanghe a lastroni di fondo.**

## PREVISIONI 03/03/2026

## GRADO DI PERICOLO: MODERATO 2

## SITUAZIONE TIPO: situazione primaverile.




## SITUAZIONE TIPO: pioggia su neve.

**MANTO NEVOSO: La stabilità del manto nevoso è discreta su molti punti (aree) per versanti da est a ovest al di sopra di 2000 mslm, possibili valanghe di dimensioni medie.**
**La stabilità del manto nevoso è discreta su pochi punti (aree) per tutte le esposizioni al di sotto di 2000 mslm, possibili valanghe di dimensioni medie.**

## AVVERTENZE

Il rialzo termico diurno richiede un'attenta valutazione temporale dell'escursione che eviti l'attraversamento di pendii ripidi nelle ore più calde della giornata.

## SCALA EUROPEA DEL GRADO DI PERICOLO VALANGHE

5 - MOLTO FORTE | 4 - FORTE | 3 - MARCATO | 2 - MODERATO | 1 - DEBOLE | NO NEVE | NO INFO

## LEGENDA PROBLEMA

NEVE FRESCA | LASTRONI DA VENTO | STRATI DEBOLI PERSISTENTI | NEVE BAGNATA | SLITTAMENTO | CORNICI | NESSUN PROBLEMA VALANGHIVO EVIDENTE | NO_INFO

**Bollettino realizzato su scala sinottica-regionale (standard EAWS). La sua valutazione non può escludere in alcun modo la necessità di una seria e capace valutazione locale del pericolo (singolo pendio) che può essere anche sensibilmente diverso. Le previsioni meteorologiche sono relative all'orario UTC (per l'Italia +1 in inverno e +2 in estate).**

MINISTERO DELLA DIFESA

meteomont
Servizio Nazionale di previsione neve e valanghe

EAWS EUROPEAN AVALANCHE WARNING SERVICES

CARABINIERI

In collaborazione con: MARCHE

# APPENNINO UMBRO-MARCHIG. MERID. - MONTI SIBILLINI

## PREVISIONE METEO

| Quota | | 03/03/2026 h6:00 | 03/03/2026 h12:00 | 03/03/2026 h18:00 |
|---|---|---|---|---|
| 1000 | Venti | 01 Nodi da S-Ovest | 01 Nodi da Est | 01 Nodi da S-Est |
| | Temperature | +04 °C | +05 °C | +04 °C |
| | Temp.percepita | 4 °C | 5 °C | 4 °C |
| 2000 | Venti | 03 Nodi da Ovest | 01 Nodi da Sud | 03 Nodi da S-Ovest |
| | Temperature | +02 °C | +01 °C | +02 °C |
| | Temp.percepita | 0 °C | 1 °C | 0 °C |
| 3000 | Venti | 08 nodi da Ovest | 08 Nodi da Ovest | 07 Nodi da Ovest |
| | Temperature | -06 °C | -05 °C | -04 °C |
| | Temp.percepita | -12 °C | -11 °C | -9 °C |
| Zero termico | | 2100-2300 m. | 2100-2300 m. | 2200-2400 m. |
| Fenomeno | | | | — |
| Stato del cielo | | | | |

## LEGENDA FENOMENI

— Assenza Fenomeni · Nebbia · Foschia · Pioggia debole · Pioggia moderata · Pioggia forte · Temporali

Nevicata debole · Nevicata moderata · Nevicata forte

## STATO DEL CIELO

Sereno · Poco nuvoloso · Nuvoloso · Molto nuvoloso · Coperto

## Parametri meteonivometrici registrati presso i campi di rilevamento il 02/03/2026.

| Località | Comune | Quota (m.s.l.m.) | Altezza neve (cm) | Neve caduta nelle 24 ore (cm) | Temp. Min (°C) | Temp. Max (°C) | Condizioni del tempo |
|---|---|---|---|---|---|---|---|
| FORCA DI GUALDO | Castelsantangelo sul Nera (MC) | 1496 | 25 | 0 | +1 | +10 | Assenza di precipitazioni |
| COLLE | Montegallo (AP) | 1036 | 0 | 0 | -1 | +11 | Assenza di precipitazioni |
| PARCO GUARNIERI | Montemonaco (AP) | 980 | 0 | 0 | +2 | +9 | Assenza di precipitazioni |
| RIFUGIO PERUGIA | Norcia (PG) | 1500 | 0 | 0 | N.P. | N.P. | Assenza di precipitazioni |
| BELVEDERE DI FRONTIGNANO * | Ussita (MC) | 1695 | 18 | 0 | N.P. | N.P. | Assenza di precipitazioni |

(*) Rilievi fuori campo

**L'INFORMAZIONE E' PREVENZIONE - LEGGI L'ATTUALE GRADO DI PERICOLO VALANGHE!**

**IL CAPO DEL CENTRO NAZIONALE METEOMONT**
**(Ten. Col. RFI Emanuela Gini)**
**FIRMA AUTOGRAFA OMESSA AI SENSI**
**DELL'ART.3 DEL D.LGS N.39/1993**

Bollettino realizzato su scala sinottica-regionale (standard EAWS). La sua valutazione non può escludere in alcun modo la necessità di una seria e capace valutazione locale del pericolo (singolo pendio) che può essere anche sensibilmente diverso. Le previsioni meteorologiche sono relative all'orario UTC (per l'Italia +1 in inverno e +2 in estate).