Bulletin d'estimation du risque d'avalanche

(valable en dehors des pistes balisées et ouvertes)

MASSIF : Cinto Rotondo

Rédigé le mardi 3 mars 2026 à 15h

Estimation des risques pour le : MERCREDI 04 MARS

CONDITIONS PRINTANIÈRES EN VERSANTS ENSOLEILLÉS; PERSISTANCE DE RARES STRUCTURES DE PLAQUES EN ALTITUDE EN VERSANTS OMBRAGÉS.

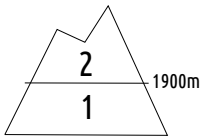

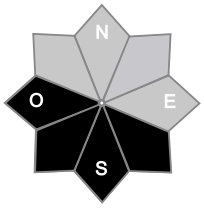

Au-dessus de 1900m indice de risque limité, plus bas indice faible.

Départs spontanés : Nombreux départs en neige humides dans les versants ensoleillés.

Déclenchements provoqués : Rares structures de plaques en Nord à Nord-Est au-delà de 2000 m difficiles à déclencher.

Indices de risque : 5 très fort - 4 fort - 3 marqué - 2 limité - 1 faible -- En noir : les pentes les plus dangereuses

Stabilité du manteau neigeux

Situation avalancheuse typique : neige humide

Départs spontanés : Après une nuit assez douce, l'humidification reprend rapidement en matinée. Elle devrait être accélérée en versants Sud et en versants occidentaux par la faible couverture nuageuse et un effet de Foehn radoucissant les températures. Quelques départs spontanés d'avalanches de taille petite à moyenne (taille 1 à 2) de neige humide restent possibles dans les pentes raides encore chargées et ensoleillées (parfois sablées) et vers les rochers/falaises. Une avalanche de fond de taille 2 (moyenne) sur les dalles rocheuses emportant la totalité du manteau neigeux en place reste possible.

Déclenchements provoqués : de rares plaques persistent dans les versants nord-ouest, nord et nord-est au-dessus de 2000/2200 mètres. Elles ont gagné en résistance mais elles reposent généralement sur des couches de neige sans cohésion (neige roulée). Souvent résistantes à de fortes surcharges, dans certaines secteurs bien ombragés et maintenus froids, un déclenchement est possible par surcharge répétée. Des glissements ponctuels en surface sur les pentes ensoleillées sous les skis ou les raquettes sont possibles.

Qualité de la neige

Qualification de l'enneigement : L'enneigement est excellent pour la saison au-dessus de 1600 m. Sur la Maniccia, à 2400 m d'altitude dans le massif du Rotondo, on mesure 2m80 de hauteur totale de neige.

Limite d'enneigement skiable : autour de 1500 m.

État de la neige : Le regel nocturne ne concerne que les très hauts sommets. L'humidification est fortement accélérée dès le milieu de matinée sur les pentes ensoleillées. La neige y devient rapidement lourde et humide. En Nord, l'humidification est plus lente, elle ne se produit qu'en dessous de 2000m, l'après-midi. Au-dessus de 2000/2200 m, la neige reste dure ou cartonnée.
À noter la présence de corniches parfois volumineuses.

Aperçu météo pour le mercredi 04 mars

nuit	matin	après-midi	soir

Quelques nuages en versants Est avec de rares averses, larges éclaircies à l'Ouest.

Pluie-Neige	2 100 m			
Iso 0 °C	2 600 m	2 500 m	2 500 m	2 700 m
Vent 1500 m	↙ 10 km/h	← 10 km/h	← 15 km/h	← 10 km/h
Vent 3000 m	↗ 10 km/h	↗ 10 km/h	↖ 10 km/h	↙ 5 km/h

Épaisseur de neige hors-piste

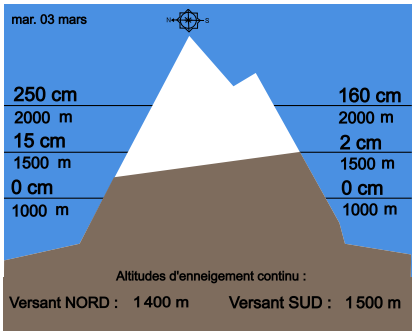

Précipitations à 1800 m

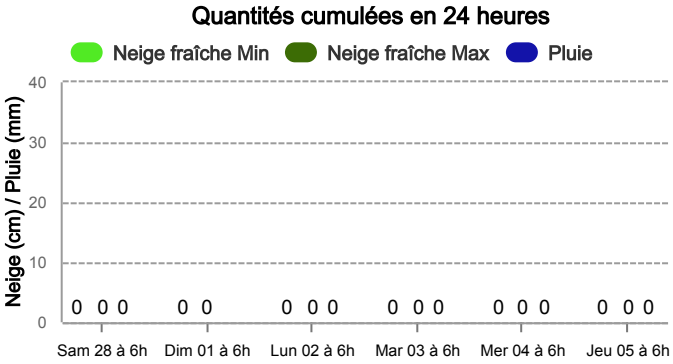

Tendance du jeudi 05 mars

Indice de risque limité

Persistance du risque d'avalanches de neige humide.

Pour consulter la vigilance en cours, veuillez vous rendre sur le site https://vigilance.meteofrance.fr/fr

Météo-France - 73 avenue de Paris, 94165 Saint-Mandé cedex - Contact : contact@meteo.fr

Rédigé par Météo-France avec la contribution des observateurs du réseau nivo-météorologiques. Partenariat : ANMSM (Maires de Stations de Montagne), DSF (Domaines Skiables de France), ADSP (Directeurs de Pistes et de la Sécurité des Stations de Sports d'Hiver) et autres acteurs de la montagne.

Bulletin neige & avalanches par téléphone au **0 892 68 10 20** Service 0,35 € / min + prix appel

RÉPUBLIQUE FRANÇAISE
Liberté Égalité Fraternité

METEO FRANCE
À VOS CÔTÉS, DANS UN CLIMAT QUI CHANGE

Bulletin d'estimation du risque d'avalanche

(valable en dehors des pistes balisées et ouvertes)

MASSIF : Cinto Rotondo

Rédigé le mardi 3 mars 2026 à 15h

Conditions nivo-météo des 7 derniers jours

	mer. 25/02				jeu. 26/02				ven. 27/02				sam. 28/02				dim. 01/03				lun. 02/03				mar. 03/03			
	03h	09h	15h	21h	03h	09h	15h	21h	03h	09h	15h	21h	03h	09h	15h	21h	03h	09h	15h	21h	03h	09h	15h	21h	03h	09h	15h	21h
Météo																												
Vent (km/h)	5	5	5	5	10	15	15	15	20	15	15	15	10	5	10	10	10	10	10	10	15	25	25	15	15	10	10	10
à 3000m																												
Vent (km/h)	5	5	10	5	5	5	5	5	10	10	10	5	5	5	10	5	5	5	10	5	10	15	20	10	10	15	20	15
à 1500m																												

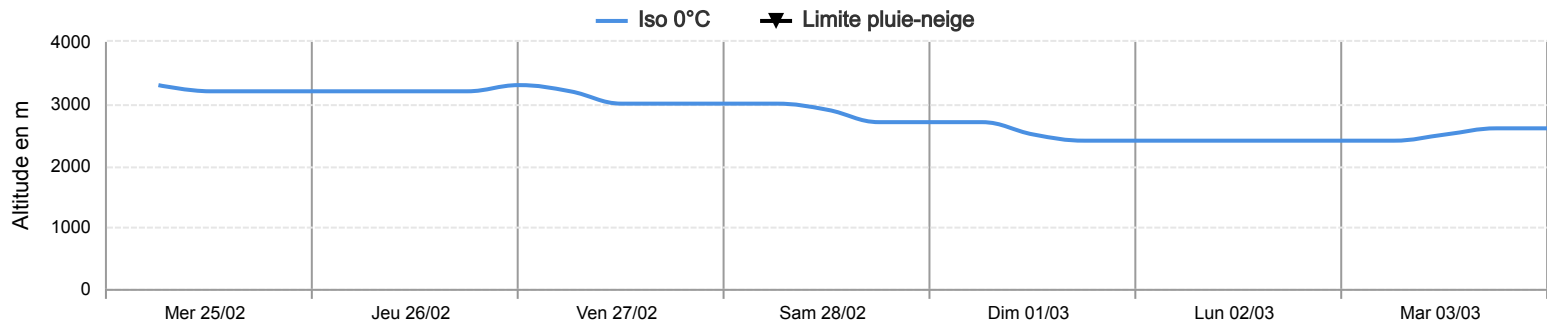

Neige fraîche à 06h

mer. 25/02	jeu. 26/02	ven. 27/02	sam. 28/02	dim. 01/03	lun. 02/03	mar. 03/03
0 cm	0 cm	0 cm	0 cm	0 cm	0 cm	

Risque d'avalanche	mer. 25/02	jeu. 26/02	ven. 27/02	sam. 28/02	dim. 01/03	lun. 02/03	mar. 03/03
	2	2	2	2	2	2	2

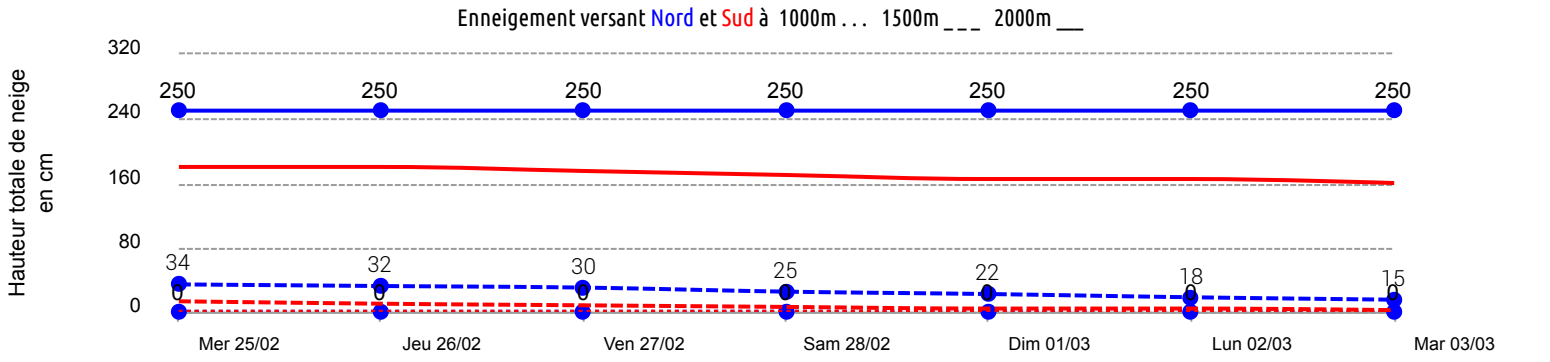

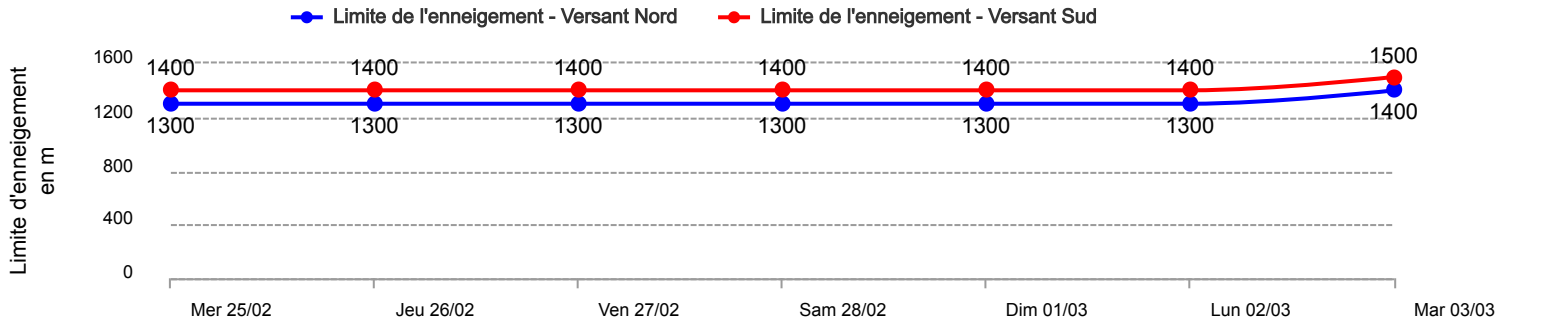

Pour consulter la vigilance en cours, veuillez vous rendre sur le site https://vigilance.meteofrance.fr/fr

Météo-France - 73 avenue de Paris, 94165 Saint-Mandé cedex - Contact : contact@meteo.fr

Rédigé par Météo-France avec la contribution des observateurs du réseau nivo-météorologiques. Partenariat : ANMSM (Maires de Stations de Montagne), DSF (Domaines Skiables de France), ADSP (Directeurs de Pistes et de la Sécurité des Stations de Sports d'Hiver) et autres acteurs de la montagne.

Bulletin neige & avalanches par téléphone au

0 892 68 10 20 Service 0,35 € / min + prix appel