Bulletin d'estimation du risque d'avalanche
(valable en dehors des pistes balisées et ouvertes)

MASSIF : Aravis

Rédigé le mardi 3 mars 2026 à 16h

Estimation des risques pour le : MERCREDI 04 MARS

MANTEAU NEIGEUX QUI SE RÉCHAUFFE AU FIL DE LA JOURNÉE.

2

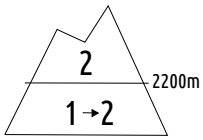

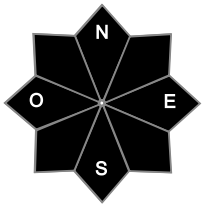

Au-dessus de 2200m indice de risque limité, plus bas indice faible évoluant en limité.

Départs spontanés : Départs humides et plaques de fond.

Déclenchements provoqués : Neige humide au fil du réchauffement diurne.

Indices de risque : 5 très fort - 4 fort - 3 marqué - 2 limité - 1 faible -- En noir : les pentes les plus dangereuses

Stabilité du manteau neigeux

Situation avalancheuse typique : neige humide avalanches de fond

Déclenchements provoqués :
* Au fil de l'ensoleillement, départs ponctuels sous les skis. Taille 1 à 2 (petite à moyenne).
* Au-dessus de 2200 m en versants E/N/O : rares plaques en présence d'une **couche fragile persistante enfouie.** Difficile à déclencher mais départ possible **en cascade**. La profondeur de l'enfouissement de la couche fragile varie énormément, même dans une même pente (abords de crêtes, près des rochers). Cette **couche fragile est rarement présente en Sud en altitude** et peut être sollicitée par un enfoncement important dans la neige humide. Une avalanche en plaque (même d'aspect humide en surface) avec une bonne propagation est possible. Taille 2, et rarement 3 en Sud (moyenne, rarement grande).

Départs spontanés :
* Avalanche de neige humide au fil du réchauffement. Très rare départ en plaque si humidification de la couche fragile persistante. Taille 1 à 2, rarement 3.
* En tous versant, principalement sous 2400 m : plaques de fond. Départs dans les pentes raides et lisses (pentes herbeuses, dalles rocheuses). Départs possibles à toute heure du jour ou de la nuit. Taille 2 (moyenne).
* Chutes de corniches, épaisses et volumineuses. Leurs chutes peuvent déclencher une plaque en contrebas.

Qualité de la neige

Enneigement : bon pour la période. On peut chausser les skis vers 1200/1300 m en versants E/N/O et 1400/1500 m en versants Sud. Les corniches sont volumineuses et menaçantes. Les arêtes et les crêtes sont érodées par le vent de SW à NW.

Qualité de la neige mercredi :
* Regel inégal, qui dépendra du voile de la fin de nuit.
* Conditions printanières tous versants (regel le matin et décaille avec le soleil). Enfoncement piéton important.
* En Nord dès 2000 m dans les secteurs préservés neige froide dure, vielle poudre. Croutée en dessous.

Aperçu météo pour le mercredi 04 mars

	nuit	matin	après-midi	soir

Journée printanière, températures douces.

Pluie-Neige				
Iso 0 °C	2 300 m	2 400 m	2 400 m	2 400 m
Vent 2000 m	↗ 5 km/h	↗ 5 km/h	↗ 5 km/h	↑ 5 km/h
Vent 2500 m	↗ 10 km/h	→ 10 km/h	↑ 10 km/h	↑ 15 km/h

Épaisseur de neige hors-piste

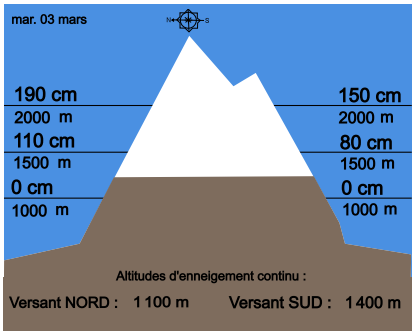

Précipitations à 1800 m

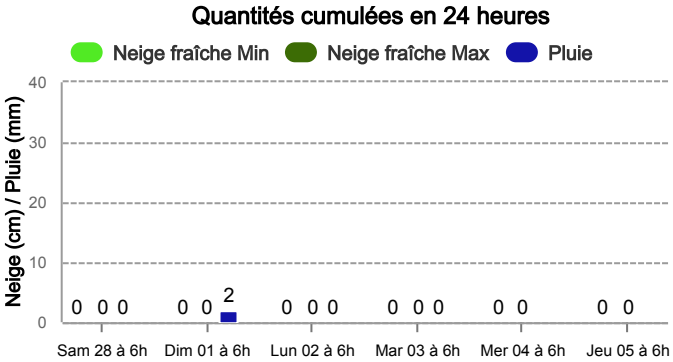

Tendance du jeudi 05 mars

2

Indice de risque limité

Risque stationnaire.

Pour consulter la vigilance en cours, veuillez vous rendre sur le site https://vigilance.meteofrance.fr/fr

Météo-France - 73 avenue de Paris, 94165 Saint-Mandé cedex - Contact : contact@meteo.fr

Rédigé par Météo-France avec la contribution des observateurs du réseau nivo-météorologiques. Partenariat : ANMSM (Maires de Stations de Montagne), DSF (Domaines Skiables de France), ADSP (Directeurs de Pistes et de la Sécurité des Stations de Sports d'Hiver) et autres acteurs de la montagne.

Bulletin neige & avalanches par téléphone au **0 892 68 10 20** Service 0,35 € / min + prix appel

RÉPUBLIQUE FRANÇAISE
Liberté Égalité Fraternité

METEO FRANCE
À VOS CÔTÉS, DANS UN CLIMAT QUI CHANGE

Bulletin d'estimation du risque d'avalanche
(valable en dehors des pistes balisées et ouvertes)

MASSIF : Aravis

Rédigé le mardi 3 mars 2026 à 16h

Conditions nivo-météo des 7 derniers jours

	mer. 25/02				jeu. 26/02				ven. 27/02				sam. 28/02				dim. 01/03				lun. 02/03				mar. 03/03			
	03h	09h	15h	21h	03h	09h	15h	21h	03h	09h	15h	21h	03h	09h	15h	21h	03h	09h	15h	21h	03h	09h	15h	21h	03h	09h	15h	21h
Météo																												
Vent (km/h)	15	15	20	20	10	10	15	15	15	15	15	25	30	35	20	15	20	20	20	25	25	25	25	15	15	10	10	10
à 2500m																												
Vent (km/h)	10	10	10	10	5	5	10	10	10	10	10	20	20	25	15	5	10	10	10	20	20	20	20	10	5	5	5	5
à 2000m																												

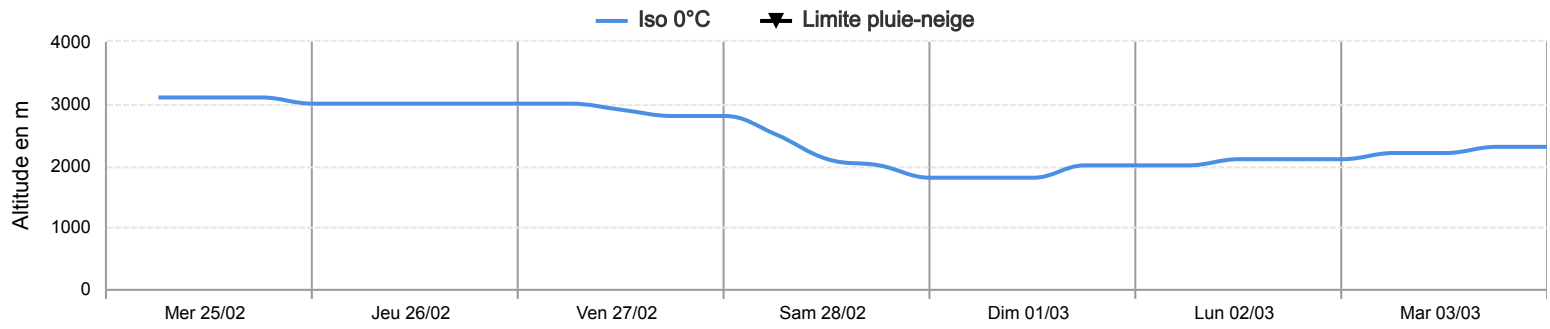

Neige fraîche à 06h

mer. 25/02	jeu. 26/02	ven. 27/02	sam. 28/02	dim. 01/03	lun. 02/03
0 cm	0 cm	0 cm	0 cm	0 cm	0 cm

Risque d'avalanche	mer. 25/02	jeu. 26/02	ven. 27/02	sam. 28/02	dim. 01/03	lun. 02/03	mar. 03/03
	3	3	3	2	2	2	2

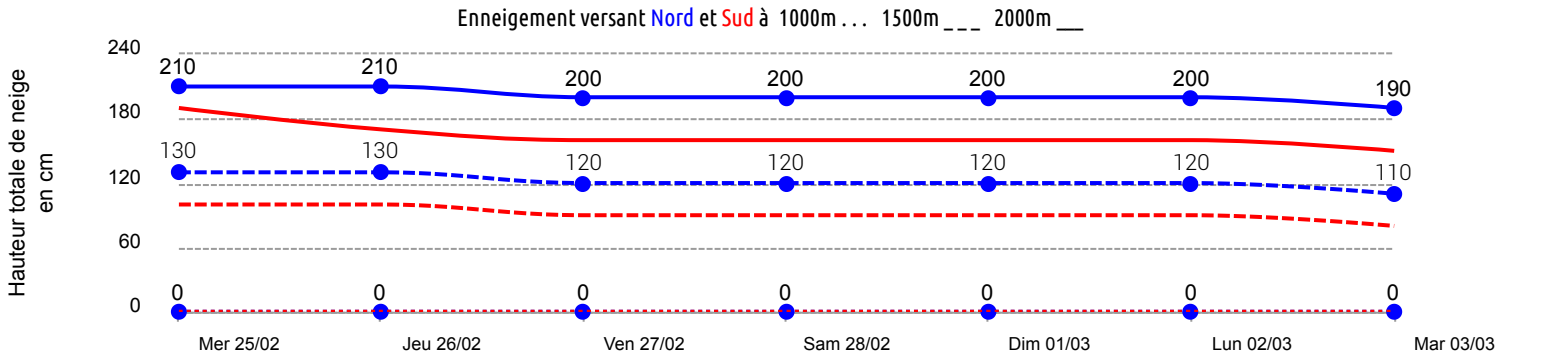

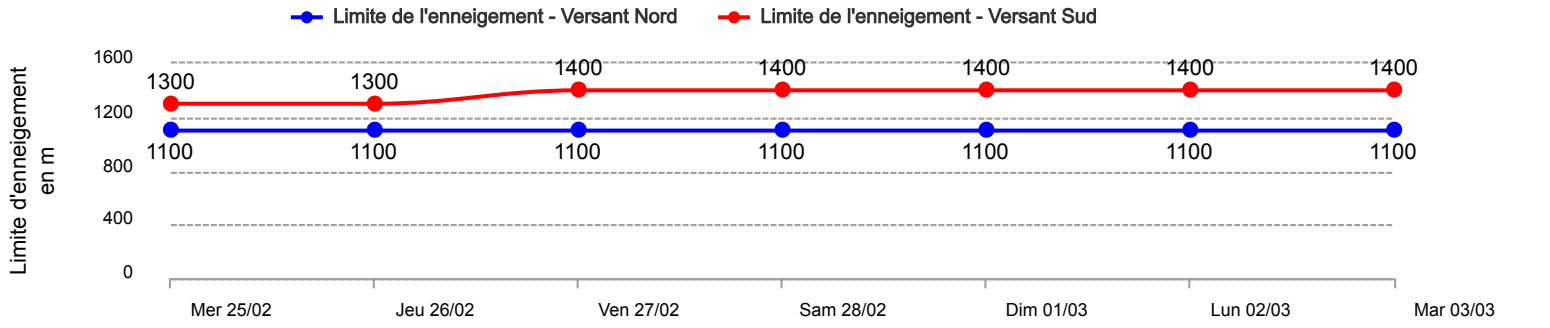

Pour consulter la vigilance en cours, veuillez vous rendre sur le site https://vigilance.meteofrance.fr/fr

Météo-France - 73 avenue de Paris, 94165 Saint-Mandé cedex - Contact : contact@meteo.fr

Rédigé par Météo-France avec la contribution des observateurs du réseau nivo-météorologiques. Partenariat : ANMSM (Maires de Stations de Montagne), DSF (Domaines Skiables de France), ADSP (Directeurs de Pistes et de la Sécurité des Stations de Sports d'Hiver) et autres acteurs de la montagne.

Bulletin neige & avalanches par téléphone au
0 892 68 10 20 Service 0,35 € / min + prix appel