Bulletin d'estimation du risque d'avalanche
(valable en dehors des pistes balisées et ouvertes)

MASSIF : Capcir Puymorens

Rédigé le mardi 3 mars 2026 à 16h

Estimation des risques pour le : MERCREDI 04 MARS

MANTEAU NEIGEUX PRINTANIER DANS LES VERSANTS AU SOLEIL ET QUELQUES STRUCTURES DE PLAQUES EN NORD D'ALTITUDE.

2

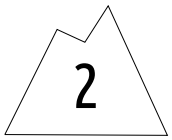

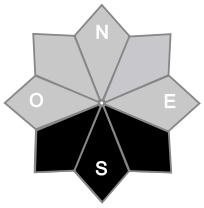

avalanches de fond

Indice de risque limité.

Départs spontanés : Avalanches de fond, rarement grandes, surtout au soleil

Déclenchements provoqués : Structures de plaques encore présentes

Indices de risque : 5 très fort - 4 fort - 3 marqué - 2 limité - 1 faible -- En noir : les pentes les plus dangereuses

Stabilité du manteau neigeux

Situation avalancheuse typique :

avalanches de fond

couche fragile persistante

Départs spontanés :
De rares, mais parfois épaisses avalanches de fond peuvent se produire en mobilisant des quantités conséquentes de neige lourde. Il est fait état, dans de nombreuses orientations et plutôt sous 2200 m, de larges fissures visibles (gueules de baleine) dans des pentes au sol souvent lisse, signes avant-coureurs de telles avalanches. Le départ de ces avalanches de fond est plus fréquent de l'après-midi à la soirée mais peut aussi se produire à d'autres moments de la journée. Les petites pluies jusqu'à 2200m d'altitude peuvent être un phénomène déclencheur.

Déclenchements provoqués :
Quelques avalanches de plaques sont encore déclenchables au passage d'un skieur, au-dessus de 2200/2400 m dans les secteurs restés en neige froide, donc plutôt orientés nord. Ces plaques sont soit assez fines (10/20 cm) et facilement déclenchables mais peu dangereuses ou plus épaisses et plus dure en altitude mais elles deviennent alors de plus en plus difficilement déclenchables. Dans certaines conditions, en bordure de couloir raide et froid, une plaque de neige dure peut rompre avec propagation.
Observables : neige travaillée par le vent en surface, corniche surplombant la pente.

Autre: Risque de glissade/dévissage en raison de la présence de neige parfois très dure voire de glace vive notamment sur les crêtes pelées par le vent.

Qualité de la neige

Enneigement :
L'enneigement est encore légèrement excédentaire dès la moyenne montagne après les nombreuses perturbations neigeuses depuis le début de l'année. Les vallons ombragés sont encore bien enneigés avec des quantités de neige importantes dès 1400 m notamment en versant Est et nord.
La limite skiable remonte autour de 1500 à 1600m plein Sud alors que certaines vallées ombragées sont encore enneigées dès 1200 à 1300m. A haute altitude, les pentes Ouest ont souvent été rabotées par le vent.

Qualité de la neige :
Mercredi matin, regel nocturne moyen après une nuit douce et voilée. En journée, reprise de l'humidification au soleil puis sous les nuages avec une neige devenant lourde et humide jusqu'à 2200/2400m en tous versants.
En altitude, à partir de 2200/2400 m, rarement plus bas, on trouvera encore de la neige restée sèche en poudre plus ou moins dense dans les pentes abritées du vent. Par contre, les crêtes et sommets sont souvent pelés ou en neige dure, parfois en glace, en versants Ouest principalement.

Aperçu météo pour le mercredi 04 mars

	nuit	matin	après-midi	soir
Doux, voilé, quelques ondées chargées de sable.				
Pluie-Neige	1 900 m			
Iso 0 °C	2 400 m	2 600 m	2 700 m	2 700 m
Vent 2000 m	↑ 15 km/h	↖ 15 km/h	↖ 25 km/h	↑ 20 km/h
Vent 3000 m	↑ 25 km/h	↖ 20 km/h	↑ 35 km/h	↑ 30 km/h

Épaisseur de neige hors-piste

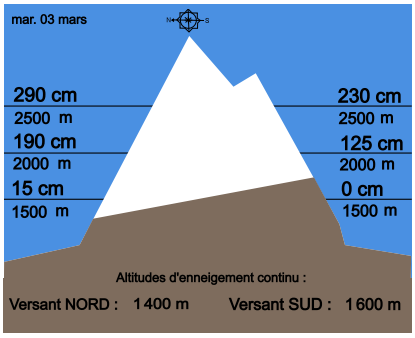

Précipitations à 1800 m

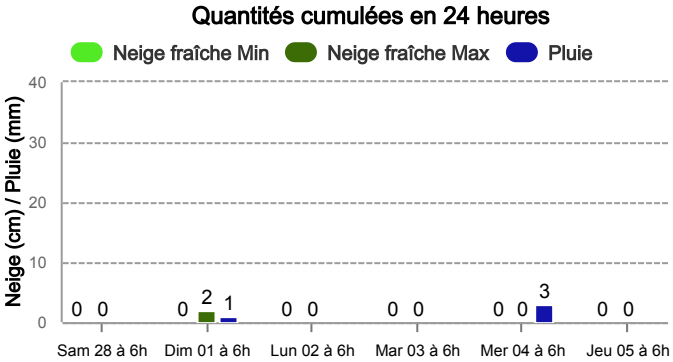

Tendance du jeudi 05 mars

Indice de risque limité

Maintient d'un risque faible à limité.

Pour consulter la vigilance en cours, veuillez vous rendre sur le site https://vigilance.meteofrance.fr/fr

Météo-France - 73 avenue de Paris, 94165 Saint-Mandé cedex - Contact : contact@meteo.fr

Rédigé par Météo-France avec la contribution des observateurs du réseau nivo-météorologiques. Partenariat : ANMSM (Maires de Stations de Montagne), DSF (Domaines Skiables de France), ADSP (Directeurs de Pistes et de la Sécurité des Stations de Sports d'Hiver) et autres acteurs de la montagne.

Bulletin neige & avalanches par téléphone au
0 892 68 10 20 Service 0,35 € / min + prix appel

RÉPUBLIQUE FRANÇAISE
Liberté Égalité Fraternité

METEO FRANCE
À VOS CÔTÉS, DANS UN CLIMAT QUI CHANGE

Bulletin d'estimation du risque d'avalanche

(valable en dehors des pistes balisées et ouvertes)

MASSIF : Capcir Puymorens

Rédigé le mardi 3 mars 2026 à 16h

Conditions nivo-météo des 7 derniers jours

	mer. 25/02				jeu. 26/02				ven. 27/02				sam. 28/02				dim. 01/03				lun. 02/03				mar. 03/03			
	03h	09h	15h	21h	03h	09h	15h	21h	03h	09h	15h	21h	03h	09h	15h	21h	03h	09h	15h	21h	03h	09h	15h	21h	03h	09h	15h	21h
Météo																												
Vent (km/h)	20	25	25	20	20	15	15	15	20	20	25	30	20	20	20	20	20	20	25	20	30	45	45	35	35	25	20	15
à 3000m																												
Vent (km/h)	15	15	15	10	10	10	10	10	15	15	15	20	10	10	15	10	10	15	20	15	20	30	35	25	25	20	20	10
à 2000m																												

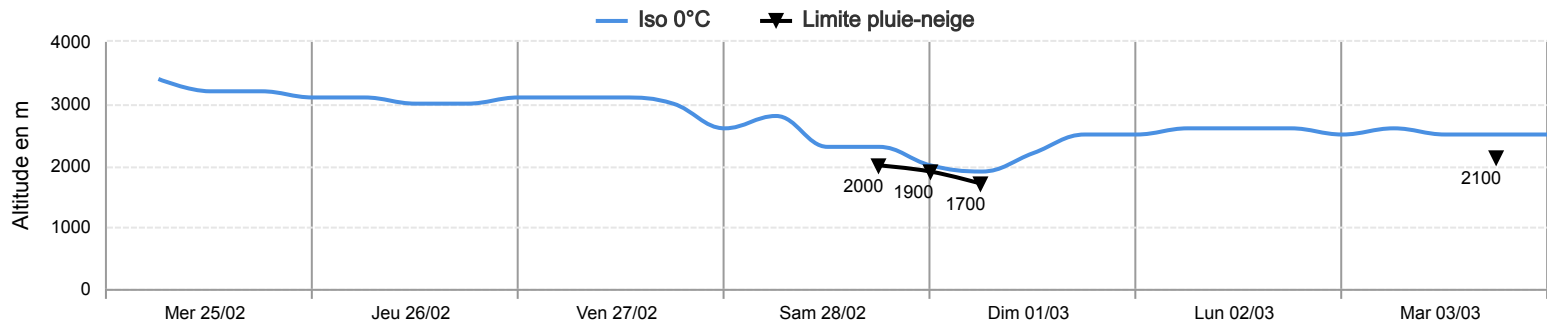

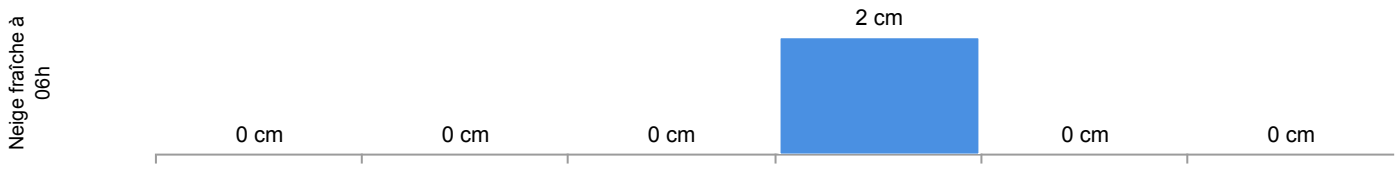

Risque d'avalanche	mer. 25/02	jeu. 26/02	ven. 27/02	sam. 28/02	dim. 01/03	lun. 02/03	mar. 03/03
	2	2	2	2	2	2	2

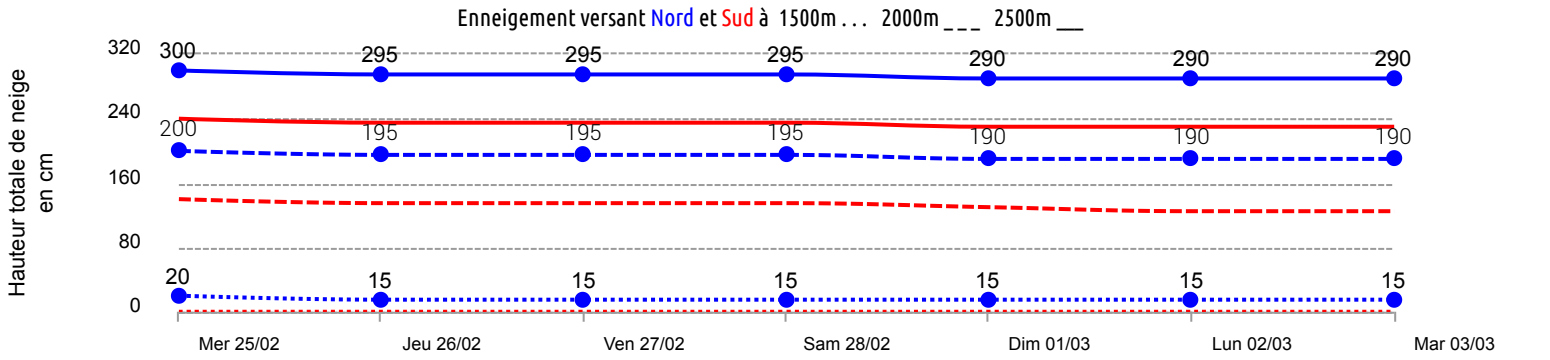

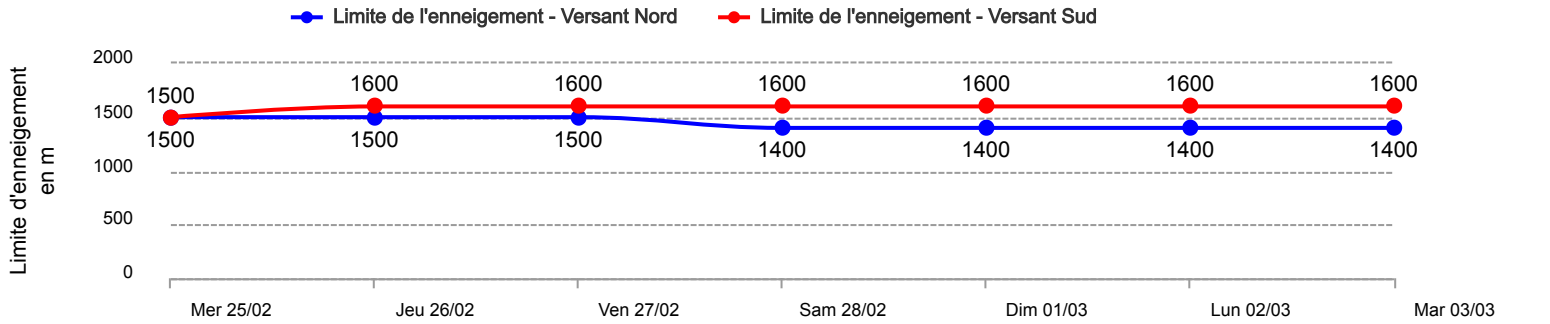

Pour consulter la vigilance en cours, veuillez vous rendre sur le site https://vigilance.meteofrance.fr/fr

Météo-France - 73 avenue de Paris, 94165 Saint-Mandé cedex - Contact : contact@meteo.fr

Rédigé par Météo-France avec la contribution des observateurs du réseau nivo-météorologiques. Partenariat : ANMSM (Maires de Stations de Montagne), DSF (Domaines Skiables de France), ADSP (Directeurs de Pistes et de la Sécurité des Stations de Sports d'Hiver) et autres acteurs de la montagne.

Bulletin neige & avalanches par téléphone au

0 892 68 10 20 Service 0,35 € / min + prix appel