Bulletin d'estimation du risque d'avalanche
(valable en dehors des pistes balisées et ouvertes)

MASSIF : Devoluy

Rédigé le mardi 3 mars 2026 à 16h

Estimation des risques pour le : MERCREDI 04 MARS

RARES PLAQUES EN ALTITUDE, DIFFICILES À SOLLICITER - FAIBLE ACTIVITÉ EN NEIGE HUMIDE

2

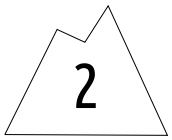

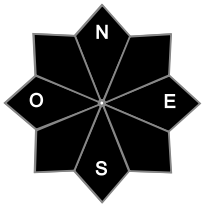

Indice de risque limité.

Départs spontanés : éventuels départs en neige humide en journée ou avalanches de fond

Déclenchements provoqués : rares avalanches de plaque difficiles à déclencher en altitude, mais pouvant engendrer d'épaisses cassures

Indices de risque : 5 très fort - 4 fort - 3 marqué - 2 limité - 1 faible -- En noir : les pentes les plus dangereuses

Stabilité du manteau neigeux

Situation avalancheuse typique : neige humide

Déclenchements provoqués :
- rares plaques difficiles à solliciter. Déclenchement non exclu dans les endroits moins enneigés ou les abords de croupes et bords des couloirs. Avalanche de grande taille, cassure épaisse et large.
- un skieur évoluant dans une pente raide ayant trop réchauffé peut aussi favoriser un départ ponctuel en neige humide.

Départs spontanés :
- éventuelles avalanches de neige humide dans les pentes ensoleillées, parfois jusqu'au sol en neige pourrie l'après-midi. Taille petite à moyenne. Même si dans ces versants la neige présente un aspect printanier, l'humidification augmente par rapport à ces derniers jours. Le regel peut être aussi plus aléatoire en lien avec l'incertitude sur la couverture nuageuse nocturne.
- une avalanche de fond ou une reptation emportant la totalité du manteau neigeux en place jusqu'au sol peut céder spontanément à n'importe quel moment du jour ou de la nuit sur terrain favorable (pentes herbeuses, dalles rocheuses). Avalanche de taille moyenne.

Qualité de la neige

L'enneigement est excédentaire. Les limites d'enneigement remontent dans les pentes bien exposées au soleil.

Limite d'enneigement skiable : 1200/1300 m en ubacs, 1500/1700 m en adrets pas trop raides.

État de la neige de surface : croute plus ou moins portante le matin avec le regel plus aléatoire et une humidification plus rapide au soleil en journée. En versants nord-est à nord-ouest au-dessus de 2100/2200 m, vieille poudreuse encore meuble, plus travaillée par le vent proche des crêtes.

Aperçu météo pour le mercredi 04 mars

	nuit	matin	après-midi	soir

Ciel plus ou moins "laiteux" avec la présence de poussières désertiques en suspension dans l'atmosphère.

Pluie-Neige				
Iso 0 °C	2 400 m	2 400 m	2 400 m	2 500 m
Vent 2000 m	5 km/h	5 km/h	10 km/h	10 km/h
Vent 3000 m	5 km/h	0 km/h	5 km/h	15 km/h

Épaisseur de neige hors-piste

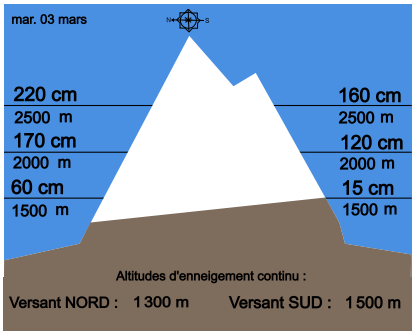

Précipitations à 1800 m

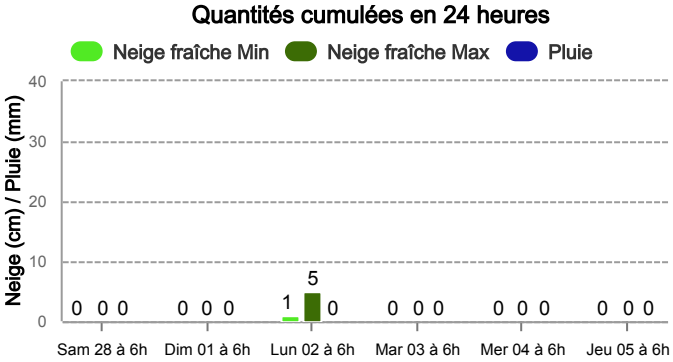

Tendance du jeudi 05 mars

2

Indice de risque limité

Risque limité. Encore de rares plaques difficiles à déclencher en altitude. Activité en neige humide limitée en journée.

Pour consulter la vigilance en cours, veuillez vous rendre sur le site https://vigilance.meteofrance.fr/fr

Météo-France - 73 avenue de Paris, 94165 Saint-Mandé cedex - Contact : contact@meteo.fr

Rédigé par Météo-France avec la contribution des observateurs du réseau nivo-météorologiques. Partenariat : ANMSM (Maires de Stations de Montagne), DSF (Domaines Skiables de France), ADSP (Directeurs de Pistes et de la Sécurité des Stations de Sports d'Hiver) et autres acteurs de la montagne.

Bulletin neige & avalanches par téléphone au 0 892 68 10 20 Service 0,35 € / min + prix appel

RÉPUBLIQUE FRANÇAISE
Liberté Égalité Fraternité

METEO FRANCE
À VOS CÔTÉS, DANS UN CLIMAT QUI CHANGE

Bulletin d'estimation du risque d'avalanche
(valable en dehors des pistes balisées et ouvertes)

MASSIF : Devoluy

Rédigé le mardi 3 mars 2026 à 16h

Conditions nivo-météo des 7 derniers jours

	mer. 25/02				jeu. 26/02				ven. 27/02				sam. 28/02				dim. 01/03				lun. 02/03				mar. 03/03			
	03h	09h	15h	21h	03h	09h	15h	21h	03h	09h	15h	21h	03h	09h	15h	21h	03h	09h	15h	21h	03h	09h	15h	21h	03h	09h	15h	21h
Météo																												
Vent (km/h)	10	10	15	20	15	10	10	10	10	10	15	20	30	30	25	20	15	20	25	20	20	30	30	25	20	10	10	5
à 3000m																												
Vent (km/h)	10	15	20	15	5	5	5	5	5	0	5	10	15	15	15	10	10	10	20	15	15	25	25	20	15	10	10	5
à 2000m																												

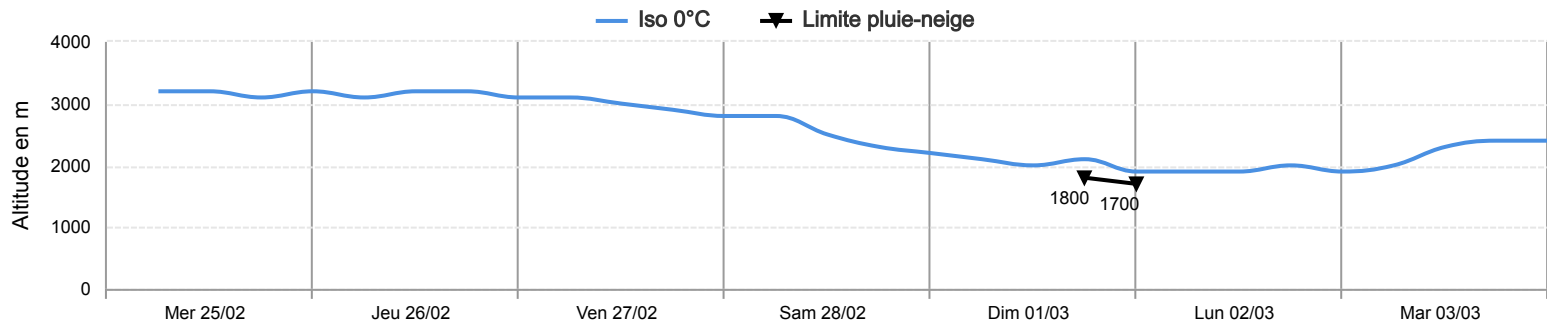

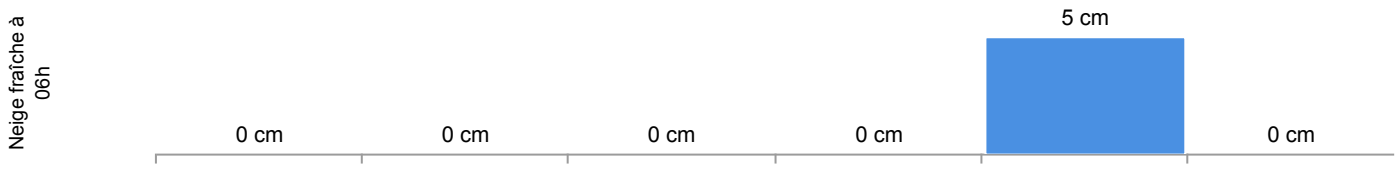

Risque d'avalanche	mer. 25/02	jeu. 26/02	ven. 27/02	sam. 28/02	dim. 01/03	lun. 02/03	mar. 03/03
	3	3	2	2	2	2	2

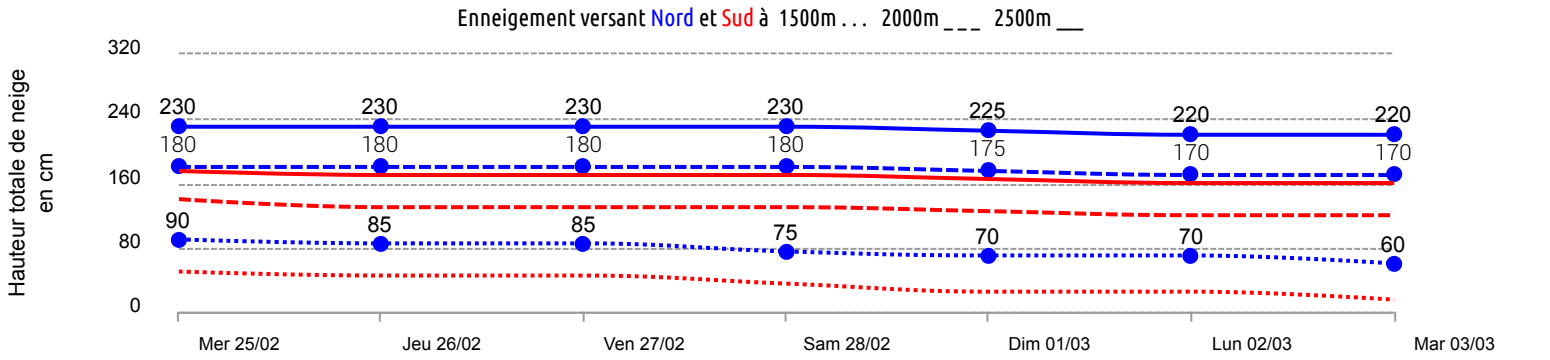

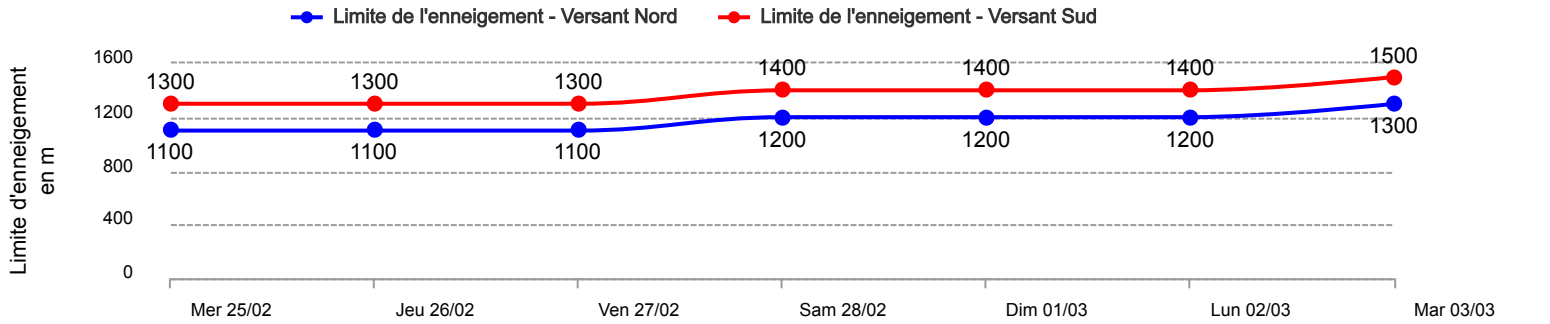

Pour consulter la vigilance en cours, veuillez vous rendre sur le site https://vigilance.meteofrance.fr/fr

Météo-France - 73 avenue de Paris, 94165 Saint-Mandé cedex - Contact : contact@meteo.fr

Rédigé par Météo-France avec la contribution des observateurs du réseau nivo-météorologiques. Partenariat : ANMSM (Maires de Stations de Montagne), DSF (Domaines Skiables de France), ADSP (Directeurs de Pistes et de la Sécurité des Stations de Sports d'Hiver) et autres acteurs de la montagne.

Bulletin neige & avalanches par téléphone au
0 892 68 10 20 Service 0,35 € / min + prix appel