Bulletin d'estimation du risque d'avalanche
(valable en dehors des pistes balisées et ouvertes)

MASSIF : Grandes-Rousses

Rédigé le mardi 3 mars 2026 à 16h

Estimation des risques pour le : MERCREDI 04 MARS

QUELQUES INSTABILITES DIFFICILES A DECLENCHER EN NORD D'ALTITUDE, ACTIVITE HUMIDE AU SOLEIL

2

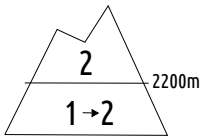

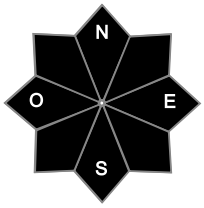

Au-dessus de 2200m indice de risque limité, plus bas indice faible évoluant en limité.

Départs spontanés : Avalanches de neige humide et plaques de fond.

Déclenchements provoqués : Très rares plaques en versant froid de haute altutde

Indices de risque : 5 très fort - 4 fort - 3 marqué - 2 limité - 1 faible -- En noir : les pentes les plus dangereuses

Stabilité du manteau neigeux

Situation avalancheuse typique : avalanches de fond couche fragile persistante

Sous l'effet de plus d'une semaine de soleil et de douceur, le manteau neigeux s'est considérablement tassé et il est bien consolidé en dessous de 2200/2400 m selon les versants. A plus haute altitude, il reste de rares instabilités en neige froide.

Départs spontanés : A toute heure de la journée ou de la nuit et principalement en large secteur Sud, possible avalanche de fond en pente raide herbeuse ou sur les dalles rocheuses, de tailles moyennes. Avalanches parfois précédées par l'ouverture d'une fissure / gueule de baleine. Aux heures chaudes et toujours en large Sud, le manteau neigeux s'humidifie parfois profondément et des coulées humides, parfois de tailles moyennes, peuvent partir spontanément près des rochers.

Déclenchements provoqués : Dans les versants ombragés de haute montagne, on ne peut pas exclure la possibilité de déclencher une plaque de neige compactée par le vent qui reposerait sur une couche fragile insuffisamment enfouie, par exemple en bordure de zone d'accumulation ou à proximité des rochers. Le risque est de plus en plus faible, mais en cas d'avalanche la cassure peut facilement dépasser un mètre. Sous 2000/2200m, les couches fragiles semblent isolées par la présence d'une croûte au sein du manteau neigeux lié à un épisode de pluie de mi février. Au soleil en neige pourrie, possibilité de faire partir une coulée humide sous les skis.

Qualité de la neige

Qualification de l'enneigement : L'enneigement régresse en partie basse, mais il est toujours bon pour la saison dès 1300 m, voire très bon au dessus de 1500 m environ, notamment dans les combes d'altitude. On trouve des crêtes un peu dégarnies par le vent, ou au contraire des corniches assez conséquentes.

Limites skiables : vers 1300/1600 m.

Qualité de la neige mercredi : En large Sud (Ouest et Est inclus), manteau de type printanier, avec une neige croûtée par le regel nocturne, s'humidifiant en journée, parfois profondément selon l'orientation. En versants ombragés, neige restée froide, quelquefois en vieille poudre, mais plus souvent compactée par le vent.

Aperçu météo pour le mercredi 04 mars

nuit	matin	après-midi	soir

Grande douceur sous un ciel voilé. Présence de sable Saharien dans l'air, rendant l'atmosphère moins limpide.

Pluie-Neige				
Iso 0 °C	2 300 m	2 400 m	2 400 m	2 500 m
Vent 2000 m	↑ 5 km/h	↑ 5 km/h	↑ 5 km/h	← 10 km/h
Vent 3000 m	↑ 10 km/h	↑ 10 km/h	↑ 10 km/h	↑ 10 km/h

Épaisseur de neige hors-piste

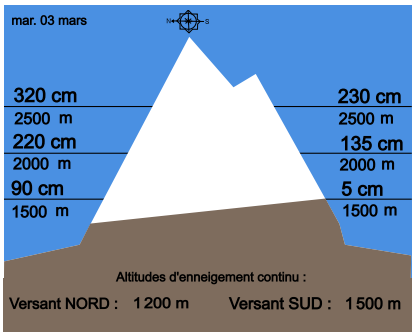

Précipitations à 1800 m

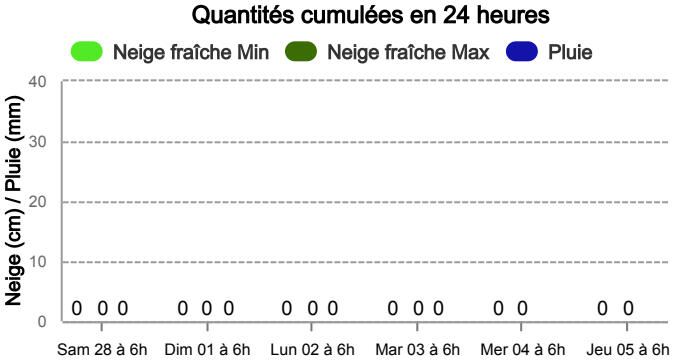

Tendance du jeudi 05 mars

2

Indice de risque limité

Peu d'évolution, risque restant limité jeudi, dans une ambiance toujours printanière.

Pour consulter la vigilance en cours, veuillez vous rendre sur le site https://vigilance.meteofrance.fr/fr

Météo-France - 73 avenue de Paris, 94165 Saint-Mandé cedex - Contact : contact@meteo.fr

Rédigé par Météo-France avec la contribution des observateurs du réseau nivo-météorologiques. Partenariat : ANMSM (Maires de Stations de Montagne), DSF (Domaines Skiables de France), ADSP (Directeurs de Pistes et de la Sécurité des Stations de Sports d'Hiver) et autres acteurs de la montagne.

Bulletin neige & avalanches par téléphone au
0 892 68 10 20 Service 0,35 € / min + prix appel

RÉPUBLIQUE FRANÇAISE
Liberté Égalité Fraternité

METEO FRANCE
À VOS CÔTÉS, DANS UN CLIMAT QUI CHANGE

Bulletin d'estimation du risque d'avalanche

(valable en dehors des pistes balisées et ouvertes)

MASSIF : Grandes-Rousses

Rédigé le mardi 3 mars 2026 à 16h

Conditions nivo-météo des 7 derniers jours

	mer. 25/02				jeu. 26/02				ven. 27/02				sam. 28/02				dim. 01/03				lun. 02/03				mar. 03/03			
	03h	09h	15h	21h	03h	09h	15h	21h	03h	09h	15h	21h	03h	09h	15h	21h	03h	09h	15h	21h	03h	09h	15h	21h	03h	09h	15h	21h
Météo																												
Vent (km/h)	10	10	15	15	10	5	10	10	10	10	20	25	15	15	25	30	30	30	30	35	40	40	35	30	15	10	10	10
à 3000m																												
Vent (km/h)	5	5	10	5	0	0	0	0	0	0	0	5	10	10	20	20	20	20	20	30	35	35	25	25	10	5	5	5
à 2000m																												

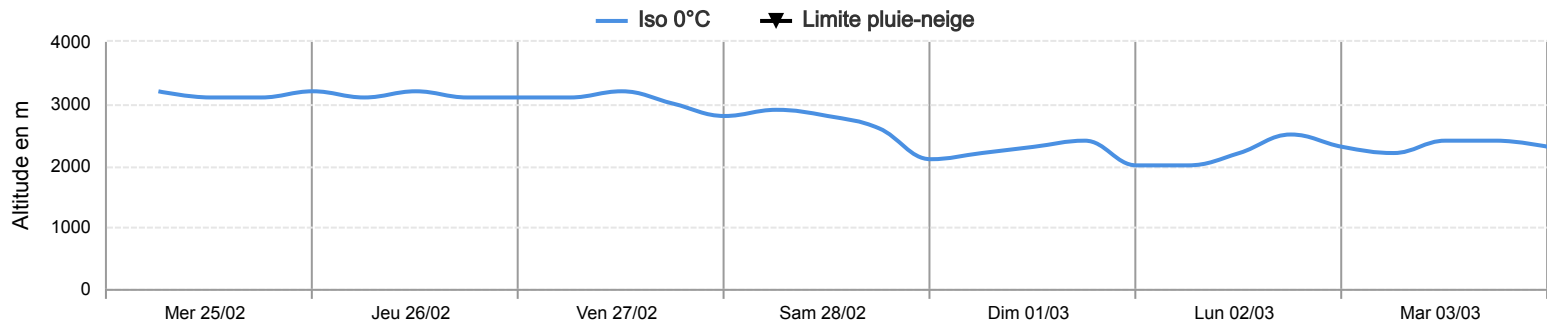

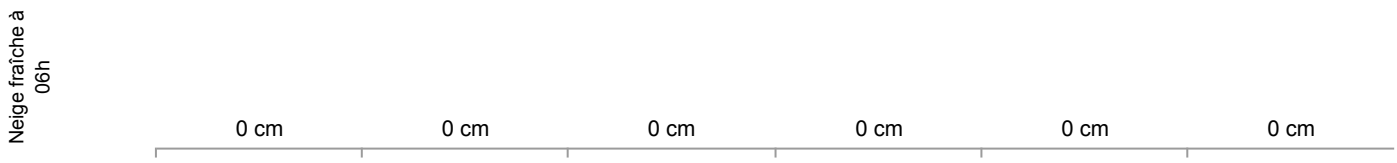

Risque d'avalanche	mer. 25/02	jeu. 26/02	ven. 27/02	sam. 28/02	dim. 01/03	lun. 02/03	mar. 03/03
	3	3	2	2	2	2	2

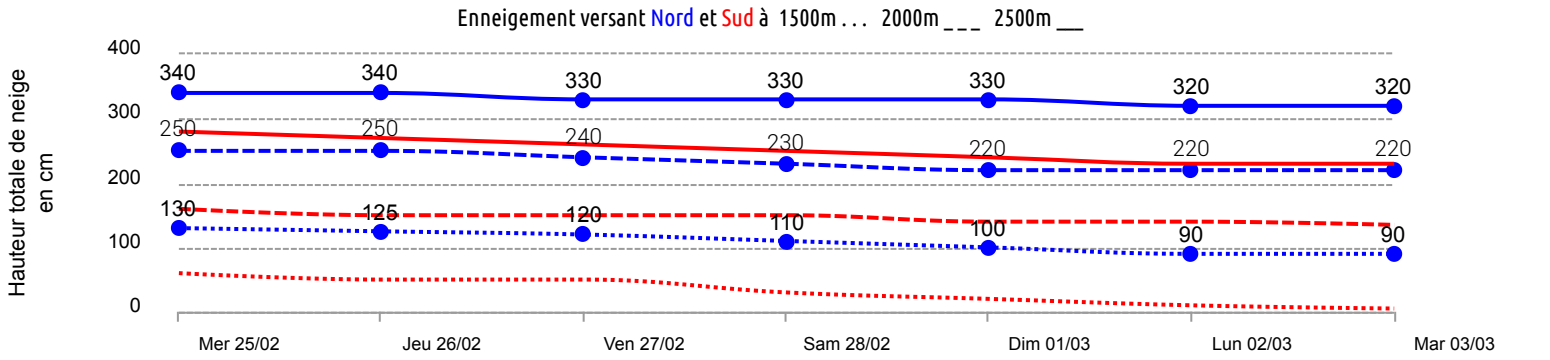

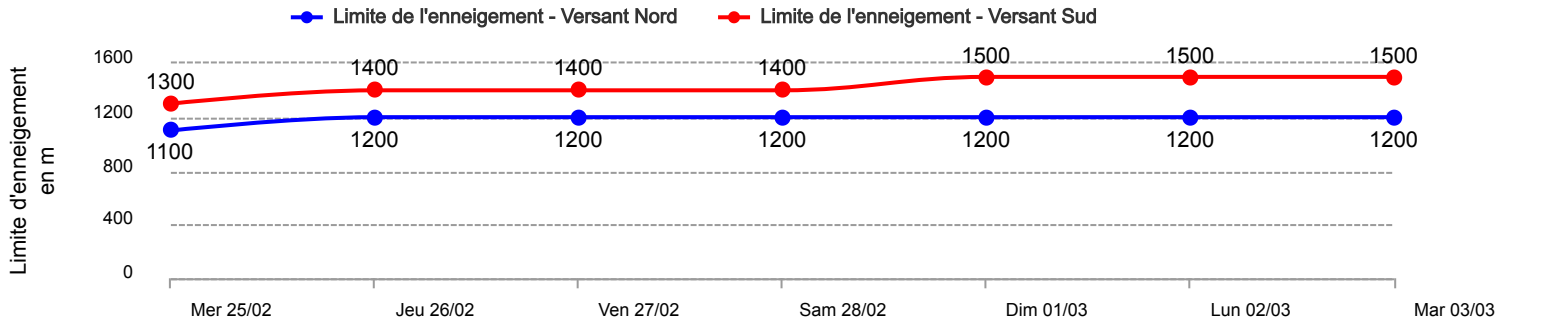

Pour consulter la vigilance en cours, veuillez vous rendre sur le site https://vigilance.meteofrance.fr/fr

Météo-France - 73 avenue de Paris, 94165 Saint-Mandé cedex - Contact : contact@meteo.fr

Rédigé par Météo-France avec la contribution des observateurs du réseau nivo-météorologiques. Partenariat : ANMSM (Maires de Stations de Montagne), DSF (Domaines Skiables de France), ADSP (Directeurs de Pistes et de la Sécurité des Stations de Sports d'Hiver) et autres acteurs de la montagne.

Bulletin neige & avalanches par téléphone au
0 892 68 10 20 Service 0,35 € / min + prix appel