RÉPUBLIQUE FRANÇAISE
Liberté Égalité Fraternité

METEO FRANCE
À VOS CÔTÉS, DANS UN CLIMAT QUI CHANGE

Bulletin d'estimation du risque d'avalanche
(valable en dehors des pistes balisées et ouvertes)
MASSIF : Pays-Basque

Rédigé le mardi 3 mars 2026 à 16h

Estimation des risques pour le : MERCREDI 04 MARS

MANTEAU HUMIDE.

2

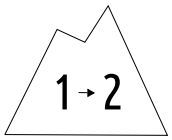

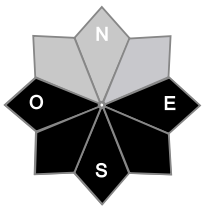

Indice de risque faible évoluant en limité.

Départs spontanés : Quelques avalanches de fond ou de surface.

Déclenchements provoqués : Peu probable.

Indices de risque : 5 très fort - 4 fort - 3 marqué - 2 limité - 1 faible -- En noir : les pentes les plus dangereuses

Stabilité du manteau neigeux

Situation avalancheuse typique : avalanches de fond

Départs spontanés : Des avalanches de fond plus probables avec le redoux persistant, surtout en journée, possibles en toutes orientations même si plus fréquentes en versants ensoleillés. Avalanches de tailles 1 à 2 (moyenne), une rare plus grande reste malgré tout envisageable partant d'une pente chargée.

Déclenchements provoqués : Les structures de plaques ont probablement toutes été détruites par le redoux, mais le passage d'un skieur peut favoriser un départ ponctuel de petite taille dans la neige très humide.

Qualité de la neige

Enneigement : faible enneigement sous 1500 m, l'enneigement est parfois bon au-dessus de 1800 m mais bien irrégulièrement réparti, crêtes dégarnies en particulier les versants ouest, combes plus chargées, et corniches parfois imposantes.
Limites skiables : à partir de 1600/1700 m en versants froids.
État de la neige : Neige humidifiée, regelée au matin, s'humidifiant en journée, profondément aux altitudes basses mais restant souvent portante en dehors des expositions raides plein sud

Aperçu météo pour le mercredi 04 mars

	nuit	matin	après-midi	soir

Ciel couvert à voilé, devenant bien couvert en soirée avec de rares averses. Vent faible à modéré de sud-est.

Pluie-Neige			2 200 m	2 200 m
Iso 0 °C	2 500 m	2 500 m	2 600 m	2 500 m
Vent 1000 m	↑ 15 km/h	↑ 15 km/h	↖ 15 km/h	↑ 10 km/h
Vent 2000 m	↑ 25 km/h	↑ 25 km/h	↑ 25 km/h	↑ 25 km/h

Épaisseur de neige hors-piste

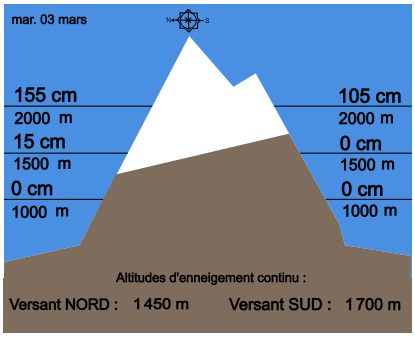

Précipitations à 1800 m

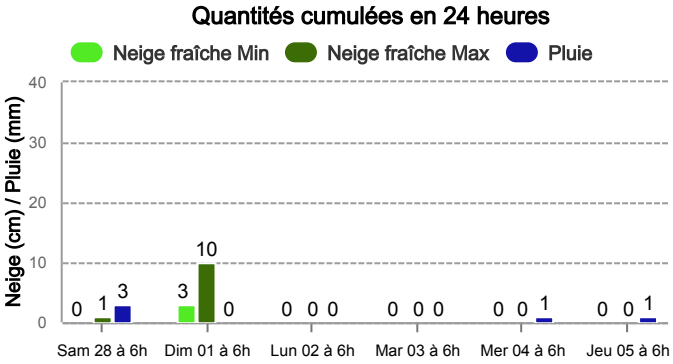

Tendance du jeudi 05 mars

1

Indice de risque faible

Risque inchangés.

Pour consulter la vigilance en cours, veuillez vous rendre sur le site https://vigilance.meteofrance.fr/fr

Météo-France - 73 avenue de Paris, 94165 Saint-Mandé cedex - Contact : contact@meteo.fr

Rédigé par Météo-France avec la contribution des observateurs du réseau nivo-météorologiques. Partenariat : ANMSM (Maires de Stations de Montagne), DSF (Domaines Skiables de France), ADSP (Directeurs de Pistes et de la Sécurité des Stations de Sports d'Hiver) et autres acteurs de la montagne.

Bulletin neige & avalanches par téléphone au
0 892 68 10 20 Service 0,35 € / min + prix appel

RÉPUBLIQUE FRANÇAISE
Liberté Égalité Fraternité

METEO FRANCE
À VOS CÔTÉS, DANS UN CLIMAT QUI CHANGE

Bulletin d'estimation du risque d'avalanche

(valable en dehors des pistes balisées et ouvertes)

MASSIF : Pays-Basque

Rédigé le mardi 3 mars 2026 à 16h

Conditions nivo-météo des 7 derniers jours

	mer. 25/02				jeu. 26/02				ven. 27/02				sam. 28/02				dim. 01/03				lun. 02/03				mar. 03/03			
	03h	09h	15h	21h	03h	09h	15h	21h	03h	09h	15h	21h	03h	09h	15h	21h	03h	09h	15h	21h	03h	09h	15h	21h	03h	09h	15h	21h
Météo																												
Vent (km/h)	35	35	35	35	35	35	45	50	50	55	45	30	25	25	25	25	30	50	75	85	85	80	80	70	50	25	15	20
à 2000m																												
Vent (km/h)	15	15	15	15	20	20	25	30	40	40	25	15	10	10	15	15	15	25	50	55	60	55	45	40	35	20	15	10
à 1000m																												

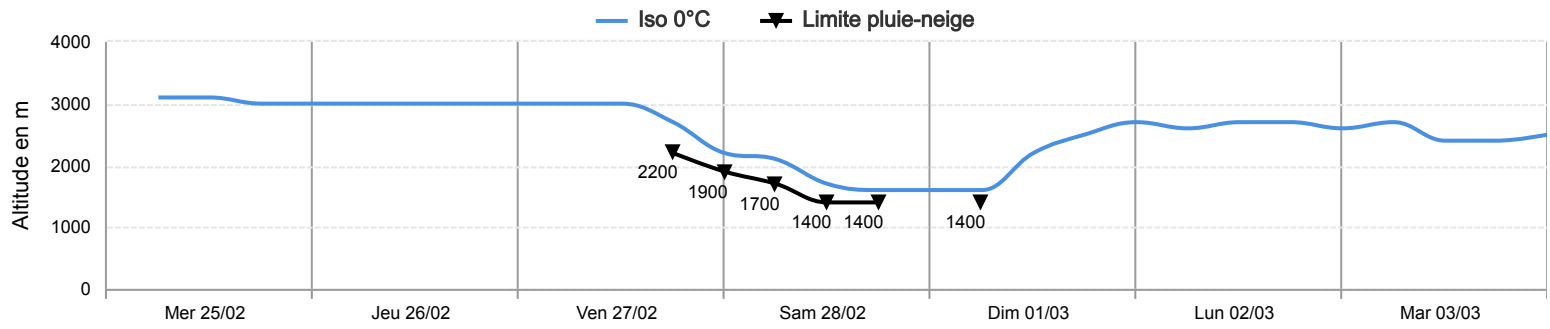

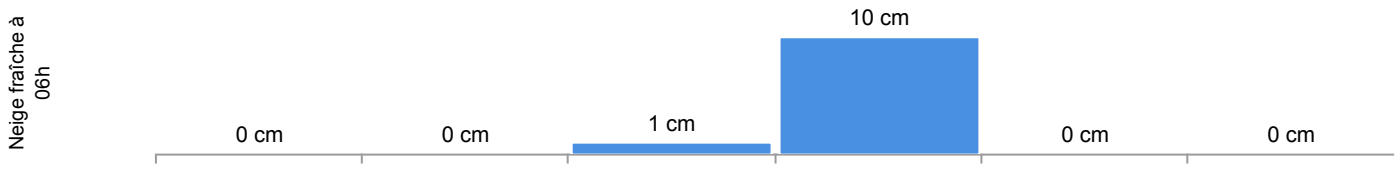

Risque d'avalanche	mer. 25/02	jeu. 26/02	ven. 27/02	sam. 28/02	dim. 01/03	lun. 02/03	mar. 03/03
	1	1	1	1	1	1	2

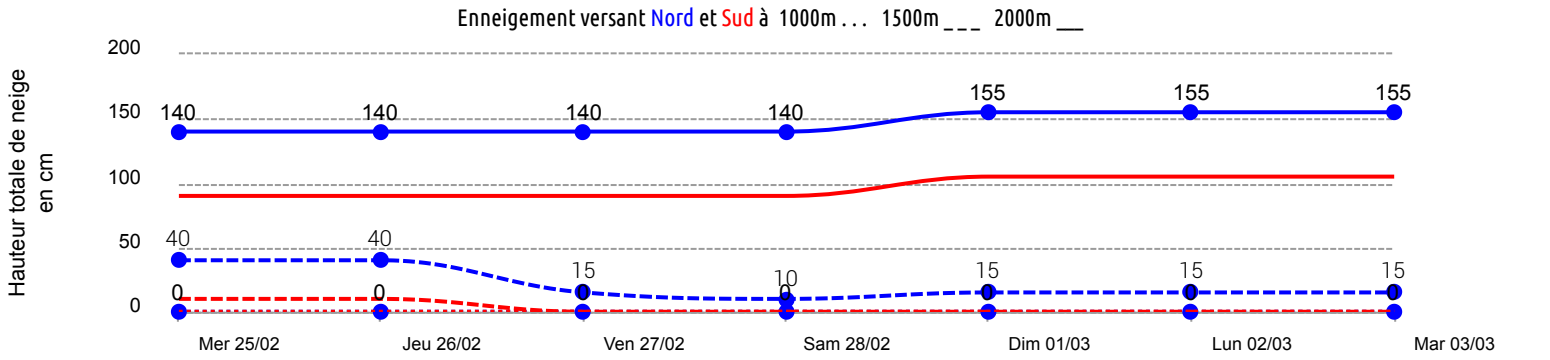

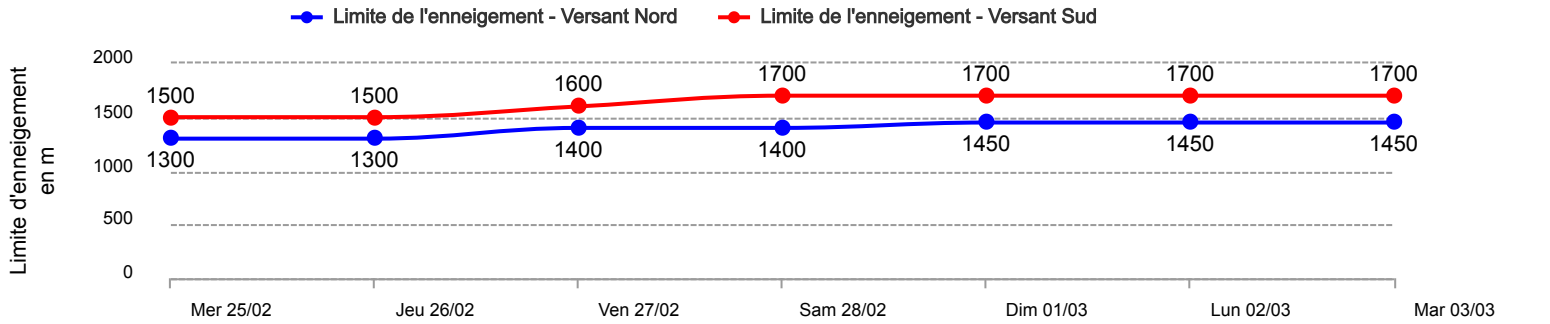

Pour consulter la vigilance en cours, veuillez vous rendre sur le site https://vigilance.meteofrance.fr/fr

Météo-France - 73 avenue de Paris, 94165 Saint-Mandé cedex - Contact : contact@meteo.fr

Bulletin neige & avalanches par téléphone au **0 892 68 10 20** Service 0,35 € / min + prix appel

Rédigé par Météo-France avec la contribution des observateurs du réseau nivo-météorologiques. Partenariat : ANMSM (Maires de Stations de Montagne), DSF (Domaines Skiables de France), ADSP (Directeurs de Pistes et de la Sécurité des Stations de Sports d'Hiver) et autres acteurs de la montagne.