Bulletin d'estimation du risque d'avalanche

(valable en dehors des pistes balisées et ouvertes)

MASSIF : Pelvoux

Rédigé le mardi 3 mars 2026 à 16h

Estimation des risques pour le : MERCREDI 04 MARS

PLAQUES EN ALTITUDE, DIFFICILES À SOLLICITER - ÉVENTUELLE ACTIVITÉ EN NEIGE HUMIDE

2

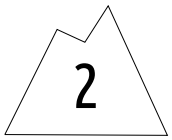

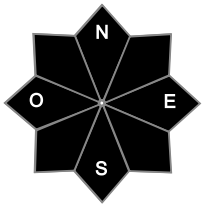

Indice de risque limité.

Départs spontanés : éventuels départs en neige humide en journée ou avalanches de fond

Déclenchements provoqués : avalanches de plaque difficiles à déclencher en altitude, mais pouvant engendrer d'épaisses cassures

Indices de risque : 5 très fort - 4 fort - 3 marqué - 2 limité - 1 faible -- En noir : les pentes les plus dangereuses

Stabilité du manteau neigeux

Situation avalancheuse typique :

couche fragile persistante

neige humide

Déclenchements provoqués :

- même si le déclenchement semble difficile, une avalanche de plaque reste encore possible (structure de plaque sur couche fragile persistante enfouie). Sollicitation dans les endroits moins enneigés ou les abords de croupes et bords des couloirs, dans les versants de large nord au-dessus de 2000/2200 m, plus haut dans les orientations plus ensoleillées. Avalanche de grande taille en ubac avec des cassures épaisses et larges, plutôt de taille moyenne en adret d'altitude. Danger difficile à détecter, la neige en surface présentant un aspect sec plus ou moins meuble, ou un aspect humidifié.
- un skieur évoluant dans une pente raide ayant trop réchauffé peut aussi favoriser un départ ponctuel en neige humide.

Départs spontanés :

- éventuelles avalanches de neige humide dans les pentes ensoleillées, parfois jusqu'au sol en neige pourrie l'après-midi. Départ linéaire non exclu. Taille petite à moyenne. Même si dans ces versants la neige présente un aspect printanier, l'humidification augmente par rapport à ces derniers jours. Le regel peut être aussi plus aléatoire en lien avec l'incertitude sur la couverture nuageuse nocturne.
- une avalanche de fond ou une reptation emportant la totalité du manteau neigeux en place jusqu'au sol peut céder spontanément à n'importe quel moment du jour ou de la nuit sur terrain favorable (pentes herbeuses, dalles rocheuses). Avalanche de taille moyenne.

Qualité de la neige

L'enneigement encore souvent excédentaire malgré le tassement.
Hauteurs de neige observées : 298 cm à la Nivôse des Écrins vers 3000 m, 210 cm au Pré de Mme Carle à 1900 m, 104 cm au hameau de Dormillouse à 1730 m.

Limite d'enneigement skiable en fond de vallées en ubacs, 1500/1600 m en adrets pas trop raides, sinon plus haut.

État de la neige de surface : croute plus ou moins portante le matin avec le regel plus aléatoire et une humidification plus rapide au soleil en journée. En versants nord-est à nord-ouest au-dessus de 2100/2200 m, vieille poudreuse encore meuble, plus travaillée par le vent proche des crêtes.

Aperçu météo pour le mercredi 04 mars

	nuit	matin	après-midi	soir

Ciel plus ou moins "laiteux" avec la présence de poussières désertiques en suspension dans l'atmosphère.

Pluie-Neige				
Iso 0 °C	2 300 m	2 300 m	2 500 m	2 400 m
Vent 2000 m	↘ 5 km/h	↘ 5 km/h	↗ 5 km/h	→ 5 km/h
Vent 3000 m	→ 5 km/h	↑ 5 km/h	↗ 5 km/h	↗ 10 km/h

Épaisseur de neige hors-piste

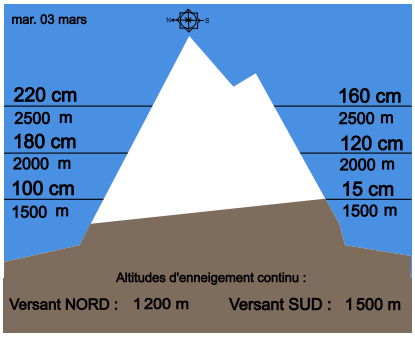

Précipitations à 1800 m

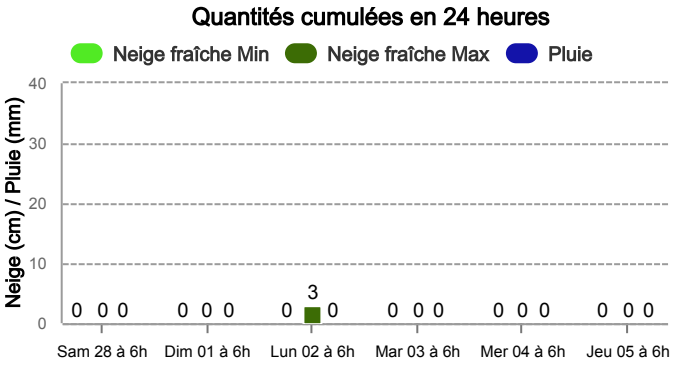

Tendance du jeudi 05 mars

2

Indice de risque limité

Risque limité. Encore des plaques difficiles à déclencher en altitude. Activité en neige humide limitée en journée.

Pour consulter la vigilance en cours, veuillez vous rendre sur le site https://vigilance.meteofrance.fr/fr

Météo-France - 73 avenue de Paris, 94165 Saint-Mandé cedex - Contact : contact@meteo.fr

Rédigé par Météo-France avec la contribution des observateurs du réseau nivo-météorologiques. Partenariat : ANMSM (Maires de Stations de Montagne), DSF (Domaines Skiables de France), ADSP (Directeurs de Pistes et de la Sécurité des Stations de Sports d'Hiver) et autres acteurs de la montagne.

Bulletin neige & avalanches par téléphone au

0 892 68 10 20 Service 0,35 € / min + prix appel

RÉPUBLIQUE FRANÇAISE
Liberté Égalité Fraternité

METEO FRANCE
À VOS CÔTÉS, DANS UN CLIMAT QUI CHANGE

Bulletin d'estimation du risque d'avalanche

(valable en dehors des pistes balisées et ouvertes)

MASSIF : Pelvoux

Rédigé le mardi 3 mars 2026 à 16h

Conditions nivo-météo des 7 derniers jours

	mer. 25/02				jeu. 26/02				ven. 27/02				sam. 28/02				dim. 01/03				lun. 02/03				mar. 03/03			
	03h	09h	15h	21h	03h	09h	15h	21h	03h	09h	15h	21h	03h	09h	15h	21h	03h	09h	15h	21h	03h	09h	15h	21h	03h	09h	15h	21h
Météo																												
Vent (km/h)	10	10	10	10	10	10	10	10	10	5	10	15	25	25	25	20	10	15	15	10	10	10	15	10	10	5	5	5
à 3000m																												
Vent (km/h)	5	5	5	5	5	5	5	5	5	5	5	5	5	10	15	10	5	10	15	10	5	5	10	5	5	5	5	5
à 2000m																												

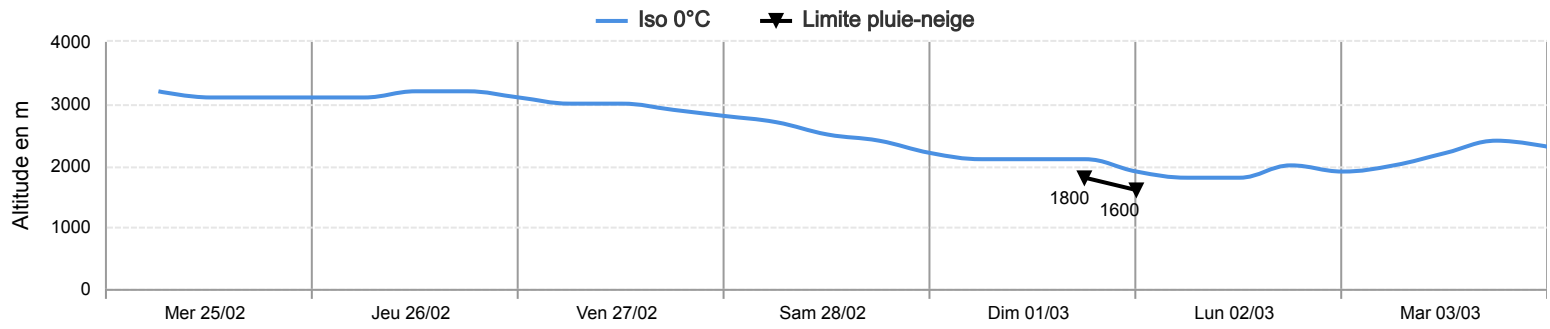

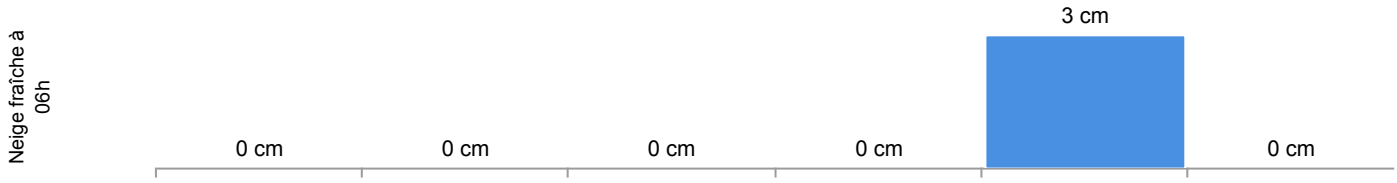

Risque d'avalanche	mer. 25/02	jeu. 26/02	ven. 27/02	sam. 28/02	dim. 01/03	lun. 02/03	mar. 03/03
	3	3	2	2	2	2	2

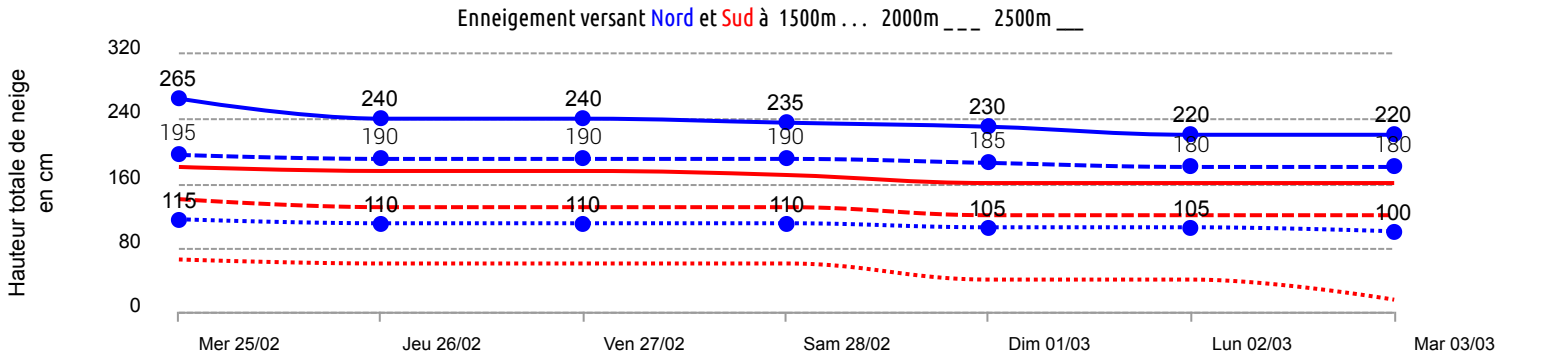

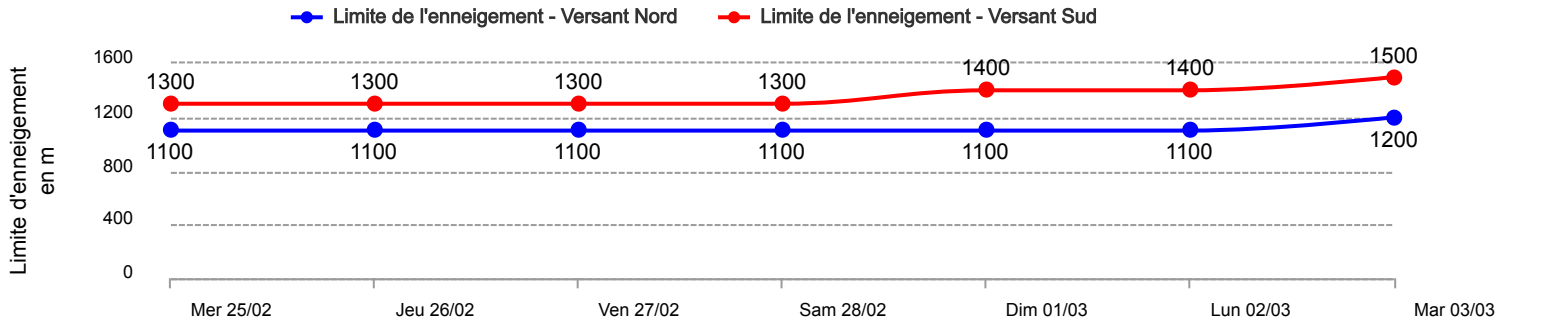

Pour consulter la vigilance en cours, veuillez vous rendre sur le site https://vigilance.meteofrance.fr/fr

Météo-France - 73 avenue de Paris, 94165 Saint-Mandé cedex - Contact : contact@meteo.fr

Bulletin neige & avalanches par téléphone au

0 892 68 10 20 Service 0,35 € / min + prix appel

Rédigé par Météo-France avec la contribution des observateurs du réseau nivo-météorologiques. Partenariat : ANMSM (Maires de Stations de Montagne), DSF (Domaines Skiables de France), ADSP (Directeurs de Pistes et de la Sécurité des Stations de Sports d'Hiver) et autres acteurs de la montagne.