Bulletin d'estimation du risque d'avalanche
(valable en dehors des pistes balisées et ouvertes)

MASSIF : Ubaye

Rédigé le mardi 3 mars 2026 à 16h

Estimation des risques pour le : MERCREDI 04 MARS

INSTABILITÉS ÉPAISSES MAIS DIFFICILES À DÉCLENCHER EN ALTITUDE - ACTIVITÉ PRINTANIÈRE NATURELLE LIMITÉE

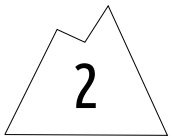

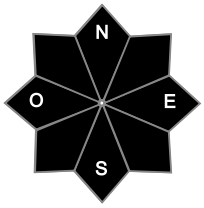

Indice de risque limité.

Départs spontanés : quelques avalanches de fond + activité en neige humide limitée au soleil.

Déclenchements provoqués : plaques épaisses, difficiles à déclencher + neige humide en pentes raides ensoleillées.

Indices de risque : 5 très fort - 4 fort - 3 marqué - 2 limité - 1 faible -- En noir : les pentes les plus dangereuses

Stabilité du manteau neigeux

Situation avalancheuse typique : couche fragile persistante avalanches de fond

Déclenchements provoqués : * Des plaques reposent sur des couches fragiles persistantes enfouies à la base du manteau neigeux. Déclenchement difficile, mais encore envisageable au passage d'un skieur là où les épaisseurs de neige sont moins importantes (près des croupes, bords de couloirs etc.). Cassure épaisse en cas de départ, emportant la quasi-totalité du manteau neigeux en place, et pouvant ponctuellement se propager sur une largeur significative en ubacs au-dessus de 2200 m environ. Danger présent également dans les pentes où seule la partie supérieure du manteau neigeux est humidifiée.
* Un skieur coupant une pente raide ayant trop chauffé au soleil peut initier une petite avalanche de neige humide.

Départs spontanés : * Quelques avalanches de fond à toute heure du jour ou de la nuit, souvent de taille moyenne (taille 2). Départs plutôt dans les pentes ouest, sud à est, avec terrain favorable (pentes herbeuses, dalles rocheuses).
* Un peu d'activité en neige humide selon la course du soleil, mais plutôt limitée. Avalanches généralement petites (taille 1), plus rarement moyennes (taille 2), notamment en cas de départ linéaire.
* Un déclenchement de plaque non exclu, en cas de chute de corniche.

Qualité de la neige

Enneigement proche des normales pour un début mars, mais plutôt déficitaire dans les adrets de basse altitude.
Données observées : 70 cm à la Nivôse de Restefond à 2550 m (secteur venté), 90 cm au-dessus de Larche à 2270 m en adret.

Enneigement skiable : vers 1500 m en ubacs, 1800/2000 m en adrets selon les secteurs et l'inclinaison de la pente.

État de la neige en surface : manteau neigeux en cycle printanier dans les adrets jusqu'à très haute altitude. Neige plus ou moins croûtée le matin, s'humidifiant au soleil l'après-midi. Dans les ubacs, neige encore froide au-dessus de 2200/2300 m environ, parfois travaillée ou durcie par le vent passé, ou en vieille neige meuble. Quelques corniches épaisses près des crêtes.

Aperçu météo pour le mercredi 04 mars

	nuit	matin	après-midi	soir

Lumineux, avec des voiles nuageux d'altitude plus ou moins denses. Vent très faible à tout niveau.

Pluie-Neige				
Iso 0 °C	2 300 m	2 300 m	2 400 m	2 500 m
Vent 2000 m	5 km/h	5 km/h	10 km/h	10 km/h
Vent 3000 m	10 km/h	10 km/h	10 km/h	5 km/h

Épaisseur de neige hors-piste

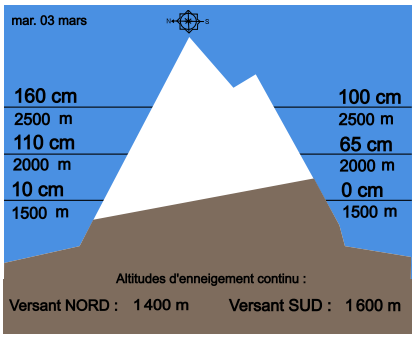

Précipitations à 1800 m

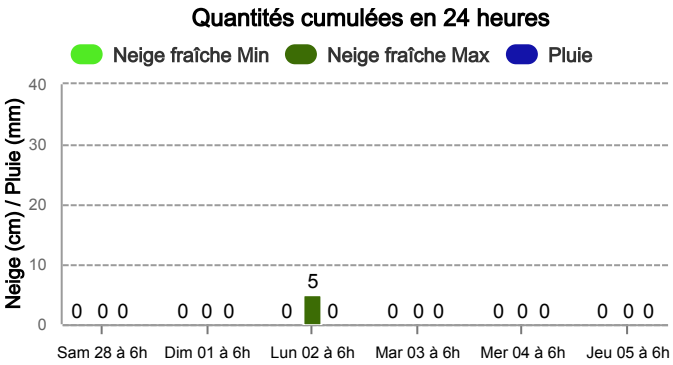

Tendance du jeudi 05 mars

Indice de risque limité

Conditions nivologiques similaires.
Maintien d'un risque limité.

Pour consulter la vigilance en cours, veuillez vous rendre sur le site https://vigilance.meteofrance.fr/fr

Météo-France - 73 avenue de Paris, 94165 Saint-Mandé cedex - Contact : contact@meteo.fr

Rédigé par Météo-France avec la contribution des observateurs du réseau nivo-météorologiques. Partenariat : ANMSM (Maires de Stations de Montagne), DSF (Domaines Skiables de France), ADSP (Directeurs de Pistes et de la Sécurité des Stations de Sports d'Hiver) et autres acteurs de la montagne.

Bulletin neige & avalanches par téléphone au **0 892 68 10 20** Service 0,35 € / min + prix appel

RÉPUBLIQUE FRANÇAISE
Liberté Égalité Fraternité

METEO FRANCE
À VOS CÔTÉS, DANS UN CLIMAT QUI CHANGE

Bulletin d'estimation du risque d'avalanche
(valable en dehors des pistes balisées et ouvertes)

MASSIF : Ubaye

Rédigé le mardi 3 mars 2026 à 16h

Conditions nivo-météo des 7 derniers jours

	mer. 25/02				jeu. 26/02				ven. 27/02				sam. 28/02				dim. 01/03				lun. 02/03				mar. 03/03			
	03h	09h	15h	21h	03h	09h	15h	21h	03h	09h	15h	21h	03h	09h	15h	21h	03h	09h	15h	21h	03h	09h	15h	21h	03h	09h	15h	21h
Météo																												
Vent (km/h)	10	10	10	10	10	10	10	10	10	10	10	10	10	20	20	15	20	20	20	20	10	15	15	10	10	10	10	10
à 3000m																												
Vent (km/h)	10	5	10	10	5	5	5	5	5	5	10	5	5	10	15	5	5	10	15	10	10	15	15	10	10	5	10	10
à 2000m																												

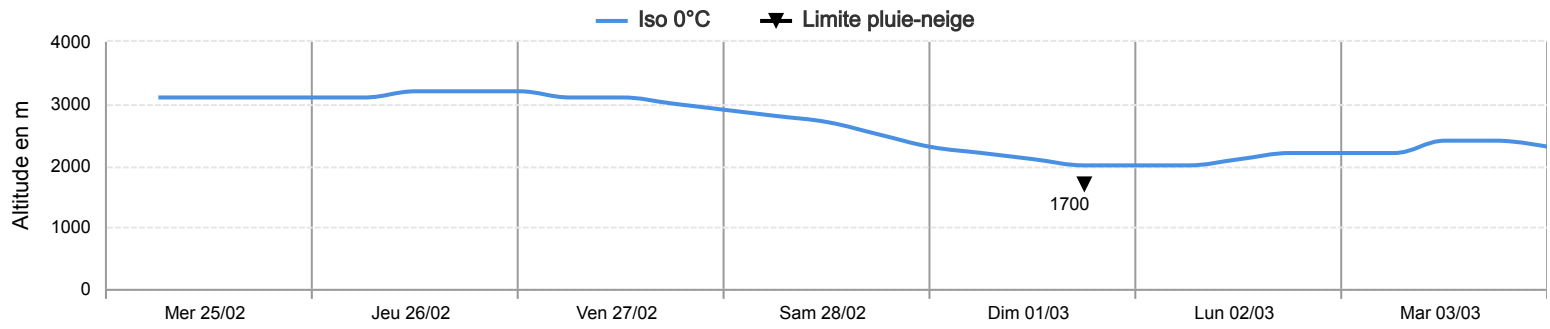

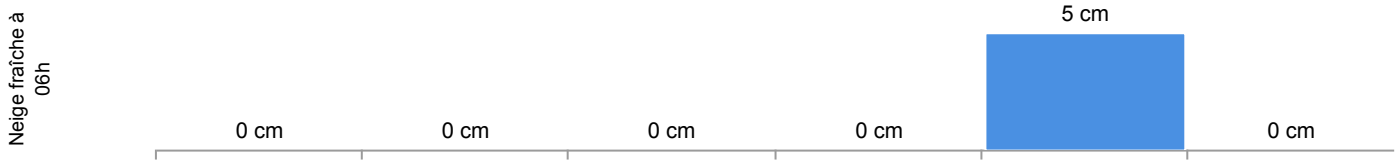

Risque d'avalanche	mer. 25/02	jeu. 26/02	ven. 27/02	sam. 28/02	dim. 01/03	lun. 02/03	mar. 03/03
	3	3	2	2	2	2	2

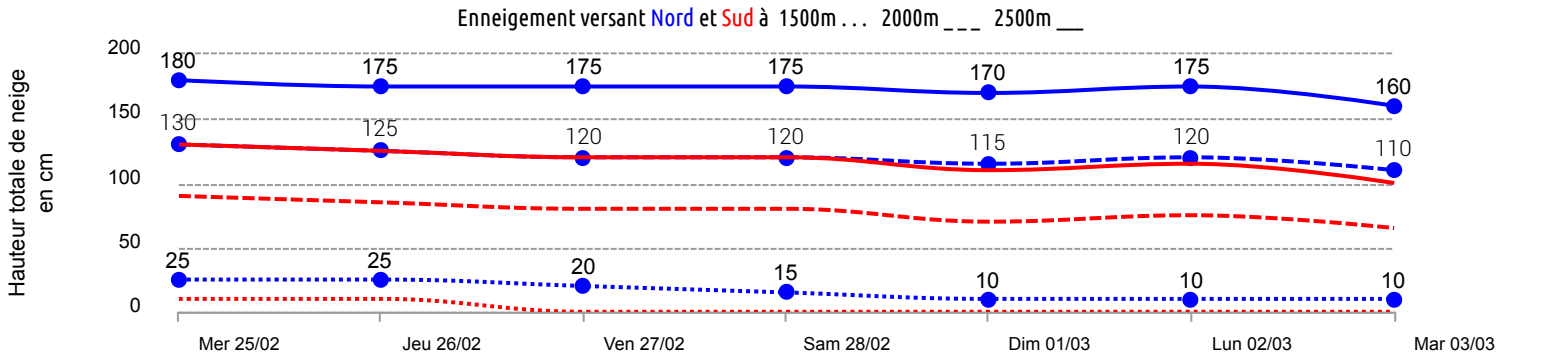

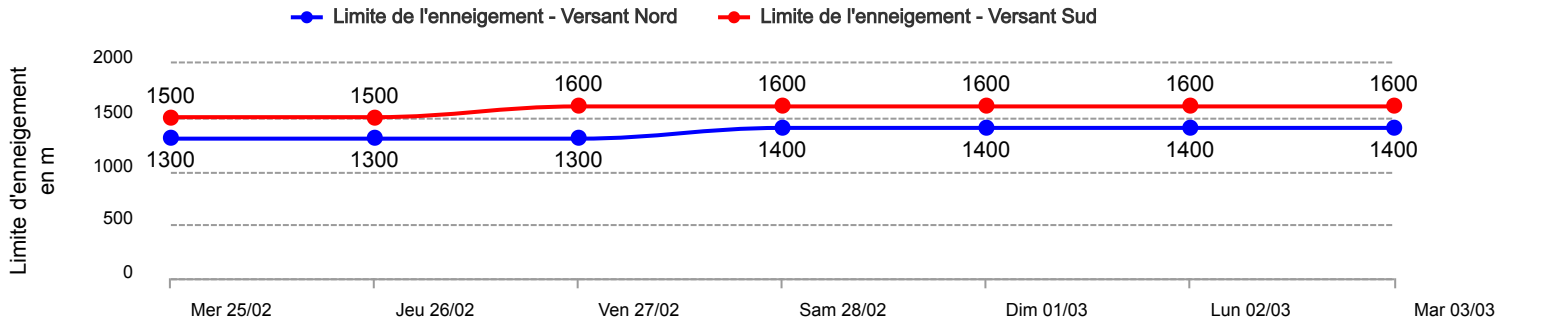

Pour consulter la vigilance en cours, veuillez vous rendre sur le site https://vigilance.meteofrance.fr/fr

Météo-France - 73 avenue de Paris, 94165 Saint-Mandé cedex - Contact : contact@meteo.fr

Rédigé par Météo-France avec la contribution des observateurs du réseau nivo-météorologiques. Partenariat : ANMSM (Maires de Stations de Montagne), DSF (Domaines Skiables de France), ADSP (Directeurs de Pistes et de la Sécurité des Stations de Sports d'Hiver) et autres acteurs de la montagne.

Bulletin neige & avalanches par téléphone au
0 892 68 10 20 Service 0,35 € / min + prix appel