Bulletin d'estimation du risque d'avalanche
(valable en dehors des pistes balisées et ouvertes)

MASSIF : Vercors

Rédigé le mardi 3 mars 2026 à 16h

Estimation des risques pour le : MERCREDI 04 MARS

FAIBLE ACTIVITE EN LARGE SUD, AVEC QUELQUES COULEES HUMIDES OU PLAQUES DE FONDS

2

1 → 2

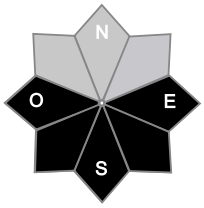

Indice de risque faible évoluant en limité.

Départs spontanés : Quelques plaques de fonds ou coulées humides en large secteur Sud.

Déclenchements provoqués : Départs ponctuels sous les skis en neige humide.

Indices de risque : 5 très fort - 4 fort - 3 marqué - 2 limité - 1 faible -- En noir : les pentes les plus dangereuses

Stabilité du manteau neigeux

Situation avalancheuse typique : neige humide — avalanches de fond

Sous l'effet de plus d'une semaine de soleil et de douceur, le manteau neigeux s'est considérablement tassé et il est bien consolidé grâce à un regel nocturne efficace.
Départs spontanés : A toute heure de la journée ou de la nuit et principalement en large secteur Sud, possible avalanche de fond en pente raide herbeuse, de tailles moyennes. Avalanches parfois précédées par l'ouverture d'une fissure / gueule de baleine. Aux heures chaudes et toujours en large Sud, possibles coulées humides en pente raide, surtout sous les rochers.
Déclenchements provoqués : Peu probables, ou alors une coulée humide sous les skis aux heures chaudes.

Qualité de la neige

Qualification de l'enneigement : L'enneigement régresse en partie basse, mais il est toujours bon pour la saison dès 1300 m, voire très bon au dessus de 1500 m environ, notamment dans les combes d'altitude. On trouve des crêtes un peu dégarnies par le vent, ou au contraire des corniches assez conséquentes.

Limites skiables : vers 1200/1600 m.

Qualité de la neige mercredi : Manteau neigeux de type printanier avec une neige croûtée par le regel nocturne, s'humidifiant en journée, parfois profondément selon l'orientation. Encore très localement un peu de neige froide en versants Nord.

Aperçu météo pour le mercredi 04 mars

	nuit	matin	après-midi	soir
Grande douceur sous un ciel voilé, avec une atmosphère chargée de sable Saharien.				
Pluie-Neige				
Iso 0 °C	2 300 m	2 300 m	2 400 m	2 500 m
Vent 1500 m	↖ 10 km/h	↖ 10 km/h	↗ 15 km/h	↖ 10 km/h
Vent 2000 m	↑ 10 km/h	↗ 15 km/h	↗ 15 km/h	← 10 km/h

Épaisseur de neige hors-piste

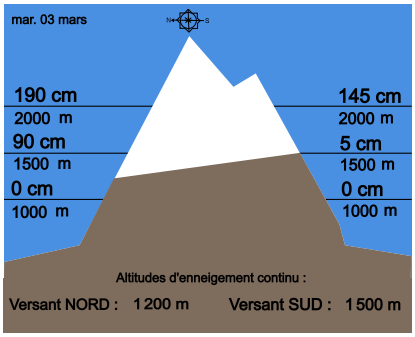

Précipitations à 1800 m

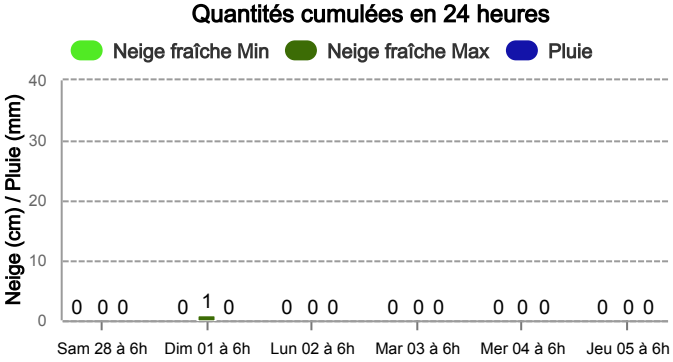

Tendance du jeudi 05 mars

2

Indice de risque limité

Peu d'évolution, risque restant limité jeudi, dans une ambiance toujours printanière.

Pour consulter la vigilance en cours, veuillez vous rendre sur le site https://vigilance.meteofrance.fr/fr

Météo-France - 73 avenue de Paris, 94165 Saint-Mandé cedex - Contact : contact@meteo.fr

Rédigé par Météo-France avec la contribution des observateurs du réseau nivo-météorologiques. Partenariat : ANMSM (Maires de Stations de Montagne), DSF (Domaines Skiables de France), ADSP (Directeurs de Pistes et de la Sécurité des Stations de Sports d'Hiver) et autres acteurs de la montagne.

Bulletin neige & avalanches par téléphone au 0 892 68 10 20 Service 0,35 € / min + prix appel

RÉPUBLIQUE FRANÇAISE
Liberté Égalité Fraternité

METEO FRANCE
À VOS CÔTÉS, DANS UN CLIMAT QUI CHANGE

Bulletin d'estimation du risque d'avalanche
(valable en dehors des pistes balisées et ouvertes)

MASSIF : Vercors

Rédigé le mardi 3 mars 2026 à 16h

Conditions nivo-météo des 7 derniers jours

	mer. 25/02				jeu. 26/02				ven. 27/02				sam. 28/02				dim. 01/03				lun. 02/03				mar. 03/03			
	03h	09h	15h	21h	03h	09h	15h	21h	03h	09h	15h	21h	03h	09h	15h	21h	03h	09h	15h	21h	03h	09h	15h	21h	03h	09h	15h	21h
Météo																												
Vent (km/h)	15	20	25	25	15	15	10	10	5	0	10	15	20	15	25	25	30	35	35	45	55	55	50	45	25	15	15	5
à 2000m																												
Vent (km/h)	10	15	20	10	10	5	5	5	5	5	10	10	20	15	15	15	25	25	25	40	50	45	35	20	20	15	15	5
à 1500m																												

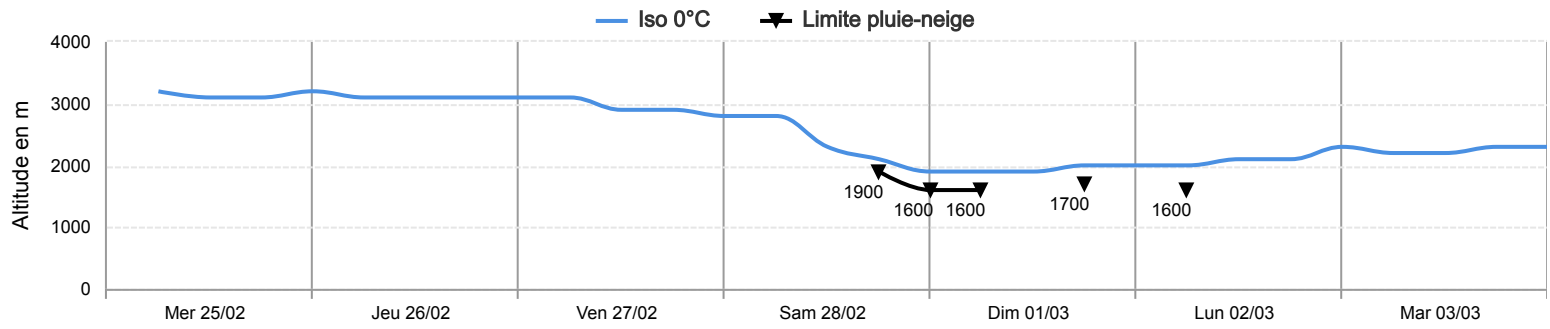

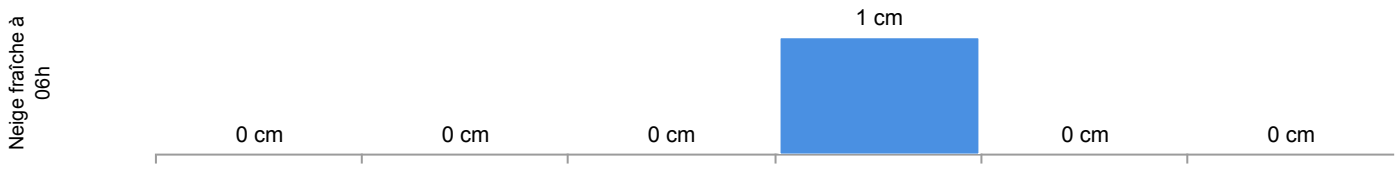

Risque d'avalanche	mer. 25/02	jeu. 26/02	ven. 27/02	sam. 28/02	dim. 01/03	lun. 02/03	mar. 03/03
	2	2	2	2	1	2	2

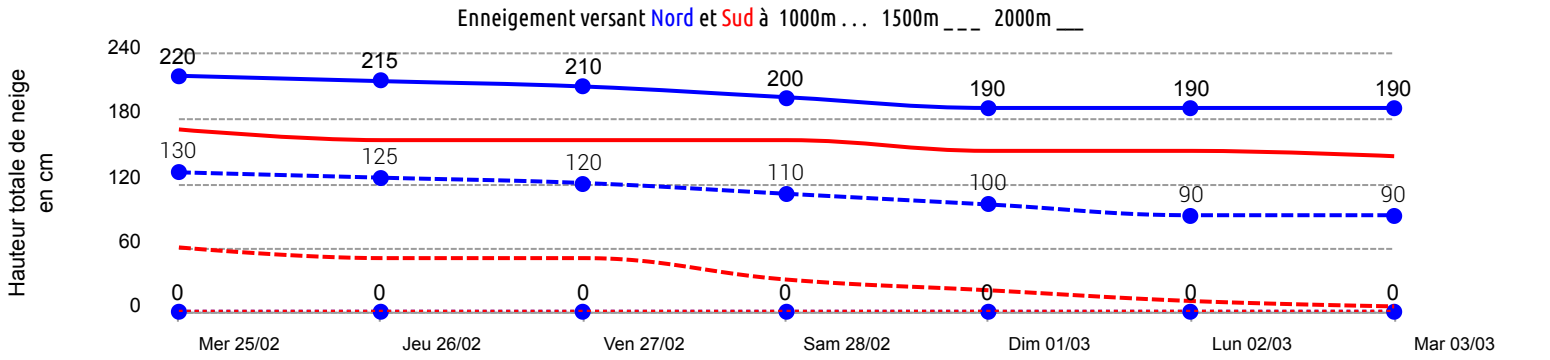

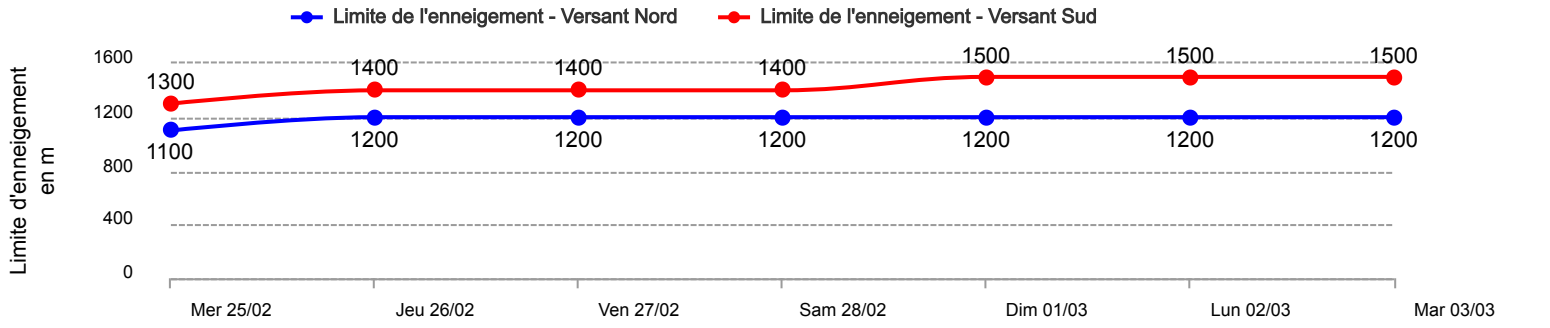

Pour consulter la vigilance en cours, veuillez vous rendre sur le site https://vigilance.meteofrance.fr/fr

Météo-France - 73 avenue de Paris, 94165 Saint-Mandé cedex - Contact : contact@meteo.fr

Rédigé par Météo-France avec la contribution des observateurs du réseau nivo-météorologiques. Partenariat : ANMSM (Maires de Stations de Montagne), DSF (Domaines Skiables de France), ADSP (Directeurs de Pistes et de la Sécurité des Stations de Sports d'Hiver) et autres acteurs de la montagne.

Bulletin neige & avalanches par téléphone au
0 892 68 10 20 Service 0,35 € / min + prix appel