GOBIERNO DE ESPAÑA
VICEPRESIDENCIA TERCERA DEL GOBIERNO
MINISTERIO PARA LA TRANSICIÓN ECOLÓGICA Y EL RETO DEMOGRÁFICO

Boletín de información nivológica y de peligro de aludes

# Pirineo Catalán

aemet Agencia Estatal de Meteorología

## miércoles, 4 de marzo de 2026

## Pronóstico hasta las 24 horas del jueves, día 5 de marzo

(Válido fuera de pistas de esquí balizadas y abiertas)

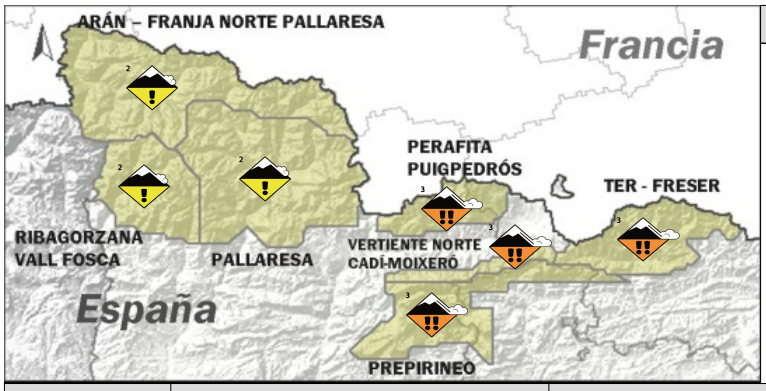


### Problemas de aludes

- Nieve reciente
- Nieve húmeda
- Deslizamientos basales

| Macizo | Peligro | Problemas de aludes, cota, orientación, tamaño | Innivación observada (m) |
|---|---|---|---|
| Arán - Franja norte Pallaresa | 2 Limitado | **Nieve reciente** 2200 N O E S 1<br>**Deslizamientos basales** 2300 N O E S 1 | 2026-03-04<br>N S<br>Cota más baja caras N |
| Ribagorzana - Vall Fosca | 2 Limitado | **Nieve reciente** 2200 N O E S 1<br>**Deslizamientos basales** 2300 N O E S 1 | 2026-03-04<br>N S<br>Cota más baja caras N |
| Pallaresa | 2 Limitado | **Nieve reciente** 2200 N O E S 1<br>**Deslizamientos basales** 2300 N O E S 1 | 2026-03-04<br>N S<br>Cota más baja caras N |


AEMET. Se autoriza la reproducción de su contenido citando la fuente.

Boletín de información nivológica y de peligro de aludes

# Pirineo Catalán



| | | | | |
|---|---|---|---|---|
| **Perafita - Puigpedrós** | 3 Por la tarde **Notable** | **Nieve reciente** 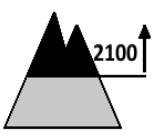   | 2026-03-04 Cota más baja caras N |
| | | **Nieve húmeda**   | |
| **Ter - Freser** | 3 Horas centrales **Notable** | **Nieve reciente** 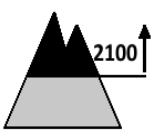   | 2026-03-04 Cota más baja caras N |
| | | **Nieve húmeda**   | |
| **Vertiente norte Cadí - Moixeró** | 3 Por la tarde **Notable** | **Nieve reciente** 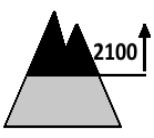   | 2026-03-04 Cota más baja caras N |
| | | **Nieve húmeda** 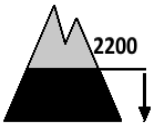   | |
| **Prepirineo** | 3 Por la tarde **Notable** | **Nieve reciente** 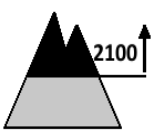   | 2026-03-04 Cota más baja caras N |
| | | **Nieve húmeda**   | |

## Estado del manto y observaciones recientes

Ayer martes se dieron algunas precipitaciones débiles, en forma de nieve por encima de 1800-2000 metros. Los espesores apenas han variado escasos centímetros, en positivo en algunos casos, y continúan siendo muy superiores al promedio a esta altura de la temporada. Por encima de unos 2200 metros se superan los 150-200 cm en muchas zonas, aún más en ventisqueros, hoyas y otras zonas propensas a la acumulación.


AEMET. Se autoriza la reproducción de su contenido citando la fuente.

En cotas medias y bajas, así como en solanas a mayor altitud, el manto se ha humidificado en profundidad y, por lo general, amanece encostrado. Las costras se ablandan durante la mañana en las solanas, sometidas a un ciclo de rehielo-fusión diario, menos efectivo en umbrías de cotas medias. En umbrías de cotas altas, la nieve se mantiene más seca y aún podemos encontrar placas de viento que no se hayan estabilizado por completo. También en estas zonas podría persistir alguna capa débil enterrada que pueda seguir latente.

## Evolución del manto y peligro de aludes para el jueves, día 5

Problemas de nieve reciente y placas de viento en cotas altas. Problemas de nieve húmeda y deslizamientos basales en cotas medias y bajas.

Mañana jueves se esperan nevadas por encima 2000-2200 metros, que podrán acumular en torno a 20-30 cm en los macizos orientales, y considerablemente menos en los occidentales. A medida que avance el día serán más probables los problemas de nieve reciente, con aludes naturales de tamaño pequeño (1, riesgo de caída) o mediano (2, capaz de enterrar a una persona). Las nevadas irán acompañadas de vientos fuertes del sureste, por lo que se espera que se formen placas de viento en orientaciones norte y oeste por encima de 2400 metros durante la tarde.

En cotas medias y bajas, las lluvias junto con la ausencia de rehielo nocturno agravarán el problema de nieve húmeda, siendo probables los aludes espontáneos desde por la mañana en la mitad oriental, y por la tarde en el resto. Se espera que sean de tamaño pequeño o mediano. Asimismo, no se descartan los deslizamientos basales en zonas herbosas o de roca lisa, que podrían movilizar una cantidad de nieve considerable y alcanzar tamaño mediano o localmente grande (3, capaz de enterrar a un grupo de personas).

## Predicción meteorológica para el jueves, día 5

Nuboso tendiendo por la tarde a cubierto, reduciéndose localmente la visibilidad. Precipitaciones moderadas, a veces como chubascos, dispersas por la mañana y generalizadas por la tarde. Serán persistentes y localmente fuertes en el Ripollés y Prepirineo. Cota de nieve: 2000-2200 metros. Tormentas ocasionales acompañando a los chubascos. Temperaturas con cambios ligeros, mínimas en ascenso y máximas en descenso. Heladas débiles en cotas altas, moderadas en cumbres. Viento del este y sureste, fuerte con probables rachas muy fuertes en cotas altas. En el resto, moderado con intervalos fuertes en el sector oriental y menos intenso en el occidental.

Datos en la atmósfera libre:

Altitud de la isoterma de 0 ºC: 2600 m
Altitud de la isoterma de -10 ºC: 4200 m

Viento a 1500 m: E 30 km/h
Viento a 3000 m: E 50 km/h

## Evolución para el viernes día 6

Peligro en ligero ascenso con la continuación de las nevadas.


AEMET. Se autoriza la reproducción de su contenido citando la fuente.

# Boletín de información nivológica y de peligro de aludes

# Pirineo Catalán



Escala europea de peligro de aludes

Débil | Limitado | Notable | Fuerte | Muy Fuerte

Problemas de aludes

Nieve reciente | Placas de viento | Capas débiles persistentes | Nieve húmeda | Deslizamientos basales | Sin problema evidente

Nota1: Se recuerda que, siempre que haya nieve, la ausencia total de peligro no existe. Hay que tener presente que en circunstancias desfavorables, con aludes de tamaño 1 (alud pequeño o colada) y tamaño 2 (alud mediano), se pueden sufrir severos daños personales.

Nota2: Los BPA se elaboran en base a información meteorológica así como al estado del manto nivoso a través de sondeos puntuales. Se advierte a los usuarios de la variabilidad de esta información al extrapolarla a zonas extensas de montaña. Por ello, AEMET no se hace responsable de su uso para la toma de decisiones que conciernen a la seguridad personal, ni de los riesgos físicos o materiales de ellas derivadas.


AEMET. Se autoriza la reproducción de su contenido citando la fuente.