GOBIERNO DE ESPAÑA
VICEPRESIDENCIA TERCERA DEL GOBIERNO
MINISTERIO PARA LA TRANSICIÓN ECOLÓGICA Y EL RETO DEMOGRÁFICO

Boletín de información nivológica y de peligro de aludes

Pirineo Navarro y Aragonés

aemet Agencia Estatal de Meteorología

miércoles, 4 de marzo de 2026

Pronóstico hasta las 24 horas del jueves, día 5 de marzo

(Válido fuera de pistas de esquí balizadas y abiertas)

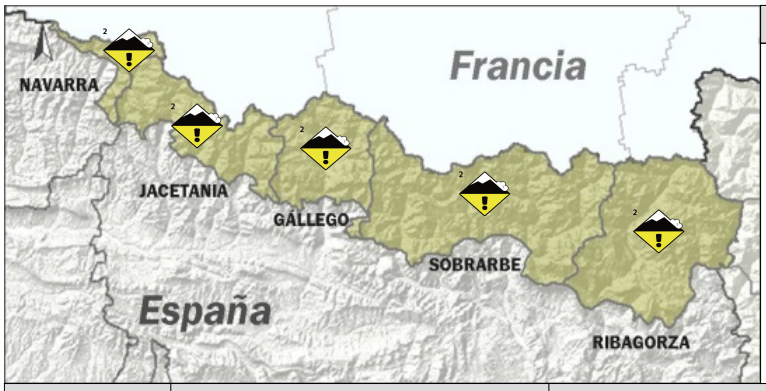

Problemas de aludes

Nieve reciente

Deslizamientos basales

Macizo	Peligro	Problemas de aludes, cota, orientación, tamaño	Innivación observada (m)
Navarra	2 — Limitado	Nieve reciente: 2100, N O E S, 1	2026-03-04
		Deslizamientos basales: 2200, N O E S, 2	N S — Cota más baja caras N
Jacetania	2 — Limitado	Nieve reciente: 2100, N O E S, 1	2026-03-04
		Deslizamientos basales: 2200, N O E S, 2	N S — Cota más baja caras N
Gállego	2 — Limitado	Nieve reciente: 2100, N O E S, 2	2026-03-04
		Deslizamientos basales: 2200, N O E S, 2	N S — Cota más baja caras N

AEMET. Se autoriza la reproducción de su contenido citando la fuente.

Boletín de información nivológica y de peligro de aludes

Pirineo Navarro y Aragonés

Sobrarbe	**Limitado**	**Nieve reciente** 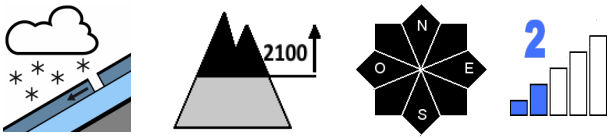 **Deslizamientos basales** 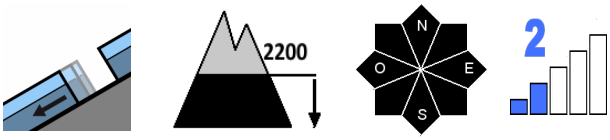	2026-03-04 Cota más baja caras N
Ribagorza	**Limitado**	**Nieve reciente** 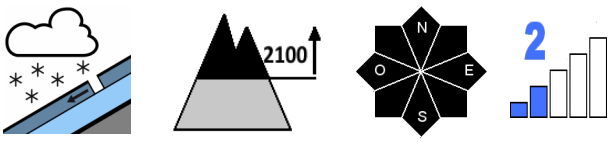 **Deslizamientos basales** 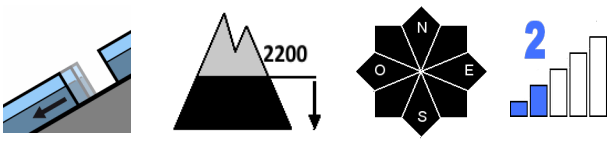	2026-03-04 Cota más baja caras N

Estado del manto y observaciones recientes

Ayer martes se dieron algunas precipitaciones débiles, en forma de nieve por encima de 2100 metros, con acumulaciones en algunos casos de hasta 5-10 centímetros. Por debajo, los espesores han menguado ligeramente, aunque continúan siendo superiores al promedio a esta altura de la temporada. En general la nieve es continua desde 1400 m en orientaciones norte y 1600 m en las sur. El manto es muy abundante desde cotas medias, aunque con perdida notable en las solanas inclinadas. Se alcanzan espesores de 160 cm a 1800 m y 280 cm a 2300 m.

La nieve reciente en superficie se ha depositado con algo de polvo sahariano, sobre un manto primaveral en solanas con ciclo de fusión rehielo con presencia de costras esta madrugada en cotas bajas. Por debajo de 2200 metros el manto está humedecido hasta su base. En cotas altas el manto está seco y, en umbrías, algunas zonas localizadas al abrigo del viento aún conservan algunas placas de viento que pueden descansar sobre capas débiles de facetas o nieve granulada. Los tests apuntan que podrían desencadenarse ante sobrecargas fuertes. Asimismo, en la base del manto aún siguen presentes algunas capas débiles persistentes, generalmente inactivas.

En las últimas 24h se han observado numerosas purgas de nieve reciente en laderas muy inclinadas de todas las orientaciones.

Evolución del manto y peligro de aludes para el jueves, día 5

Problemas de nieve reciente y placas de viento en cotas altas. Problemas de nieve húmeda y deslizamientos basales en cotas medias y bajas.

AEMET. Se autoriza la reproducción de su contenido citando la fuente.

Mañana jueves se esperan nevadas por encima 2000-2200 metros, que podrán acumular en torno a 10-15 cm en los macizos orientales, 5-10 cm en los occidentales, principalmente en la segunda mitad del día. A medida que avance la tarde serán más probables los problemas de nieve reciente, con aludes naturales de tamaño pequeño (1, riesgo de caída) o mediano (2, capaz de enterrar a una persona). Las nevadas irán acompañadas de vientos fuertes del sureste, por lo que se espera que se vayan formando placas de viento en orientaciones norte y oeste a partir de media tarde. Dada la presencia en algunos enclaves de las umbrías de placas viejas o costras sobre capas débiles, la rotura de las placas recientes podría movilizar mayor cantidad de nieve y desencadenar aludes medianos o alguno localmente grande (3, capaz de enterrar a un grupo de personas). Tampoco se descarta que pueda reactivarse alguna capa débil persistente, especialmente en zonas de manto más delgado o erosionado.

En cotas medias y bajas, las lluvias junto con la ausencia de rehielo nocturno agravarán el problema de nieve húmeda, siendo probables los aludes espontáneos sobre todo por la tarde cuando se generalicen las precipitaciones, de tamaño pequeño o localmente mediano, así como los deslizamientos basales en zonas herbosas o de roca lisa, que podrían movilizar una cantidad de nieve considerable y alcanzar tamaño mediano o localmente grande.

Predicción meteorológica para el jueves, día 5

Intervalos nubosos aumentando durante la tarde hasta quedar cubierto, reduciéndose localmente la visibilidad. Precipitaciones débiles o moderadas, a veces como chubascos, principalmente en la segunda mitad del día aunque podrán darse algunas por la mañana en el tercio oriental. Cota de nieve: 2000-2200 metros. Tormentas ocasionales acompañando a los chubascos. Temperaturas sin cambios o en ligero ascenso. Heladas débiles en cotas altas, moderadas en cumbres. Predominio de viento del este y sureste, flojo o moderado hasta media tarde cuando arreciará llegando a soplar continuamente fuerte en cotas altas.

Datos en la atmósfera libre:

Altitud de la isoterma de 0 ºC: 2600 m
Altitud de la isoterma de -10 ºC: 4100 m

Viento a 1500 m: SE 10 km/h
Viento a 3000 m: SE 30 km/h

Evolución para el viernes día 6

Peligro en ligero ascenso con la continuación de las precipitaciones.

(Información elaborada a partir de los datos recibidos de los refugios de Linza, Lizara, Panticosa, Góriz, Pineta, Estós, Angel Orús, La Renclusa, Cap de Llauset y Belagua, de las estaciones de esquí de Candanchú, Formigal y Panticosa (lagos), de la estación de esquí de fondo de Llanos del Hospital y de Ordesa Pradera)

Escala europea de peligro de aludes

Débil Limitado Notable Fuerte Muy Fuerte

Problemas de aludes

Nieve reciente Placas de viento Capas débiles persistentes Nieve húmeda Deslizamientos basales Sin problema evidente

Nota1: Se recuerda que, siempre que haya nieve, la ausencia total de peligro no existe. Hay que tener presente que en circunstancias desfavorables, con aludes de tamaño 1 (alud pequeño o colada) y tamaño 2 (alud mediano), se pueden sufrir severos daños personales.

AEMET. Se autoriza la reproducción de su contenido citando la fuente.

Nota2: Los BPA se elaboran en base a información meteorológica así como al estado del manto nivoso a través de sondeos puntuales. Se advierte a los usuarios de la variabilidad de esta información al extrapolarla a zonas extensas de montaña. Por ello, AEMET no se hace responsable de su uso para la toma de decisiones que conciernen a la seguridad personal, ni de los riesgos físicos o materiales de ellas derivadas.

AEMET. Se autoriza la reproducción de su contenido citando la fuente.