Donnerstag 05.03.2026

Veröffentlicht am 04.03.2026 um 17:00

Vormittag

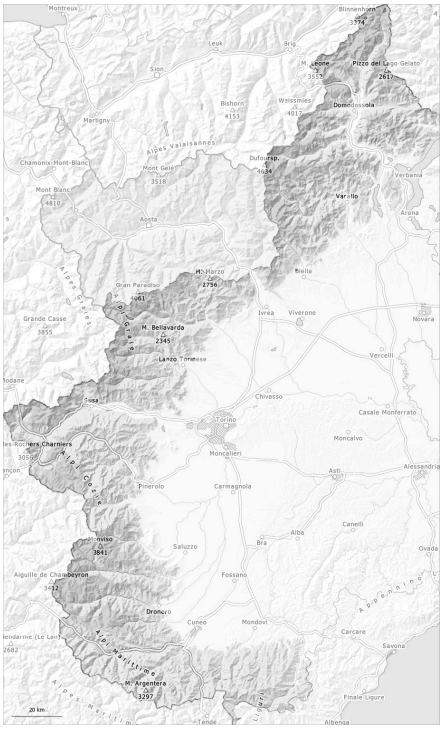

Nachmittag

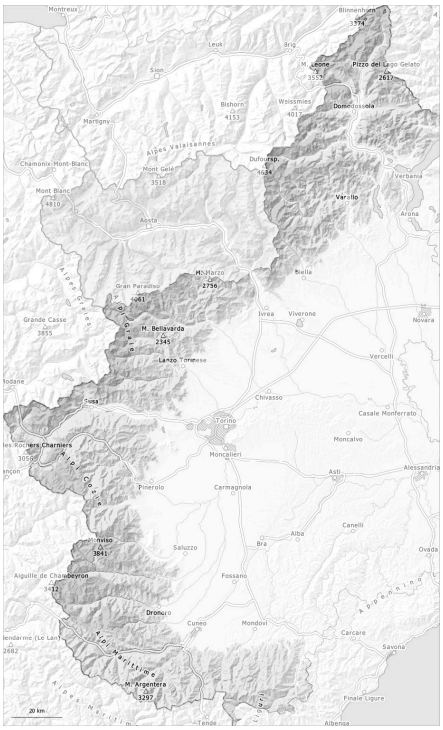

1	2	3	4	5
gering	mäßig	erheblich	groß	sehr groß

Gefahrenstufe 2 - Mäßig

AM:

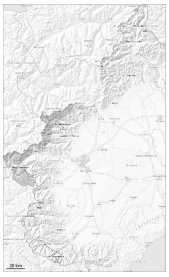

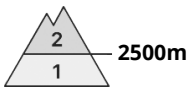

Tendenz: Lawinengefahr bleibt gleich
am Freitag, den 06.03.2026

Altschnee

PM:

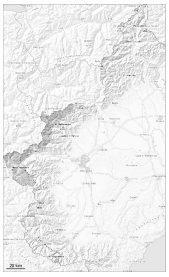

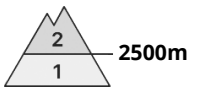

Tendenz: Lawinengefahr bleibt gleich
am Freitag, den 06.03.2026

Altschnee

Nassschnee

Im mittleren Teil der Altschneedecke sind oberhalb von rund 2500 m einzelne Schwachschichten vorhanden.

Schwachschichten im Altschnee können besonders oberhalb von rund 2500 m besonders mit großer Zusatzbelastung ausgelöst werden. Vorsicht vor allem an Übergängen von wenig zu viel Schnee und an sehr steilen Hängen in mittleren und hohen Lagen.
Zudem sind die harten Triebschneeansammlungen v.a. in Kammlagen, Rinnen und Mulden teils noch auslösbar. Vor allem in tiefen und mittleren Lagen und im felsdurchsetzten Steilgelände sind mit der tageszeitlichen Erwärmung und der Sonneneinstrahlung einzelne meist kleine feuchte und nasse Lawinen möglich.

Am Morgen, Auf der harten Schneeoberfläche besteht Absturzgefahr.

Schneedecke

Gefahrenmuster gm.10: frühjahrssituation | gm.1: bodennahe schwachschicht

Montag: Es fielen lokal oberhalb von rund 1600 m 5 cm Schnee.

Vor allem steile Sonnenhänge tiefe und mittlere Lagen: Die Schneeoberfläche ist tragfähig gefroren und weicht später auf als am Vortag.

Besonders steile West-, Nord- und Nordosthänge hohe Lagen und Hochgebirge: In der Altschneedecke sind Schwachschichten vorhanden.

> In Gipfellagen liegen je nach Windeinfluss sehr unterschiedliche Schneehöhen.

Gefahrenstufe 2 - Mäßig

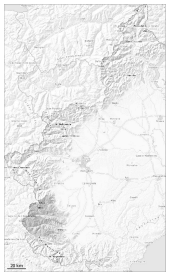

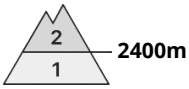

Tendenz: Lawinengefahr bleibt gleich
am Freitag, den 06.03.2026

Altschnee

Die Gefahrenstellen liegen vor allem im Steilgelände in mittleren und hohen Lagen.

Vor allem oberhalb von rund 2400 m: Schwachschichten im Altschnee können stellenweise noch von Wintersportlern ausgelöst werden. Dies vor allem an sehr steilen West-, Nord- und Nordosthängen.
Die spontane Lawinenaktivität nimmt mit der Abkühlung ab.
Am Morgen, Auf der harten Schneeoberfläche besteht Absturzgefahr.

Schneedecke

Gefahrenmuster gm.10: frühjahrssituation | gm.1: bodennahe schwachschicht

Montag: Seit Montag fielen lokal oberhalb von rund 1600 m 5 bis 15 cm Schnee, lokal bis zu 20 cm.

Mittlere und hohe Lagen: In der Schneedecke sind besonders an West-, Nord- und Nordosthängen Schwachschichten vorhanden.

In Gipfellagen liegen je nach Windeinfluss sehr unterschiedliche Schneehöhen. In windgeschützten Lagen in allen Höhenlagen liegt für die Jahreszeit viel Schnee.

Die Schneeoberfläche gefriert tragfähig und weicht später auf als am Vortag.

Gefahrenstufe 2 - Mäßig

AM:

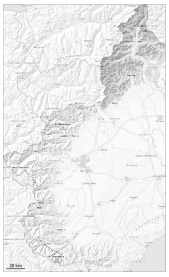

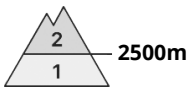

Tendenz: Lawinengefahr bleibt gleich
am Freitag, den 06.03.2026

Altschnee

PM:

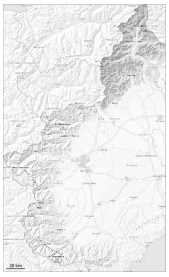

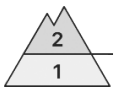

Tendenz: Lawinengefahr bleibt gleich
am Freitag, den 06.03.2026

Altschnee

Nassschnee

Im mittleren Teil der Altschneedecke sind oberhalb von rund 2500 m einzelne Schwachschichten vorhanden.

Schwachschichten im Altschnee können besonders oberhalb von rund 2500 m besonders mit großer Zusatzbelastung ausgelöst werden. Vorsicht vor allem an Übergängen von wenig zu viel Schnee und an sehr steilen Hängen in mittleren und hohen Lagen.
Sonne und Wärme führen im Tagesverlauf vor allem an Sonnenhängen in tiefen und mittleren Lagen teilweise zu einem Festigkeitsverlust innerhalb der Schneedecke.
Am Morgen, Auf der harten Schneeoberfläche besteht Absturzgefahr.

Schneedecke

Gefahrenmuster gm.10: frühjahrssituation | gm.1: bodennahe schwachschicht

Montag: Es fielen lokal oberhalb von rund 1600 m bis zu 10 cm Schnee.

Besonders steile Sonnenhänge tiefe und mittlere Lagen: Die Altschneedecke ist hart, mit einer tragfähigen Schmelzharschkruste an der Oberfläche.
Sonne und Wärme führen im Tagesverlauf vor allem an Sonnenhängen in tiefen und mittleren Lagen zu einer Aufweichung der Schneedecke.
Besonders steile West-, Nord- und Nordosthänge hohe Lagen und Hochgebirge: In der Altschneedecke sind einzelne Schwachschichten vorhanden.

In Gipfellagen liegen je nach Windeinfluss sehr unterschiedliche Schneehöhen.

> In diesen Gebieten liegt für die Jahreszeit wenig Schnee.

Gefahrenstufe 1 - Gering

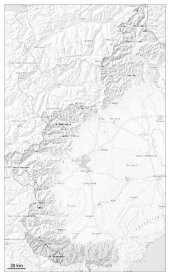

1

Tendenz: Lawinengefahr bleibt gleich
am Freitag, den 06.03.2026

Meist günstige Lawinensituation. Rückgang der Gefahr von feuchten und nassen Lawinen mit der Abkühlung.

Die Schneedecke ist meist gut verfestigt. Die Schneeoberfläche ist tragfähig gefroren und weicht später auf als am Vortag. Die spontane Lawinenaktivität nimmt mit der Abkühlung ab. Am Morgen, Auf der harten Schneeoberfläche besteht Absturzgefahr.

Schneedecke

Gefahrenmuster gm.10: frühjahrssituation gm.2: gleitschnee

V.a. in Gipfellagen liegen je nach Windeinfluss sehr unterschiedliche Schneehöhen.
Die Schneeoberfläche ist tragfähig gefroren und weicht später auf als am Vortag. Dort liegt für die Jahreszeit viel Schnee.

Gefahrenstufe 1 - Gering

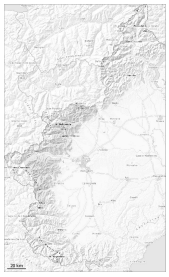

Tendenz: Lawinengefahr bleibt gleich
am Freitag, den 06.03.2026

Altschnee

2300m

Die Schneedecke ist recht stabil. Rückgang der Gefahr von feuchten und nassen Lawinen mit der Abkühlung.

Schwachschichten im Altschnee können in hohen Lagen und im Hochgebirge vereinzelt und meist mit großer Zusatzbelastung ausgelöst werden. Dies an Übergängen von wenig zu viel Schnee und an extrem steilen Hängen in mittleren und hohen Lagen.
Die spontane Lawinenaktivität nimmt mit der Abkühlung ab.
Am Morgen, Auf der harten Schneeoberfläche besteht Absturzgefahr.

Schneedecke

Gefahrenmuster gm.10: frühjahrssituation | gm.1: bodennahe schwachschicht

Montag: Es fielen lokal oberhalb von rund 1600 m bis zu 10 cm Schnee.

Vor allem tiefe und mittlere Lagen: Die Schneeoberfläche ist tragfähig gefroren und weicht später auf als am Vortag.